Bulletin d'estimation du risque d'avalanche
(valable en dehors des pistes balisées et ouvertes)

MASSIF : Chartreuse

Rédigé le vendredi 17 avril 2026 à 15h

Estimation des risques pour le : SAMEDI 18 AVRIL

POURSUITE DE L'HUMIDIFICATION DU MANTEAU : QUELQUES DÉPARTS POSSIBLES, PARFOIS AU TERRAIN.

2

1 → 2

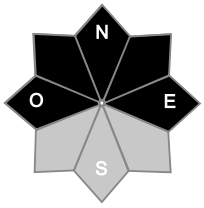

neige humide

Indice de risque faible évoluant en limité.

Départs spontanés : Quelques avalanches humides de taille 1 à 2, possibles surtout l'après-midi.

Déclenchements provoqués : Peu probables ou sous les skis en neige très humide l'après-midi.

Indices de risque : 5 très fort - 4 fort - 3 marqué - 2 limité - 1 faible -- En noir : les pentes les plus dangereuses

Stabilité du manteau neigeux

Situation avalancheuse typique : neige humide — avalanches de fond

Départs spontanés : Après un bon regel, le risque est faible en matinée puis augmente au fil des heures avec quelques avalanches de neige humide possibles en tous versants. Généralement de taille 1 à 2 (petite à moyenne), on ne peut cependant exclure une rare taille 3 (grande) dans un versant d'un large Nord. Par ailleurs, dans certaines pentes herbeuses / secteurs de reptation, une avalanche de glissement n'est pas exclue. Enfin vers les hautes crêtes, un effondrement spontané de corniche n'est pas exclu. A noter que si les faces d'un large Sud sont également très humides, elles sont en neige plus dense/transformée, et le risque d'avalanche volumineuse y est moindre.

Déclenchements provoqués : Le principal risque pour le pratiquant est de faire couler la neige humide sous les skis, dans une pente raide où la neige est humidifiée jusqu'en profondeur. Ce risque est plutot présent l'après-midi.

Qualité de la neige

Qualification de l'enneigement : L'enneigement s'est fortement réduit depuis une dizaine de jours mais reste assez important en faces peu ensoleillées et en combe d'altitude....

Limites skiables : Vers 1500 à 1800/2200m suivant l'exposition, la raideur de la pente...

Qualité de la neige samedi : Bon regel attendu. Neige dure et surfaces glacées en matinée puis devenant humide au fil des heures jusqu'en profondeur, au soleil. En Sud, neige de printemps déjà très densifiée.
Neige très humide à "soupe" selon le versant/l'altitude.

Aperçu météo pour le samedi 18 avril

	nuit	matin	après-midi	soir
Pluie-Neige				
Iso 0 °C	3 200 m	3 300 m	3 200 m	3 200 m
Vent 1500 m	10 km/h	10 km/h	5 km/h	0 km/h
Vent 2000 m	5 km/h	10 km/h	5 km/h	5 km/h

Encore une belle journée bien ensoleillée et douce. Rares passages nuageux d'altitude.

Épaisseur de neige hors-piste

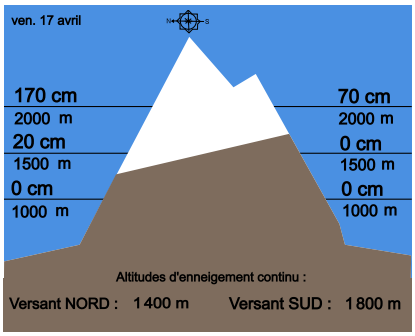

Précipitations à 1800 m

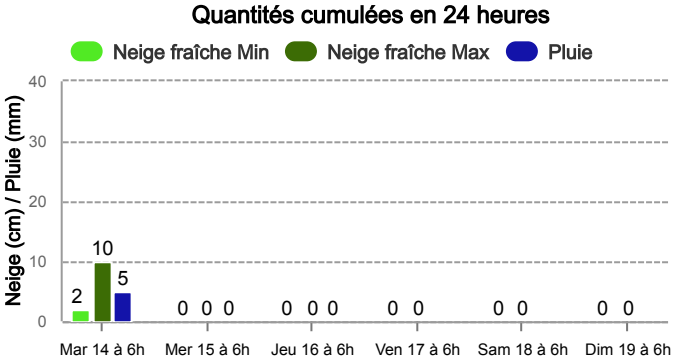

Tendance du dimanche 19 avril

2

Indice de risque limité

Risque stable avec l'humidification progressive du manteau.

Pour consulter la vigilance en cours, veuillez vous rendre sur le site https://vigilance.meteofrance.fr/fr

Météo-France - 73 avenue de Paris, 94165 Saint-Mandé cedex - Contact : contact@meteo.fr

Rédigé par Météo-France avec la contribution des observateurs du réseau nivo-météorologiques. Partenariat : ANMSM (Maires de Stations de Montagne), DSF (Domaines Skiables de France), ADSP (Directeurs de Pistes et de la Sécurité des Stations de Sports d'Hiver) et autres acteurs de la montagne.

Bulletin neige & avalanches par téléphone au 0 892 68 10 20 Service 0,35 € / min + prix appel

RÉPUBLIQUE FRANÇAISE
Liberté Égalité Fraternité

METEO FRANCE
À VOS CÔTÉS, DANS UN CLIMAT QUI CHANGE

Bulletin d'estimation du risque d'avalanche

(valable en dehors des pistes balisées et ouvertes)

MASSIF : Chartreuse

Rédigé le vendredi 17 avril 2026 à 15h

Conditions nivo-météo des 7 derniers jours

	sam. 11/04				dim. 12/04				lun. 13/04				mar. 14/04				mer. 15/04				jeu. 16/04				ven. 17/04			
	03h	09h	15h	21h	03h	09h	15h	21h	03h	09h	15h	21h	03h	09h	15h	21h	03h	09h	15h	21h	03h	09h	15h	21h	03h	09h	15h	21h
Météo																												
Vent (km/h)	25	25	20	20	30	20	20	25	20	15	20	30	25	25	30	20	25	10	15	10	15	15	10	5	10	10	5	5
à 2000m																												
Vent (km/h)	10	20	15	15	20	10	15	10	10	10	15	20	20	20	25	15	15	5	10	5	5	5	5	15	10	5	5	5
à 1500m																												

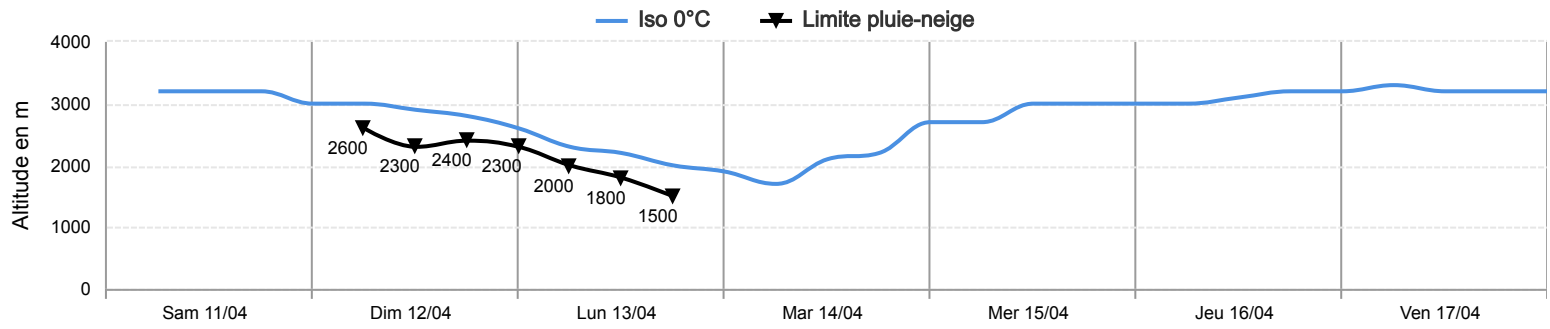

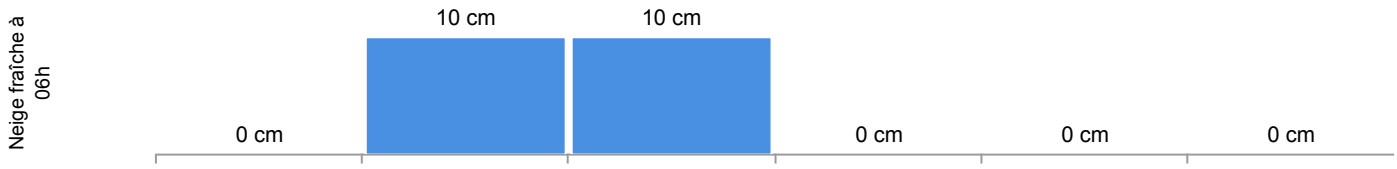

Risque d'avalanche	sam. 11/04	dim. 12/04	lun. 13/04	mar. 14/04	mer. 15/04	jeu. 16/04	ven. 17/04
	2	2	2	2	2	2	2

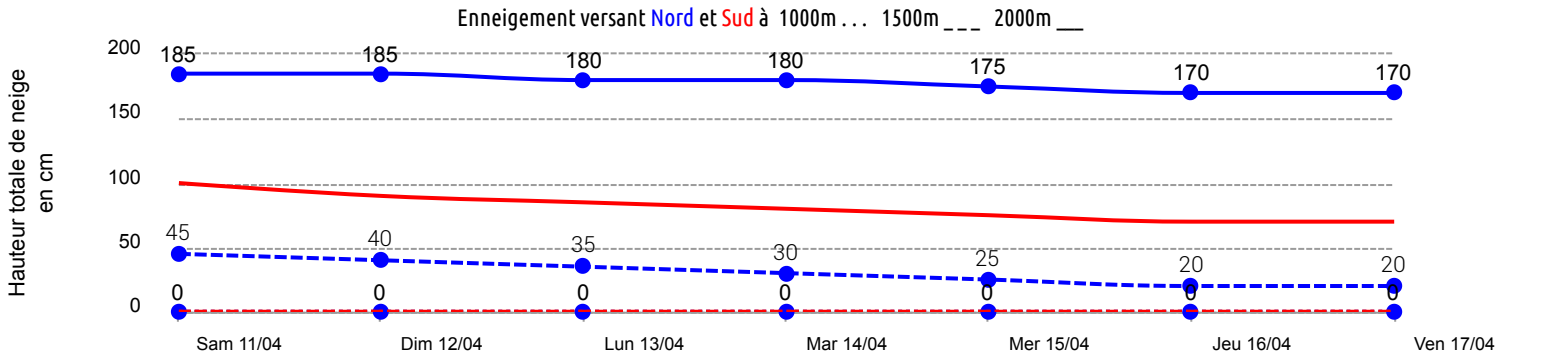

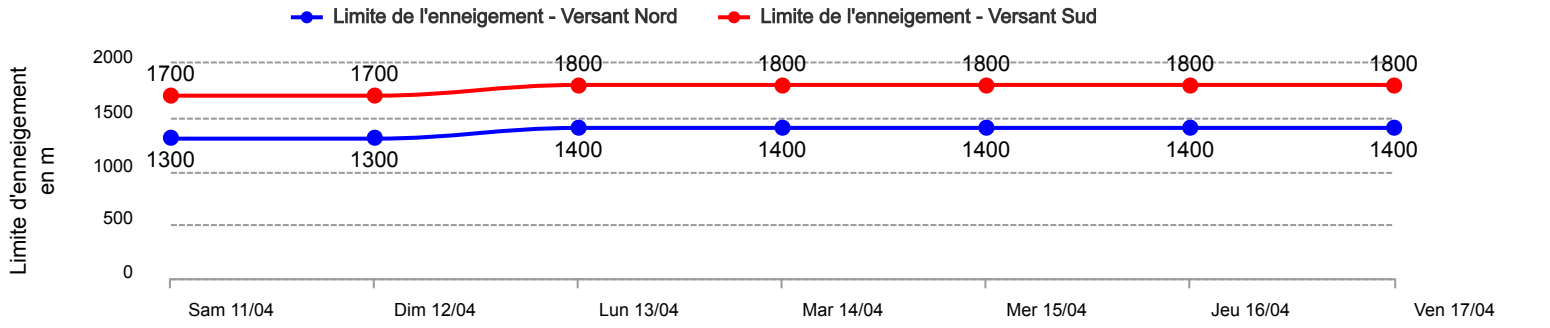

Pour consulter la vigilance en cours, veuillez vous rendre sur le site https://vigilance.meteofrance.fr/fr

Météo-France - 73 avenue de Paris, 94165 Saint-Mandé cedex - Contact : contact@meteo.fr

Rédigé par Météo-France avec la contribution des observateurs du réseau nivo-météorologiques. Partenariat : ANMSM (Maires de Stations de Montagne), DSF (Domaines Skiables de France), ADSP (Directeurs de Pistes et de la Sécurité des Stations de Sports d'Hiver) et autres acteurs de la montagne.

Bulletin neige & avalanches par téléphone au
0 892 68 10 20 Service 0,35 € / min + prix appel