Bulletin d'estimation du risque d'avalanche

(valable en dehors des pistes balisées et ouvertes)

MASSIF : Haut-Var Haut-Verdon

Rédigé le vendredi 17 avril 2026 à 16h

Estimation des risques pour le : SAMEDI 18 AVRIL

ACTIVITÉ NATURELLE PRINTANIÈRE

2

1 → 2

N O E S

Indice de risque faible évoluant en limité.

Départs spontanés : quelques avalanches de neige humide, généralement de taille limitée - une avalanche volumineuse possible en ubacs d'altitude.

Déclenchements provoqués : en neige humide sous les skis.

Indices de risque : 5 très fort - 4 fort - 3 marqué - 2 limité - 1 faible -- En noir : les pentes les plus dangereuses

Stabilité du manteau neigeux

Situation avalancheuse typique : neige humide

Départs spontanés : l'activité en neige humide est à nouveau en hausse en cours de journée. Avalanches superficielles de petite taille en général (taille 1), mais quelques départs linéaires plus volumineux sont possibles dans les pentes nord-ouest à nord-est au-dessus de 2200/2300 m environ, emportant la totalité du manteau neigeux en place. Avalanches moyennes, voire ponctuellement grandes (taille 2 à 3).

Déclenchements provoqués : un skieur coupant une pente raide trop tardivement peut initier un départ de neige humide sous ses skis. À noter également que dans les ubacs d'altitude, une première avalanche superficielle de neige humide déclenchée par un skieur peut dans de rares cas provoquer un second départ linéaire plus volumineux.

Qualité de la neige

Enneigement désormais déficitaire pour la saison, avec une fonte qui s'accélère. Absence de précipitations significatives depuis environ 1 mois et grande douceur en place depuis début avril.
Hauteurs de neige observées : vers 2000 m, 105 cm dans le vallon de Valdemars dans le Haut-Verdon, 35 cm à la Sanguinière dans le Haut-Var.

Enneigement skiable généralement à partir de 1800 m en ubacs sur terrain favorable (routes forestières, terrains herbeux) et 2300 m en adrets peu pentus.

État de la neige en surface : manteau neigeux printanier, croûté le matin, puis s'humidifiant rapidement au soleil en cours de journée dans toutes les expositions.

Aperçu météo pour le samedi 18 avril

Temps printanier : ensoleillé le matin, puis cumulus l'après-midi donnant quelques averses isolées. Températures atteignant 13 °C à 2000 m l'après-midi.

	nuit	matin	après-midi	soir
Pluie-Neige	2700 m			
Iso 0 °C	3200 m	3200 m	3200 m	3300 m
Vent 2000 m	↓ 10 km/h	↑ 10 km/h	↗ 20 km/h	↘ 10 km/h
Vent 3000 m	→ 15 km/h	↗ 15 km/h	↘ 20 km/h	→ 20 km/h

Épaisseur de neige hors-piste

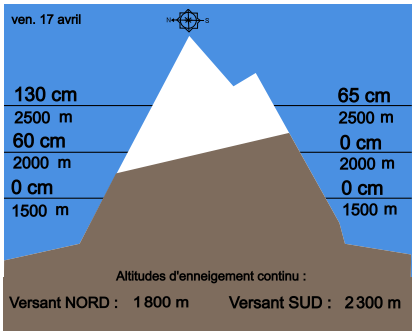

Précipitations à 1800 m

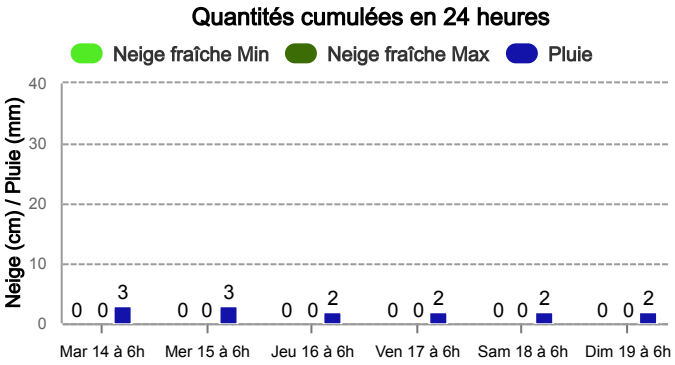

Tendance du dimanche 19 avril

2

Indice de risque limité

La situation nivologique n'évolue pas et reste pilotée par l'activité en neige humide au cours de la journée. Rares départs linéaires volumineux dans les ubacs d'altitude.

Pour consulter la vigilance en cours, veuillez vous rendre sur le site https://vigilance.meteofrance.fr/fr

Météo-France - 73 avenue de Paris, 94165 Saint-Mandé cedex - Contact : contact@meteo.fr

Rédigé par Météo-France avec la contribution des observateurs du réseau nivo-météorologiques. Partenariat : ANMSM (Maires de Stations de Montagne), DSF (Domaines Skiables de France), ADSP (Directeurs de Pistes et de la Sécurité des Stations de Sports d'Hiver) et autres acteurs de la montagne.

Bulletin neige & avalanches par téléphone au 0 892 68 10 20 Service 0,35 € / min + prix appel

RÉPUBLIQUE FRANÇAISE
Liberté Égalité Fraternité

METEO FRANCE
À VOS CÔTÉS, DANS UN CLIMAT QUI CHANGE

Bulletin d'estimation du risque d'avalanche

(valable en dehors des pistes balisées et ouvertes)

MASSIF : Haut-Var Haut-Verdon

Rédigé le vendredi 17 avril 2026 à 16h

Conditions nivo-météo des 7 derniers jours

	sam. 11/04				dim. 12/04				lun. 13/04				mar. 14/04				mer. 15/04				jeu. 16/04				ven. 17/04			
	03h	09h	15h	21h	03h	09h	15h	21h	03h	09h	15h	21h	03h	09h	15h	21h	03h	09h	15h	21h	03h	09h	15h	21h	03h	09h	15h	21h
Météo																												
Vent (km/h)	25	25	30	15	15	20	25	25	25	30	35	40	40	35	35	25	35	20	15	10	15	10	15	10	10	10	15	15
à 3000m																												
Vent (km/h)	20	15	20	10	10	15	25	35	35	25	25	25	25	30	25	20	25	15	20	10	10	10	20	5	5	10	20	10
à 2000m																												

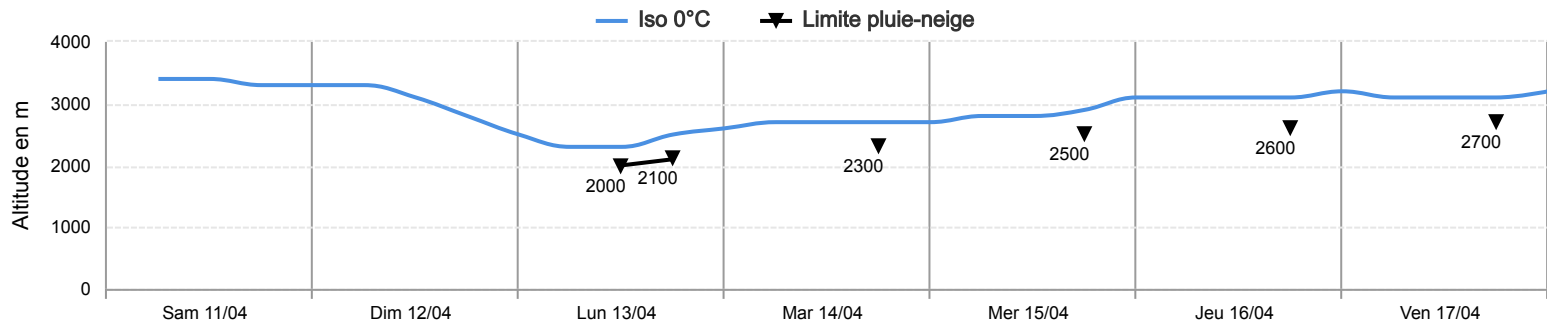

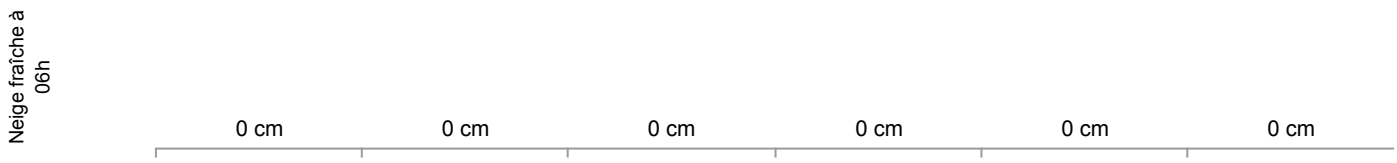

Risque d'avalanche	sam. 11/04	dim. 12/04	lun. 13/04	mar. 14/04	mer. 15/04	jeu. 16/04	ven. 17/04
	3	2	2	2	2	2	2

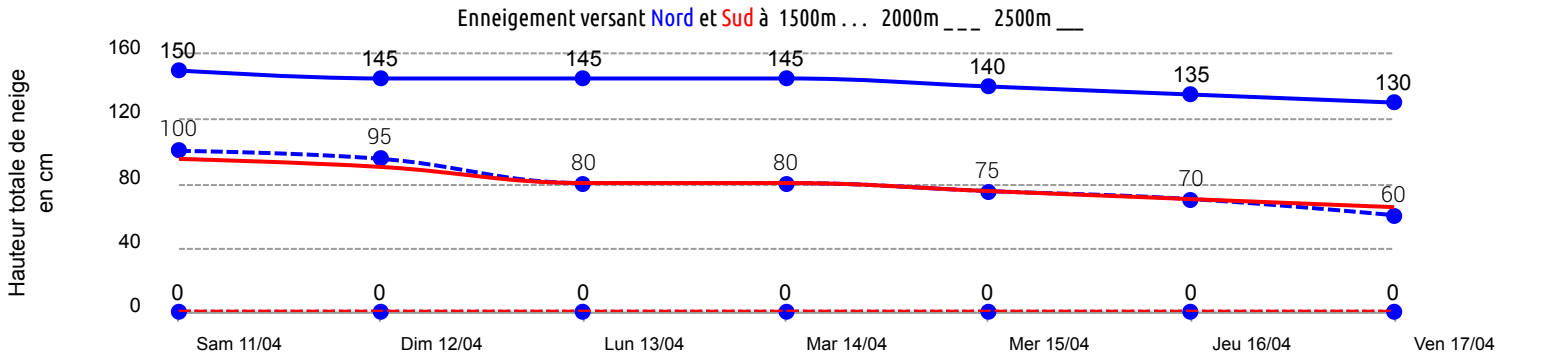

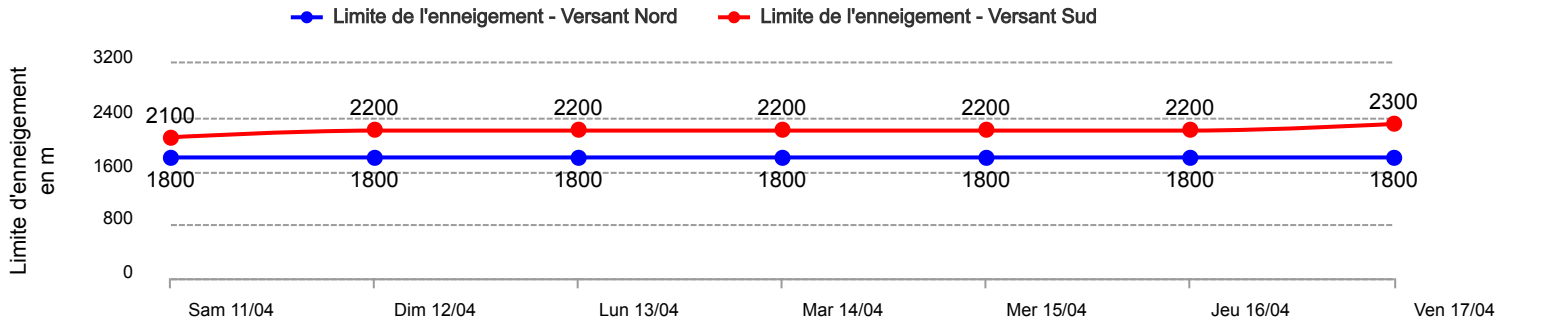

Pour consulter la vigilance en cours, veuillez vous rendre sur le site https://vigilance.meteofrance.fr/fr

Météo-France - 73 avenue de Paris, 94165 Saint-Mandé cedex - Contact : contact@meteo.fr

Rédigé par Météo-France avec la contribution des observateurs du réseau nivo-météorologiques. Partenariat : ANMSM (Maires de Stations de Montagne), DSF (Domaines Skiables de France), ADSP (Directeurs de Pistes et de la Sécurité des Stations de Sports d'Hiver) et autres acteurs de la montagne.

Bulletin neige & avalanches par téléphone au
0 892 68 10 20
Service 0,35 € / min + prix appel