# Bulletin d'estimation du risque d'avalanche
## (valable en dehors des pistes balisées et ouvertes)

# MASSIF : Mont-Blanc

Rédigé le vendredi 17 avril 2026 à 16h

## Estimation des risques pour le : SAMEDI 18 AVRIL

**POURSUITE DE L'HUMIDIFICATION DU MANTEAU NEIGEUX**

2

1 → 2

N O E S

Indice de risque faible évoluant en limité.

**Départs spontanés :** Avalanches de neige humide

**Déclenchements provoqués :** Avalanches de neige humide

Indices de risque : 5 très fort - 4 fort - 3 marqué - 2 limité - 1 faible -- En noir : les pentes les plus dangereuses

## Stabilité du manteau neigeux

**Situation avalancheuse typique :** neige humide — avalanches de fond

Départs spontanés :

* **avalanches de neige humide de plus en plus nombreuses au fil de la course du soleil, majoritairement sous 4000 m en sud et 2700 m en nord**. Taille 1 à 2 (petites à moyennes). Au-dessus de 2000 m, de petits départs ponctuels peuvent déclencher, en cascade, une plaque de plus grandes ampleurs (taille 3, grande).
*Observables* : enfoncement piéton important, boulettes, escargots
* quelques plaques de fond dans les zones herbeuses ou dalles rocheuses, à toute heure du jour ou de la nuit, en dessous de 2700 m. Taille 2.

Déclenchements provoqués :

* Avalanches de neige humides sous 4000 m en sud et 2700 m en nord, dans les versants raides et chauffés par le soleil, facilement déclenchable par un skieur. Départ ponctuel pouvant parfois déclencher, en cascade, une petite plaque. Taille 1, rarement 2.

## Qualité de la neige

Enneigement :
Pour la saison, l'enneigement est correct, au-dessus de 3000 m, en dessous il est légèrement déficitaire.
On peut chausser les skis au-dessus de 1800 m en sud et 1500 m en nord.

Qualité de la neige ce samedi matin :
* au-dessus de 3000 m en nord et 4000 m en sud, 10/30 cm de neige récente encore froide, travaillée par le vent au-dessus de 4000 m, reposant sur un fond dur. Les crêtes sommitales sont souvent décapées ou glacées.
* en dessous de ces altitudes, neige de printemps avec un bon regel nocturne. Neige portante à skis et souvent à pied en début de journée.

## Aperçu météo pour le samedi 18 avril

| nuit | matin | après-midi | soir |
|---|---|---|---|

Beau temps jusqu'en milieu de journée. Voile nuageux parfois épais dans l'après-midi. Températures à 2000 m : 4/11°C.

| Pluie-Neige | | | | |
|---|---|---|---|---|
| Iso 0 °C | 3 100 m | 3 300 m | 3 200 m | 3 200 m |
| Vent 2000 m | 5 km/h | 5 km/h | 5 km/h | 10 km/h |
| Vent 4000 m | 40 km/h | 40 km/h | 40 km/h | 40 km/h |

## Épaisseur de neige hors-piste

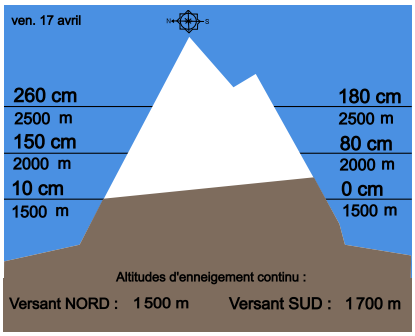


## Précipitations à 1800 m

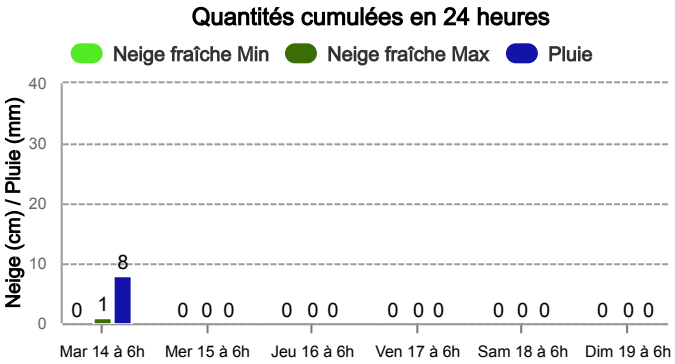


## Tendance du dimanche 19 avril

2

**Indice de risque limité**

Quelques petites averses dans l'après-midi, isotherme 0°C vers 2700 m.
Pas d'évolution significative du manteau neigeux.

Pour consulter la vigilance en cours, veuillez vous rendre sur le site https://vigilance.meteofrance.fr/fr

Météo-France - 73 avenue de Paris, 94165 Saint-Mandé cedex - Contact : contact@meteo.fr

Rédigé par Météo-France avec la contribution des observateurs du réseau nivo-météorologiques. Partenariat : ANMSM (Maires de Stations de Montagne), DSF (Domaines Skiables de France), ADSP (Directeurs de Pistes et de la Sécurité des Stations de Sports d'Hiver) et autres acteurs de la montagne.

Bulletin neige & avalanches par téléphone au 0 892 68 10 20 Service 0,35 € / min + prix appel

RÉPUBLIQUE FRANÇAISE
*Liberté Égalité Fraternité*

METEO FRANCE
À VOS CÔTÉS, DANS UN CLIMAT QUI CHANGE

# Bulletin d'estimation du risque d'avalanche

## (valable en dehors des pistes balisées et ouvertes)

# MASSIF : Mont-Blanc

Rédigé le vendredi 17 avril 2026 à 16h

## Conditions nivo-météo des 7 derniers jours

| | sam. 11/04 | | | | dim. 12/04 | | | | lun. 13/04 | | | | mar. 14/04 | | | | mer. 15/04 | | | | jeu. 16/04 | | | | ven. 17/04 | | | |
|---|---|---|---|---|---|---|---|---|---|---|---|---|---|---|---|---|---|---|---|---|---|---|---|---|---|---|---|---|
| | 03h | 09h | 15h | 21h | 03h | 09h | 15h | 21h | 03h | 09h | 15h | 21h | 03h | 09h | 15h | 21h | 03h | 09h | 15h | 21h | 03h | 09h | 15h | 21h | 03h | 09h | 15h | 21h |
| Météo | | | | | | | | | | | | | | | | | | | | | | | | | | | | |
| Vent (km/h) | 60 | 60 | 50 | 60 | 60 | 55 | 60 | 50 | 45 | 40 | 30 | 30 | 25 | 15 | 20 | 20 | 10 | 20 | 10 | 20 | 30 | 20 | 20 | 20 | 20 | 20 | 20 | 20 |
| à 4000m | | | | | | | | | | | | | | | | | | | | | | | | | | | | |
| Vent (km/h) | 20 | 20 | 25 | 20 | 20 | 15 | 20 | 15 | 10 | 5 | 5 | 10 | 20 | 25 | 15 | 10 | 15 | 5 | 5 | 5 | 5 | 5 | 5 | 10 | 10 | 10 | 10 | 10 |
| à 2000m | | | | | | | | | | | | | | | | | | | | | | | | | | | | |

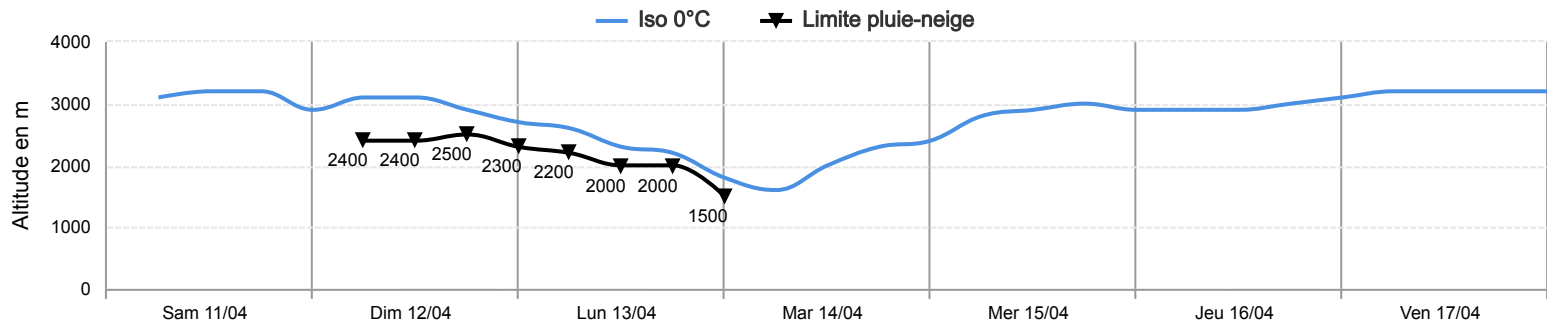


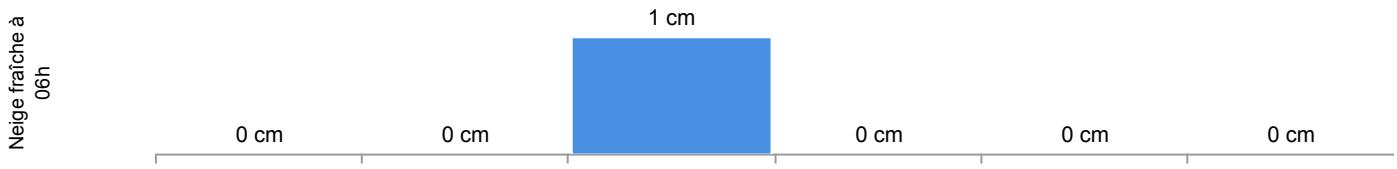


| Risque d'avalanche | sam. 11/04 | dim. 12/04 | lun. 13/04 | mar. 14/04 | mer. 15/04 | jeu. 16/04 | ven. 17/04 |
|---|---|---|---|---|---|---|---|
| | 3 | 2 | 2 | 2 | 2 | 2 | 2 |

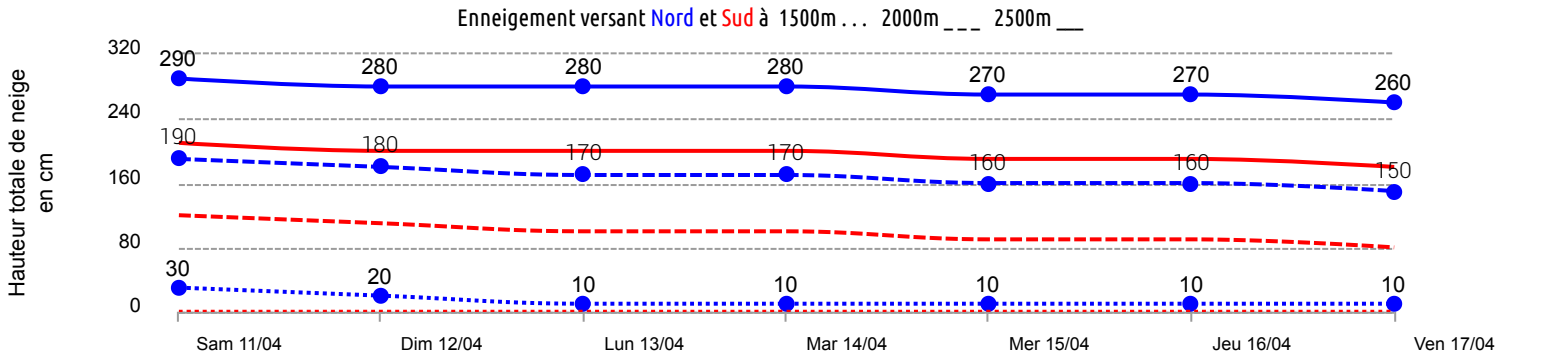


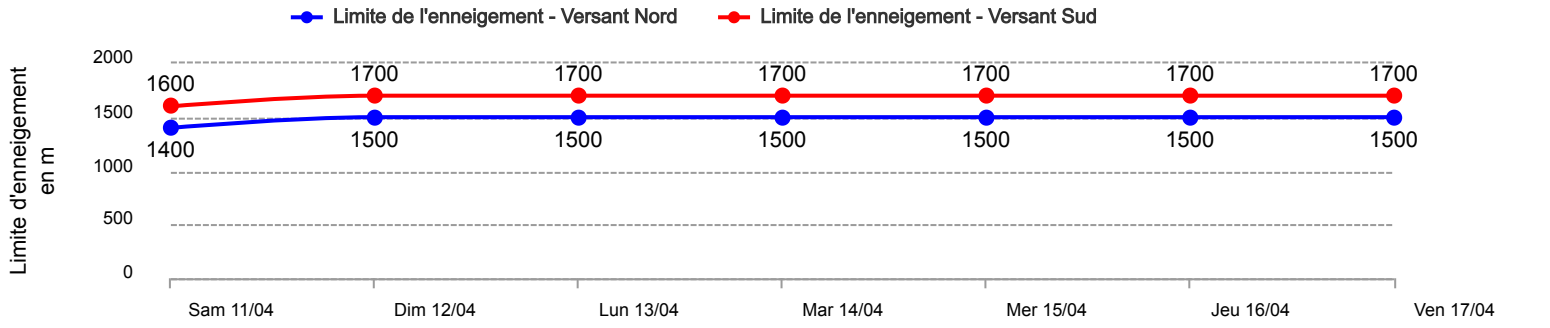


Pour consulter la vigilance en cours, veuillez vous rendre sur le site https://vigilance.meteofrance.fr/fr


Météo-France - 73 avenue de Paris, 94165 Saint-Mandé cedex - Contact : contact@meteo.fr



Rédigé par Météo-France avec la contribution des observateurs du réseau nivo-météorologiques. Partenariat : ANMSM (Maires de Stations de Montagne), DSF (Domaines Skiables de France), ADSP (Directeurs de Pistes et de la Sécurité des Stations de Sports d'Hiver) et autres acteurs de la montagne.



Bulletin neige & avalanches par téléphone au
0 892 68 10 20 Service 0,35 € / min + prix appel