Bulletin d'estimation du risque d'avalanche
(valable en dehors des pistes balisées et ouvertes)

MASSIF : Queyras

Rédigé le vendredi 17 avril 2026 à 16h

Estimation des risques pour le : SAMEDI 18 AVRIL

MANTEAU NEIGEUX PRINTANIER, RARES DÉPARTS VOLUMINEUX EN UBACS D'ALTITUDE

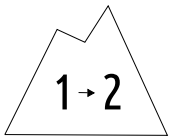

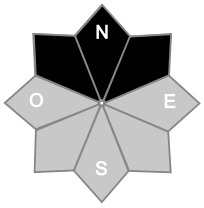

Indice de risque faible évoluant en limité.

Départs spontanés : en neige humide en versants nord d'altitude

Déclenchements provoqués : en neige humide en versants nord d'altitude

Indices de risque : 5 très fort - 4 fort - 3 marqué - 2 limité - 1 faible -- En noir : les pentes les plus dangereuses

Stabilité du manteau neigeux

Situation avalancheuse typique : neige humide

Déclenchements provoqués : instabilités localisées en versants nord-ouest, nord et nord-est d'altitude, à partir de 2400 m environ, dans les pentes raides fortement humidifiées au soleil. Avalanches de neige humide pouvant être déclenchées par un seul skieur, généralement ponctuelles et de petite taille (taille 1), plus rarement moyenne (taille 2) et exceptionnellement grande (taille 3) avec départ linéaire et jusqu'au sol.
L'humidification du manteau neigeux se poursuit et peut atteindre localement les couches fragiles encore présentes à la base du manteau neigeux.

Départs spontanés : peu probables au petit matin après un regel nocturne correct, puis reprise rapide de l'activité en neige humide au fil de la course du soleil. Avalanches de petite taille (taille 1), plus rarement moyenne (taille 2) et exceptionnellement grande (taille 3) avec départ linéaire et jusqu'au sol.

Qualité de la neige

Enneigement très déficitaire pour une mi-avril, notamment en adrets, souvent secs jusqu'à plus de 2500 m.
Hauteurs de neige observées : 105 cm en versant nord du col Izoard à 2300 m et au-dessus de Saint-Véran à 2700 m, 61 cm à la Nivôse du Col Agnel à 2630 m.

Limite d'enneigement skiable : au plus bas à 1800 m en ubacs bien protégés ou sur pistes forestières vers le Briançonnais

État de la neige de surface : neige en cycle printanier. Après un regel nocturne correct, reprise rapide de l'humidification au soleil.

Aperçu météo pour le samedi 18 avril

	nuit	matin	après-midi	soir

Temps chaud et peu venté, passages nuageux parfois denses l'après-midi.

Pluie-Neige				
Iso 0 °C	3200 m	3200 m	3200 m	3200 m
Vent 2000 m	↓ 5 km/h	↓ 10 km/h	→ 15 km/h	→ 10 km/h
Vent 3000 m	↘ 10 km/h	↘ 15 km/h	↘ 10 km/h	→ 5 km/h

Épaisseur de neige hors-piste

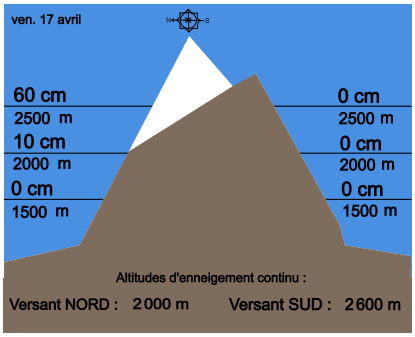

Précipitations à 1800 m

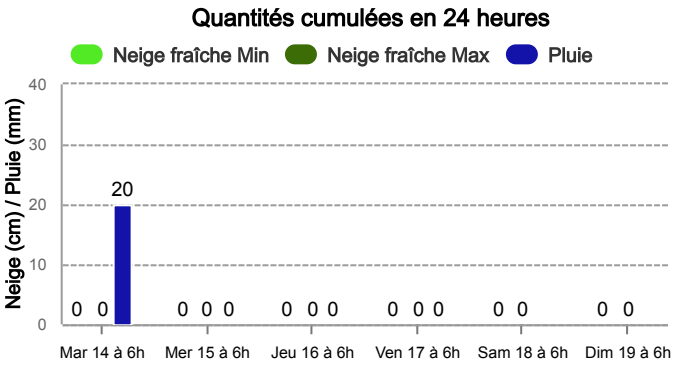

Tendance du dimanche 19 avril

Indice de risque limité

Peu d'évolution. Temps encore chaud, risque limité en neige humide.

Pour consulter la vigilance en cours, veuillez vous rendre sur le site https://vigilance.meteofrance.fr/fr

Météo-France - 73 avenue de Paris, 94165 Saint-Mandé cedex - Contact : contact@meteo.fr

Rédigé par Météo-France avec la contribution des observateurs du réseau nivo-météorologiques. Partenariat : ANMSM (Maires de Stations de Montagne), DSF (Domaines Skiables de France), ADSP (Directeurs de Pistes et de la Sécurité des Stations de Sports d'Hiver) et autres acteurs de la montagne.

Bulletin neige & avalanches par téléphone au
0 892 68 10 20 Service 0,35 € / min + prix appel

RÉPUBLIQUE FRANÇAISE
Liberté Égalité Fraternité

METEO FRANCE
À VOS CÔTÉS, DANS UN CLIMAT QUI CHANGE

Bulletin d'estimation du risque d'avalanche

(valable en dehors des pistes balisées et ouvertes)

MASSIF : Queyras

Rédigé le vendredi 17 avril 2026 à 16h

Conditions nivo-météo des 7 derniers jours

	sam. 11/04				dim. 12/04				lun. 13/04				mar. 14/04				mer. 15/04				jeu. 16/04				ven. 17/04			
	03h	09h	15h	21h	03h	09h	15h	21h	03h	09h	15h	21h	03h	09h	15h	21h	03h	09h	15h	21h	03h	09h	15h	21h	03h	09h	15h	21h
Météo																												
Vent (km/h)	25	25	25	15	20	25	30	30	25	40	30	30	35	30	30	30	25	20	10	5	10	10	15	5	5	5	5	5
à 3000m																												
Vent (km/h)	10	10	25	10	10	15	30	20	25	20	25	15	15	20	25	20	15	15	15	5	10	10	15	5	5	5	5	5
à 2000m																												

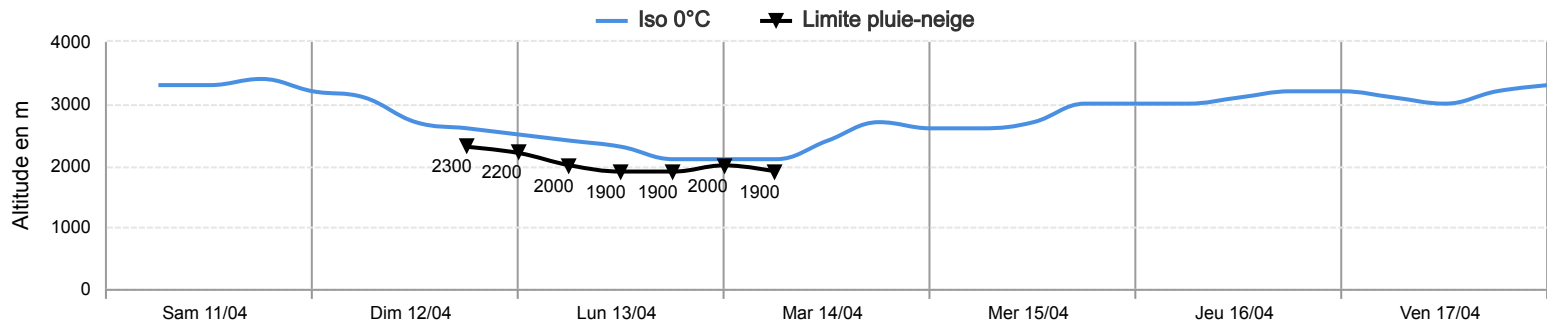

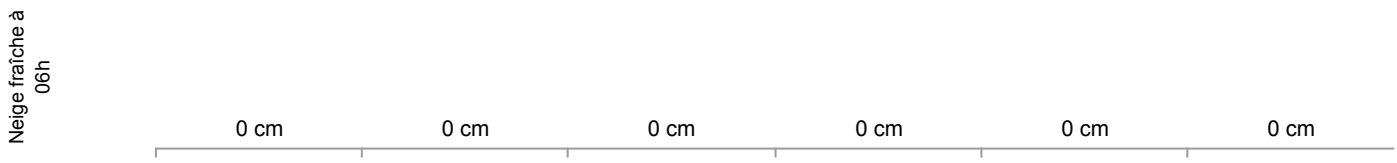

Risque d'avalanche	sam. 11/04	dim. 12/04	lun. 13/04	mar. 14/04	mer. 15/04	jeu. 16/04	ven. 17/04
	3	2	3	3	2	2	2

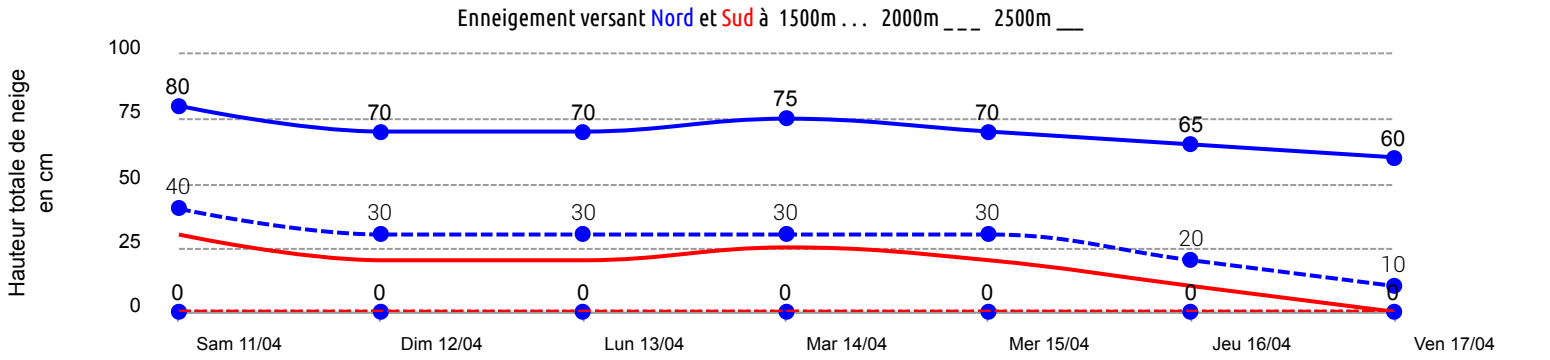

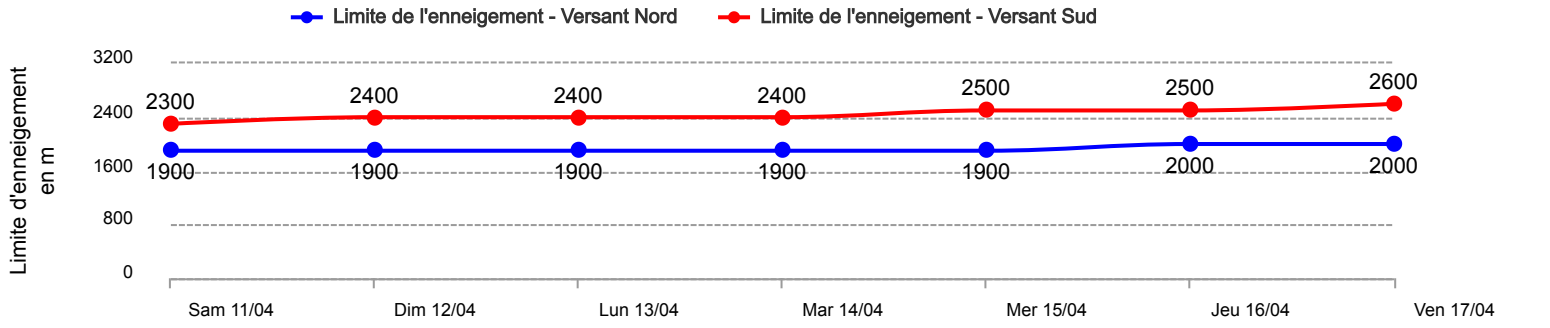

Pour consulter la vigilance en cours, veuillez vous rendre sur le site https://vigilance.meteofrance.fr/fr

Météo-France - 73 avenue de Paris, 94165 Saint-Mandé cedex - Contact : contact@meteo.fr

Rédigé par Météo-France avec la contribution des observateurs du réseau nivo-météorologiques. Partenariat : ANMSM (Maires de Stations de Montagne), DSF (Domaines Skiables de France), ADSP (Directeurs de Pistes et de la Sécurité des Stations de Sports d'Hiver) et autres acteurs de la montagne.

Bulletin neige & avalanches par téléphone au
0 892 68 10 20 Service 0,35 € / min + prix appel