Bulletin d'estimation du risque d'avalanche

(valable en dehors des pistes balisées et ouvertes)

MASSIF : Thabor

Rédigé le vendredi 17 avril 2026 à 16h

Estimation des risques pour le : SAMEDI 18 AVRIL

MANTEAU NEIGEUX PRINTANIER, RARES DÉPARTS VOLUMINEUX EN UBACS D'ALTITUDE

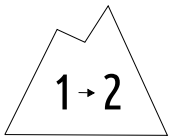

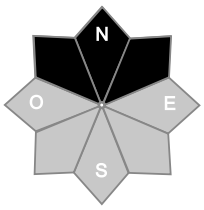

Indice de risque faible évoluant en limité.

Départs spontanés : en neige humide en versants nord d'altitude

Déclenchements provoqués : en neige humide en versants nord d'altitude

Indices de risque : 5 très fort - 4 fort - 3 marqué - 2 limité - 1 faible -- En noir : les pentes les plus dangereuses

Stabilité du manteau neigeux

Situation avalancheuse typique : neige humide

Déclenchements provoqués : instabilités localisées en versants nord-ouest, nord et nord-est d'altitude, à partir de 2400 m environ, dans les pentes raides fortement humidifiées au soleil. Avalanches de neige humide pouvant être déclenchées par un seul skieur, généralement ponctuelles et de petite taille (taille 1), plus rarement moyenne (taille 2) et exceptionnellement grande (taille 3) avec départ linéaire et jusqu'au sol.
L'humidification du manteau neigeux se poursuit et peut atteindre localement les couches fragiles encore présentes à la base du manteau neigeux.

Départs spontanés : peu probables au petit matin après un regel nocturne correct, puis reprise rapide de l'activité en neige humide au fil de la course du soleil. Avalanches généralement ponctuelles et de petite taille (taille 1), plus rarement moyenne (taille 2) et exceptionnellement grande (taille 3) avec départ linéaire et jusqu'au sol.

Qualité de la neige

Enneigement déficitaire sur le massif, particulièrement en adrets.
Hauteurs de neige observées vers 2500 m : 128 cm dans le vallon du Chardonnet, 91 cm aux Rochilles, 42 cm dans le vallon de Roche Noire vers le Galibier.

Limite d'enneigement skiable : vers 1700/1800 m en ubacs favorables (terrains herbeux, pistes forestières), 2200/2400 m en adrets pas trop raides.

État de la neige de surface : neige en cycle printanier. Après un regel nocturne correct, reprise rapide de l'humidification au soleil.

Aperçu météo pour le samedi 18 avril

	nuit	matin	après-midi	soir
	Temps chaud et peu venté, passages nuageux parfois denses l'après-midi.			
Pluie-Neige				
Iso 0 °C	3 200 m	3 300 m	3 300 m	3 200 m
Vent 2000 m	↘ 5 km/h	↘ 5 km/h	↘ 10 km/h	↘ 10 km/h
Vent 3000 m	↓ 15 km/h	↘ 15 km/h	↘ 15 km/h	↘ 15 km/h

Épaisseur de neige hors-piste

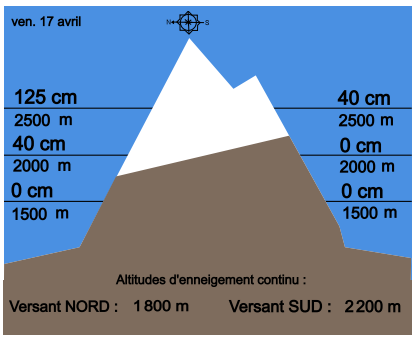

Précipitations à 1800 m

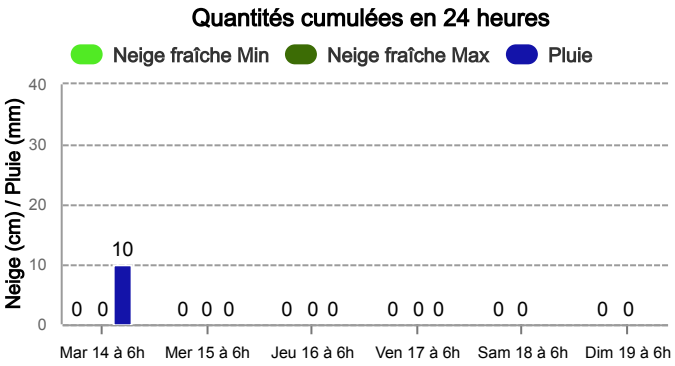

Tendance du dimanche 19 avril

Indice de risque limité

Peu d'évolution. Temps encore chaud, risque limité en neige humide.

Pour consulter la vigilance en cours, veuillez vous rendre sur le site https://vigilance.meteofrance.fr/fr

Météo-France - 73 avenue de Paris, 94165 Saint-Mandé cedex - Contact : contact@meteo.fr

Rédigé par Météo-France avec la contribution des observateurs du réseau nivo-météorologiques. Partenariat : ANMSM (Maires de Stations de Montagne), DSF (Domaines Skiables de France), ADSP (Directeurs de Pistes et de la Sécurité des Stations de Sports d'Hiver) et autres acteurs de la montagne.

Bulletin neige & avalanches par téléphone au

0 892 68 10 20 Service 0,35 € / min + prix appel

Bulletin d'estimation du risque d'avalanche

(valable en dehors des pistes balisées et ouvertes)

MASSIF : Thabor

Rédigé le vendredi 17 avril 2026 à 16h

Conditions nivo-météo des 7 derniers jours

	sam. 11/04				dim. 12/04				lun. 13/04				mar. 14/04				mer. 15/04				jeu. 16/04				ven. 17/04			
	03h	09h	15h	21h	03h	09h	15h	21h	03h	09h	15h	21h	03h	09h	15h	21h	03h	09h	15h	21h	03h	09h	15h	21h	03h	09h	15h	21h
Météo																												
Vent (km/h)	20	15	15	20	25	25	30	40	35	30	25	20	15	15	15	15	15	15	15	15	15	15	10	5	5	5	5	10
à 3000m																												
Vent (km/h)	10	10	15	10	15	25	15	15	15	15	20	20	15	15	15	10	10	15	15	10	10	10	10	5	5	5	10	5
à 2000m																												

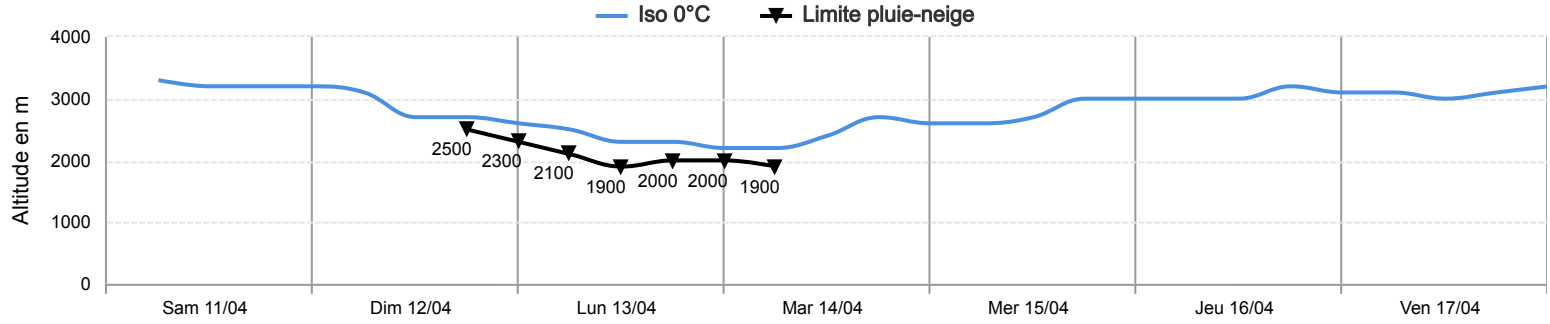

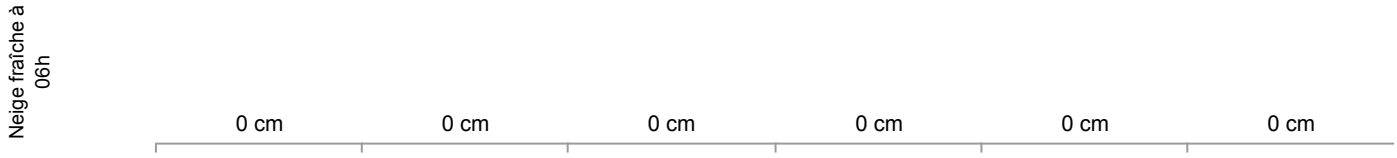

Risque d'avalanche	sam. 11/04	dim. 12/04	lun. 13/04	mar. 14/04	mer. 15/04	jeu. 16/04	ven. 17/04
	3	2	2	2	2	2	2

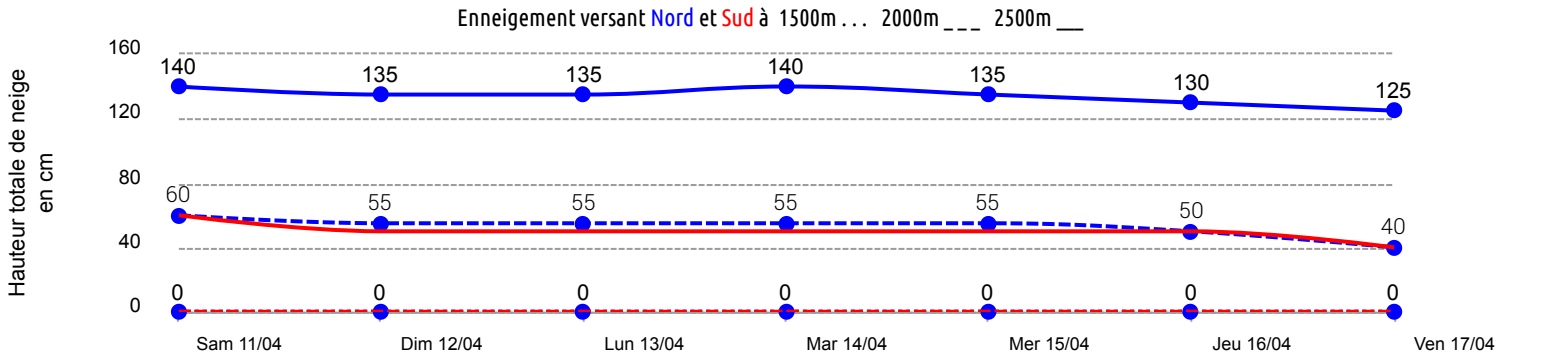

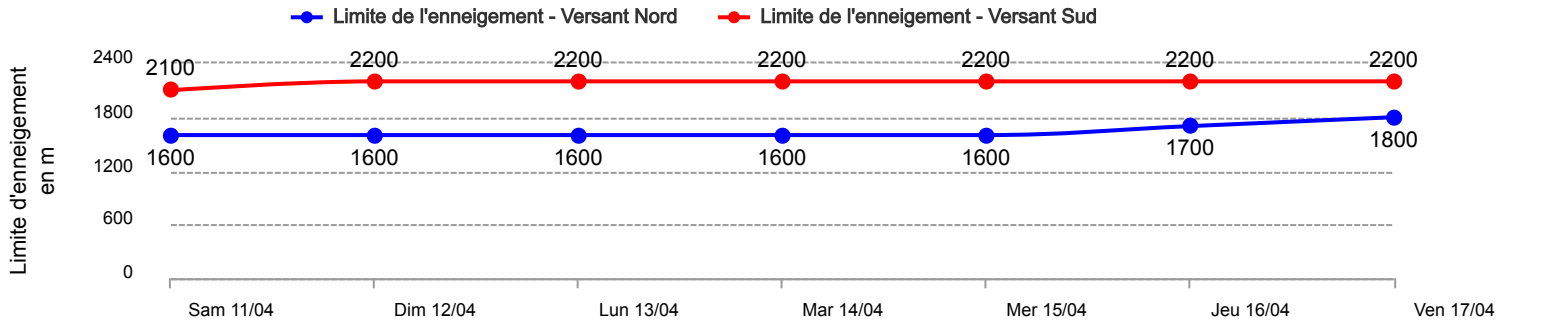

Pour consulter la vigilance en cours, veuillez vous rendre sur le site https://vigilance.meteofrance.fr/fr

Météo-France - 73 avenue de Paris, 94165 Saint-Mandé cedex - Contact : contact@meteo.fr

Bulletin neige & avalanches par téléphone au

0 892 68 10 20 Service 0,35 € / min + prix appel

Rédigé par Météo-France avec la contribution des observateurs du réseau nivo-météorologiques. Partenariat : ANMSM (Maires de Stations de Montagne), DSF (Domaines Skiables de France), ADSP (Directeurs de Pistes et de la Sécurité des Stations de Sports d'Hiver) et autres acteurs de la montagne.