Bulletin d'estimation du risque d'avalanche

(valable en dehors des pistes balisées et ouvertes)

MASSIF : Capcir Puymorens

Rédigé le vendredi 17 avril 2026 à 17h

Estimation des risques pour le : SAMEDI 18 AVRIL

POURSUITE DE L'HUMIDIFICATION

2

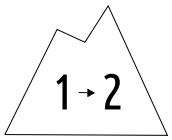

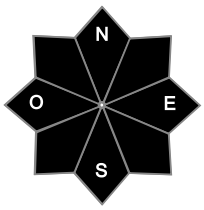

Indice de risque faible évoluant en limité.

Départs spontanés : Départs en neige humide au fil de la journée et de l'humidification; avalanches de fond possibles

Déclenchements provoqués : Possibles persistance de rares plaques dans la neige encore froide en altitude

Indices de risque : 5 très fort - 4 fort - 3 marqué - 2 limité - 1 faible -- En noir : les pentes les plus dangereuses

Stabilité du manteau neigeux

Situation avalancheuse typique : neige humide avalanches de fond

Départs spontanés :

- Peu probables en tout début de journée grâce à un regel efficace. Au fil de la journée, dans les pentes ensoleillées, des départs spontanés d'**avalanches en neige humide** de taille petite à moyenne sont attendus avec la douceur et l'ensoleillement. Ils concernent les pentes nord-est à sud-est dans un premier temps puis se généralisent à l'ensemble des versants. Ces départs emportent la neige récente, et dans de rares cas des couches plus anciennes avec une éventuelle avalanche de moyenne, voire grande taille. Les petites averses attendues par endroits l'après-midi peuvent être favorables à une recrudescence de ces départs.
- Des reptations sont actuellement signalées, signes avant-coureurs de potentielles **avalanches de glissement** pouvant emporter l'ensemble du manteau neigeux, donc de taille moyenne, voire rarement grande.

Déclenchements provoqués :

- Au-dessus de 2400/2500m, il n'est pas impossible que dans de rares pentes à l'ombre, des accumulations de neige encore sèche puissent reposer sur d'éventuelles couches fragiles persistantes. Le passage d'un pratiquant pourrait alors suffire à provoquer une avalanche, généralement petite, possiblement de taille moyenne dans les cas les plus défavorables.

Observables : signe de transport de neige par le vent avec de la neige de surface froide et bien blanche contrastant avec la couche de neige plus ancienne de couleur ocre, fissures devant les skis, "wwoomfs".

- Par ailleurs, un skieur coupant une pente raide déjà humidifiée pourra déclencher une coulée sous ses skis, mobilisant parfois de bonnes quantités de neige humide.

Autre : Des corniches encore imposantes sont en place et sont susceptibles de céder spontanément avec le redoux.

Qualité de la neige

Enneigement :

Excellent enneigement pour avril, parmi les plus importants des 30 dernières années. Avec le redoux et le soleil, la limite skiable remonte progressivement surtout en sud. Elle est encore au mieux vers 1700/1800 m en nord et plutôt 2000 m en sud. L'épaisseur de neige est rapidement conséquente surtout proche de l'Ariège avec souvent 2 m dès 2000m en nord et plus encore en altitude (3 à 4 m de neige).

Qualité de la neige :

Au petit matin, regel efficace en altitude. En journée, reprise rapide de l'humidification avec la neige qui s'humidifie au soleil, plus rapidement si la couche ocre est visible, avec donc de la neige lourde et humide dès la mi-journée. En secteur nord, l'enfoncement peut se faire sur une couche de neige molle assez profonde. En sud, la neige est davantage tassée et donc généralement plus portante. De rares endroits sont restés en neige sèche et plus légère dans les versants raides à l'ombre au-dessus de 2400/2500m. Les cols et crêtes ouest à nord-ouest sont généralement moins garnis en neige voire pelés.

Aperçu météo pour le samedi 18 avril

	nuit	matin	après-midi	soir

Beau temps le matin puis possibles bourgeonnements dans l'après-midi

Pluie-Neige				
Iso 0 °C	3 400 m	3 400 m	3 400 m	3 300 m
Vent 2000 m	→ 10 km/h	→ 10 km/h	→ 15 km/h	→ 10 km/h
Vent 3000 m	→ 15 km/h	→ 15 km/h	→ 20 km/h	→ 15 km/h

Pour consulter la vigilance en cours, veuillez vous rendre sur le site https://vigilance.meteofrance.fr/fr

Météo-France - 73 avenue de Paris, 94165 Saint-Mandé cedex - Contact : contact@meteo.fr

Rédigé par Météo-France avec la contribution des observateurs du réseau nivo-météorologiques. Partenariat : ANMSM (Maires de Stations de Montagne), DSF (Domaines Skiables de France), ADSP (Directeurs de Pistes et de la Sécurité des Stations de Sports d'Hiver) et autres acteurs de la montagne.

Bulletin neige & avalanches par téléphone au 0 892 68 10 20 Service 0,35 € / min + prix appel

RÉPUBLIQUE FRANÇAISE
Liberté Égalité Fraternité

METEO FRANCE
À VOS CÔTÉS, DANS UN CLIMAT QUI CHANGE

Bulletin d'estimation du risque d'avalanche

(valable en dehors des pistes balisées et ouvertes)

MASSIF : Capcir Puymorens

Rédigé le vendredi 17 avril 2026 à 17h

Épaisseur de neige hors-piste

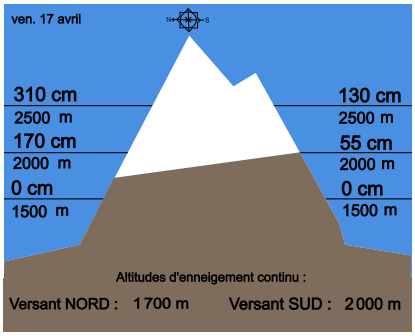

Précipitations à 1800 m

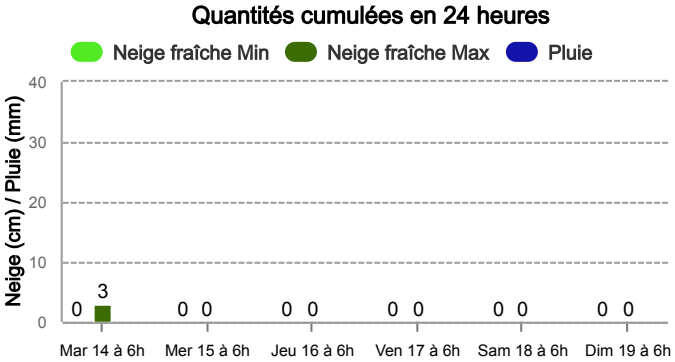

Tendance du dimanche 19 avril

Indice de risque limité

Persistance probable du risque limité. La douceur et les averses attendues dimanche seront favorables à la poursuite de l'humidification du manteau neigeux.

Pour consulter la vigilance en cours, veuillez vous rendre sur le site https://vigilance.meteofrance.fr/fr

Météo-France - 73 avenue de Paris, 94165 Saint-Mandé cedex - Contact : contact@meteo.fr

Rédigé par Météo-France avec la contribution des observateurs du réseau nivo-météorologiques. Partenariat : ANMSM (Maires de Stations de Montagne), DSF (Domaines Skiables de France), ADSP (Directeurs de Pistes et de la Sécurité des Stations de Sports d'Hiver) et autres acteurs de la montagne.

Bulletin neige & avalanches par téléphone au

0 892 68 10 20 Service 0,35 € / min + prix appel

RÉPUBLIQUE FRANÇAISE
Liberté Égalité Fraternité

METEO FRANCE
À VOS CÔTÉS, DANS UN CLIMAT QUI CHANGE

Bulletin d'estimation du risque d'avalanche

(valable en dehors des pistes balisées et ouvertes)

MASSIF : Capcir Puymorens

Rédigé le vendredi 17 avril 2026 à 17h

Conditions nivo-météo des 7 derniers jours

	sam. 11/04				dim. 12/04				lun. 13/04				mar. 14/04				mer. 15/04				jeu. 16/04				ven. 17/04			
	03h	09h	15h	21h	03h	09h	15h	21h	03h	09h	15h	21h	03h	09h	15h	21h	03h	09h	15h	21h	03h	09h	15h	21h	03h	09h	15h	21h
Météo																												
Vent (km/h)	30	30	45	45	35	30	30	40	50	50	55	55	50	50	50	45	35	25	25	20	20	20	25	20	20	20	15	15
à 3000m																												
Vent (km/h)	25	25	35	35	20	20	25	35	35	30	30	25	25	25	25	20	20	15	15	10	10	10	15	10	10	10	10	10
à 2000m																												

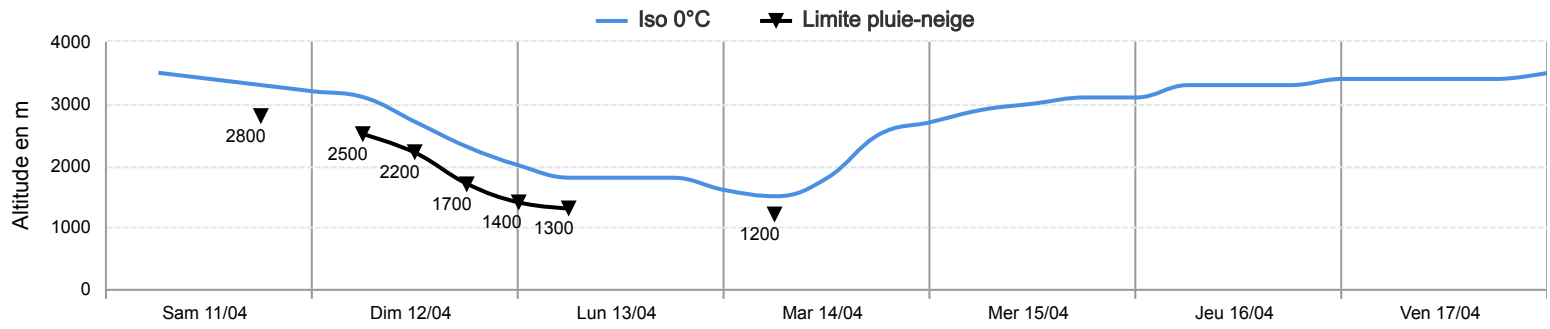

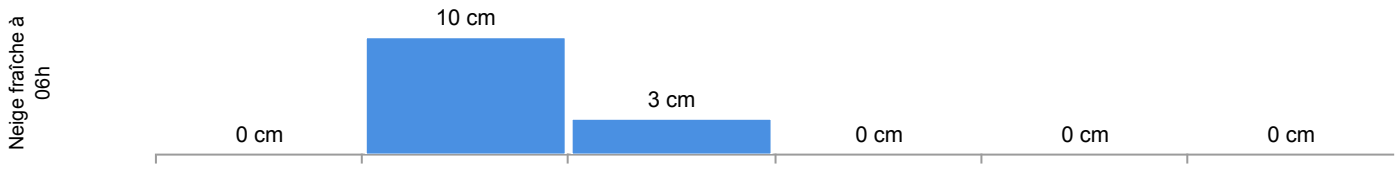

Risque d'avalanche	sam. 11/04	dim. 12/04	lun. 13/04	mar. 14/04	mer. 15/04	jeu. 16/04	ven. 17/04
	3	2	3	2	2	2	2

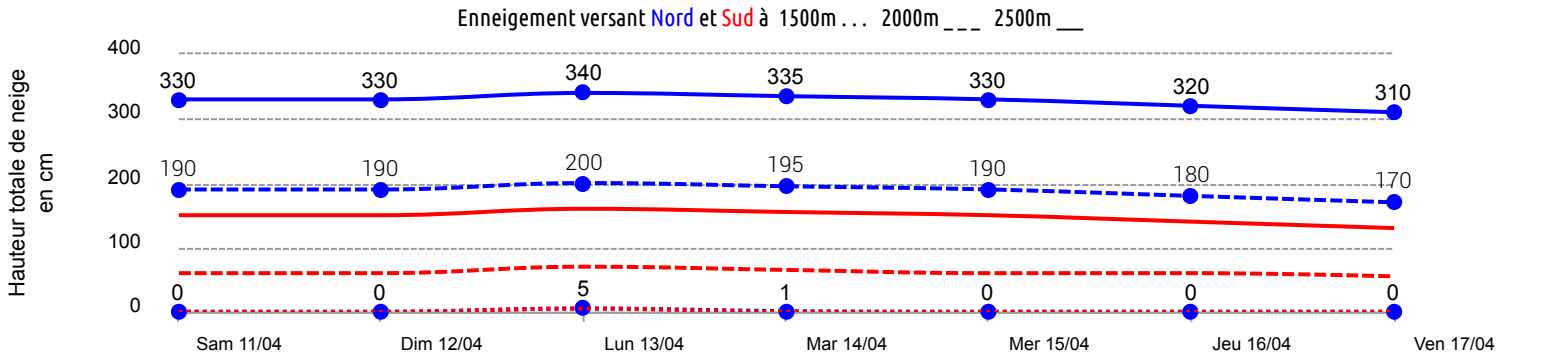

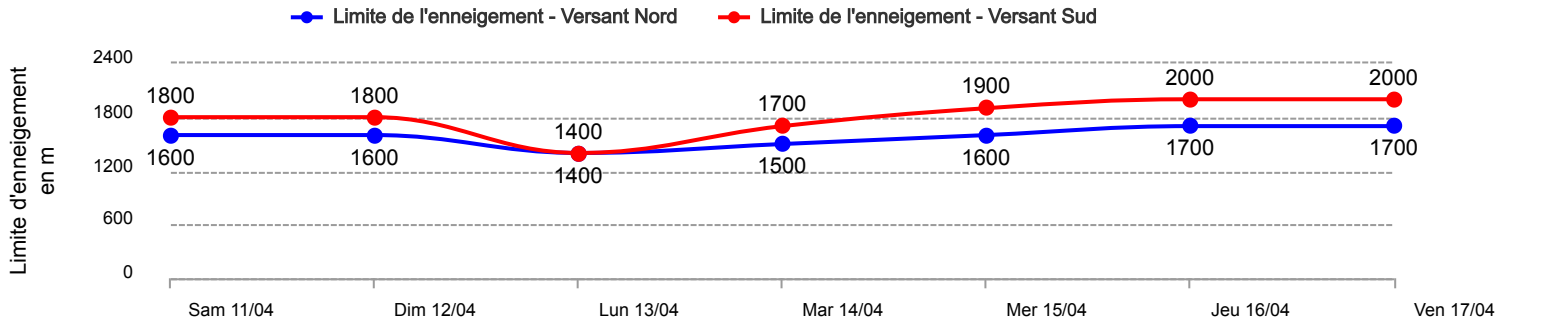

Pour consulter la vigilance en cours, veuillez vous rendre sur le site https://vigilance.meteofrance.fr/fr

Météo-France - 73 avenue de Paris, 94165 Saint-Mandé cedex - Contact : contact@meteo.fr

Rédigé par Météo-France avec la contribution des observateurs du réseau nivo-météorologiques. Partenariat : ANMSM (Maires de Stations de Montagne), DSF (Domaines Skiables de France), ADSP (Directeurs de Pistes et de la Sécurité des Stations de Sports d'Hiver) et autres acteurs de la montagne.

Bulletin neige & avalanches par téléphone au
0 892 68 10 20 Service 0,35 € / min + prix appel