RÉPUBLIQUE FRANÇAISE
Liberté Égalité Fraternité

METEO FRANCE
À VOS CÔTÉS, DANS UN CLIMAT QUI CHANGE

Bulletin d'estimation du risque d'avalanche
(valable en dehors des pistes balisées et ouvertes)

MASSIF : Luchonnais

Rédigé le vendredi 17 avril 2026 à 17h

Estimation des risques pour le : SAMEDI 18 AVRIL

WEEKEND MARQUÉ PAR L'ÉVOLUTION EN PROFONDEUR DE L'HUMIDIFICATION

2

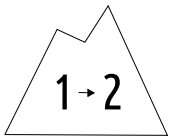

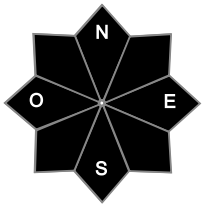

Humidification

Indices de risque : 5 très fort - 4 fort - 3 marqué - 2 limité - 1 faible -- En noir : les pentes les plus dangereuses

Indice de risque faible évoluant en limité.

Départs spontanés : Dans la neige humide, assez rapidement, avalanches de fond possibles.

Déclenchements provoqués : Limités au plus haut du massif, rares

Stabilité du manteau neigeux

Situation avalancheuse typique : neige humide avalanches de fond

Départs spontanés :
L'activité avalancheuse est faible en tout début de journée à la faveur du regel. Mais celui-ci est faible, des départs sont attendus rapidement en matinée, au fil de l'ensoleillement, d'abord dans un large secteur nord-est à sud-est, puis se généralisent progressivement à toutes les expositions, même nord, prenant aussi le soleil à cette saison, puis sous les averses de l'après-midi. Les avalanches atteignent une taille petite à moyenne, plus rarement grande, par départ d'une avalanche de fond, souvent depuis une fissure déjà ouverte, plutôt en secteurs nord, en particulier nord-est où les accumulations sont plus importantes.

Déclenchements provoqués :
Le passage d'un skieur dans la neige très humide peut favoriser un départ ponctuel de taille petite voire moyenne. Dans les secteurs nord les plus hauts du massif, quelques plaques peuvent encore avoir échappé à l'humidification mais sont devenues assez difficilement déclenchables par tassement.

Autres :
Neige dure et glissante au petit matin. Avec la douceur ambiante, les corniches et ponts de neige deviennent à nouveau très fragiles.

Qualité de la neige

Enneigement : L'enneigement est plutôt bon pour la saison, débutant vers 1650m en nord, et 1950m environ en sud. Cette limite d'enneigement tend à remonter progressivement avec la douceur ambiante et le soleil.
État de la neige : Modeste regel samedi matin, la neige s'humidifie ensuite rapidement (neige molle à la mi-journée sous 2500m), avec des enfoncements importants en expositions nord. Elle est plus portante car déjà bien tassée en versants ensoleillés ou sur la neige ocre.

Aperçu météo pour le samedi 18 avril

	nuit	matin	après-midi	soir

Matinée bien ensoleillée, développement de nuages l'après-midi, donnant quelques averses.

Pluie-Neige			3 000 m	
Iso 0 °C	3 400 m	3 400 m	3 300 m	3 300 m
Vent 2000 m	5 km/h	5 km/h	15 km/h	10 km/h
Vent 3000 m	10 km/h	10 km/h	25 km/h	20 km/h

Épaisseur de neige hors-piste

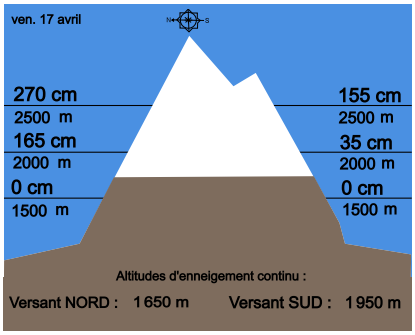

Précipitations à 1800 m

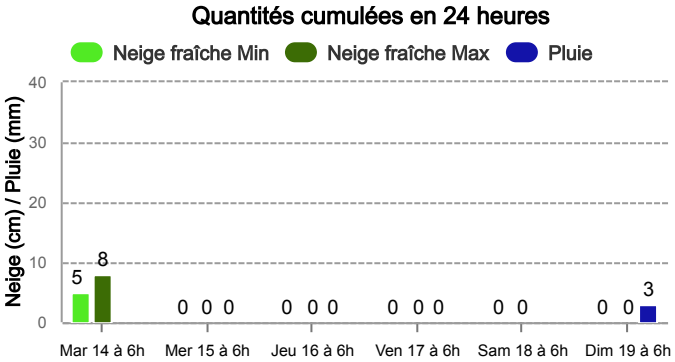

Tendance du dimanche 19 avril

2

Indice de risque limité

L'humidification se poursuit en profondeur, avec un regel médiocre. L'activité en neige humide va s'accroître au fil des jours

Pour consulter la vigilance en cours, veuillez vous rendre sur le site https://vigilance.meteofrance.fr/fr

Météo-France - 73 avenue de Paris, 94165 Saint-Mandé cedex - Contact : contact@meteo.fr

Rédigé par Météo-France avec la contribution des observateurs du réseau nivo-météorologiques. Partenariat : ANMSM (Maires de Stations de Montagne), DSF (Domaines Skiables de France), ADSP (Directeurs de Pistes et de la Sécurité des Stations de Sports d'Hiver) et autres acteurs de la montagne.

Bulletin neige & avalanches par téléphone au
0 892 68 10 20 Service 0,35 € / min + prix appel

RÉPUBLIQUE FRANÇAISE
Liberté Égalité Fraternité

METEO FRANCE
À VOS CÔTÉS, DANS UN CLIMAT QUI CHANGE

Bulletin d'estimation du risque d'avalanche

(valable en dehors des pistes balisées et ouvertes)

MASSIF : Luchonnais

Rédigé le vendredi 17 avril 2026 à 17h

Conditions nivo-météo des 7 derniers jours

	sam. 11/04				dim. 12/04				lun. 13/04				mar. 14/04				mer. 15/04				jeu. 16/04				ven. 17/04			
	03h	09h	15h	21h	03h	09h	15h	21h	03h	09h	15h	21h	03h	09h	15h	21h	03h	09h	15h	21h	03h	09h	15h	21h	03h	09h	15h	21h
Météo																												
Vent (km/h)	45	50	35	60	30	25	20	30	55	45	35	30	55	55	45	40	45	20	25	30	20	15	15	20	20	15	10	10
à 3000m																												
Vent (km/h)	30	25	10	15	5	10	10	10	20	20	15	10	15	15	20	5	5	10	15	5	5	5	5	5	5	5	5	5
à 2000m																												

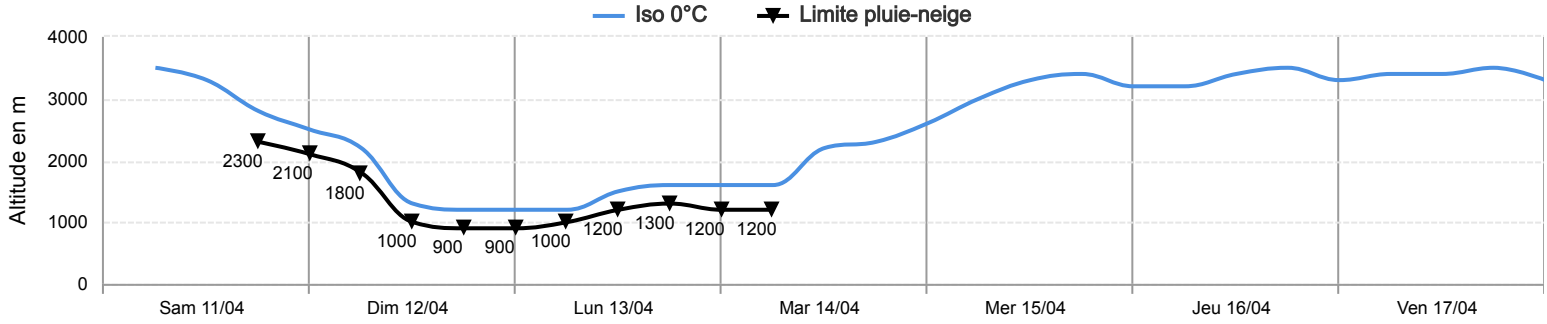

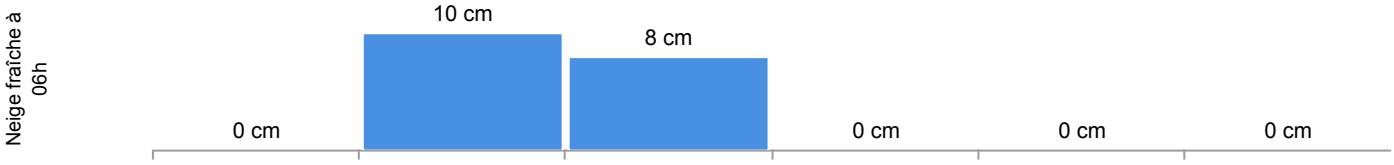

Risque d'avalanche	sam. 11/04	dim. 12/04	lun. 13/04	mar. 14/04	mer. 15/04	jeu. 16/04	ven. 17/04
	2	2	3	2	2	2	2

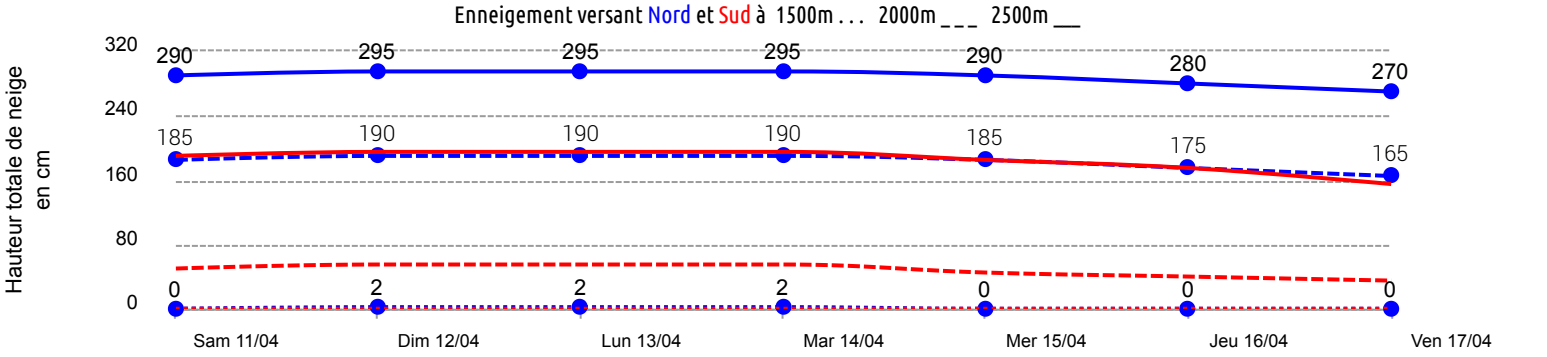

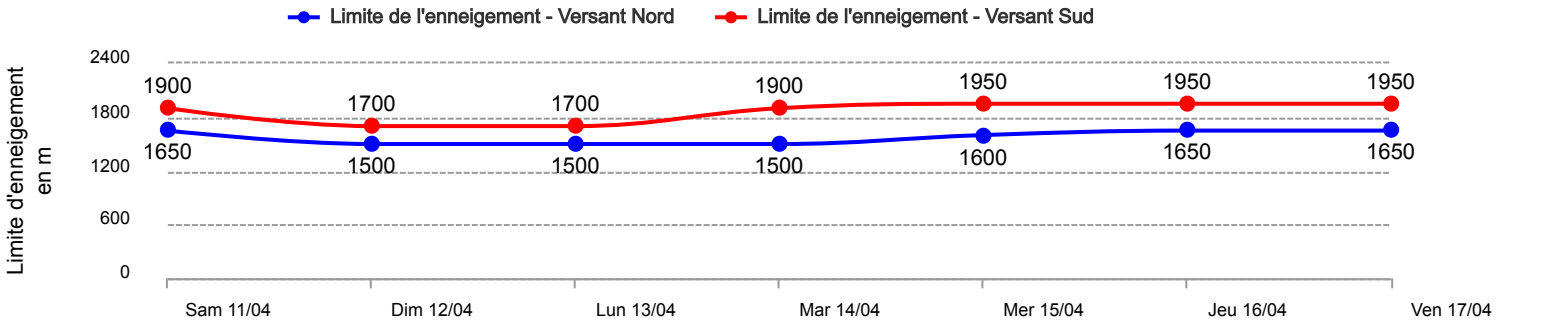

Pour consulter la vigilance en cours, veuillez vous rendre sur le site https://vigilance.meteofrance.fr/fr

Météo-France - 73 avenue de Paris, 94165 Saint-Mandé cedex - Contact : contact@meteo.fr

Rédigé par Météo-France avec la contribution des observateurs du réseau nivo-météorologiques. Partenariat : ANMSM (Maires de Stations de Montagne), DSF (Domaines Skiables de France), ADSP (Directeurs de Pistes et de la Sécurité des Stations de Sports d'Hiver) et autres acteurs de la montagne.

Bulletin neige & avalanches par téléphone au
0 892 68 10 20 Service 0,35 € / min + prix appel