GOBIERNO DE ESPAÑA
VICEPRESIDENCIA TERCERA DEL GOBIERNO
MINISTERIO PARA LA TRANSICIÓN ECOLÓGICA Y EL RETO DEMOGRÁFICO

Boletín de información nivológica y de peligro de aludes

Pirineo Navarro y Aragonés

aemet Agencia Estatal de Meteorología

sábado, 18 de abril de 2026

Pronóstico hasta las 24 horas del domingo, día 19 de abril

(Válido fuera de pistas de esquí balizadas y abiertas)

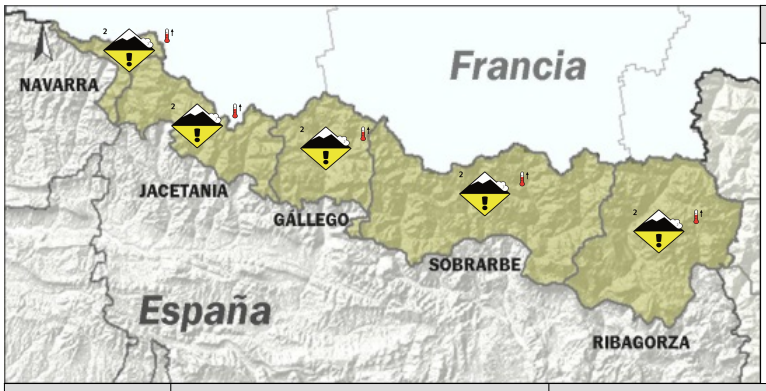

Problemas de aludes

Nieve húmeda

Deslizamientos basales

Macizo	Peligro	Problemas de aludes, cota, orientación, tamaño	Innivación observada (m)
Navarra	2 Limitado	Nieve húmeda: 2 / Deslizamientos basales: 2	2026-04-18 Cota más baja caras N
Jacetania	2 Limitado	Nieve húmeda: 2 / Deslizamientos basales: 2	2026-04-18 Cota más baja caras N
Gállego	2 Limitado	Nieve húmeda: 2 / Deslizamientos basales: 2	2026-04-18 Cota más baja caras N

AEMET. Se autoriza la reproducción de su contenido citando la fuente.

Boletín de información nivológica y de peligro de aludes

Pirineo Navarro y Aragonés

Sobrarbe	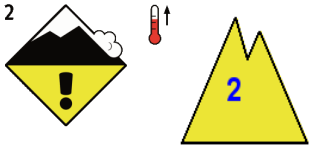 **Limitado**	**Nieve húmeda**  **Deslizamientos basales** 	2026-04-18 Cota más baja caras N
Ribagorza	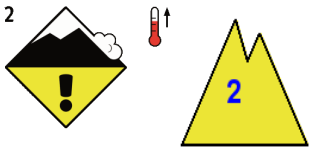 **Limitado**	**Nieve húmeda** **Deslizamientos basales** 	2026-04-18 Cota más baja caras N

Estado del manto y observaciones recientes

Continúa la fusión del manto como consecuencia de las elevadas temperaturas, con una mengua de espesores que en algún caso supera los 10 cm durante las últimas 24 horas. La insolación a estas alturas del mes de abril es intensa y hace mella en las laderas de solana, donde las superficies desprovistas de nieve cada vez las encontramos a mayor altitud. En umbrías la nieve se conserva mejor, pero sigue erosionándose y su continuidad va disminuyendo progresivamente. Con todo ello, aún podemos encontrar cantidades que superan holgadamente los 100 cm por encima de 2.100 metros en numerosas zonas, aún más en ventisqueros y otras áreas propensas a a la acumulación.
El manto es típicamente primaveral, con nieve muy humedecida y predominio de grano redondo. El rehielo nocturno es débil y está prácticamente restringido a la alta montaña.

Evolución del manto y peligro de aludes para el domingo, día 19

Situación de nieve húmeda y deslizamientos basales.

Pocos cambios en el nivel de peligro, con temperaturas que seguirán siendo más altas de lo normal para estas fechas, tanto diurnas como nocturnas, y previsión de chubascos, sobre todo durante las horas vespertinas, que contribuirán a humidificar aún más un manto de nieve vieja y muy evolucionada. Por ello serán probables las purgas de nieve húmeda en pendientes suficientemente inclinadas de cualquier orientación, que en general serán de tamaño pequeño o mediano, pero no se descarta algún deslizamiento basal en laderas herbosas o de roca lisa que, al arrastrar la totalidad del manto, pueda adquirir dimensión grande, suficiente como para enterrar a un grupo de personas, por lo que se recomienda tomar precauciones durante el transito.

AEMET. Se autoriza la reproducción de su contenido citando la fuente.

Predicción meteorológica para el domingo, día 19

Intervalos nubosos, con nubes medias, altas y, sobre todo por la tarde, nubosidad de evolución diurna. Se esperan chubascos y tormentas durante la segunda mitad del día, que podrían ser localmente fuertes y con granizo. Cota de nieve: muy elevada, en torno a 2.700 ó 2.800 metros. Temperaturas en ligero o moderado ascenso. Alguna helada débil en la alta montaña. Vientos flojos de dirección variable, con intervalos de oeste moderado en cotas altas, pudiendo ser fuertes y racheados durante los chubascos o tormentas.

Datos en la atmósfera libre:

Altitud de la isoterma de 0 ºC: 3.200 m
Altitud de la isoterma de -10 ºC: 4.500 m

Viento a 1500 m: SW 15 km/h
Viento a 3000 m: W 30 km/h

Evolución para el lunes día 20

Nivel de peligro con pocos cambios.

(Información elaborada a partir de los datos recibidos de los refugios de Linza, Lizara, Respomuso, Panticosa, Bachimaña, Góriz, Pineta, Estós, Angel Orús, La Renclusa, Cap de Llauset y Belagua, de las estaciones de esquí de Formigal y Panticosa (lagos) y de Ordesa Pradera)

Escala europea de peligro de aludes

Débil | Limitado | Notable | Fuerte | Muy Fuerte

Problemas de aludes

Nieve reciente | Placas de viento | Capas débiles persistentes | Nieve húmeda | Deslizamientos basales | Sin problema evidente

Nota1: Se recuerda que, siempre que haya nieve, la ausencia total de peligro no existe. Hay que tener presente que en circunstancias desfavorables, con aludes de tamaño 1 (alud pequeño o colada) y tamaño 2 (alud mediano), se pueden sufrir severos daños personales.

Nota2: Los BPA se elaboran en base a información meteorológica así como al estado del manto nivoso a través de sondeos puntuales. Se advierte a los usuarios de la variabilidad de esta información al extrapolarla a zonas extensas de montaña. Por ello, AEMET no se hace responsable de su uso para la toma de decisiones que conciernen a la seguridad personal, ni de los riesgos físicos o materiales de ellas derivadas.

AEMET. Se autoriza la reproducción de su contenido citando la fuente.