Sonntag 19.04.2026

Veröffentlicht am 18.04.2026 um 17:00

Vormittag

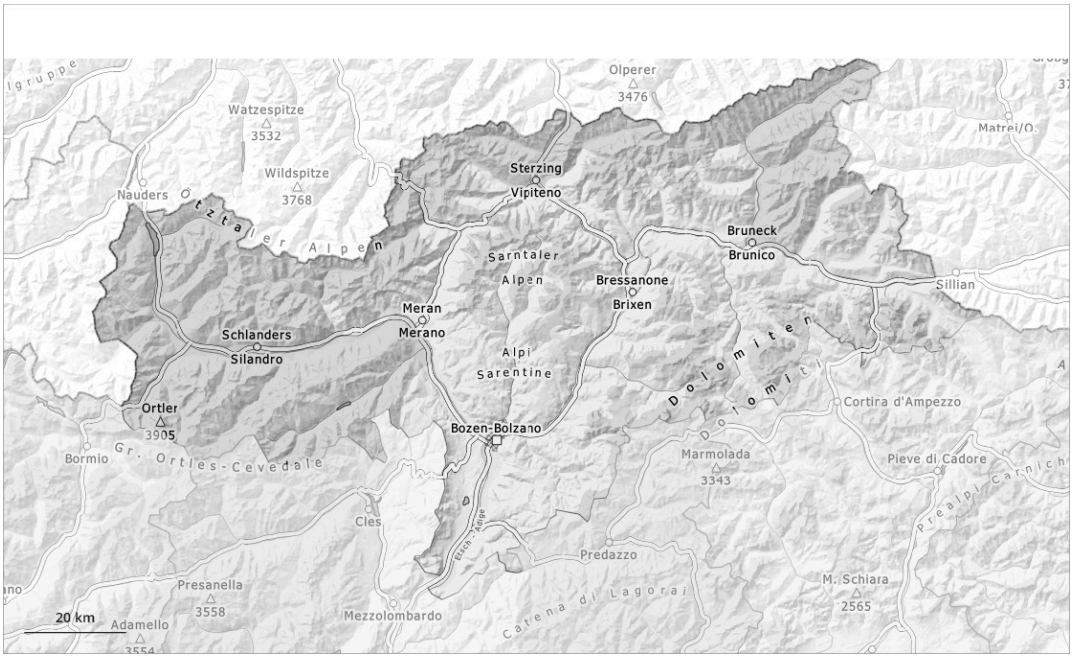

Nachmittag

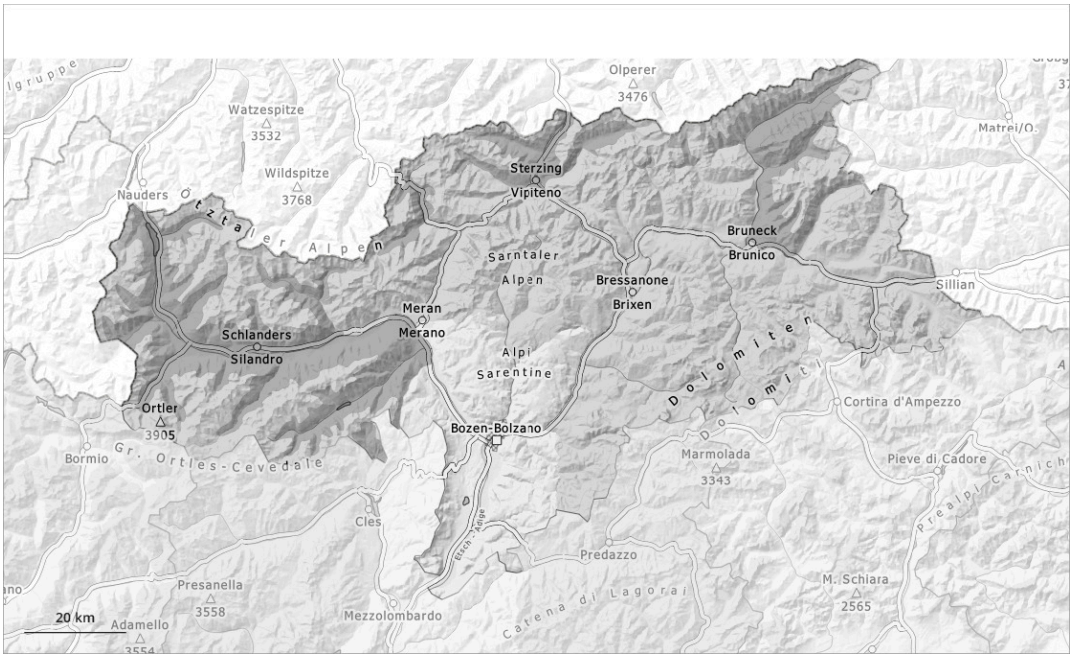

1	2	3	4	5
gering	mäßig	erheblich	groß	sehr groß

Gefahrenstufe 3 - Erheblich

AM:

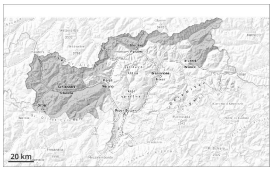

Tendenz: Lawinengefahr bleibt gleich
am Montag, den 20.04.2026

Altschnee

Nassschnee

PM:

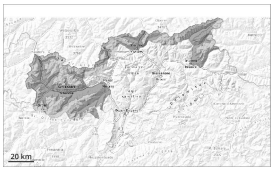

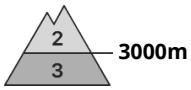

Tendenz: Lawinengefahr bleibt gleich
am Montag, den 20.04.2026

Nassschnee

Altschnee

Anstieg der Gefahr von nassen Lawinen im Tagesverlauf.

Ab dem Vormittag steigt die Auslösebereitschaft von nassen Lawinen an. Mit der tageszeitlichen Erwärmung und der Sonneneinstrahlung sind nasse Lockerschneelawinen möglich, besonders aus sehr steilen noch nicht vollständig entladenen Einzugsgebieten.

Mit der Durchnässung sind im Tagesverlauf nasse Schneebrettlawinen möglich, vor allem solche mittlerer Größe. Dies besonders aus schattseitigen Einzugsgebieten, vereinzelt aber auch aus hoch gelegenen sonnenbeschienenen noch nicht entladenen Einzugsgebieten.

Einzelne Gefahrenstellen für trockene Lawinen liegen an sehr steilen Schattenhängen oberhalb von rund 2500 m. Ungünstig sind besonders Übergänge von wenig zu viel Schnee. Die Gefahrenstellen sind schwer zu erkennen.

Schneedecke

Gefahrenmuster gm.10: frühjahrssituation | gm.1: bodennahe schwachschicht

Ab dem Mittag fällt gebietsweise Regen bis auf 2600 m. Die nächtliche Abstrahlung ist zeitweise recht gut. Die Schneeoberfläche weicht rasch auf. Sonne und Wärme führen unterhalb von rund 3000 m zu einer

raschen Durchnässung der Schneedecke.
West-, Nord- und Osthänge oberhalb von rund 2500 m: Im unteren Teil der Altschneedecke sind in der Höhe kantig aufgebaute Schwachschichten vorhanden.

Tendenz

Es fallen gebietsweise bis zu 10 cm Schnee. Dies vor allem in der Höhe in der Venedigergruppe und in der Glocknergruppe.

Gefahrenstufe 2 - Mäßig

AM:

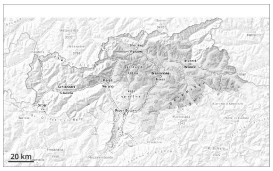

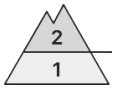

2500m

Tendenz: Lawinengefahr bleibt gleich
am Montag, den 20.04.2026

Altschnee

2500m

PM:

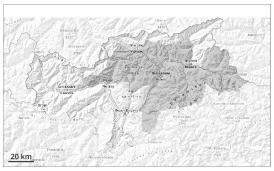

Tendenz: Lawinengefahr bleibt gleich
am Montag, den 20.04.2026

Nassschnee

3000m

Altschnee

2500m

Anstieg der Gefahr von nassen Lawinen im Tagesverlauf.

Mit der tageszeitlichen Erwärmung und der Sonneneinstrahlung steigt die Gefahr von nassen Lawinen im Tagesverlauf an. Dort wo lokal viel Regen fällt ist die Lawinengefahr höher. Nasse Lawinen können stellenweise von einzelnen Wintersportlern ausgelöst werden. Dies an sehr steilen Schattenhängen unterhalb von rund 2500 m sowie an sehr steilen Sonnenhängen in der Höhe. Am Nachmittag sind kleine und mittlere spontane Lawinen möglich.

Einzelne Gefahrenstellen für trockene Lawinen liegen an sehr steilen Schattenhängen oberhalb von rund 2500 m. Ungünstig sind besonders Übergänge von wenig zu viel Schnee. Die Gefahrenstellen sind schwer zu erkennen.

Schneedecke

Gefahrenmuster gm.10: frühjahrssituation | gm.1: bodennahe schwachschicht

Ab dem Mittag fällt gebietsweise Regen bis auf 2600 m. Die nächtliche Abstrahlung ist zeitweise recht gut. Die Schneeoberfläche gefriert tragfähig und weicht im Tagesverlauf auf. Die frühlingshaften Wetterbedingungen führen in mittleren und hohen Lagen zu einer raschen Aufweichung der Schneedecke. Steile Hänge: Im unteren Teil der Altschneedecke sind in der Höhe kantig aufgebaute Schwachschichten vorhanden.

Tendenz

> Es fällt lokal etwas Regen. Die Gefahr von nassen Lawinen bleibt bestehen.

Gefahrenstufe 1 - Gering

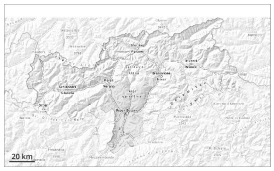

1

Tendenz: Lawinengefahr bleibt gleich
am Montag, den 20.04.2026

Nassschnee

N
S

2000m

Nassschnee beachten.

Es sind nur noch vereinzelt nasse Lawinen möglich. Vorsicht an extrem steilen Schattenhängen. Lawinen sind meist eher klein.

Schneedecke

Gefahrenmuster gm.10: frühjahrssituation gm.1: bodennahe schwachschicht

Die Schneeoberfläche gefriert tragfähig und weicht im Tagesverlauf auf.

Tendenz

Geringe Lawinengefahr. Nassschnee beachten.