Sonntag 19.04.2026

Veröffentlicht am 18.04.2026 um 17:00

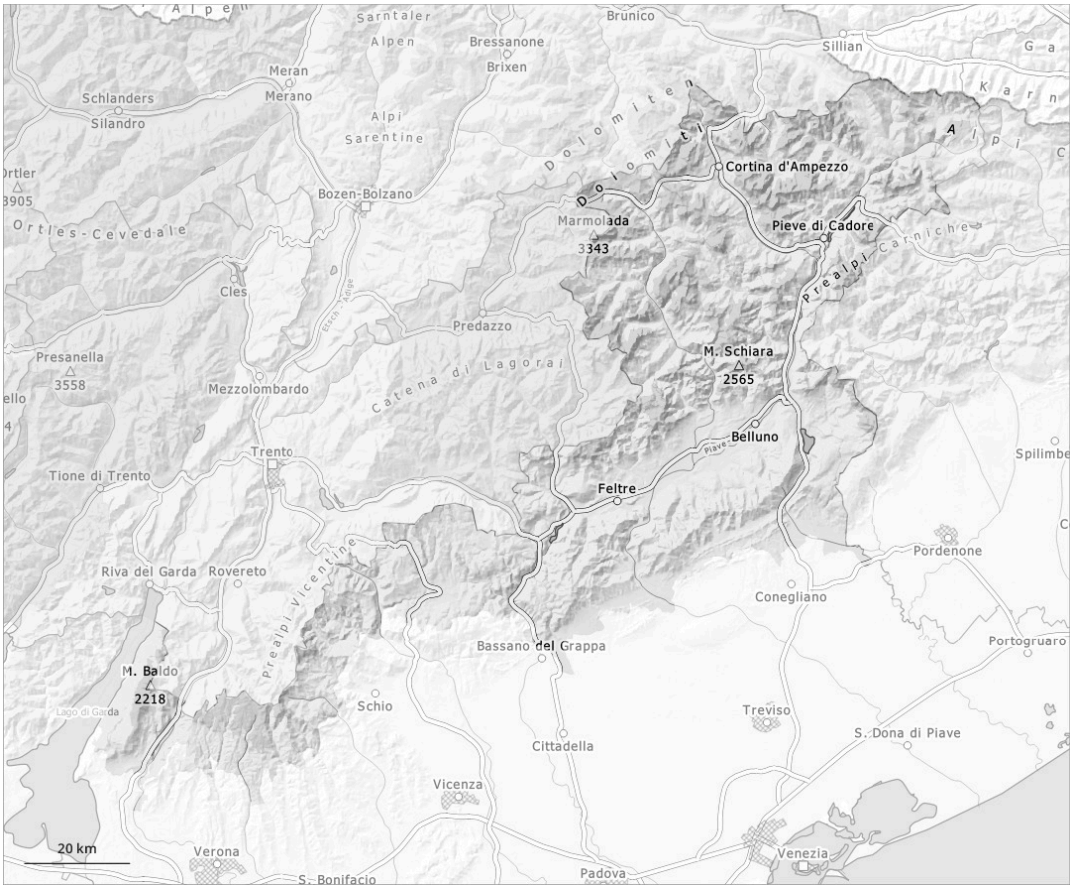

1	2	3	4	5
gering	mäßig	erheblich	groß	sehr groß

Gefahrenstufe 2 - Mäßig

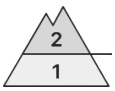

1900m

Tendenz: Lawinengefahr bleibt gleich
am Montag, den 20.04.2026

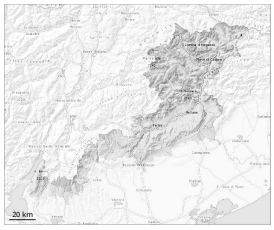

Nassschnee

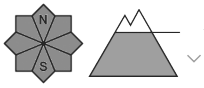

1900m

Nassschnee

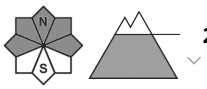

2700m

Triebschnee

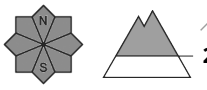

2700m

Es fallen gebietsweise oberhalb von rund 2700 m bis zu 5 cm Schnee, lokal auch mehr.

Die Gefahrenstellen für feuchte Lawinen liegen v.a. an Böschungen unterhalb von rund 2800 m. Besonders ungünstig sind Felswandfüße. Feuchte Lawinen können an sehr steilen Schattenhängen aus noch nicht vollständig entladenen Einzugsgebieten sehr vereinzelt groß werden. Die frischeren Triebschneeansammlungen liegen besonders in Gipfellagen. Die Gefahrenstellen liegen vor allem in Kammlagen, Rinnen und Mulden der Expositionen Nordwest über Nord bis Nordost oberhalb von rund 2500 m. Besonders gefährlich sind Übergänge von wenig zu viel Schnee, wo Schwachstellen im Altschnee vorhanden sind.
Kaum Anstieg der Gefahr von feuchten und nassen Lawinen mit dem Niederschlag.

Schneedecke

In der Schneedecke sind an Nordwest-, Nord- und Nordosthängen heikle Schwachschichten vorhanden. Die Wetterbedingungen führen im Tagesverlauf vor allem an steilen Hängen unterhalb von rund 2700 m stellenweise zu einer zunehmenden Anfeuchtung der Schneedecke. Der Neuschnee wird unterhalb von rund 2700 m auf eine schwache Altschneedecke abgelagert.