Sonntag 19.04.2026

Veröffentlicht am 18.04.2026 um 17:00

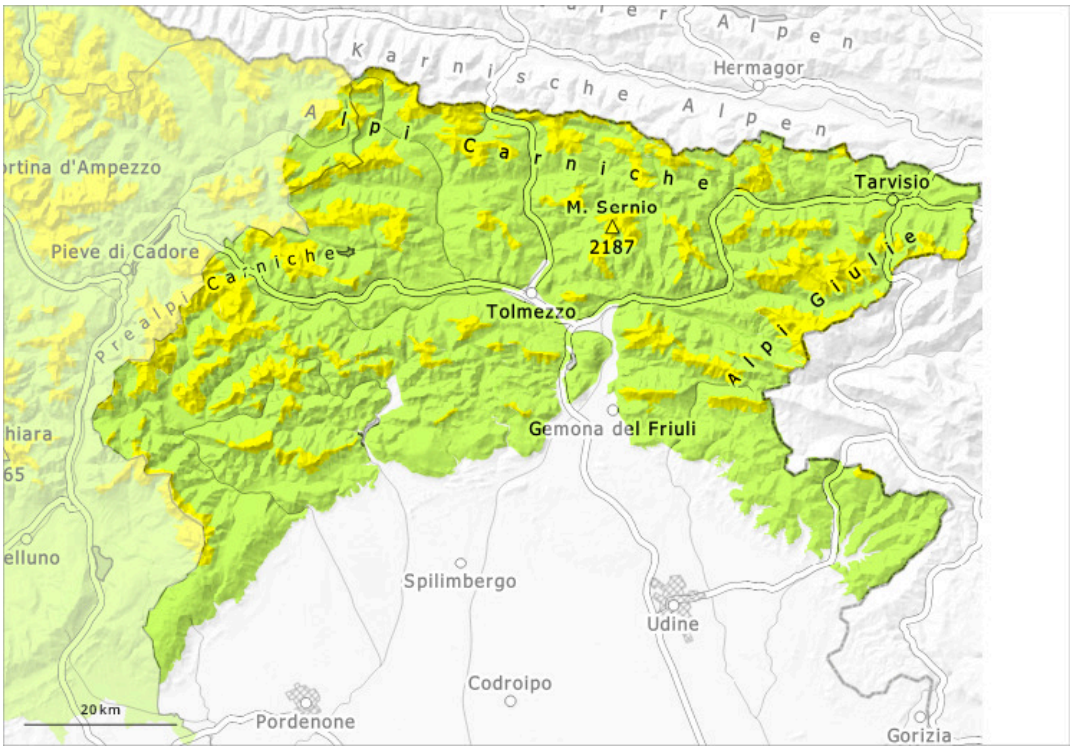

1	2	3	4	5
gering	mäßig	erheblich	groß	sehr groß

Gefahrenstufe 2 - Mäßig

1800m

Tendenz: Lawinengefahr bleibt gleich
am Montag, den 20.04.2026

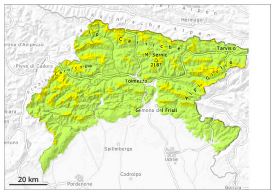

Nassschnee

1800m

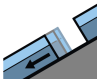

Gleitschnee

1800m

Altschnee

1800m

Verbreitet Regen. Mit der Anfeuchtung nehmen die Gefahrenstellen zu.

Es sind Nass- und Gleitschneelawinen möglich. Die Lawinengefahr sollte vor Ort besonders gründlich überprüft werden. Die Gefahrenstellen liegen vor allem an Felswandfüßen, sowie in Kammlagen, Rinnen und Mulden. Besonders heikel sind Stellen, wo Schwachstellen im Altschnee vorhanden sind. Die Lawinen können in tiefen Schichten anreißen.

Schneedecke

Snow cover and thickness vary greatly depending on exposure and altitude, and are steadily decreasing. Weather conditions will further soak the snowpack in many areas. Verbreitet liegt an Südhängen wenig Schnee. In der Schneedecke sind vor allem an Schattenhängen Schwachschichten vorhanden.

Tendenz

Es ist bewölkt. Verbreitet Regen unterhalb von rund 2000 m.