ICGC Institut Cartogràfic i Geològic de Catalunya

Servei Meteorològic de Catalunya meteo.cat

Boletín de peligro de aludes para el Pirineo de Catalunya
Del 18/04/2026 al 20/04/2026

(Válido fuera pistas de esquí y zonas no controladas)

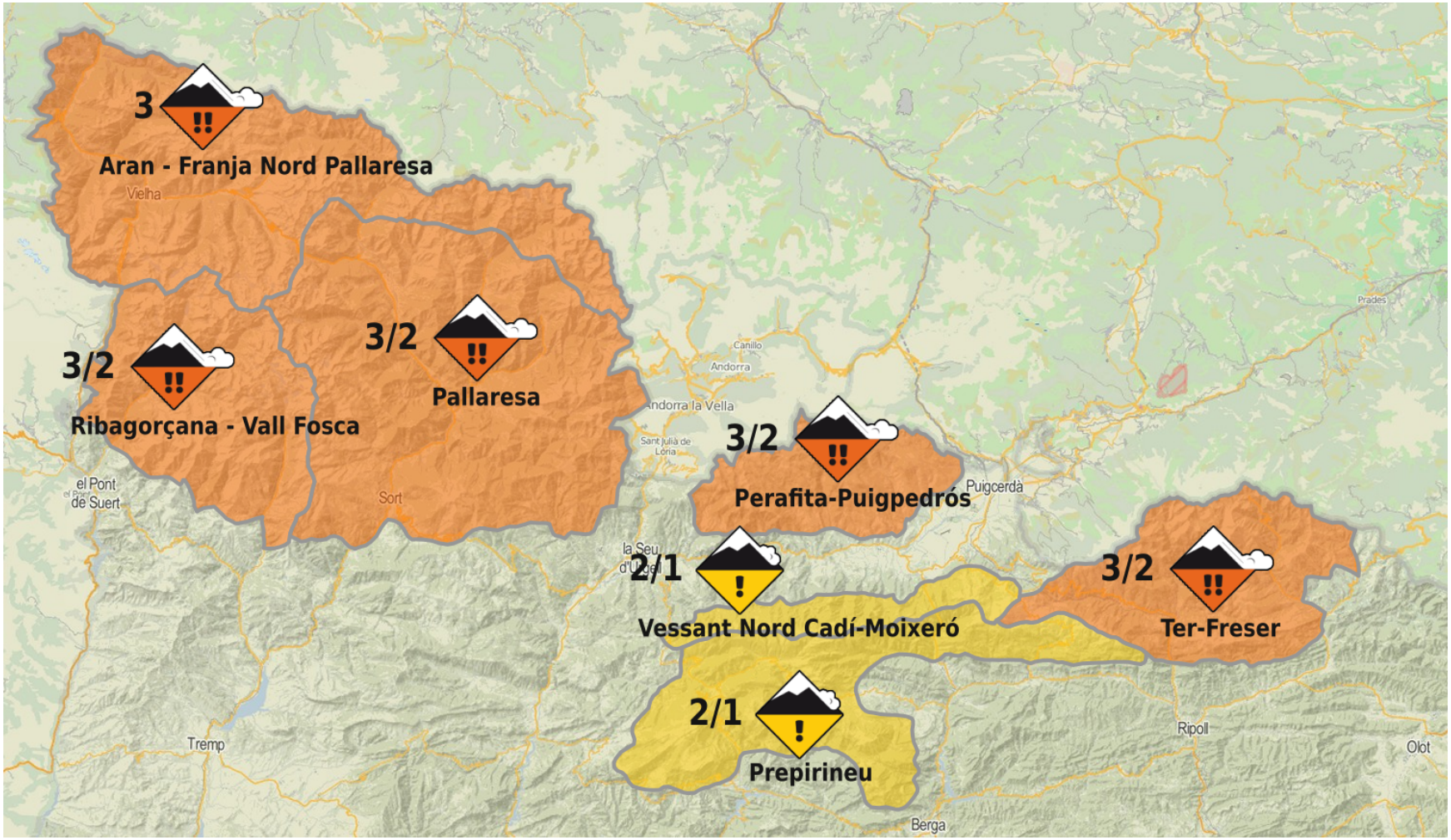

5 MUY FUERTE	4 FUERTE	3 NOTABLE	2 LIMITADO	1 DÉBIL

ICGC Institut Cartogràfic i Geològic de Catalunya

Servei Meteorològic de Catalunya

Boletín de peligro de aludes Aran - Franja Nord Pallaresa Del 18/04/2026 al 20/04/2026

(Válido fuera pistas de esquí y zonas no controladas)

Marcado (3)

Situación primaria

Deslizamientos basales **Distribución** **Tamaño** **Origen** **Tendencia**

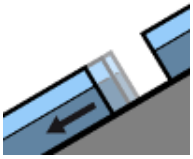

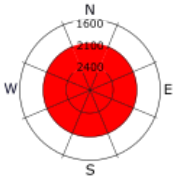

Situación secundaria

Nieve húmeda **Distribución** **Tamaño** **Origen** **Tendencia**

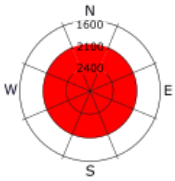

Estado del manto nivoso

El manto nivoso se encuentra húmedo. El rehielo nocturno es cada vez menor y menos eficiente. Desde el viernes tarde caen deslizamientos basales y aludes de fusión. Se esperan lluvias y chubascos todos los días, hasta el lunes en forma de agua hasta las cimas. En estas condiciones se espera que continúe la actividad de deslizamientode de hasta tamaño 3 (grande, suficiente para enterrar un grupo). Además son muy probables las caídas naturales de aludes de fusión, que serán en general de de tamaño 2 (mediano, con capacidad de cubrirnos). Las caídas de aludes y deslizamientos, afectan a cualquier orientación en momentos chubasco y cuando falte el rehielo. Por encima los 2200 m es donde los aludes y deslizamientos son de mayor alcance dado el mayor grosor movilizable de nieve. Hay que prestar atención a la aparición de grietas para evitar los deslizamientos y evitar los momentos de lluvia. De noche y madrugada puede haber cierto rehielo que favorezca levemente la estabilidad.

Distribución del manto nivoso

Hay nieve en el suelo con continuidad por encima de 1.800-1.900 m en umbrías y de 2.000 m en solanas. Los espesores a unos 2.200 m rondan los 135-215 cm. Los valores están por encima de los normales por la época.

Tendencia para las próximas 48-72h

Se mantendrá la situación de fusión. Evolución del peligro: ESTACIONARIO

El próximo boletín será emitido el día 2026-04-20

5 MUY FUERTE	4 FUERTE	3 NOTABLE	2 LIMITADO	1 DÉBIL

EAWS EUROPEAN AVALANCHE WARNING SERVICES

ICGC Institut Cartogràfic i Geològic de Catalunya

meteo.cat Servei Meteorològic de Catalunya

Boletín de peligro de aludes Ribagorçana - Vall Fosca Del 18/04/2026 al 20/04/2026

(Válido fuera pistas de esquí y zonas no controladas)

Notable (3) en el extremo norte, Limitado (2) en el resto.

Situación primaria

Deslizamientos basales | **Distribución** | **Tamaño** | **Origen** | **Tendencia**

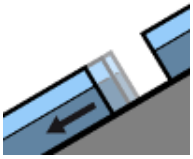

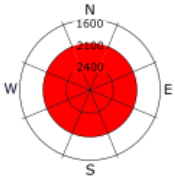

Situación secundaria

Nieve húmeda | **Distribución** | **Tamaño** | **Origen** | **Tendencia**

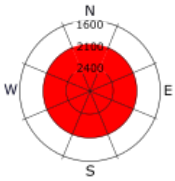

Estado del manto nivoso

Hasta el sábado el manto se mantiene húmedo de día y se encostra de noche y madrugada. Con los chubascos y lluvias previstos el sábado tarde, domingo y lunes, siempre en forma de agua hasta cotas altas, se prevé un fuerte humedecimiento del manto y que continúe la caída de deslizamientos basales y aludes de fusión. Los deslizamientos basales pueden tener tamaño para enterrarnos (tamaño 2, mediano) e incluso pueden alcanzar tamaño suficiente para tapar un grupo (tamaño 3, grande) en el extremo norte del sector. Las vertientes más proclives son las vertientes de suelo herboso. Los aludes de fusión pueden tener tamaño suficiente para enterrarnos. Las orientaciones afectadas por deslizamientos y por fusión son todas y los tamaños de los aludes de mayor alcance serán en el extremo norte de este sector y por encima de los 2200 m, donde el grosor movilizable de nieve es mayor. De noche y madrugada puede haber un cierto rehielo pero las costras que se formen, transforman rápidamente a fusión.

Distribución del manto nivoso

Hay nieve por encima de 1.800-2.000 m pero esquiable en N por encima de 2.100 m-2.300 m en S. Se alcanzan los 75-95 cm a unos 2.200 m, con frecuentes deflaciones y acumulaciones por encima del nivel del bosque. Estos valores están ligeramente por debajo de los normales para la época.

Tendencia para las próximas 48-72h

Se mantendrá la situación de fusión. Evolución del peligro: ESTACIONARIO

El próximo boletín será emitido el día 2026-04-20

5 MUY FUERTE	4 FUERTE	3 NOTABLE	2 LIMITADO	1 DÉBIL

EAWS EUROPEAN AVALANCHE WARNING SERVICES

ICGC Institut Cartogràfic i Geològic de Catalunya

meteo.cat Servei Meteorològic de Catalunya

Boletín de peligro de aludes Pallaresa
Del 18/04/2026 al 20/04/2026

(Válido fuera pistas de esquí y zonas no controladas)

Notable (3) en el extremo norte, Limitado (2) en el resto.

Situación primaria

Deslizamientos basales | **Distribución** | **Tamaño** | **Origen** | **Tendencia**

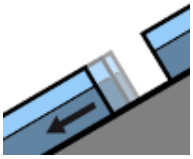

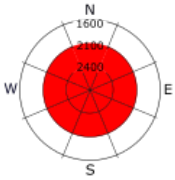

Situación secundaria

Nieve húmeda | **Distribución** | **Tamaño** | **Origen** | **Tendencia**

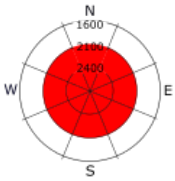

Estado del manto nivoso

Hasta el sábado el manto se mantiene húmedo de día y se encostra de noche y madrugada. Con los chubascos y lluvias previstos el sábado tarde, domingo y lunes, siempre en forma de agua hasta cotas altas, se prevé un fuerte humedecimiento del manto y que continúe la caída de deslizamientos basales y aludes de fusión. Los deslizamientos basales pueden tener tamaño para enterrarnos (tamaño 2, mediano) e incluso pueden alcanzar tamaño suficiente para tapar un grupo (tamaño 3, grande) en el extremo norte del sector. Las vertientes más proclives son las vertientes de suelo herboso. Los aludes de fusión pueden tener tamaño suficiente para enterrarnos. Las orientaciones afectadas por deslizamientos y por fusión son todas y los tamaños de los aludes de mayor alcance serán en el extremo norte de este sector y por encima de los 2200 m, donde el grosor movilizable de nieve es mayor. De noche y madrugada puede haber un cierto rehielo pero las costras que se formen, transforman rápidamente a fusión.

Distribución del manto nivoso

Hay nieve por encima de 1.800-2.000 m en N por encima de 2.100-2.300 m en S. Se alcanzan los 75-95 cm a unos 2.200 m, con frecuentes deflaciones y acumulaciones por encima del nivel del bosque.

Tendencia para las próximas 48-72h

Se mantendrá la situación de fusión. Evolución del peligro: ESTACIONARIO

El próximo boletín será emitido el día 2026-04-20

5 MUY FUERTE	4 FUERTE	3 NOTABLE	2 LIMITADO	1 DÉBIL

EAWS EUROPEAN AVALANCHE WARNING SERVICES

ICGC Institut Cartogràfic i Geològic de Catalunya

Servei Meteorològic de Catalunya

Boletín de peligro de aludes Perafita-Puigpedrós Del 18/04/2026 al 20/04/2026

(Válido fuera pistas de esquí y zonas no controladas)

Notable (3) por encima de los 2200 m Limitado (2) en el resto.

Situación primaria

Deslizamientos basales | **Distribución** | **Tamaño** | **Origen** | **Tendencia**

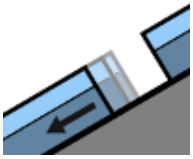

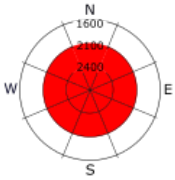

Situación secundaria

Nieve húmeda | **Distribución** | **Tamaño** | **Origen** | **Tendencia**

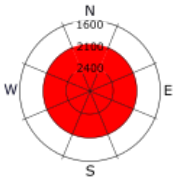

Estado del manto nivoso

Hasta el sábado el manto se mantiene húmedo de día y se encostra de noche y madrugada. Con las lluvias previstas el domingo y el lunes y posibilidad de chubascos el sábado, siempre en forma de agua hasta cotas altas, se prevé un fuerte humedecimiento del manto y que continúe la caída de deslizamientos basales y aludes de fusión. Los deslizamientos basales pueden tener tamaño suficiente para enterrarnos (tamaño 2, mediano) e incluso pueden alcanzar tamaño para tapar un grupo (tamaño 3, grande). Las vertientes más proclives son las vertientes de suelo herboso. Los aludes de fusión pueden tener tamaño suficiente para enterrarnos. Las orientaciones afectadas por deslizamientos y por fusión son todas y los tamaños de los aludes serán de mayor alcance por encima de los 2200 m donde el grosor movilizable de nieve es mayor. De noche y madrugada puede haber un cierto rehielo pero las costras que se formen, transforman rápidamente a fusión.

Distribución del manto nivoso

Hay nieve por encima de 1.900-2.000 m en orientaciones N y de 2.200 m en S. Se alcanzan los 35-75 cm de espesor a unos 2.400 m, con frecuentes deflaciones y acumulaciones por encima del nivel del bosque. Estos valores están algo por debajo de los normales por la época.

Tendencia para las próximas 48-72h

Se mantendrá la situación de fusión. Evolución del peligro: ESTACIONARIO

El próximo boletín será emitido el día 2026-04-20

5 MUY FUERTE	4 FUERTE	3 NOTABLE	2 LIMITADO	1 DÉBIL

EAWS EUROPEAN AVALANCHE WARNING SERVICES

ICGC Institut Cartogràfic i Geològic de Catalunya

Servei Meteorològic de Catalunya

Boletín de peligro de aludes Vessant Nord Cadí-Moixeró Del 18/04/2026 al 20/04/2026

(Válido fuera pistas de esquí y zonas no controladas)

Limitado (2) por encima de 2200 m Débil (1) en el resto.

Situación primaria

Nieve húmeda

Distribución

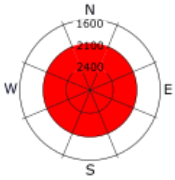

Tamaño

Origen

Tendencia

Estado del manto nivoso

Hasta el sábado el manto se mantiene húmedo de día y se encostra de noche y madrugada. Con las lluvias previstas el domingo y el lunes y posibilidad de chubascos el sábado, siempre en forma de agua hasta cotas altas, se prevé un fuerte humedecimiento del manto y un rehielo nocturno cada vez menos efectivo. Con esta previsión de lluvias y chubascos, son probables las caídas naturales de aludes de fusión, sobre todo en momentos de chubascos y allí donde el manto previamente no estuviera rehelado. Estos aludes son posibles en cualquier orientación y alcanzarán mayor alcance por encima de los 2200 m, donde hay más grosor de manto movilizable; serán de tamaño 1 (pequeño, con capacidad de arrastrarnos) pero puede haber alguna que tenga capacidad de enterrarnos (tamaño 2). Por debajo de los 2200 m no pasarán de tamaño 1. Con el descenso térmico nocturno se prevé un leve encostrante que puede favorecer momentáneamente la estabilización del manto de noche y madrugada.

Distribución del manto nivoso

Hay nieve por encima de 1.900 m en N y de 2.100 m en S. Se alcanzan los 125-145 cm a unos 2.200 m, con frecuentes deflaciones y acumulaciones por encima del nivel del bosque. Estos valores están por encima de los normales para la época.

Tendencia para las próximas 48-72h

Se mantendrá la situación de fusión. Evolución del peligro: ESTACIONARIO

El próximo boletín será emitido el día 2026-04-20

5 MUY FUERTE	4 FUERTE	3 NOTABLE	2 LIMITADO	1 DÉBIL

EAWS EUROPEAN AVALANCHE WARNING SERVICES

ICGC Institut Cartogràfic i Geològic de Catalunya

Servei Meteorològic de Catalunya

Boletín de peligro de aludes Prepirineu
Del 18/04/2026 al 20/04/2026

(Válido fuera pistas de esquí y zonas no controladas)

Limitado (2) por encima de 2200 m Débil (1) en el resto.

Situación primaria

Nieve húmeda

Distribución

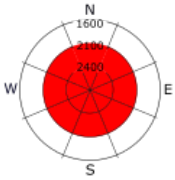

Tamaño

Origen

Tendencia

Estado del manto nivoso

Hasta el sábado el manto se mantiene húmedo de día y se encostra de noche y madrugada. Con las lluvias previstas el domingo y el lunes y posibilidad de chubascos el sábado, siempre en forma de agua hasta cotas altas, se prevé un fuerte humedecimiento del manto y un rehielo nocturno cada vez menos efectivo. Con esta previsión de lluvias y chubascos, son probables las caídas naturales de aludes de fusión, sobre todo en momentos de chubascos y allí donde el manto previamente no estuviera rehelado. Estos aludes son posibles en cualquier orientación y alcanzarán mayor alcance por encima de los 2200 m, donde hay más grosor de manto movilizable; serán de tamaño 1 (pequeño, con capacidad de arrastrarnos) pero puede haber alguna que tenga capacidad de enterrarnos (tamaño 2). Por debajo de los 2200 m no pasarán de tamaño 1. Con él descenso térmico nocturno se prevé un leve encostrante que puede favorecer momentáneamente la estabilización del manto de noche y madrugada.

Distribución del manto nivoso

Hay nieve por encima de 1.900 m en N y de 2.100-2.200 m en S. Se alcanzan los 55-75 cm a unos 2.200 m, con frecuentes deflaciones y acumulaciones por encima del nivel del bosque.

Tendencia para las próximas 48-72h

Se mantendrá la situación de fusión. Evolución del peligro: ESTACIONARIO

El próximo boletín será emitido el día 2026-04-20

5 MUY FUERTE	4 FUERTE	3 NOTABLE	2 LIMITADO	1 DÉBIL

EAWS EUROPEAN AVALANCHE WARNING SERVICES

ICGC Institut Cartogràfic i Geològic de Catalunya

Servei Meteorològic de Catalunya

Boletín de peligro de aludes Ter-Freser
Del 18/04/2026 al 20/04/2026

(Válido fuera pistas de esquí y zonas no controladas)

Notable (3) por encima de los 2200 m Limitado (2) en el resto.

Situación primaria

Deslizamientos basales | **Distribución** | **Tamaño** | **Origen** | **Tendencia**

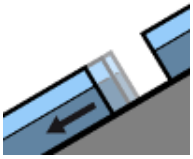

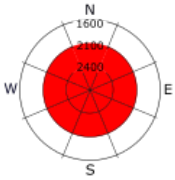

Situación secundaria

Nieve húmeda | **Distribución** | **Tamaño** | **Origen** | **Tendencia**

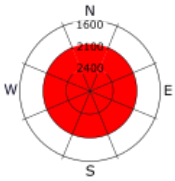

Estado del manto nivoso

Hasta el sábado el manto se mantiene húmedo de día y se encostra de noche y madrugada. Ha habido actividad de deslizamientos basales en la zona en días pasados. Con las lluvias previstas el domingo y el lunes y posibilidad de chubascos el sábado, siempre en forma de agua hasta cotas altas, se prevé un fuerte humedecimiento del manto y que continúe la caída de deslizamientos basales y aludes de fusión. Los deslizamientos pueden tener tamaño para enterrarnos (tamaño 2, mediano) e incluso pueden alcanzar tamaño para tapar un grupo (tamaño 3, grande). Las vertientes más proclives son las vertientes de suelo herboso. Los aludes de fusión pueden tener tamaño suficiente para enterrarnos. Las orientaciones afectadas por deslizamientos y por fusión son todas y los tamaños de los aludes serán de mayor alcance por encima de los 2200 m donde el grosor movilizable de nieve es mayor. De noche y madrugada puede haber un cierto rehielo pero las costras que se formen, transforman rápidamente a fusión.

Distribución del manto nivoso

Hay nieve por encima de 1.900 m en N y de 2.100-2.200 m en S. Los espesores rondan los 45-75 cm a unos 2.200 m, y más de 130-190 cm por encima de 2.400 m, con frecuentes deflaciones y acumulaciones por encima. Estos valores están por encima de la media.

Tendencia para las próximas 48-72h

Se mantendrá la situación de fusión. Evolución del peligro: ESTACIONARIO

El próximo boletín será emitido el día 2026-04-20

5 MUY FUERTE	4 FUERTE	3 NOTABLE	2 LIMITADO	1 DÉBIL

EAWS EUROPEAN AVALANCHE WARNING SERVICES