BUTLLETÍ DEL PERILL D'ALLAUS DEL PRINCIPAT D'ANDORRA

Elaborat el 18/04/2026 16:00
Propera actualització 19/04/2026 a les 16h

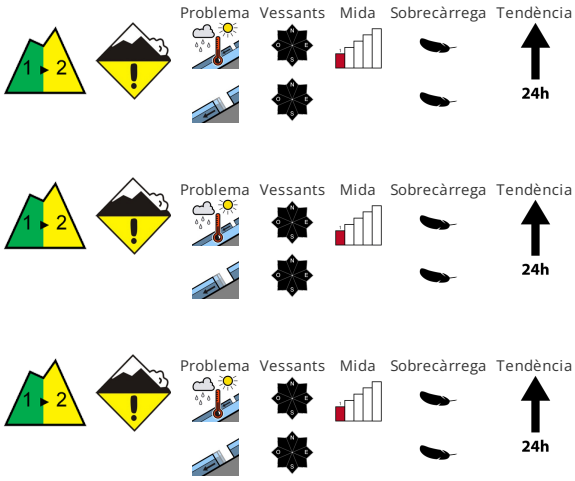

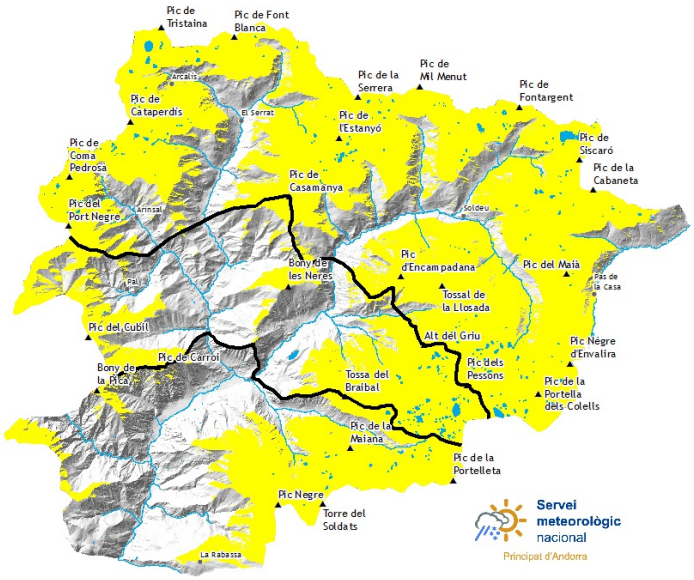

ESTABILITAT DEL MANTELL NIVAL

Després d'una nit serena, al matí predominen en molts sectors condicions favorables, a partir d'aleshores augmentarà el perill d'allaus de neu molt humida i de lliscament basal. A partir del migdia , són probables allaus naturals de neu humida. Aquestes poden desencadenar-se de manera natural i, de manera aïllada, atènyer mida mitjana. A més, són d'esperar allaus de lliscament basal. Els indrets perillosos són fàcils de reconèixer.

QUALITAT DE LA NEU

Les condicions són primaverals. El refredament nocturn serà bo. A causa de la crosta de gel hi ha el perill de relliscar i caure fins i tot en vessants moderadament inclinats. En el transcurs de la jornada la radiació solar causarà una progressiva humidificació del mantell de neu als vessants assolellats. Evitar les zones amb esquerdes de lliscament basal. Les excursions de muntanya han de començar i acabar d'hora.

GRUIXOS DEL MANTELL NIVAL FORA DE PISTA

Zona nord		Gruix neu		
Mantell Nival		1500m	2000m	2500m
N	1800 m	0 cm	150 cm	250 cm
S	2200 m	0 cm	0 cm	180 cm

Zona centre		Gruix neu		
Mantell Nival		1500m	2000m	2500m
N	1800 m	0 cm	120 cm	160 cm
S	2200 m	0 cm	0 cm	120 cm

Zona sud		Gruix neu		
Mantell Nival		1500m	2000m	2500m
N	1800 m	0 cm	120 cm	160 cm
S	2200 m	0 cm	0 cm	120 cm

Govern d'Andorra

Aquest butlletí ha estat elaborat seguint les normes i recomanacions de l'**European Avalanche Warning Services**, del qual el **Servei meteorològic Nacional** n'és membre

BUTLLETÍ DEL PERILL D'ALLAUS DEL PRINCIPAT D'ANDORRA

Servei meteorològic nacional
Principat d'Andorra

Informació detallada per espais naturals protegits

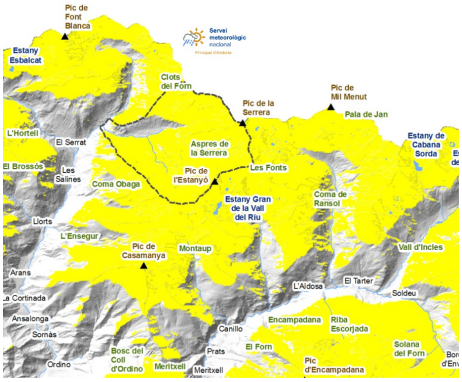

SORTENY

Tot i les febles precipitacions de la tarda de dissabte, no s´espera que canviïn les condicions de la neu. Amb les pluges de diumenge, si que es preveu un cicle d´activitat d´allaus de fons més important. Els vessants nord encara tenen gruixos importants, però als vessants sud la neu contínua s´ha d´anar a buscar per sobre dels 2.200 metres. L´accés al refugi s´ha de fer a peu, i ja no es pot fer el Planell del Quer amb esquís. Per passar cap a Rialb s´hi ha d´anar pel Forn.

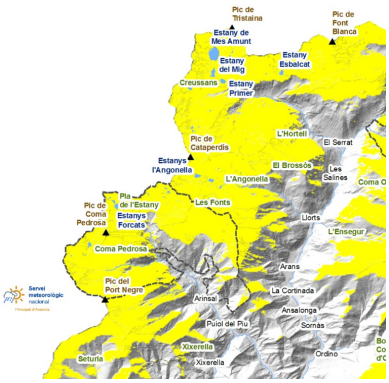

COMAPEDROSA

La neu s´humidificarà als vessants sud i cotes mitges, però al matí la trobarem ben dura. Als vessants més inclinats continuaran baixant purgues de neu humida. A primera hora, amb la neu encara dura serà més difícil i tècnic circular.

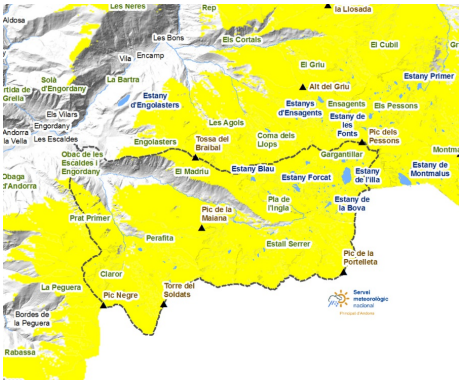

MADRIU-PERAFITA-CLAROR

Durant el dia esperem purgues als vessants sud a causa de la calor. A les parts més planes dels circs, sovint encara és més ràpida la neu marró que la blanca. A partir de l´Estall Serrer en avall, ja no queda neu contínua.

Govern d'Andorra

EAWS
EUROPEAN AVALANCHE WARNING SERVICES

Aquest butlletí ha estat elaborat seguint les normes i recomanacions de l'**European Avalanche Warning Services**, del qual el **Servei meteorològic Nacional** n'és membre

BUTLLETÍ DEL PERILL D'ALLAUS DEL PRINCIPAT D'ANDORRA

Servei meteorològic nacional
Principat d'Andorra

Gruixos de neu nova dels darrers dies (de les últimes 24h mesurat a les 06:00h UTC)

	14/04/2026	15/04/2026	16/04/2026	17/04/2026
FEDA (Central)	0 cm	0 cm	0 cm	0 cm
Engolasters - FEDA	0 cm	0 cm	0 cm	0 cm
Bony de les Neres	0 cm	0 cm	0 cm	0 cm
Sorteny	0 cm	0 cm	0 cm	0 cm
Les Fonts d'Arinsal	0 cm	0 cm	0 cm	0 cm
Aixàs	0 cm	0 cm	0 cm	0 cm
Perafita	0 cm	0 cm	0 cm	0 cm
Tossa Espiolets	0 cm	0 cm	0 cm	0 cm
Grau Roig - FEDA	0 cm	0 cm	0 cm	0 cm
Fontverd	0 cm	0 cm	0 cm	1 cm
Coll Ordino	0 cm	0 cm	0 cm	0 cm
Ransol - FEDA	0 cm	0 cm	0 cm	0 cm
Setúria	0 cm	0 cm	0 cm	0 cm
Caborreu	0 cm	0 cm	0 cm	0 cm
La Solana	0 cm	0 cm	0 cm	0 cm
Coll Pa	0 cm	0 cm	0 cm	0 cm
Envalira Antenes	0 cm	0 cm	0 cm	0 cm
Vall del Riu FEDA	1 cm	0 cm	0 cm	0 cm