Bulletin d'estimation du risque d'avalanche
(valable en dehors des pistes balisées et ouvertes)

MASSIF : Aure Louron

Rédigé le samedi 18 avril 2026 à 16h

Estimation des risques pour le : DIMANCHE 19 AVRIL

WEEKEND MARQUÉ PAR L'ÉVOLUTION EN PROFONDEUR DE L'HUMIDIFICATION

2

2

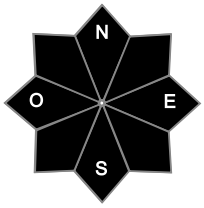

Humidification

Indice de risque limité.

Départs spontanés : Avalanches de fond probables, avalanches de neige humide.

Déclenchements provoqués : Limités au plus haut du massif, rares

Indices de risque : 5 très fort - 4 fort - 3 marqué - 2 limité - 1 faible -- En noir : les pentes les plus dangereuses

Stabilité du manteau neigeux

Situation avalancheuse typique : avalanches de fond — neige humide

Départs spontanés :
L'activité avalancheuse si faible la nuit, peut toutefois présenter de rares départs de **grandes avalanches de fond à cassure linéaire**, partant souvent depuis une fissure déjà ouverte. Elles sont plus probables en versants Nord à Nord-est où les accumulations sont plus importantes et au fil de l'ensoleillement mais une grande, voire très grande avalanche peut advenir en versant sud au vu de l'enneigement conséquent sur le massif. Des avalanches petites à moyennes seront de plus en plus fréquentes en pentes raides dès 2100 m en sud et 1800 m en nord, au fil de l'ensoleillement et en toutes expositions.

Déclenchements provoqués :
Dans les secteurs nord au-dessus de **2700 m**, de **rares plaques** peuvent encore avoir échappé à l'humidification mais sont devenues assez difficilement déclenchables par tassement.
Le passage d'un skieur dans la neige très humide peut favoriser un départ ponctuel de taille petite voire moyenne.

Autres :
Avec la douceur ambiante, les corniches et ponts de neige sont de plus en plus fragiles.

Qualité de la neige

Enneigement : L'enneigement est plutôt bon pour la saison, débutant vers 1650 m en nord, et 2000 m environ en sud. Cette limite d'enneigement en sud tend à remonter progressivement avec la douceur ambiante et le soleil.
État de la neige : Absence de regel ou rare regel au lever du jour au-dessus de 2600 m, la neige s'humidifie ensuite rapidement, avec des enfoncements importants en expositions nord. Neige dense en sud au lever du jour mais généralement non croutée, devenant vite printanière, très humide au soleil.

Aperçu météo pour le dimanche 19 avril

Nuit voilée avant une journée de dimanche où les cumulus apportent des averses dès le matin, plus probables et localement orageuses en après-midi

	nuit	matin	après-midi	soir
Pluie-Neige	2 800 m	2 700 m	2 900 m	2 900 m
Iso 0 °C	3 200 m	3 100 m	3 300 m	3 300 m
Vent 1500 m	10 km/h	10 km/h	20 km/h	15 km/h
Vent 3000 m	20 km/h	20 km/h	30 km/h	25 km/h

Épaisseur de neige hors-piste

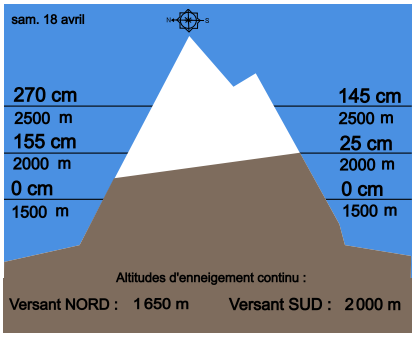

Précipitations à 1800 m

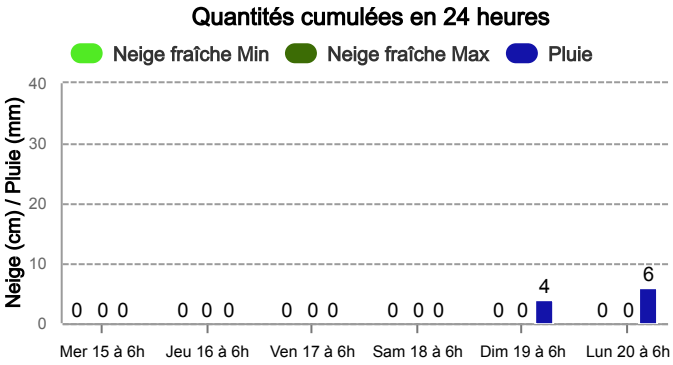

Tendance du lundi 20 avril

2

Indice de risque limité

Risque d'avalanches de fond maintenu avec la douceur.

Pour consulter la vigilance en cours, veuillez vous rendre sur le site https://vigilance.meteofrance.fr/fr

Météo-France - 73 avenue de Paris, 94165 Saint-Mandé cedex - Contact : contact@meteo.fr

Rédigé par Météo-France avec la contribution des observateurs du réseau nivo-météorologiques. Partenariat : ANMSM (Maires de Stations de Montagne), DSF (Domaines Skiables de France), ADSP (Directeurs de Pistes et de la Sécurité des Stations de Sports d'Hiver) et autres acteurs de la montagne.

Bulletin neige & avalanches par téléphone au
0 892 68 10 20 Service 0,35 € / min + prix appel

RÉPUBLIQUE FRANÇAISE
Liberté Égalité Fraternité

METEO FRANCE
À VOS CÔTÉS, DANS UN CLIMAT QUI CHANGE

Bulletin d'estimation du risque d'avalanche

(valable en dehors des pistes balisées et ouvertes)

MASSIF : Aure Louron

Rédigé le samedi 18 avril 2026 à 16h

Conditions nivo-météo des 7 derniers jours

	dim. 12/04				lun. 13/04				mar. 14/04				mer. 15/04				jeu. 16/04				ven. 17/04				sam. 18/04			
	03h	09h	15h	21h	03h	09h	15h	21h	03h	09h	15h	21h	03h	09h	15h	21h	03h	09h	15h	21h	03h	09h	15h	21h	03h	09h	15h	21h
Météo																												
Vent (km/h)	30	25	20	30	55	45	35	30	60	60	50	35	45	20	25	25	20	15	15	15	15	10	10	10	10	15	20	15
à 3000m																												
Vent (km/h)	15	10	10	10	15	15	10	5	10	15	25	5	5	10	20	5	5	5	5	5	5	5	5	5	5	10	15	10
à 1500m																												

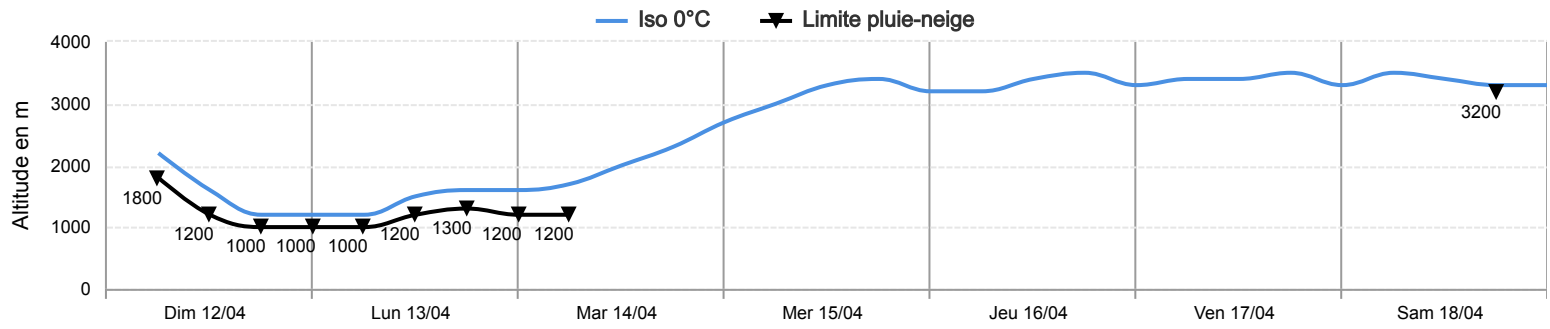

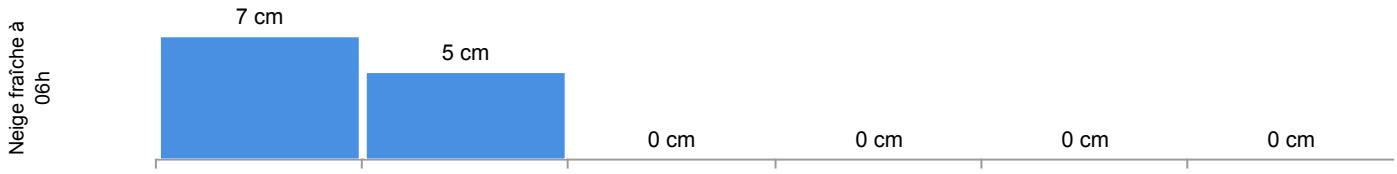

Risque d'avalanche	dim. 12/04	lun. 13/04	mar. 14/04	mer. 15/04	jeu. 16/04	ven. 17/04	sam. 18/04
	2	3	2	2	2	2	2

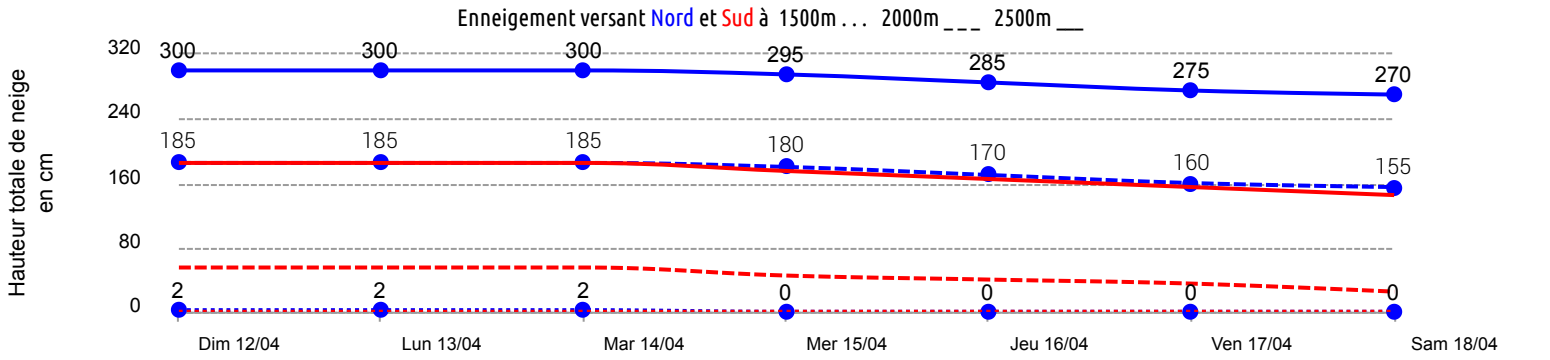

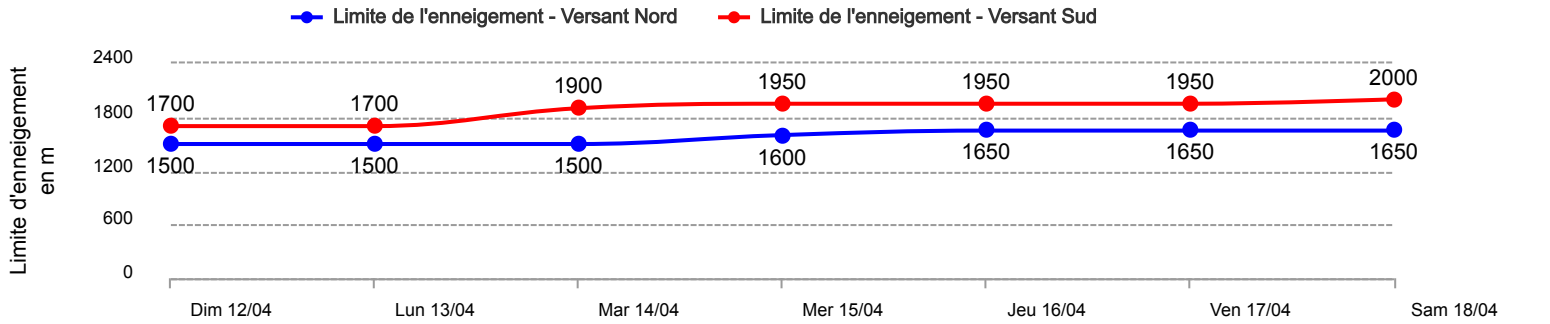

Pour consulter la vigilance en cours, veuillez vous rendre sur le site https://vigilance.meteofrance.fr/fr

Météo-France - 73 avenue de Paris, 94165 Saint-Mandé cedex - Contact : contact@meteo.fr

Rédigé par Météo-France avec la contribution des observateurs du réseau nivo-météorologiques. Partenariat : ANMSM (Maires de Stations de Montagne), DSF (Domaines Skiables de France), ADSP (Directeurs de Pistes et de la Sécurité des Stations de Sports d'Hiver) et autres acteurs de la montagne.

Bulletin neige & avalanches par téléphone au

0 892 68 10 20 Service 0,35 € / min + prix appel