Bulletin d'estimation du risque d'avalanche

(valable en dehors des pistes balisées et ouvertes)

MASSIF : Cerdagne Canigou

Rédigé le samedi 18 avril 2026 à 16h

Estimation des risques pour le : DIMANCHE 19 AVRIL

POURSUITE DE L'HUMIDIFICATION

2

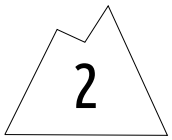

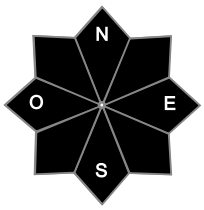

Indice de risque limité.

Départs spontanés : Avalanches de surface et avalanches de fond en neige humide

Déclenchements provoqués : Départs ponctuels en neige humide

Indices de risque : 5 très fort - 4 fort - 3 marqué - 2 limité - 1 faible -- En noir : les pentes les plus dangereuses

Stabilité du manteau neigeux

Situation avalancheuse typique : neige humide avalanches de fond

Départs spontanés :

- Regel moins efficace que les jours précédents (à cause des nuages), favorisant des départs ponctuels d'**avalanches en neige humide** de taille petite à moyenne dès le matin. Ils concernent dans un premier temps les pentes nord-est à sud-est puis se généralisent à l'ensemble des versants avec les averses de pluie prévues l'après-midi.
- En altitude, avec l'humidification qui gagne en profondeur, des **avalanches de glissement** emportant l'ensemble du manteau neigeux sont possibles en toutes orientations (des fissures/reptations et avalanches de glissement nous ont en effet été signalées récemment). Elles seront de taille moyenne, voire plus rarement grandes dans les zones de plus fortes accumulations.

Déclenchements provoqués :

- Un skieur coupant une pente raide déjà humidifiée pourra favoriser un départ ponctuel de taille petite à plus rarement moyenne.
- Au-dessus de 2600/2700m, dans de rares pentes à l'ombre, quelques structures de plaques sont possiblement encore en place, mais deviennent de plus en plus difficilement déclenchables

Autre : Des corniches encore imposantes sont en place et sont susceptibles de céder spontanément avec le redoux, tout comme les ponts de neige sur les torrents bien alimentés par la fonte en cours.

Qualité de la neige

Enneigement :

L'enneigement dans nos massifs reste encore très bon pour la saison, un des meilleurs de ces 30 dernières années. Avec le redoux et le soleil, la limite skiable remonte progressivement surtout en sud. Elle est encore au mieux vers 1700 m en nord et 2000 m en sud. On trouve ensuite rapidement une bonne épaisseur de neige dans les combres, qui dépasse souvent 1m dès 2000/2200 m, et les 2m50 dès 2500m.

Qualité de la neige :

Au petit matin, le regel aura été médiocre à cause des nuages de la nuit. L'humidification reprend rapidement en matinée, et se renforce l'après-midi avec les averses. La surface du manteau est majoritairement constituée de neige ocre, chargée en poussières sahariennes. La neige blanche, sèche et légère devient difficile à trouver, à part peut être dans quelques versants raides à l'ombre des plus hauts sommets. Les cols et crêtes ouest à nord-ouest sont généralement moins garnis en neige voire pelés.

Aperçu météo pour le dimanche 19 avril

	nuit	matin	après-midi	soir

Nuageux et averses localement orageuses l'après-midi, dans la douceur

Pluie-Neige		2700 m	2800 m	
Iso 0 °C	3300 m	3100 m	3100 m	3200 m
Vent 2000 m	↘ 15 km/h	↗ 15 km/h	↗ 30 km/h	↗ 15 km/h
Vent 3000 m	↙ 20 km/h	↗ 25 km/h	→ 35 km/h	→ 20 km/h

Épaisseur de neige hors-piste

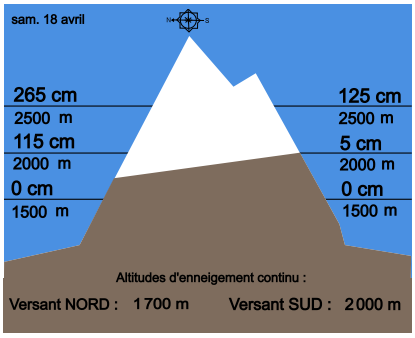

Précipitations à 1800 m

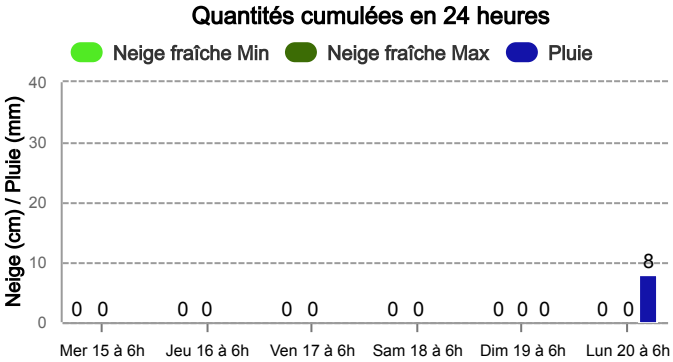

Tendance du lundi 20 avril

2

Indice de risque limité

Peu de changement à attendre avec le même type de temps prévu lundi.

Pour consulter la vigilance en cours, veuillez vous rendre sur le site https://vigilance.meteofrance.fr/fr

Météo-France - 73 avenue de Paris, 94165 Saint-Mandé cedex - Contact : contact@meteo.fr

Rédigé par Météo-France avec la contribution des observateurs du réseau nivo-météorologiques. Partenariat : ANMSM (Maires de Stations de Montagne), DSF (Domaines Skiables de France), ADSP (Directeurs de Pistes et de la Sécurité des Stations de Sports d'Hiver) et autres acteurs de la montagne.

Bulletin neige & avalanches par téléphone au

0 892 68 10 20 Service 0,35 € / min + prix appel

RÉPUBLIQUE FRANÇAISE
Liberté Égalité Fraternité

METEO FRANCE
À VOS CÔTÉS, DANS UN CLIMAT QUI CHANGE

Bulletin d'estimation du risque d'avalanche

(valable en dehors des pistes balisées et ouvertes)

MASSIF : Cerdagne Canigou

Rédigé le samedi 18 avril 2026 à 16h

Conditions nivo-météo des 7 derniers jours

	dim. 12/04				lun. 13/04				mar. 14/04				mer. 15/04				jeu. 16/04				ven. 17/04				sam. 18/04			
	03h	09h	15h	21h	03h	09h	15h	21h	03h	09h	15h	21h	03h	09h	15h	21h	03h	09h	15h	21h	03h	09h	15h	21h	03h	09h	15h	21h
Météo																												
Vent (km/h)	40	30	30	20	50	50	55	55	50	50	50	45	35	25	25	20	20	20	25	20	20	20	15	15	15	15	20	15
à 3000m																												
Vent (km/h)	25	20	20	15	35	30	30	25	25	25	25	20	20	15	15	10	10	10	15	10	10	10	10	10	10	10	15	10
à 2000m																												

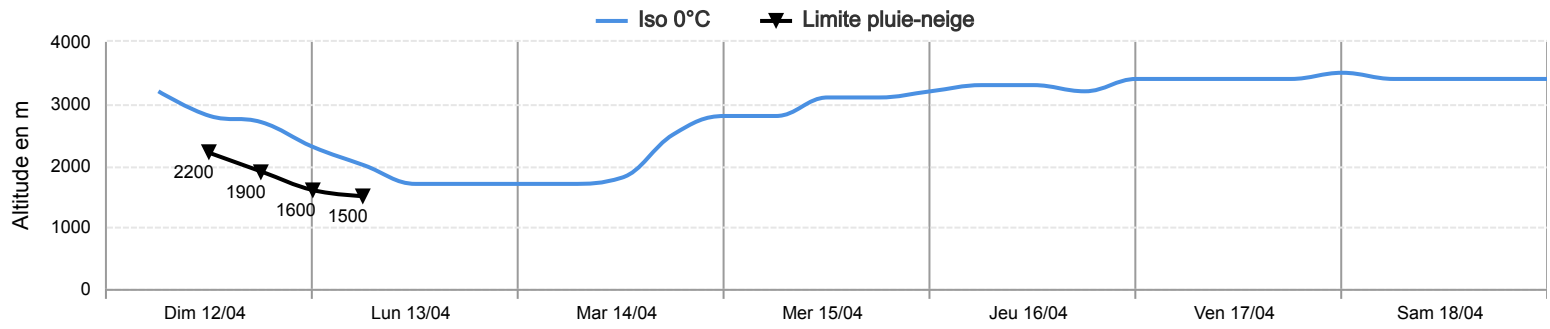

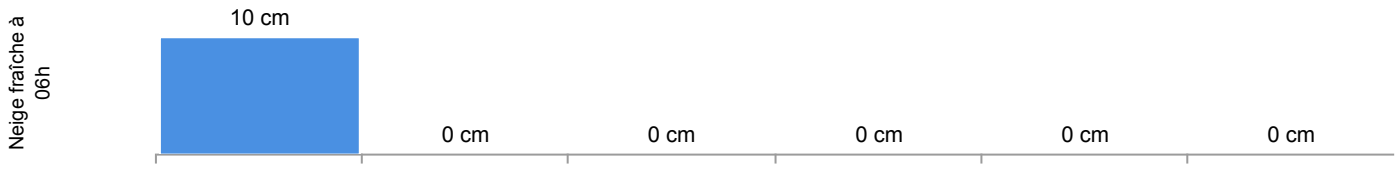

Risque d'avalanche	dim. 12/04	lun. 13/04	mar. 14/04	mer. 15/04	jeu. 16/04	ven. 17/04	sam. 18/04
	2	2	2	2	2	2	2

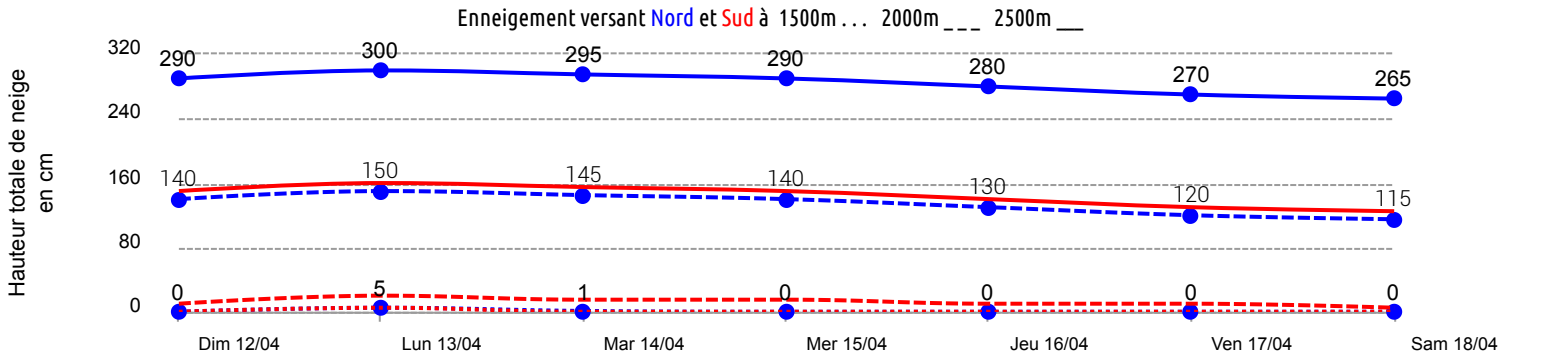

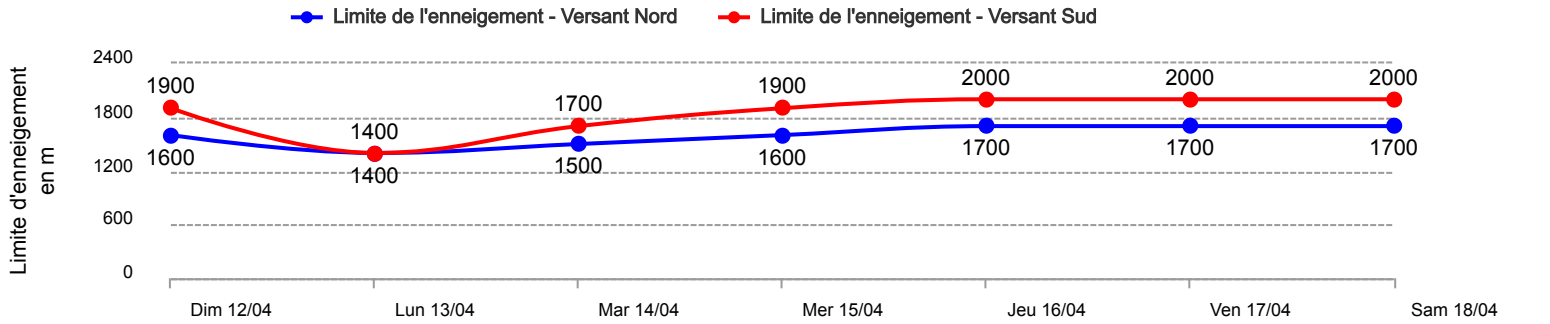

Pour consulter la vigilance en cours, veuillez vous rendre sur le site https://vigilance.meteofrance.fr/fr

Météo-France - 73 avenue de Paris, 94165 Saint-Mandé cedex - Contact : contact@meteo.fr

Rédigé par Météo-France avec la contribution des observateurs du réseau nivo-météorologiques. Partenariat : ANMSM (Maires de Stations de Montagne), DSF (Domaines Skiables de France), ADSP (Directeurs de Pistes et de la Sécurité des Stations de Sports d'Hiver) et autres acteurs de la montagne.

Bulletin neige & avalanches par téléphone au

0 892 68 10 20 Service 0,35 € / min + prix appel