Bulletin d'estimation du risque d'avalanche

(valable en dehors des pistes balisées et ouvertes)

MASSIF : Cinto Rotondo

Rédigé le samedi 18 avril 2026 à 16h

Estimation des risques pour le : DIMANCHE 19 AVRIL

MANTEAU NEIGEUX PRINTANIER

2

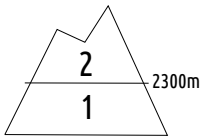

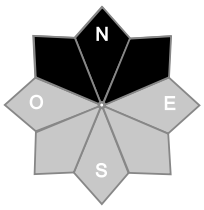

Au-dessus de 2300m indice de risque limité, plus bas indice faible.

Départs spontanés : Coulées et avalanches de neige humide en journée dans les pentes raides

Déclenchements provoqués : Peu probables

Indices de risque : 5 très fort - 4 fort - 3 marqué - 2 limité - 1 faible -- En noir : les pentes les plus dangereuses

Stabilité du manteau neigeux

Situation avalancheuse typique : neige humide

Départs spontanés : Le manteau neigeux est bien humidifié et bien tassé jusqu'à 2300 m d'altitude. En journée, sous l'effet de la douceur et de l'ensoleillement, des coulées ou avalanches de neige humide sont attendues dans les pentes raides et ensoleillées. Des avalanches de taille moyenne peuvent se produire au-dessus de 2300 m, notamment dans les pentes orientées Nord.. À noter également qu'une avalanche de fond n'est pas exclue sur les dalles rocheuses (apparition de fissures de reptation).
Déclenchements provoqués : Peu probables. Un randonneur peut provoquer un départ superficiel sous les skis, en coupant une pente raide très humidifiée.
Autres : Présence de nombreuses corniches, susceptibles de rompre à cause des conditions printanières. Rares surfaces glacées au-dessus de 2300 m.

Qualité de la neige

Qualification de l'enneigement : L'enneigement est encore très bon pour la saison. Sur la Maniccia, à 2400 m d'altitude dans le massif du Rotondo, on relève 2m76 de hauteur de neige totale.
Limite d'enneigement skiable : vers 1600 à 1700 m en Nord, 1800 à 1900 m en Sud.
État de la neige : Regel nocturne correct en altitude, inexistant en dessous de 1800 à 2000 m. Rapide humidification en matinée. En moyenne montagne, la neige est très humide, généralement colorée par le sable. Elle devient dense et portante à partir de 1800 m, légèrement revenue en versants Sud dans la journée. Dans les pentes Nord et près des crêtes, on trouve des surfaces plus dures. Au-dessus de 2300 m, présence d'une couche de neige récente, entre 10 et 20 cm, devenant lourde et humide. Elle peut rester sèche dans les pentes ombragées au-dessus de 2500 m. Rares surfaces glacées sur les plus hauts sommets.

Aperçu météo pour le dimanche 19 avril

	nuit	matin	après-midi	soir
Averses possibles l'après-midi.				
Pluie-Neige				
Iso 0 °C	3 200 m	3 200 m	3 200 m	3 200 m
Vent 1500 m	↘ 5 km/h	↗ 20 km/h	↗ 30 km/h	→ 25 km/h
Vent 3000 m	↘ 10 km/h	→ 20 km/h	→ 30 km/h	→ 30 km/h

Épaisseur de neige hors-piste

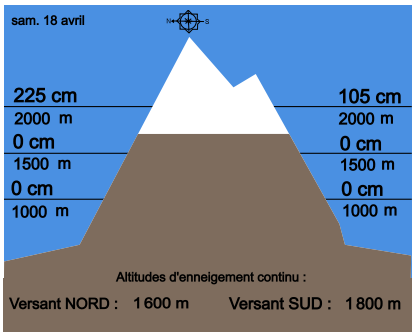

Précipitations à 1800 m

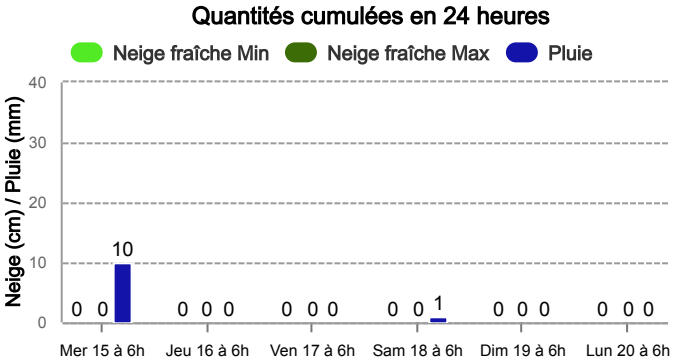

Tendance du lundi 20 avril

2

Indice de risque limité

Pas d'évolution notable en termes de risque.

Pour consulter la vigilance en cours, veuillez vous rendre sur le site https://vigilance.meteofrance.fr/fr

Météo-France - 73 avenue de Paris, 94165 Saint-Mandé cedex - Contact : contact@meteo.fr

Rédigé par Météo-France avec la contribution des observateurs du réseau nivo-météorologiques. Partenariat : ANMSM (Maires de Stations de Montagne), DSF (Domaines Skiables de France), ADSP (Directeurs de Pistes et de la Sécurité des Stations de Sports d'Hiver) et autres acteurs de la montagne.

Bulletin neige & avalanches par téléphone au 0 892 68 10 20 Service 0,35 € / min + prix appel

Bulletin d'estimation du risque d'avalanche

(valable en dehors des pistes balisées et ouvertes)

MASSIF : Cinto Rotondo

Rédigé le samedi 18 avril 2026 à 16h

Conditions nivo-météo des 7 derniers jours

	dim. 12/04				lun. 13/04				mar. 14/04				mer. 15/04				jeu. 16/04				ven. 17/04				sam. 18/04			
	03h	09h	15h	21h	03h	09h	15h	21h	03h	09h	15h	21h	03h	09h	15h	21h	03h	09h	15h	21h	03h	09h	15h	21h	03h	09h	15h	21h
Météo																												
Vent (km/h)	10	25	20	30	80	50	25	15	15	15	20	30	30	30	25	30	30	20	20	20	20	15	15	20	15	15	15	20
à 3000m																												
Vent (km/h)	10	25	20	25	45	35	20	10	15	15	20	25	30	30	25	20	20	15	10	20	15	15	10	15	10	15	10	5
à 1500m																												

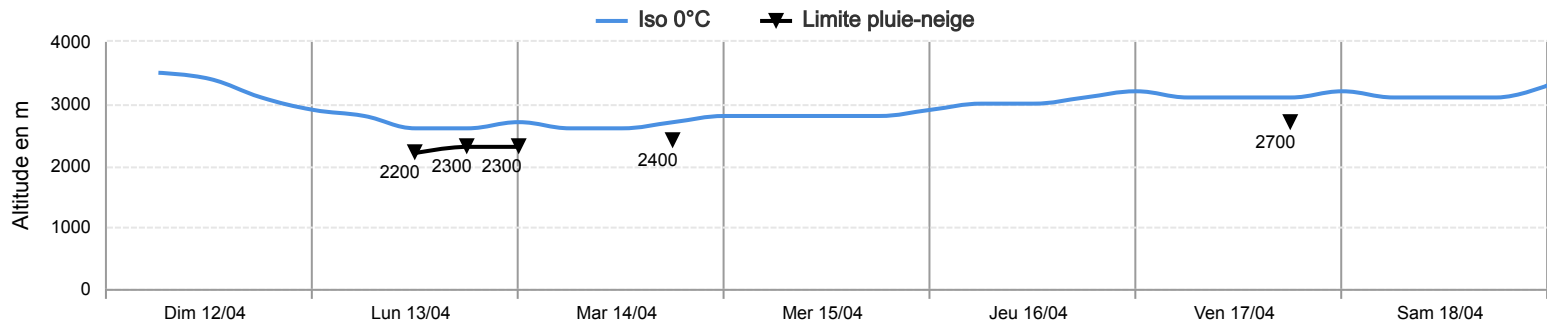

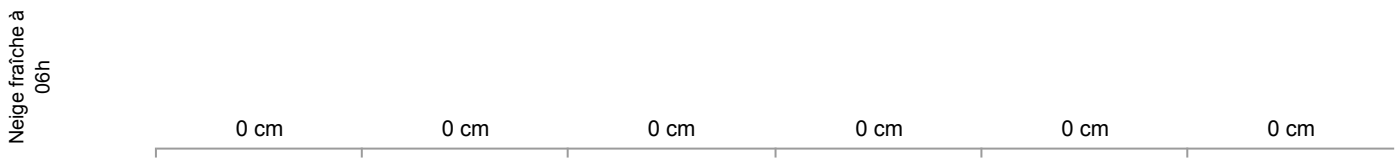

Risque d'avalanche	dim. 12/04	lun. 13/04	mar. 14/04	mer. 15/04	jeu. 16/04	ven. 17/04	sam. 18/04
	2	2	3	3	2	2	2

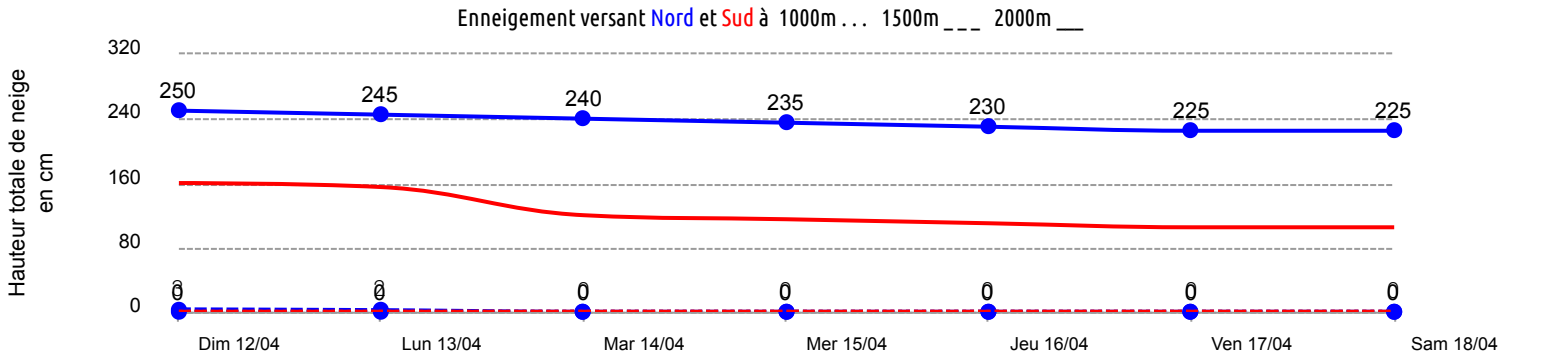

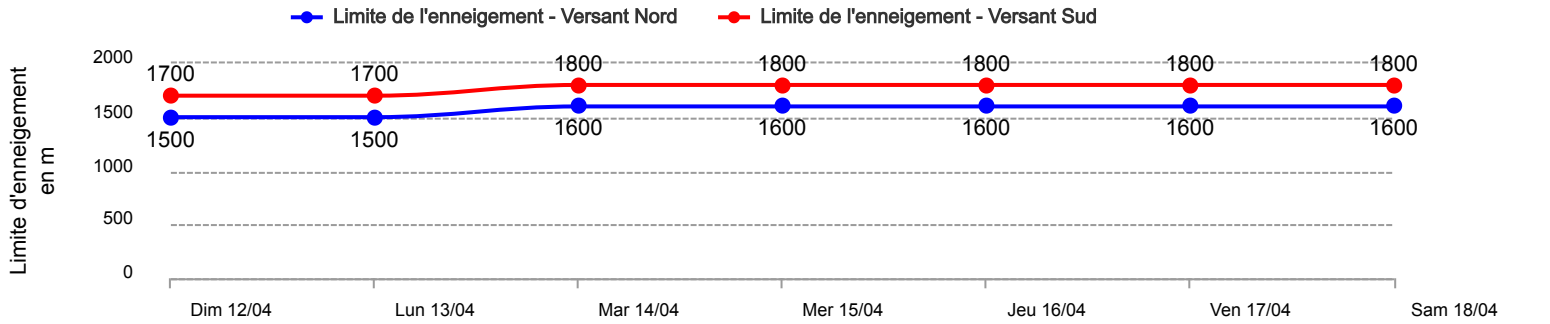

Pour consulter la vigilance en cours, veuillez vous rendre sur le site https://vigilance.meteofrance.fr/fr

Météo-France - 73 avenue de Paris, 94165 Saint-Mandé cedex - Contact : contact@meteo.fr

Rédigé par Météo-France avec la contribution des observateurs du réseau nivo-météorologiques. Partenariat : ANMSM (Maires de Stations de Montagne), DSF (Domaines Skiables de France), ADSP (Directeurs de Pistes et de la Sécurité des Stations de Sports d'Hiver) et autres acteurs de la montagne.

Bulletin neige & avalanches par téléphone au

0 892 68 10 20 Service 0,35 € / min + prix appel