BUTLLETÍ DEL PERILL D'ALLAUS DEL PRINCIPAT D'ANDORRA

Elaborado el 19/04/2026 07:54
Proxima actualización 19/04/2026 a las 16h

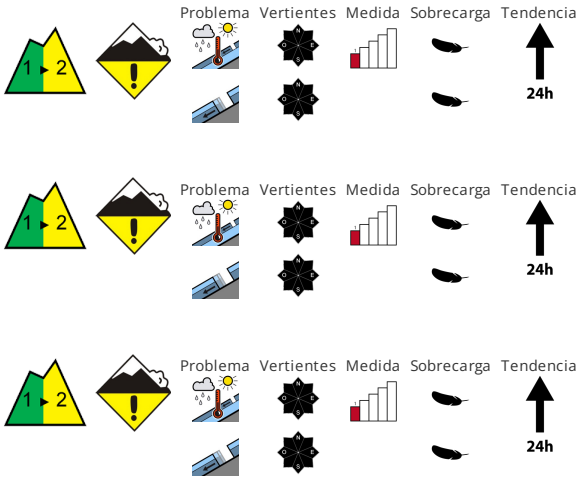

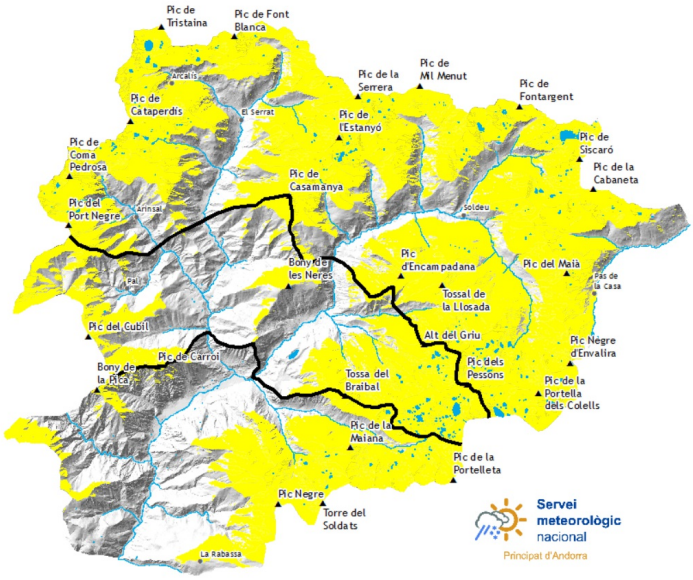

CALIDAD DE LA NIEVE

Después de una noche serena, por la mañana reinan condiciones favorables, a partir de entonces aumentará el peligro de aludes de nieve muy húmeda y de deslizamiento basal. A partir del mediodía , son probables avalanchas naturales de nieve húmeda. Estos pueden desencadenarse de manera natural y, de manera aislada, alcanzar un tamaño mediano. Además son de esperar aludes de deslizamiento basal. Los lugares peligrosos son resultan fáciles de reconocer.

ESTABILIDAD DEL MANTO NIVOSO

Las condiciones son primaverales. El enfriamiento nocturno ha sido en muchos sectores reducido. Debido a la costra de hielo hay el peligro de resbalar y caer incluso en laderas moderadamente inclinadas. En el transcurso de la jornada la radiación solar causará una progresiva humidificación del manto de nieve en las laderas solanas. Evitar las zonas con grietas de deslizamiento basal. Las excursiones de montaña deben comenzar y acabar temprano. Durante la tarde caerá lluvia hasta por encima de los 3000 m.

ESPESORES DEL MANTO NIVOSO FUERA DE PISTA

Zona norte		Espesor nieve		
Manto Nival		1500m	2000m	2500m
N	1800 m	0 cm	150 cm	250 cm
S	2200 m	0 cm	0 cm	180 cm

zona centro		Espesor nieve		
Manto Nival		1500m	2000m	2500m
N	1800 m	0 cm	120 cm	160 cm
S	2200 m	0 cm	0 cm	120 cm

Zona sur		Espesor nieve		
Manto Nival		1500m	2000m	2500m
N	1800 m	0 cm	120 cm	160 cm
S	2200 m	0 cm	0 cm	120 cm

Govern d'Andorra

Aquest butlletí ha estat elaborat seguint les normes i recomanacions de l'**European Avalanche Warning Services**, del qual el **Servei meteorològic Nacional** n'és membre

Información detallada por espacios naturales protegidos

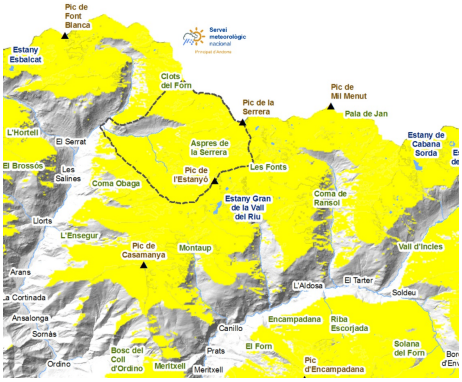

SORTENY

Pese a las débiles precipitaciones de la tarde del sábado, no se espera que cambien las condiciones de la nieve. Con las lluvias del domingo, se prevé un ciclo de actividad de aludes de fondo más importante. Las vertientes norte todavía tienen grosores importantes, pero en las vertientes sur la nieve continua se debe ir a buscar por encima de los 2.200 metros. El acceso al refugio debe realizarse a pie, y ya no se puede hacer el Planell del Quer con esquís. Para pasar hacia Rialb hay que ir por el Forn.

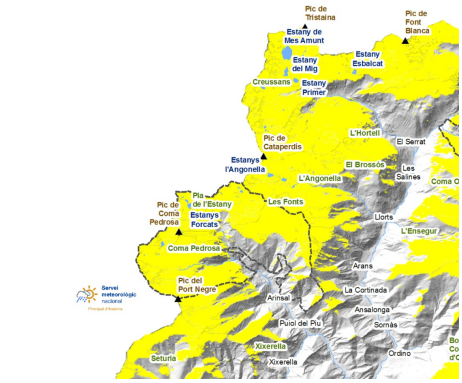

COMAPEDROSA

La nieve se humidificará en las vertientes sur y cotas medias, pero por la mañana la encontraremos muy dura. En las vertientes más inclinadas continuarán bajando purgas de nieve húmeda. A primera hora, con la nieve dura todavía será más difícil y técnico circular.

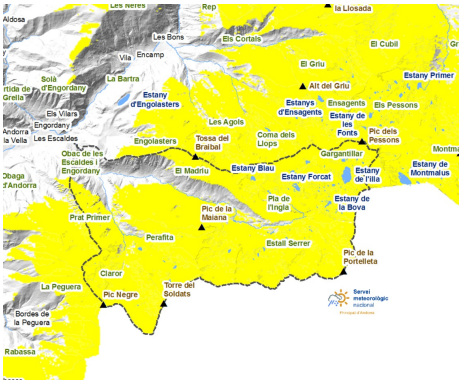

MADRIU-PERAFITA-CLAROR

Durante el día esperamos purgas en las vertientes sur a causa del calor. En las partes más llanas de los circos, a menudo es aún más rápida la nieve marrón que la blanca. A partir del Estall Serrer hacia abajo, ya no queda nieve continua.

BUTLLETÍ DEL PERILL D'ALLAUS DEL PRINCIPAT D'ANDORRA

Servei meteorològic nacional
Principat d'Andorra

Espesores de nieve nueva de los últimos días (de las ultimas 24h mesurado a las 06:00h UTC)

	15/04/2026	16/04/2026	17/04/2026	18/04/2026
FEDA (Central)	0 cm	0 cm	0 cm	0 cm
Engolasters - FEDA	0 cm	0 cm	0 cm	0 cm
Bony de les Neres	0 cm	0 cm	0 cm	0 cm
Sorteny	0 cm	0 cm	0 cm	0 cm
Les Fonts d'Arinsal	0 cm	0 cm	0 cm	0 cm
Aixàs	0 cm	0 cm	0 cm	0 cm
Perafita	0 cm	0 cm	0 cm	0 cm
Tossa Espiolets	0 cm	0 cm	0 cm	0 cm
Grau Roig - FEDA	0 cm	0 cm	0 cm	0 cm
Fontverd	0 cm	0 cm	1 cm	0 cm
Coll Ordino	0 cm	0 cm	0 cm	0 cm
Ransol - FEDA	0 cm	0 cm	0 cm	0 cm
Setúria	0 cm	0 cm	0 cm	0 cm
Caborreu	0 cm	0 cm	0 cm	0 cm
La Solana	0 cm	0 cm	0 cm	0 cm
Coll Pa	0 cm	0 cm	0 cm	0 cm
Envalira Antenes	0 cm	0 cm	0 cm	0 cm
Vall del Riu FEDA	0 cm	0 cm	0 cm	0 cm