BUTLLETÍ DEL PERILL D'ALLAUS DEL PRINCIPAT D'ANDORRA

Servei meteorològic nacional
Principat d'Andorra

Préparé le 19/04/2026 07:54
Prochaine mise à jour le 19/04/2026 à 16h

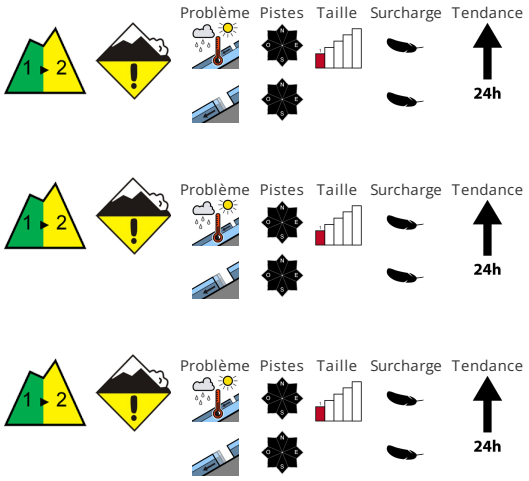

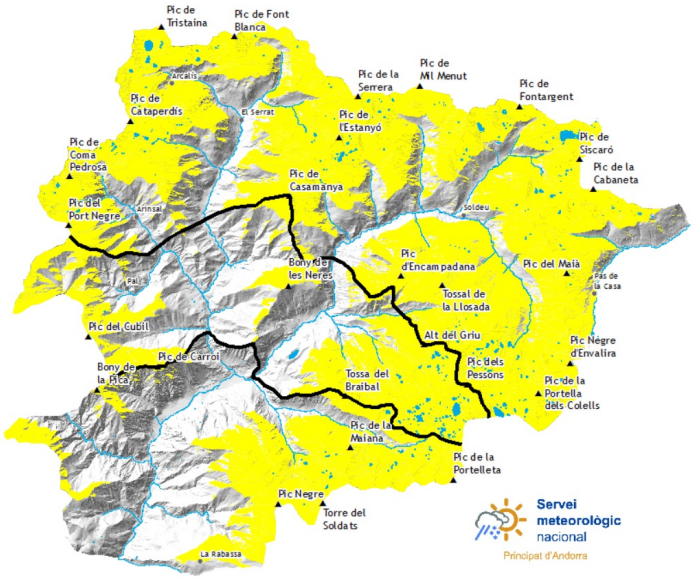

STABILITÉ DU MANTEAU NEIGEUX

Après une nuit claire, il règne le matin des conditions favorables généralisées , puis le danger d'avalanches mouillées et de glissement augmente.. Des avalanches spontanées humides sont ils sont à attendre à partir de midi. Explication: celles-ci ne peut signifier que celles-ci avalanches peuvent se déclencher spontanément et atteindre une taille moyenne de manière isolée.. En outre, des avalanches de glissement sont à attendre.. Les endroits dangereux sont facilement identifiables..

QUALITÈ DE LA NEIGE

Les conditions sont printanières. Le rayonnement nocturne était généralement réduit.. Sur la croûte glacée il existe également dans des terrains moyennement raides un risque de chute.. Le rayonnement solaire en cours de journée entraîne sur les pentes au soleil une humidification croissante du manteau neigeux. Les zones présentant des fissures de glissement doivent être évitées.. Les randonnées devraient être commencées et terminées tôt.. L'après-midi il tombera de la pluie jusqu'au-dessus de 3000 m.

EPAISSEUR DE NEIGE HORS PISTE

Zone nord		Epaisseur de neige		
Nival manteau		1500m	2000m	2500m
N	1800 m	0 cm	150 cm	250 cm
S	2200 m	0 cm	0 cm	180 cm

Zone centre		Epaisseur de neige		
Nival manteau		1500m	2000m	2500m
N	1800 m	0 cm	120 cm	160 cm
S	2200 m	0 cm	0 cm	120 cm

Zone sud		Epaisseur de neige		
Nival manteau		1500m	2000m	2500m
N	1800 m	0 cm	120 cm	160 cm
S	2200 m	0 cm	0 cm	120 cm

Govern d'Andorra

EAWS
EUROPEAN AVALANCHE WARNING SERVICES

Aquest butlletí ha estat elaborat seguint les normes i recomanacions de l'**European Avalanche Warning Services**, del qual el **Servei meteorològic Nacional** n'és membre

Des informations détaillées par espace naturel protégé

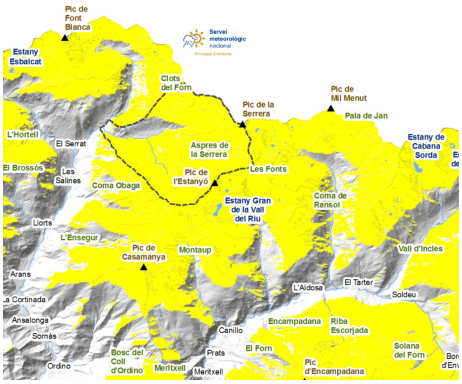

SORTENY

Malgré les légères précipitations de samedi après-midi, les conditions d'enneigement ne devraient pas changer. Avec les pluies de dimanche, on s'attend à un cycle d'activité avalancheuse plus important. Les versants nord présentent encore des épaisseurs importantes, mais sur les versants sud il faut rechercher une neige continue au-dessus de 2 200 mètres. L'accès au refuge doit se faire à pied, et vous ne pouvez plus faire le Planell del Quer à ski. Pour aller à Rialb il faut passer par Forn. , , , , , , , , ,

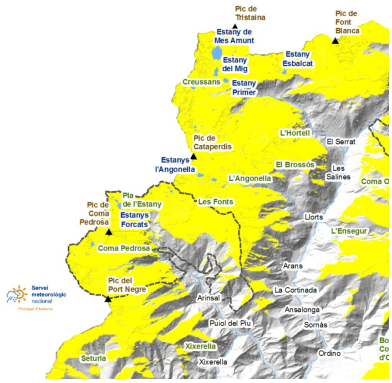

COMAPEDROSA

La neige sera humide sur les versants sud et aux altitudes moyennes, mais le matin nous la trouverons très dure. Des averses de neige mouillée continueront de tomber sur les pentes les plus raides. Au petit matin, avec la neige encore dure, la circulation sera plus difficile et technique. , , , , ,

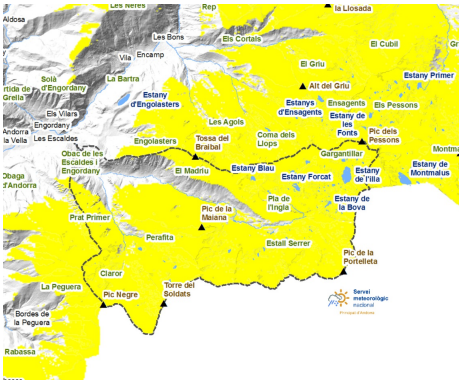

MADRIU-PERAFITA-CLAROR

En journée on s'attend à des purges sur le versant sud en raison de la chaleur. Dans les parties les plus plates des cirques, la neige brune est souvent encore plus rapide que la neige blanche. Depuis l'Estall Serrer en aval, il ne reste plus de neige continue. , , , , ,

BUTLLETÍ DEL PERILL D'ALLAUS DEL PRINCIPAT D'ANDORRA

Servei meteorològic nacional
Principat d'Andorra

Couche de neige fraiche des derniers jours (De 24 h mesurée à 06:00 h UTC)

	15/04/2026	16/04/2026	17/04/2026	18/04/2026
FEDA (Central)	0 cm	0 cm	0 cm	0 cm
Engolasters - FEDA	0 cm	0 cm	0 cm	0 cm
Bony de les Neres	0 cm	0 cm	0 cm	0 cm
Sorteny	0 cm	0 cm	0 cm	0 cm
Les Fonts d'Arinsal	0 cm	0 cm	0 cm	0 cm
Aixàs	0 cm	0 cm	0 cm	0 cm
Perafita	0 cm	0 cm	0 cm	0 cm
Tossa Espiolets	0 cm	0 cm	0 cm	0 cm
Grau Roig - FEDA	0 cm	0 cm	0 cm	0 cm
Fontverd	0 cm	0 cm	1 cm	0 cm
Coll Ordino	0 cm	0 cm	0 cm	0 cm
Ransol - FEDA	0 cm	0 cm	0 cm	0 cm
Setúria	0 cm	0 cm	0 cm	0 cm
Caborreu	0 cm	0 cm	0 cm	0 cm
La Solana	0 cm	0 cm	0 cm	0 cm
Coll Pa	0 cm	0 cm	0 cm	0 cm
Envalira Antenes	0 cm	0 cm	0 cm	0 cm
Vall del Riu FEDA	0 cm	0 cm	0 cm	0 cm