Bulletin d'estimation du risque d'avalanche
(valable en dehors des pistes balisées et ouvertes)

MASSIF : Aure Louron

Rédigé le dimanche 19 avril 2026 à 16h

Estimation des risques pour le : LUNDI 20 AVRIL

EVOLUTION EN PROFONDEUR DE L'HUMIDIFICATION.

2

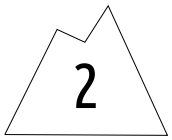

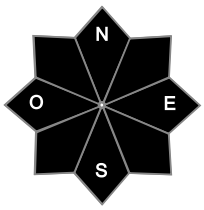

Humidification

Indice de risque limité.

Départs spontanés : Avalanches de fond probables, avalanches de neige humide.

Déclenchements provoqués : Rares, limités au plus haut du massif, en nord.

Indices de risque : 5 très fort - 4 fort - 3 marqué - 2 limité - 1 faible -- En noir : les pentes les plus dangereuses

Stabilité du manteau neigeux

Situation avalancheuse typique : avalanches de fond neige humide

Départs spontanés :
L'activité avalancheuse si faible la nuit, peut toutefois présenter de rares départs de **grandes avalanches de fond à cassure linéaire**, partant souvent depuis une fissure déjà ouverte. Elles sont plus probables en versants Nord à Nord-est où les accumulations sont plus importantes et avec les éclaircies mais une grande, voire très grande avalanche peut advenir en versant sud au vu de l'enneigement conséquent sur le massif au-dessus de 2200 m. Des avalanches de neige humide petites à moyennes seront de plus en plus fréquentes en pentes raides dès 2100 m en sud et 1800 m en nord, au fil de l'ensoleillement et en toutes expositions.

Déclenchements provoqués :
Dans les secteurs nord au-dessus de **2700 m**, de **rares plaques** peuvent encore avoir échappées à l'humidification mais sont devenues assez difficilement déclenchables par tassement.
Le passage d'un skieur dans la neige très humide peut favoriser un départ ponctuel de taille petite voire moyenne.

Autres :
Avec la douceur ambiante, les corniches et ponts de neige sont de plus en plus fragiles et peuvent céder sans surpoids.

Qualité de la neige

Enneigement : L'enneigement est plutôt bon pour la saison, débutant vers 1650 m en nord, relégué au-dessus de 2000 m en sud progressant chaque jour plus haut avec la douceur ambiante et les éclaircies.
État de la neige : Absence de regel sous 2400 m ou rare regel au-dessus au lever du jour, neige portant éventuellement au plus gaut du massif puis la teneur en eau liquide augmente rapidement, avec des enfoncements importants en expositions nord. Neige dense en sud au lever du jour mais généralement non croûtée, devenant vite printanière, très humide sous les éclaircies. Nombreuses fissures en place.

Aperçu météo pour le lundi 20 avril

	nuit	matin	après-midi	soir
	Ciel voilé, éclaircies et passages nuageux en matinée, après midi chargé avec cumulus et bourgeonnements induisant des averses orageuses localisées.			
Pluie-Neige		2 600 m	2 900 m	2 700 m
Iso 0 °C	3 200 m	3 100 m	3 200 m	3 200 m
Vent 1500 m	↑ 15 km/h	← 10 km/h	↑ 30 km/h	↑ 20 km/h
Vent 3000 m	↘ 30 km/h	→ 25 km/h	→ 45 km/h	→ 40 km/h

Épaisseur de neige hors-piste

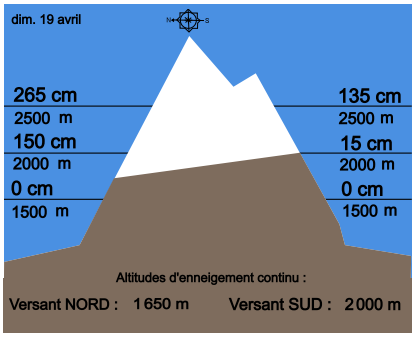

Précipitations à 1800 m

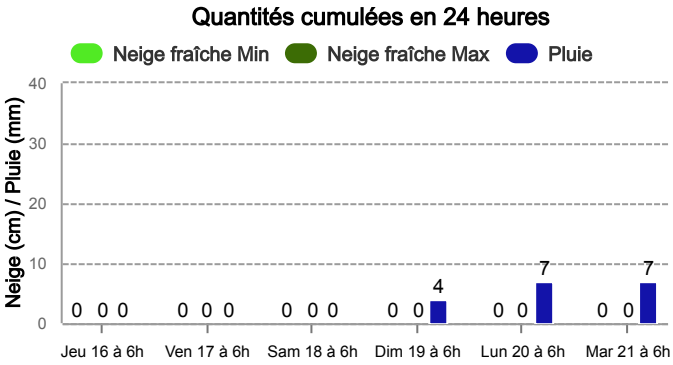

Tendance du mardi 21 avril

2

Indice de risque limité

Mêmes risques avec des températures maximales ayant 1 à 2 degrés de plus.

Pour consulter la vigilance en cours, veuillez vous rendre sur le site https://vigilance.meteofrance.fr/fr

Météo-France - 73 avenue de Paris, 94165 Saint-Mandé cedex - Contact : contact@meteo.fr

Rédigé par Météo-France avec la contribution des observateurs du réseau nivo-météorologiques. Partenariat : ANMSM (Maires de Stations de Montagne), DSF (Domaines Skiables de France), ADSP (Directeurs de Pistes et de la Sécurité des Stations de Sports d'Hiver) et autres acteurs de la montagne.

Bulletin neige & avalanches par téléphone au
0 892 68 10 20 Service 0,35 € / min + prix appel

RÉPUBLIQUE FRANÇAISE
Liberté Égalité Fraternité

METEO FRANCE
À VOS CÔTÉS, DANS UN CLIMAT QUI CHANGE

Bulletin d'estimation du risque d'avalanche

(valable en dehors des pistes balisées et ouvertes)

MASSIF : Aure Louron

Rédigé le dimanche 19 avril 2026 à 16h

Conditions nivo-météo des 7 derniers jours

	lun. 13/04				mar. 14/04				mer. 15/04				jeu. 16/04				ven. 17/04				sam. 18/04				dim. 19/04			
	03h	09h	15h	21h	03h	09h	15h	21h	03h	09h	15h	21h	03h	09h	15h	21h	03h	09h	15h	21h	03h	09h	15h	21h	03h	09h	15h	21h
Météo																												
Vent (km/h)	55	45	35	30	60	60	50	35	45	20	25	25	20	15	15	15	15	10	10	10	10	15	20	15	20	20	30	25
à 3000m																												
Vent (km/h)	15	15	10	5	10	15	25	5	5	10	20	5	5	5	5	5	5	5	5	5	5	10	15	10	10	10	20	15
à 1500m																												

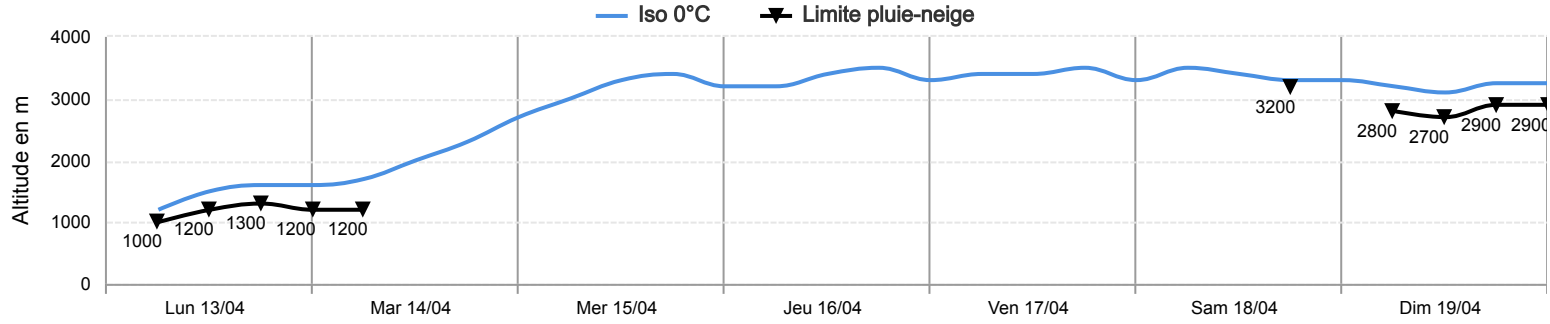

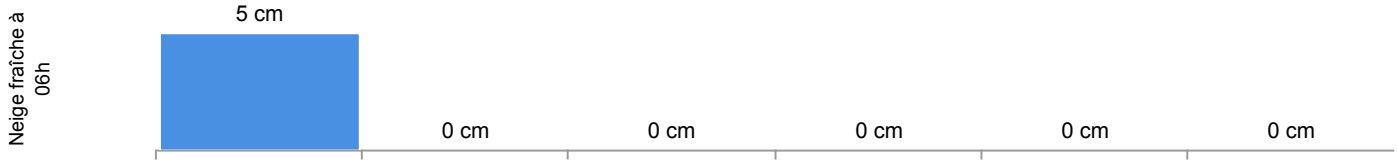

Risque d'avalanche	lun. 13/04	mar. 14/04	mer. 15/04	jeu. 16/04	ven. 17/04	sam. 18/04	dim. 19/04
	3	2	2	2	2	2	2

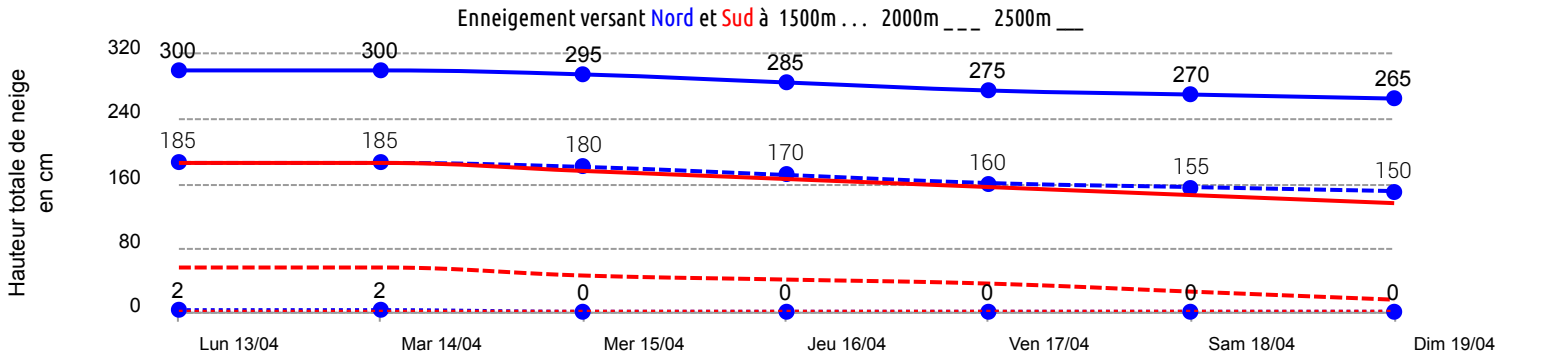

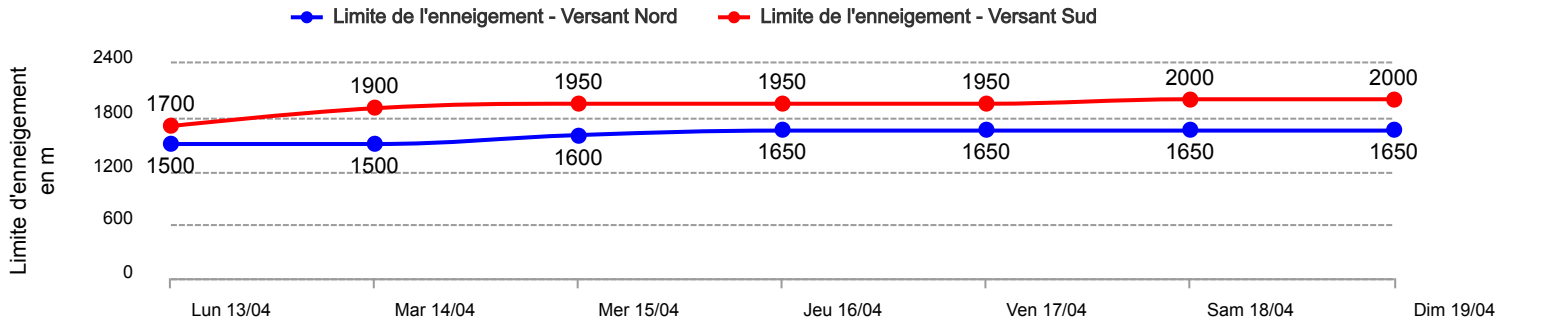

Pour consulter la vigilance en cours, veuillez vous rendre sur le site https://vigilance.meteofrance.fr/fr

Météo-France - 73 avenue de Paris, 94165 Saint-Mandé cedex - Contact : contact@meteo.fr

Rédigé par Météo-France avec la contribution des observateurs du réseau nivo-météorologiques. Partenariat : ANMSM (Maires de Stations de Montagne), DSF (Domaines Skiables de France), ADSP (Directeurs de Pistes et de la Sécurité des Stations de Sports d'Hiver) et autres acteurs de la montagne.

Bulletin neige & avalanches par téléphone au

0 892 68 10 20 Service 0,35 € / min + prix appel