Bulletin d'estimation du risque d'avalanche
(valable en dehors des pistes balisées et ouvertes)

MASSIF : Bauges

Rédigé le dimanche 19 avril 2026 à 16h

Estimation des risques pour le : LUNDI 20 AVRIL

POURSUITE DE L'HUMIDIFICATION (ET DE LA FONTE) DU MANTEAU NEIGEUX.

1

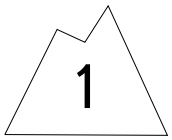

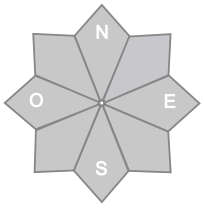

Indice de risque faible.

Départs spontanés : Avalanches de neige humide au soleil.

Déclenchements provoqués : Avalanches de neige humide

Indices de risque : 5 très fort - 4 fort - 3 marqué - 2 limité - 1 faible -- En noir : les pentes les plus dangereuses

Stabilité du manteau neigeux

Situation avalancheuse typique : avalanches de fond neige humide

Départs spontanés :

* Des fissures de reptations continuent de s'ouvrir sur les dalles herbeuses ou rocheuses à toute heure du jour et de la nuit. Par conséquent, des avalanches de fond sont toujours possibles, mais elles peuvent descendre tout de même sans signe avant-coureur. Taille 1 à 2.
* Avalanches de neige humide, en toutes orientations et à toutes altitudes. Ces avalanches sont de plus en plus nombreuses et probables au fil de l'ensoleillement. Taille 1 à 2 (petites à moyennes).

Observables : enfoncement piéton important, boulettes, escargots

Déclenchements provoqués :

* Avalanches de neige humide, dans les versants raides et chauffés par le soleil, facilement déclenchable par un skieur. Taille 1 à 2.

Qualité de la neige

Enneigement :

Pour la saison, l'enneigement est correct, au-dessus de 2000 m, en dessous, il est légèrement déficitaire.

On peut chausser les skis au-dessus de 1800 m en sud et 1500 m en nord.

Qualité de la neige ce lundi :

* On retrouve un manteau neigeux printanier à toutes les altitudes. Durant la nuit, le regel a été bon et ainsi la neige est dure le matin et ramollit rapidement en journée.
* Les crêtes et les arêtes sont souvent décapées.

Aperçu météo pour le lundi 20 avril

	nuit	matin	après-midi	soir

Retour du soleil avec seulement quelques nuages le matin.

Pluie-Neige				
Iso 0 °C	2 800 m	2 700 m	2 700 m	2 700 m
Vent 1500 m	↑ 10 km/h	↗ 15 km/h	→ 20 km/h	↙ 10 km/h
Vent 2000 m	→ 20 km/h	↗ 25 km/h	↘ 25 km/h	→ 15 km/h

Épaisseur de neige hors-piste

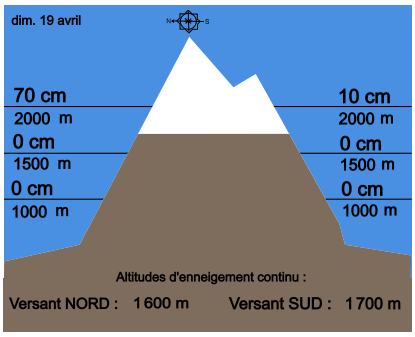

Précipitations à 1800 m

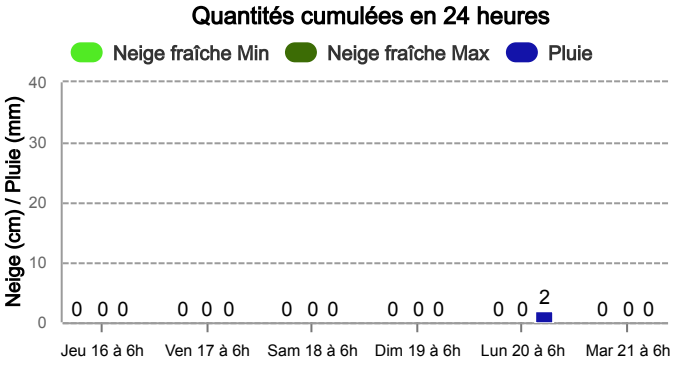

Tendance du mardi 21 avril

1

Indice de risque faible

Le temps est toujours printanier et doux. La fonte se poursuit et le risque reste faible.

Pour consulter la vigilance en cours, veuillez vous rendre sur le site https://vigilance.meteofrance.fr/fr

Météo-France - 73 avenue de Paris, 94165 Saint-Mandé cedex - Contact : contact@meteo.fr

Rédigé par Météo-France avec la contribution des observateurs du réseau nivo-météorologiques. Partenariat : ANMSM (Maires de Stations de Montagne), DSF (Domaines Skiables de France), ADSP (Directeurs de Pistes et de la Sécurité des Stations de Sports d'Hiver) et autres acteurs de la montagne.

Bulletin neige & avalanches par téléphone au 0 892 68 10 20 Service 0,35 € / min + prix appel

RÉPUBLIQUE FRANÇAISE
Liberté Égalité Fraternité

METEO FRANCE
À VOS CÔTÉS, DANS UN CLIMAT QUI CHANGE

Bulletin d'estimation du risque d'avalanche

(valable en dehors des pistes balisées et ouvertes)

MASSIF : Bauges

Rédigé le dimanche 19 avril 2026 à 16h

Conditions nivo-météo des 7 derniers jours

	lun. 13/04				mar. 14/04				mer. 15/04				jeu. 16/04				ven. 17/04				sam. 18/04				dim. 19/04			
	03h	09h	15h	21h	03h	09h	15h	21h	03h	09h	15h	21h	03h	09h	15h	21h	03h	09h	15h	21h	03h	09h	15h	21h	03h	09h	15h	21h
Météo																												
Vent (km/h)	15	20	20	15	20	25	20	15	10	10	10	10	20	15	20	10	20	20	10	10	10	10	10	10	15	25	25	15
à 2000m																												
Vent (km/h)	10	10	15	10	15	20	20	10	5	5	10	5	15	10	15	5	10	10	5	5	5	5	5	5	10	15	20	10
à 1500m																												

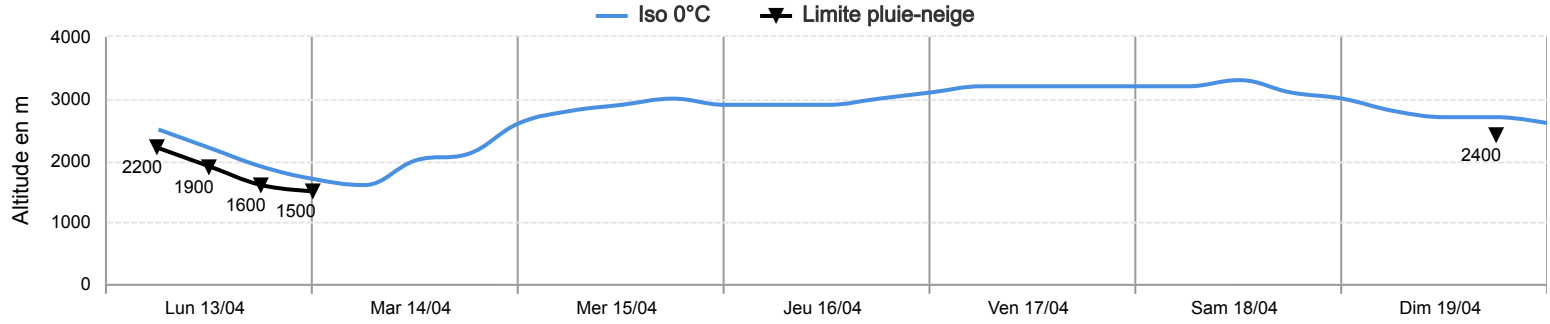

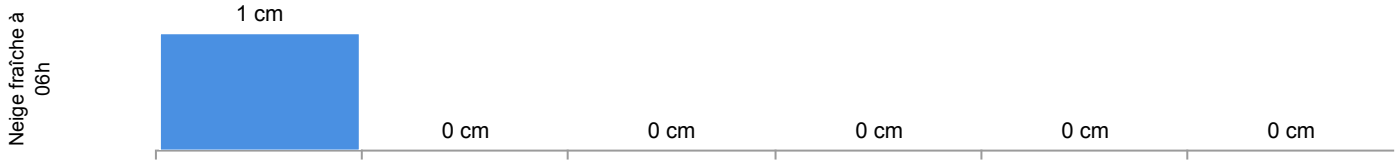

Risque d'avalanche	lun. 13/04	mar. 14/04	mer. 15/04	jeu. 16/04	ven. 17/04	sam. 18/04	dim. 19/04
	2	2	2	2	2	1	1

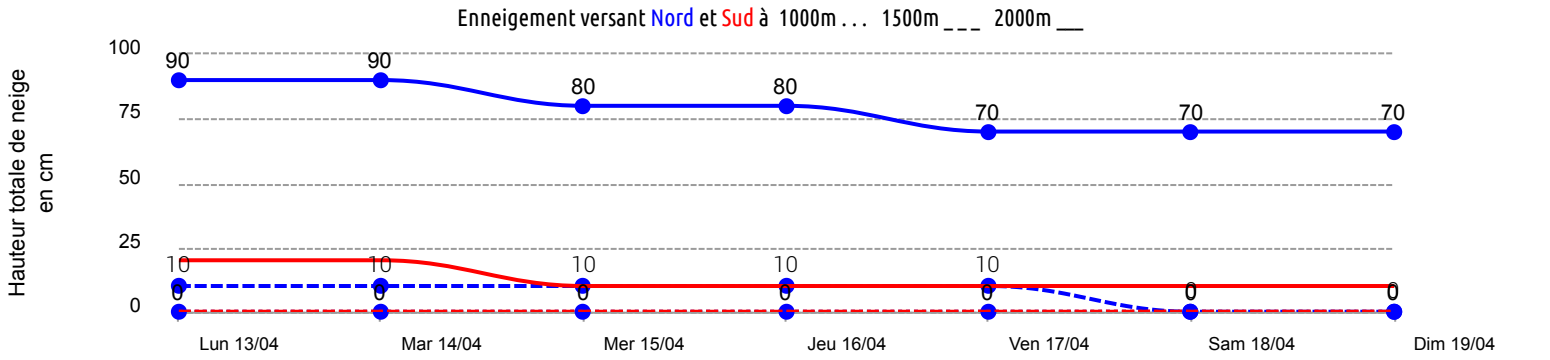

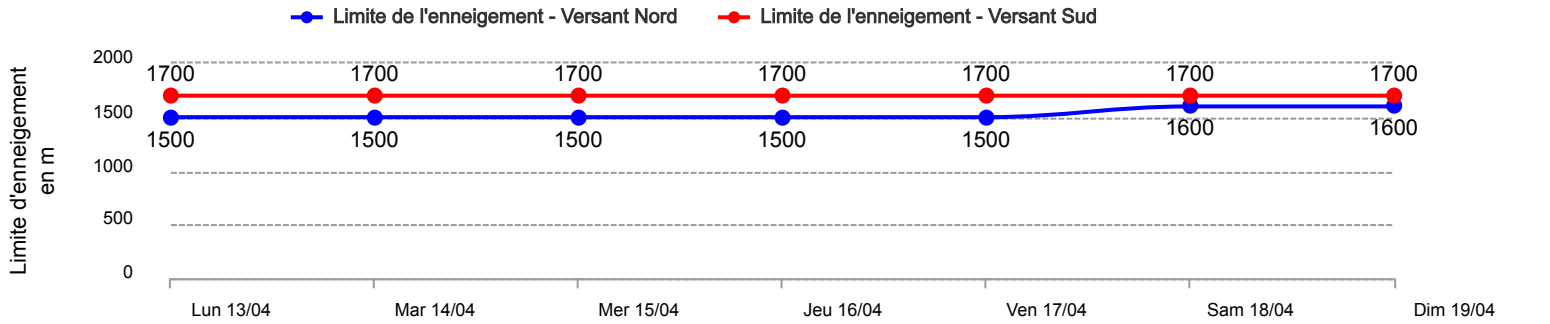

Pour consulter la vigilance en cours, veuillez vous rendre sur le site https://vigilance.meteofrance.fr/fr

Météo-France - 73 avenue de Paris, 94165 Saint-Mandé cedex - Contact : contact@meteo.fr

Rédigé par Météo-France avec la contribution des observateurs du réseau nivo-météorologiques. Partenariat : ANMSM (Maires de Stations de Montagne), DSF (Domaines Skiables de France), ADSP (Directeurs de Pistes et de la Sécurité des Stations de Sports d'Hiver) et autres acteurs de la montagne.

Bulletin neige & avalanches par téléphone au

0 892 68 10 20 Service 0,35 € / min + prix appel