Bulletin d'estimation du risque d'avalanche
(valable en dehors des pistes balisées et ouvertes)

MASSIF : Chablais

Rédigé le dimanche 19 avril 2026 à 16h

Estimation des risques pour le : LUNDI 20 AVRIL

POURSUITE DE L'HUMIDIFICATION DU MANTEAU NEIGEUX.

2

1 → 2

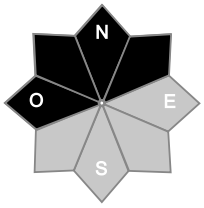

Indice de risque faible évoluant en limité.

Départs spontanés : Avalanches de neige humide au soleil.

Déclenchements provoqués : Avalanches de neige humide

Indices de risque : 5 très fort - 4 fort - 3 marqué - 2 limité - 1 faible -- En noir : les pentes les plus dangereuses

Stabilité du manteau neigeux

Situation avalancheuse typique : neige humide — couche fragile persistante

Départs spontanés :
* Avalanches de neige humide, en toutes orientations et à toutes altitudes. Ces avalanches sont de plus en plus nombreuses et probables au fil de l'ensoleillement. Taille 1 à 2 (petites à moyennes).
* Au-dessus de 2200m dans les ubacs, une couche fragile persistante est enfouie en profondeur dans le manteau neigeux. Cette couche fragile pourrait être sollicitée via un petit départ ponctuel, engendrant ainsi un départ linéaire en cascade. Avalanche de taille 2, voire 3 (moyenne à grande).
Observables : enfoncement piéton important, boulettes, escargots
* Des fissures de reptations continuent de s'ouvrir sur les dalles herbeuses ou rocheuses à toute heure du jour et de la nuit. Par conséquent, des avalanches de fond sont toujours possibles, mais elles peuvent descendre tout de même sans signe avant-coureur. Taille 1 à 2.

Déclenchements provoqués :
* Avalanches de neige humide, dans les versants raides et chauffés par le soleil, facilement déclenchable par un skieur. Taille 1 à 2.
* La couche fragile persiste évoquée plus tôt ne semble pas être directement déclenchable par un skieur, mais une première coulée pourrait la solliciter et engendrer ainsi des avalanches de taille 2 à 3.

Qualité de la neige

Enneigement :
Pour la saison, l'enneigement est correct, au-dessus de 2000 m, en dessous, il est légèrement déficitaire.
On peut chausser les skis au-dessus de 1800 m en sud et 1500 m en nord.

Qualité de la neige ce lundi :
* On retrouve un manteau neigeux printanier à toutes les altitudes. Durant la nuit, le regel a été bon et ainsi la neige est dure le matin et ramollit rapidement en journée.
* Les crêtes et les arêtes sont souvent décapées.

Aperçu météo pour le lundi 20 avril

	nuit	matin	après-midi	soir
Pluie-Neige				
Iso 0 °C	2 700 m	2 500 m	2 600 m	2 500 m
Vent 2000 m	↗ 15 km/h	↗ 15 km/h	↘ 15 km/h	↗ 10 km/h
Vent 2500 m	↗ 30 km/h	↗ 20 km/h	→ 20 km/h	→ 20 km/h

Retour du soleil avec seulement quelques nuages le matin.

Épaisseur de neige hors-piste

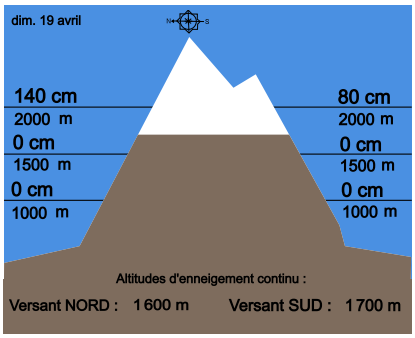

Précipitations à 1800 m

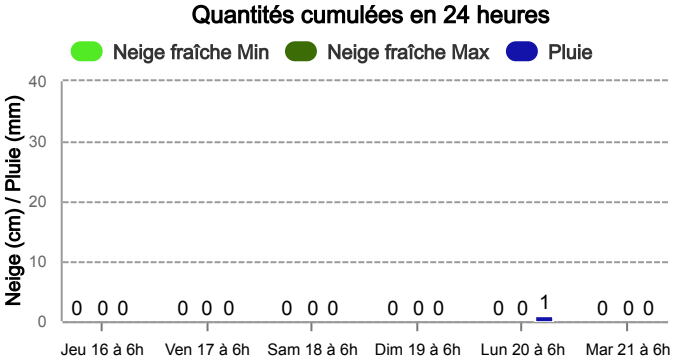

Tendance du mardi 21 avril

2

Indice de risque limité

Le temps est toujours printanier et doux. La fonte se poursuit et le risque reste stable.

Pour consulter la vigilance en cours, veuillez vous rendre sur le site https://vigilance.meteofrance.fr/fr

Météo-France - 73 avenue de Paris, 94165 Saint-Mandé cedex - Contact : contact@meteo.fr

Rédigé par Météo-France avec la contribution des observateurs du réseau nivo-météorologiques. Partenariat : ANMSM (Maires de Stations de Montagne), DSF (Domaines Skiables de France), ADSP (Directeurs de Pistes et de la Sécurité des Stations de Sports d'Hiver) et autres acteurs de la montagne.

Bulletin neige & avalanches par téléphone au 0 892 68 10 20 Service 0,35 € / min + prix appel

RÉPUBLIQUE FRANÇAISE
Liberté Égalité Fraternité

METEO FRANCE
À VOS CÔTÉS, DANS UN CLIMAT QUI CHANGE

Bulletin d'estimation du risque d'avalanche

(valable en dehors des pistes balisées et ouvertes)

MASSIF : Chablais

Rédigé le dimanche 19 avril 2026 à 16h

Conditions nivo-météo des 7 derniers jours

	lun. 13/04				mar. 14/04				mer. 15/04				jeu. 16/04				ven. 17/04				sam. 18/04				dim. 19/04			
	03h	09h	15h	21h	03h	09h	15h	21h	03h	09h	15h	21h	03h	09h	15h	21h	03h	09h	15h	21h	03h	09h	15h	21h	03h	09h	15h	21h
Météo																												
Vent (km/h)	25	25	15	15	15	20	20	20	15	10	10	10	15	15	10	15	20	20	20	20	10	10	15	15	20	25	25	30
à 2500m																												
Vent (km/h)	10	15	10	10	20	25	15	15	10	5	5	5	10	10	5	10	10	10	10	10	5	5	10	10	15	20	15	20
à 2000m																												

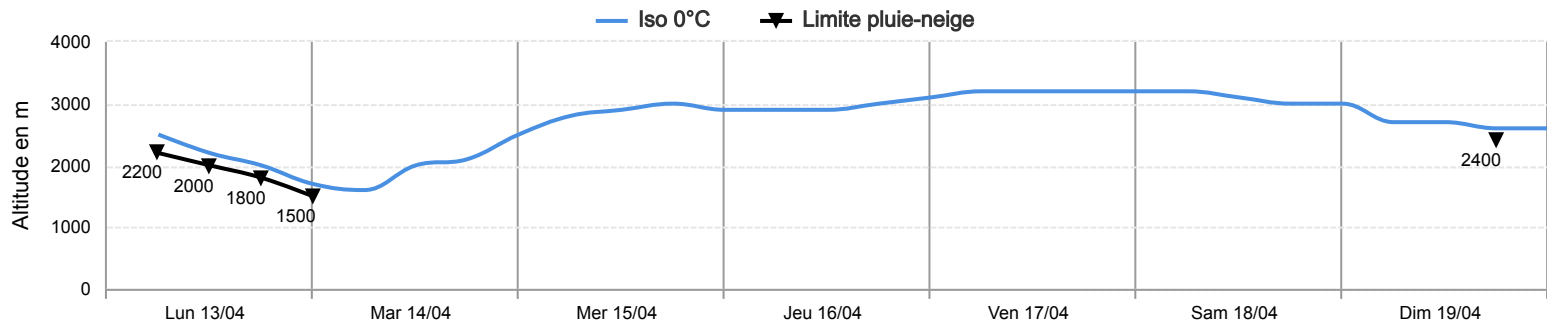

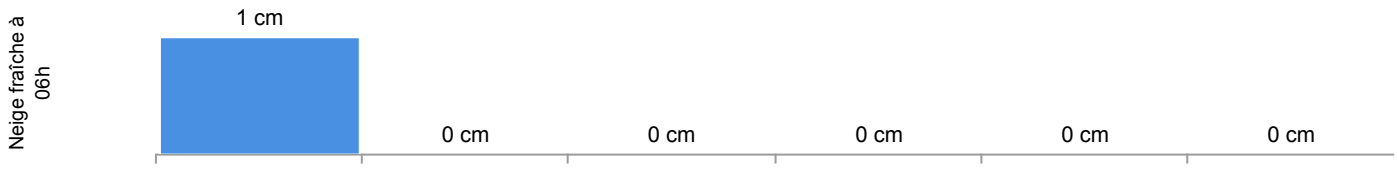

Risque d'avalanche	lun. 13/04	mar. 14/04	mer. 15/04	jeu. 16/04	ven. 17/04	sam. 18/04	dim. 19/04
	2	2	2	2	2	2	2

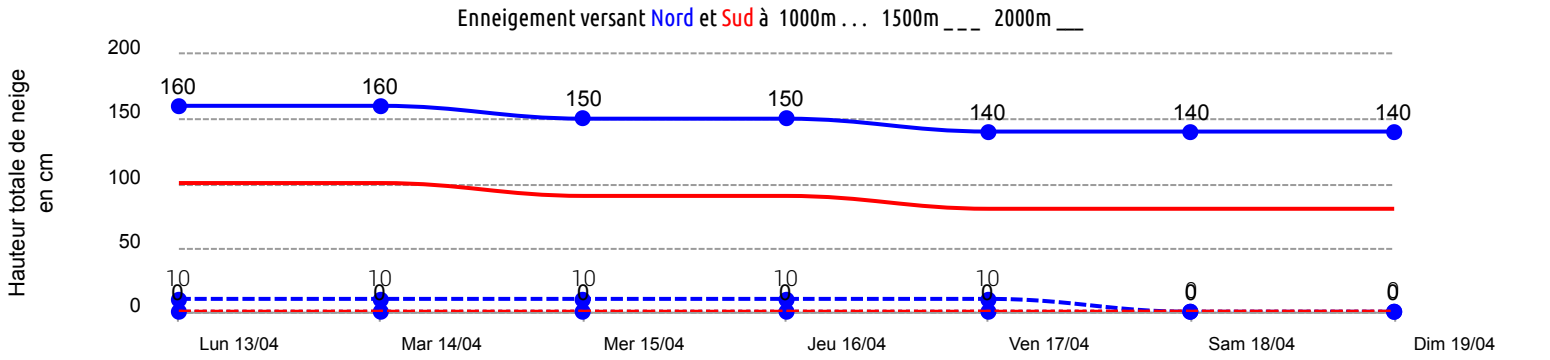

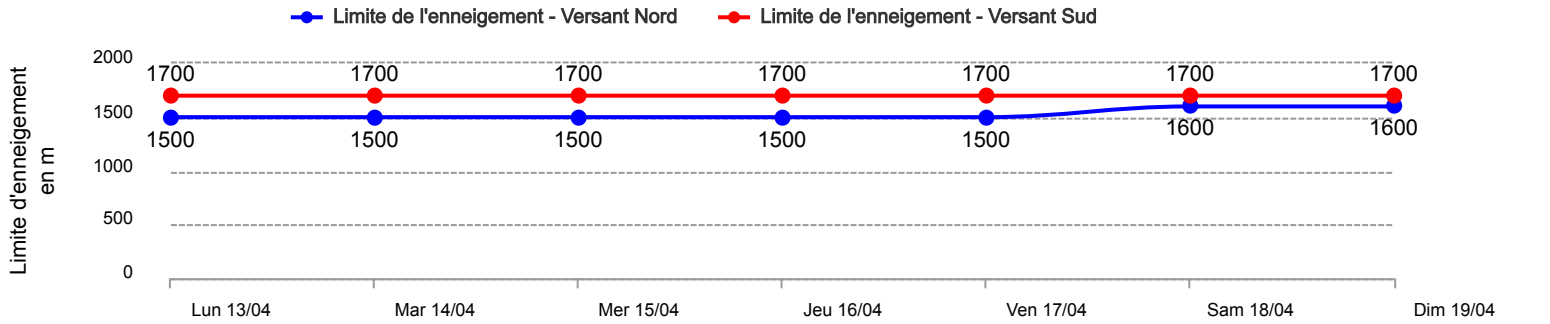

Pour consulter la vigilance en cours, veuillez vous rendre sur le site https://vigilance.meteofrance.fr/fr

Météo-France - 73 avenue de Paris, 94165 Saint-Mandé cedex - Contact : contact@meteo.fr

Rédigé par Météo-France avec la contribution des observateurs du réseau nivo-météorologiques. Partenariat : ANMSM (Maires de Stations de Montagne), DSF (Domaines Skiables de France), ADSP (Directeurs de Pistes et de la Sécurité des Stations de Sports d'Hiver) et autres acteurs de la montagne.

Bulletin neige & avalanches par téléphone au
0 892 68 10 20 Service 0,35 € / min + prix appel