RÉPUBLIQUE FRANÇAISE
Liberté Égalité Fraternité

METEO FRANCE
À VOS CÔTÉS, DANS UN CLIMAT QUI CHANGE

Bulletin d'estimation du risque d'avalanche
(valable en dehors des pistes balisées et ouvertes)
MASSIF : Haute-Tarentaise

Rédigé le dimanche 19 avril 2026 à 16h

Estimation des risques pour le : LUNDI 20 AVRIL

CONDITIONS DE PRINTEMPS AVEC FONTE RAPIDE AVEC LA CHALEUR EXCESSIVE EN COURS

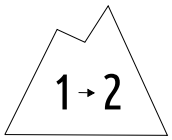

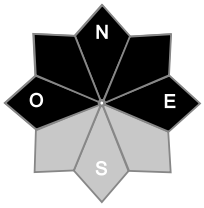

Indice de risque faible évoluant en limité.

Départs spontanés : rares mais possiblement gros départs en neige humide.

Déclenchements provoqués : neige humide sous les skis.

Indices de risque : 5 très fort - 4 fort - 3 marqué - 2 limité - 1 faible -- En noir : les pentes les plus dangereuses

Stabilité du manteau neigeux

Situation avalancheuse typique : neige humide

Départs spontanés :
- **Rares avalanches de neige humide** dans les **pentes ensoleillées** au fil de la journée. Les départs ponctuels (en poire) se font désormais petits et rares. Avec l'avancée dans la saison, les pentes Sud deviennent relativement inertes avec une neige transformée sur toute l'épaisseur du manteau jusqu'à haute altitude. Par contre, dans les versants Est, Nord et Ouest, l'humidification gagne des couches plus profondes. Ainsi, lorsqu'une couche fragile est atteinte, **un départ linéaire est possible**. On peut alors s'attendre à de **rares grandes avalanches (taille 3).**

Déclenchements provoqués : avalanche de neige humide (pourrie) sous les skis en coupant une pente trop humidifiée.
Secteur sources de l'Isère et Pisaillas : en Nord très raide et encaissé, au-dessus de 3000 m, une rare petite plaque d'aspect poudreux peut subsister dans la neige récente.

Autres : chutes de corniches signalées.

Qualité de la neige

Enneigement : déficitaire pour la saison, la montagne subit les assauts répétés de la chaleur excessive et la neige fond à vue d'œil

Limite skiable : vers 1400/1500 m en Nord, 1700/1800 m en Sud.

Qualité de la neige : neige de printemps après un très bon regel nocturne. Neige dure aux premières heures du jour puis moquette aux bonnes heures (milieu de matinée à la mi journée suivant orientations et altitude. Comme les jours précédents, les pentes Est chauffent très vite le matin.. Neige pourrie l'après midi / soirée.
A la marge, dans le Nord raide au-delà de 3000/3200 m, on peut encore trouver un peu de neige froide en surface.

Aperçu météo pour le lundi 20 avril

	nuit	matin	après-midi	soir

Beau le matin, plus nuageux l'après midi.

Pluie-Neige				
Iso 0 °C	2 800 m	2 900 m	2 900 m	2 600 m
Vent 2500 m	→ 15 km/h	→ 20 km/h	→ 20 km/h	→ 15 km/h
Vent 3500 m	→ 40 km/h	→ 40 km/h	→ 35 km/h	→ 40 km/h

Épaisseur de neige hors-piste

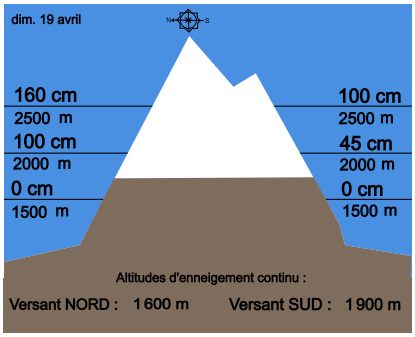

Précipitations à 1800 m

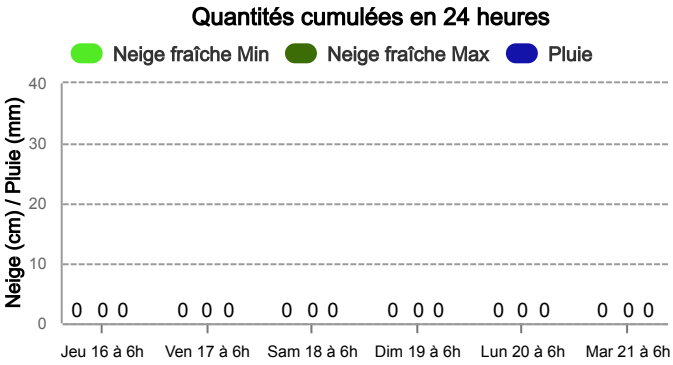

Tendance du mardi 21 avril

Indice de risque limité

Toujours trop chaud et trop sec pour la saison. La neige poursuit sa fonte accélérée. Manteau stable le matin tôt puis rares avalanches de neige humide ensuite en cours de journée.

Pour consulter la vigilance en cours, veuillez vous rendre sur le site https://vigilance.meteofrance.fr/fr

Météo-France - 73 avenue de Paris, 94165 Saint-Mandé cedex - Contact : contact@meteo.fr

Rédigé par Météo-France avec la contribution des observateurs du réseau nivo-météorologiques. Partenariat : ANMSM (Maires de Stations de Montagne), DSF (Domaines Skiables de France), ADSP (Directeurs de Pistes et de la Sécurité des Stations de Sports d'Hiver) et autres acteurs de la montagne.

Bulletin neige & avalanches par téléphone au
0 892 68 10 20 Service 0,35 € / min + prix appel

RÉPUBLIQUE FRANÇAISE
Liberté Égalité Fraternité

METEO FRANCE
À VOS CÔTÉS, DANS UN CLIMAT QUI CHANGE

Bulletin d'estimation du risque d'avalanche

(valable en dehors des pistes balisées et ouvertes)

MASSIF : Haute-Tarentaise

Rédigé le dimanche 19 avril 2026 à 16h

Conditions nivo-météo des 7 derniers jours

	lun. 13/04				mar. 14/04				mer. 15/04				jeu. 16/04				ven. 17/04				sam. 18/04				dim. 19/04			
	03h	09h	15h	21h	03h	09h	15h	21h	03h	09h	15h	21h	03h	09h	15h	21h	03h	09h	15h	21h	03h	09h	15h	21h	03h	09h	15h	21h
Météo																												
Vent (km/h)	40	35	30	25	20	25	25	15	10	10	15	10	15	15	15	10	10	15	15	15	20	15	15	15	20	30	30	30
à 3500m	↖	←	←	←	←	←	↙	↘	↘	↘	↘	↘	↘	↘	↗	→	↘	→	→	→	↘	↘	↘	→	→	→	→	→
Vent (km/h)	30	25	20	10	15	20	20	10	5	5	15	5	10	10	10	5	5	5	10	10	15	10	10	10	10	15	20	15
à 2500m	←	↙	↙	↙	←	←	↙	↘	↘	↘	↘	↘	↘	↘	→	↗	→	↗	→	↘	↘	↘	↘	↘	→	↘	↘	→

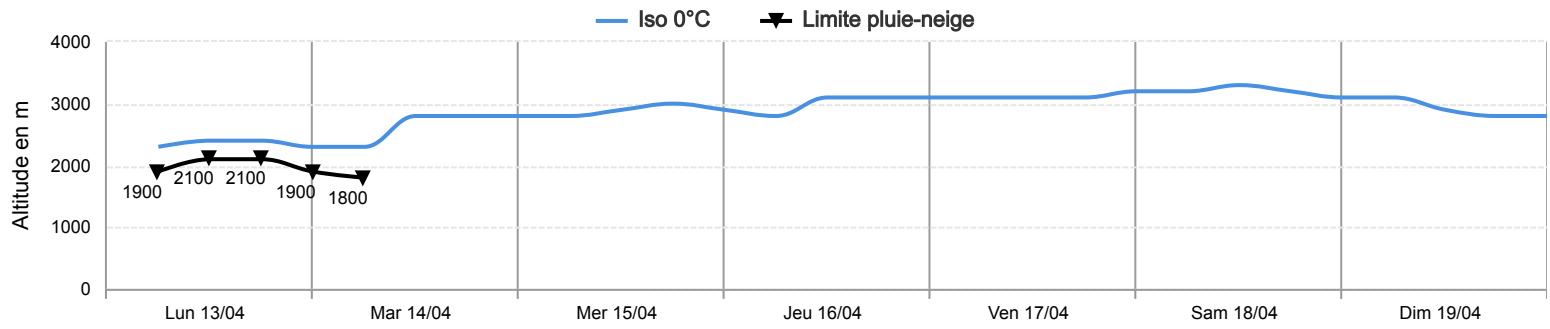

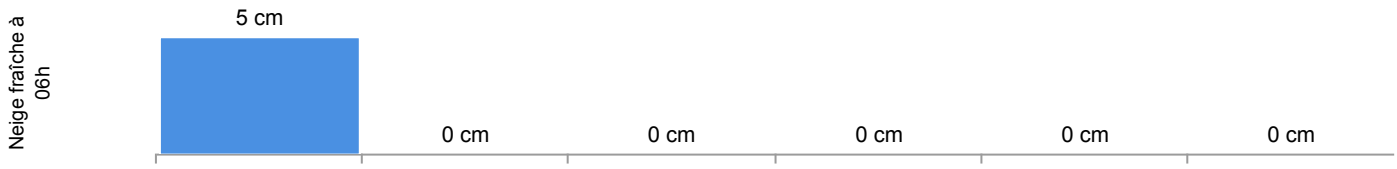

Risque d'avalanche	lun. 13/04	mar. 14/04	mer. 15/04	jeu. 16/04	ven. 17/04	sam. 18/04	dim. 19/04
	2	2	2	2	2	2	2

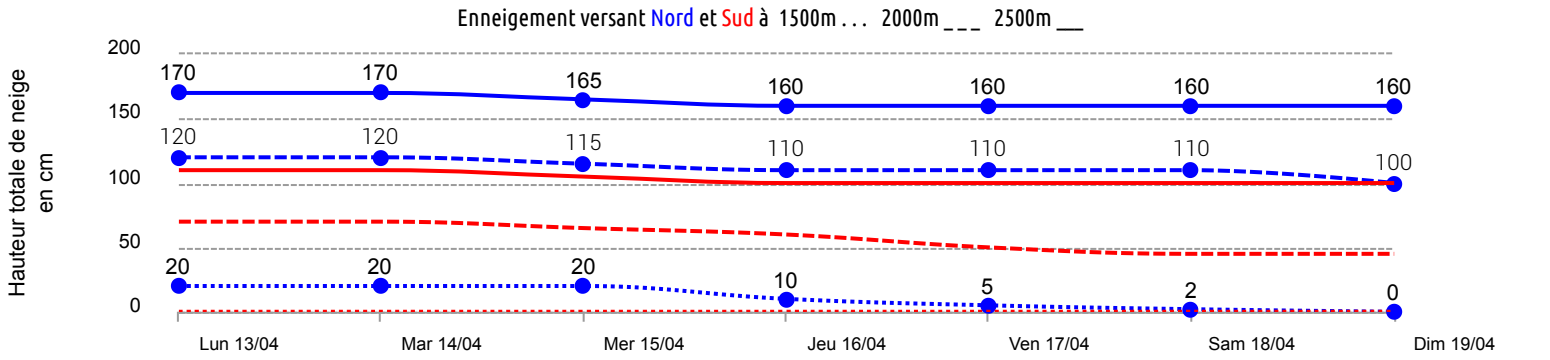

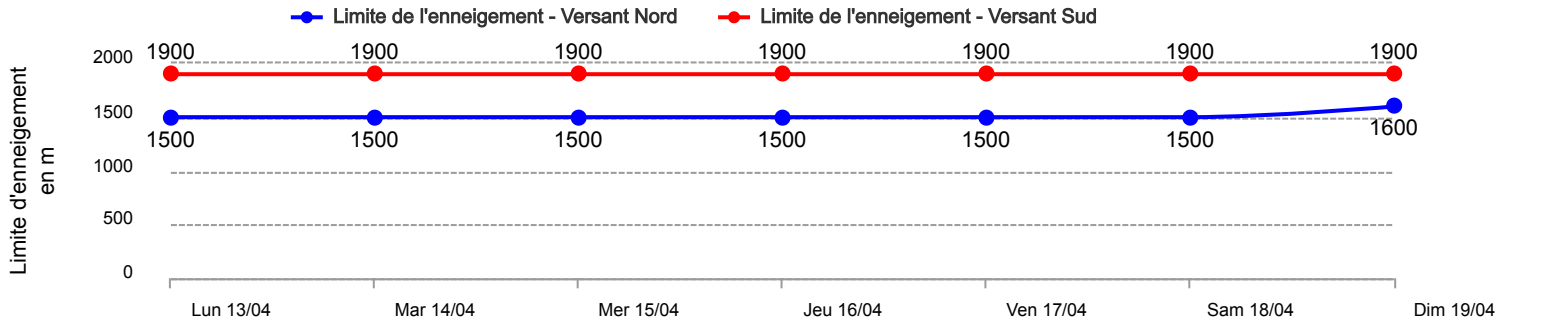

Pour consulter la vigilance en cours, veuillez vous rendre sur le site https://vigilance.meteofrance.fr/fr

Météo-France - 73 avenue de Paris, 94165 Saint-Mandé cedex - Contact : contact@meteo.fr

Rédigé par Météo-France avec la contribution des observateurs du réseau nivo-météorologiques. Partenariat : ANMSM (Maires de Stations de Montagne), DSF (Domaines Skiables de France), ADSP (Directeurs de Pistes et de la Sécurité des Stations de Sports d'Hiver) et autres acteurs de la montagne.

Bulletin neige & avalanches par téléphone au
0 892 68 10 20 Service 0,35 € / min + prix appel