Bulletin d'estimation du risque d'avalanche
(valable en dehors des pistes balisées et ouvertes)

MASSIF : Pays-Basque

Rédigé le dimanche 19 avril 2026 à 16h

Estimation des risques pour le : LUNDI 20 AVRIL

POURSUITE DE L'HUMIDIFICATION EN PROFONDEUR.

2

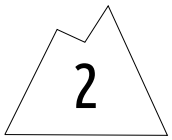

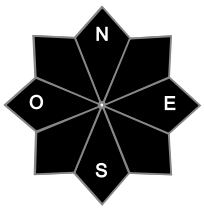

Neige humide

Indice de risque limité.

Départs spontanés : Avalanches de fond / neige humide

Déclenchements provoqués : Difficiles

Indices de risque : 5 très fort - 4 fort - 3 marqué - 2 limité - 1 faible -- En noir : les pentes les plus dangereuses

Stabilité du manteau neigeux

Situation avalancheuse typique : avalanches de fond neige humide

Départs spontanés :
L'activité avalancheuse si faible la nuit, peut toutefois présenter de rares départs de grandes avalanches de fond, partant souvent depuis une fissure déjà ouverte. Elles sont plus probables en nord à nord-est où les accumulations sont plus importantes. Des avalanches petites à moyennes sont fréquentes en pentes raides au vu de l'enneigement restant en place, celles-ci peuvent être plus fréquentes en journée au fil de l'ensoleillement en toutes expositions. Risque présent surtout vers le Barétous et l'Anie, le reste du massif étant peu enneigé.

Déclenchements provoqués :
Pas de structure de plaques dans ce massif. Le passage d'un skieur dans la neige très humide peut favoriser un départ ponctuel de taille petite voire moyenne.

Autres :
Avec la douceur ambiante, les corniches et ponts de neige (au-dessus des ruisseaux ou des fissures du Lapiaz) deviennent à nouveau très fragiles.

Qualité de la neige

Enneigement : L'enneigement est plutôt bon pour la saison vers la Pierre-Saint-Martin, débutant vers 1650 m en nord et 2000 m environ en sud. Cette limite d'enneigement tend à remonter progressivement avec la douceur ambiante et les éclaircies. Enneigement discontinu et faible en allant vers l'ouest, coté Pays Basque.
État de la neige : Absence ou rare regel au lever du jour, la neige s'humidifie ensuite rapidement, avec des enfoncements importants en expositions nord. Neige dense en sud au lever du jour mais généralement non croûtée, devenant très humide au soleil.

Aperçu météo pour le lundi 20 avril

	nuit	matin	après-midi	soir
	Ciel voilé, éclaircies et passages nuageux en matinée, après midi chargé avec cumulus et bourgeonnements induisant des averses orageuses localisées.			
Pluie-Neige		2700 m	2700 m	2700 m
Iso 0 °C	3200 m	3100 m	3200 m	3300 m
Vent 1000 m	↑ 25 km/h	↗ 25 km/h	↓ 30 km/h	← 20 km/h
Vent 2000 m	↑ 35 km/h	↑ 45 km/h	↘ 45 km/h	↑ 40 km/h

Épaisseur de neige hors-piste

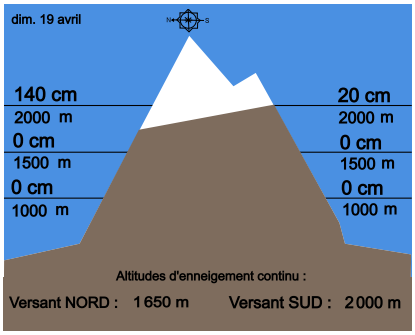

Précipitations à 1800 m

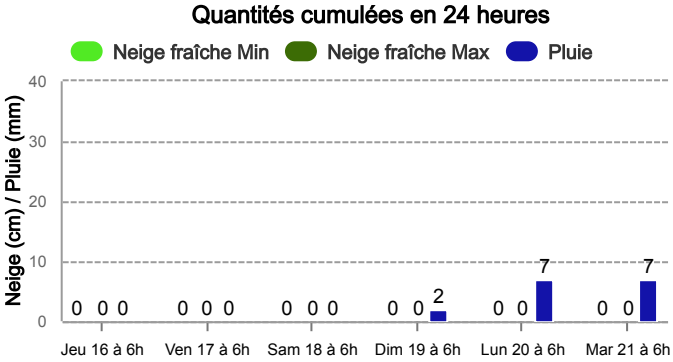

Tendance du mardi 21 avril

2

Indice de risque limité

Mêmes risques avec 2 degrés de plus.

Pour consulter la vigilance en cours, veuillez vous rendre sur le site https://vigilance.meteofrance.fr/fr

Météo-France - 73 avenue de Paris, 94165 Saint-Mandé cedex - Contact : contact@meteo.fr

Rédigé par Météo-France avec la contribution des observateurs du réseau nivo-météorologiques. Partenariat : ANMSM (Maires de Stations de Montagne), DSF (Domaines Skiables de France), ADSP (Directeurs de Pistes et de la Sécurité des Stations de Sports d'Hiver) et autres acteurs de la montagne.

Bulletin neige & avalanches par téléphone au
0 892 68 10 20 Service 0,35 € / min + prix appel

RÉPUBLIQUE FRANÇAISE
Liberté Égalité Fraternité

METEO FRANCE
À VOS CÔTÉS, DANS UN CLIMAT QUI CHANGE

Bulletin d'estimation du risque d'avalanche

(valable en dehors des pistes balisées et ouvertes)

MASSIF : Pays-Basque

Rédigé le dimanche 19 avril 2026 à 16h

Conditions nivo-météo des 7 derniers jours

	lun. 13/04				mar. 14/04				mer. 15/04				jeu. 16/04				ven. 17/04				sam. 18/04				dim. 19/04			
	03h	09h	15h	21h	03h	09h	15h	21h	03h	09h	15h	21h	03h	09h	15h	21h	03h	09h	15h	21h	03h	09h	15h	21h	03h	09h	15h	21h
Météo																												
Vent (km/h)	35	40	45	35	45	40	35	30	35	35	35	25	15	15	15	10	10	10	10	10	20	15	15	20	25	25	25	30
à 2000m	↓	↓	↓	↓	↓	↓	↓	↙	↙	↙	↓	←	←	↗	↗	→	→	↗	→	↘	↑	↘	↙	↑	↑	↗	↘	↑
Vent (km/h)	15	15	20	15	15	20	30	15	10	15	15	10	5	5	5	5	5	5	5	5	5	10	10	10	10	15	15	15
à 1000m	↓	↓	↓	↓	↓	↓	↓	↙	↓	↙	↓	↙	↙	↙	↙	↙	↙	↙	↙	↙	↙	↙	↙	←	↑	↑	↓	↗

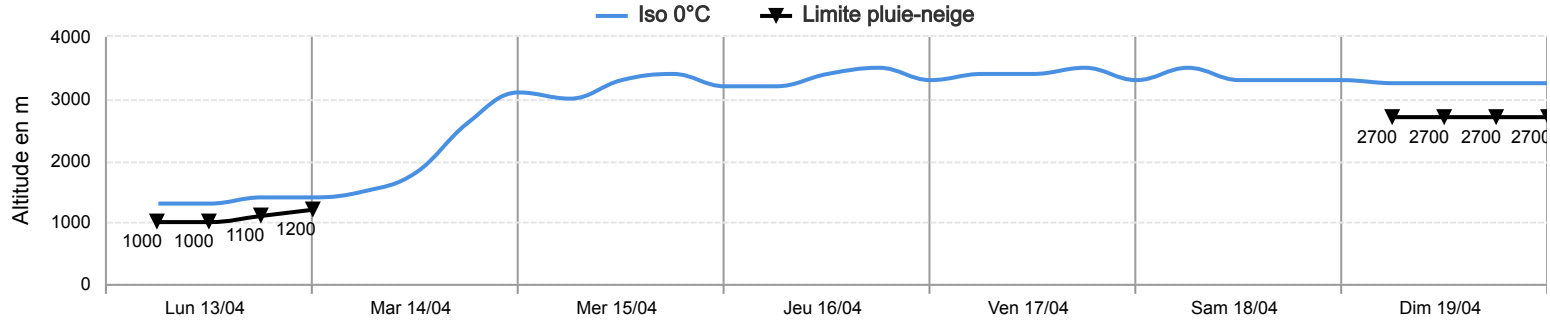

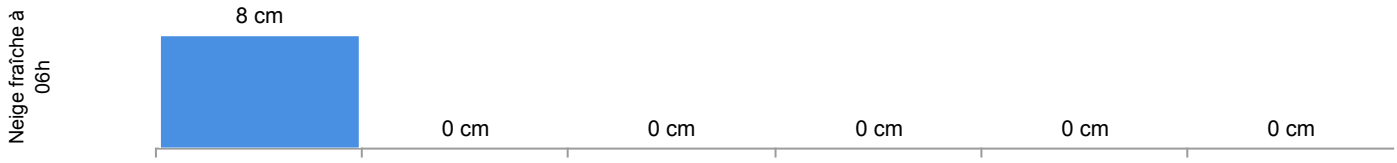

Risque d'avalanche	lun. 13/04	mar. 14/04	mer. 15/04	jeu. 16/04	ven. 17/04	sam. 18/04	dim. 19/04
	3	2	2	2	2	2	2

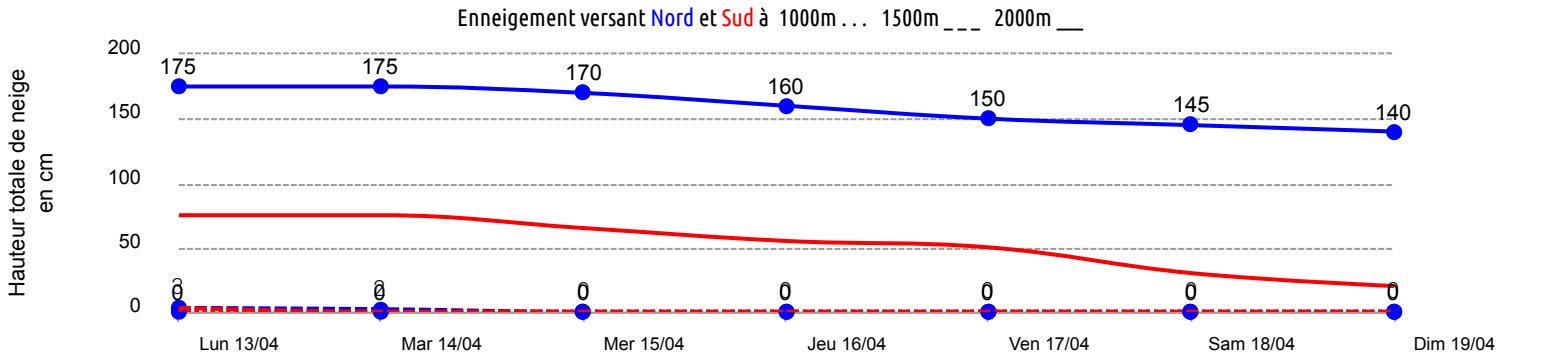

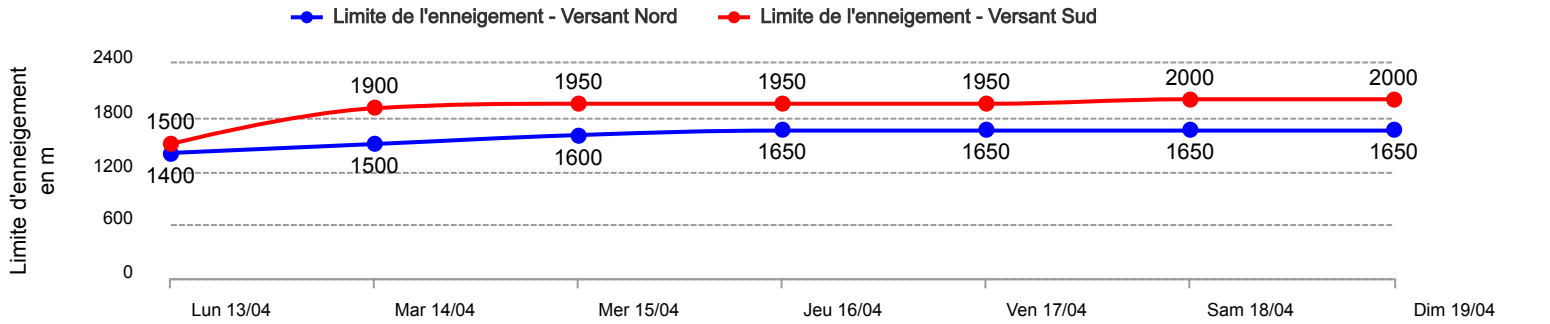

Pour consulter la vigilance en cours, veuillez vous rendre sur le site https://vigilance.meteofrance.fr/fr

Météo-France - 73 avenue de Paris, 94165 Saint-Mandé cedex - Contact : contact@meteo.fr

Rédigé par Météo-France avec la contribution des observateurs du réseau nivo-météorologiques. Partenariat : ANMSM (Maires de Stations de Montagne), DSF (Domaines Skiables de France), ADSP (Directeurs de Pistes et de la Sécurité des Stations de Sports d'Hiver) et autres acteurs de la montagne.

Bulletin neige & avalanches par téléphone au

0 892 68 10 20 Service 0,35 € / min + prix appel