Bulletin d'estimation du risque d'avalanche
(valable en dehors des pistes balisées et ouvertes)

MASSIF : Pelvoux

Rédigé le dimanche 19 avril 2026 à 16h

Estimation des risques pour le : LUNDI 20 AVRIL

MANTEAU NEIGEUX PRINTANIER, QUELQUES AVALANCHES DE NEIGE HUMIDE POSSIBLES EN UBACS D'ALTITUDE

2

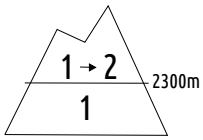

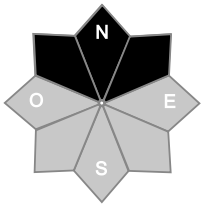

Au-dessus de 2300m indice de risque faible évoluant en limité, plus bas indice faible.

Départs spontanés : en neige humide en altitude.

Déclenchements provoqués : en neige humide en altitude.

Indices de risque : 5 très fort - 4 fort - 3 marqué - 2 limité - 1 faible -- En noir : les pentes les plus dangereuses

Stabilité du manteau neigeux

Situation avalancheuse typique : neige humide

Déclenchements provoqués :
Départs possibles sous les skis de neige fortement humidifiée par le soleil en pente raide. Instabilités localisées principalement en versants ouest, nord et est d'altitude supérieure à 2300 m, les pentes sud et les basses altitudes étant déjà en neige transformée sur l'intégralité du manteau neigeux. Avalanches pouvant être déclenchées par un skieur, généralement ponctuelles et de petite taille (taille 1), plus rarement moyenne (taille 2). Exceptionnellement une grande taille est possible sous forme de départ linéaire jusqu'au sol, en un large versant nord au dessus de 2300/2400 m environ où se trouvent encore localement des couches fragiles persistantes enfouies à la base du manteau neigeux.

Départs spontanés :
Peu probables en tout début de journée après un regel nocturne plutôt bon, puis reprise rapide de l'humidification au fil de la course du soleil. Quelques avalanches peuvent alors se déclencher, principalement au dessus de 2300 m environ, généralement sous forme de départ ponctuel de petite taille (taille 1), plus rarement moyenne (taille 2), et exceptionnellement grande (taille 3) en cas de départ linéaire en versant nord si l'humidification du manteau neigeux atteint pour la première fois la couche fragile encore présente à la base du manteau neigeux.

Qualité de la neige

Enneigement légèrement déficitaire sur l'ensemble du massif : nettement déficitaires en adrets, plus proche des normales voire légèrement déficitaire en ubacs et vallons d'altitude au-dessus de 2500 m environ.
Hauteurs de neige observées : 236 cm à la nivôse des Ecrins à 2900 m, 121 cm au Pré de Madame Carle à 1900 m.

Limite d'enneigement skiable : à partir de 1700/1800 m en ubacs favorables (terrains herbeux, pistes forestières), 2300/2400 m en adrets pas trop raides.

État de la neige de surface : neige en cycle printanier. Après un regel nocturne plutôt efficace, reprise rapide de l'humidification au soleil. Neige restée sèche seulement au-dessus de 3000/3200 m en versants nord.

Aperçu météo pour le lundi 20 avril

Poursuite d'un temps plutôt ensoleillé et chaud. Rares averses isolées possibles l'après-midi.

	nuit	matin	après-midi	soir
Pluie-Neige				
Iso 0 °C	2 900 m	2 800 m	2 800 m	2 800 m
Vent 2000 m	→ 10 km/h	→ 15 km/h	→ 25 km/h	↘ 15 km/h
Vent 3000 m	↘ 20 km/h	↘ 25 km/h	→ 25 km/h	↘ 25 km/h

Épaisseur de neige hors-piste

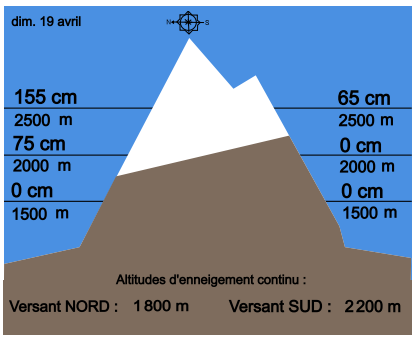

Précipitations à 1800 m

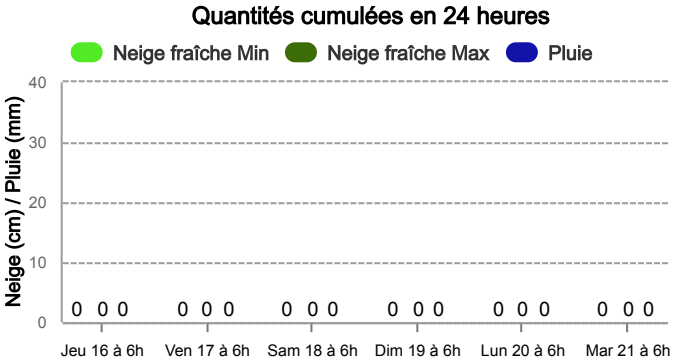

Tendance du mardi 21 avril

2

Indice de risque limité

Poursuite de l'humidification du manteau neigeux, avec des conditions généralement douces et ensoleillées.

Pour consulter la vigilance en cours, veuillez vous rendre sur le site https://vigilance.meteofrance.fr/fr

Météo-France - 73 avenue de Paris, 94165 Saint-Mandé cedex - Contact : contact@meteo.fr

Rédigé par Météo-France avec la contribution des observateurs du réseau nivo-météorologiques. Partenariat : ANMSM (Maires de Stations de Montagne), DSF (Domaines Skiables de France), ADSP (Directeurs de Pistes et de la Sécurité des Stations de Sports d'Hiver) et autres acteurs de la montagne.

Bulletin neige & avalanches par téléphone au
0 892 68 10 20 Service 0,35 € / min + prix appel

Bulletin d'estimation du risque d'avalanche

(valable en dehors des pistes balisées et ouvertes)

MASSIF : Pelvoux

Rédigé le dimanche 19 avril 2026 à 16h

Conditions nivo-météo des 7 derniers jours

	lun. 13/04				mar. 14/04				mer. 15/04				jeu. 16/04				ven. 17/04				sam. 18/04				dim. 19/04			
	03h	09h	15h	21h	03h	09h	15h	21h	03h	09h	15h	21h	03h	09h	15h	21h	03h	09h	15h	21h	03h	09h	15h	21h	03h	09h	15h	21h
Météo																												
Vent (km/h)	35	30	25	20	30	25	20	20	15	15	15	5	5	10	10	5	5	5	5	5	10	15	10	10	20	25	25	20
à 3000m																												
Vent (km/h)	15	15	20	20	15	15	20	15	10	10	15	5	5	10	15	5	5	5	5	0	0	5	2	2	10	15	25	15
à 2000m																												

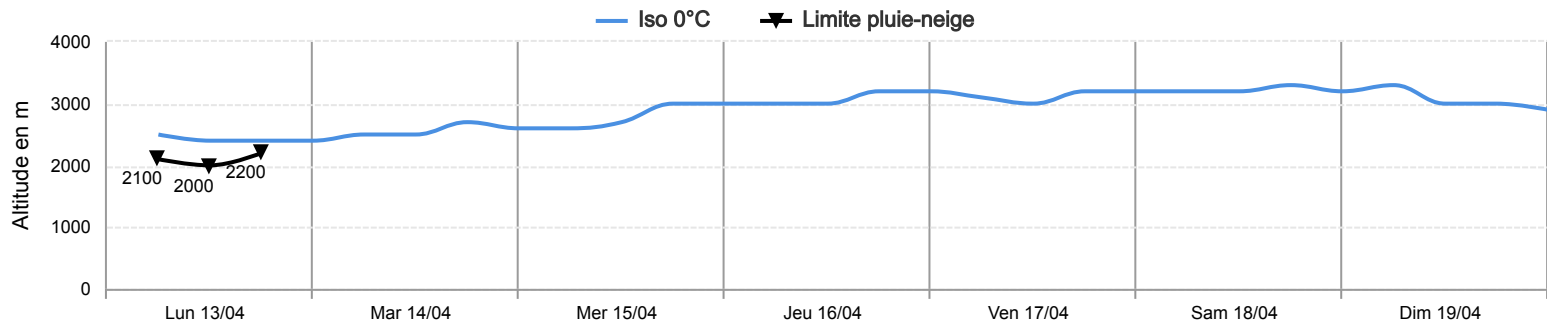

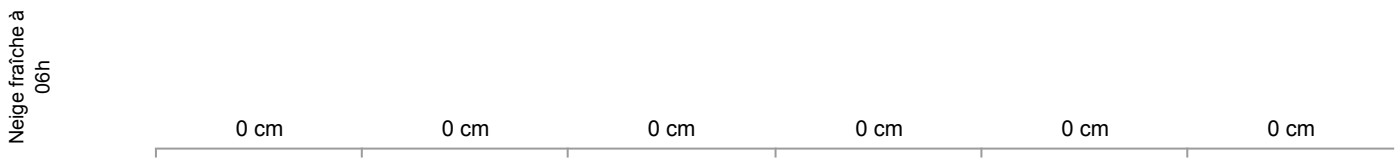

Risque d'avalanche	lun. 13/04	mar. 14/04	mer. 15/04	jeu. 16/04	ven. 17/04	sam. 18/04	dim. 19/04
	2	2	2	2	2	2	2

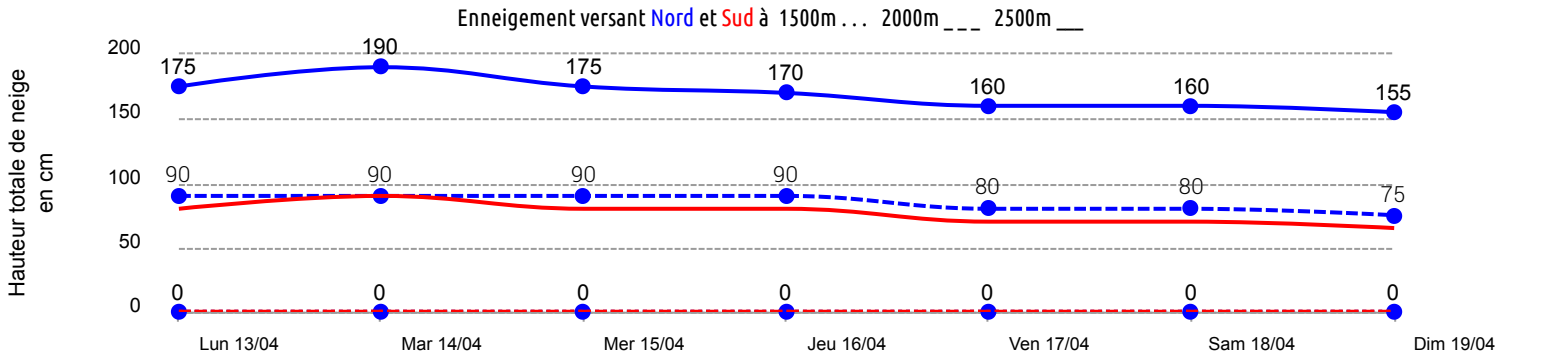

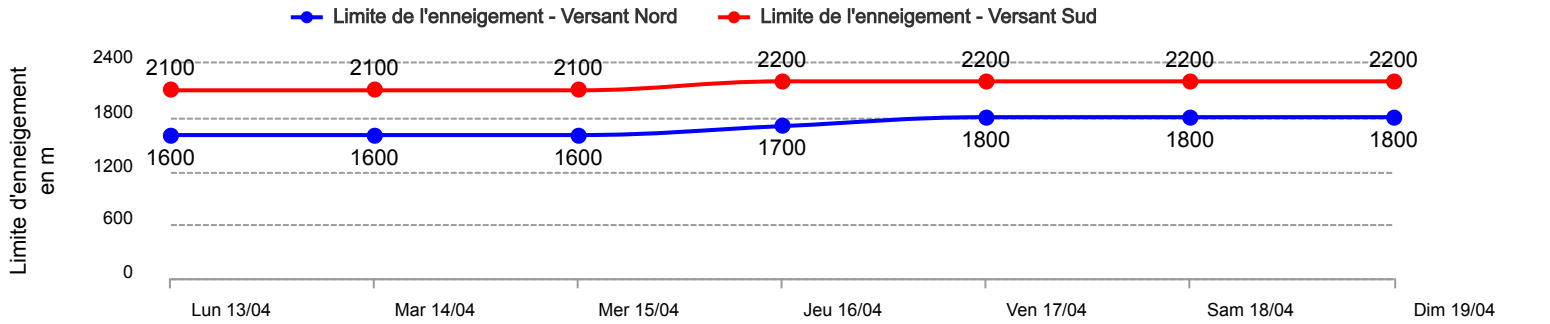

Pour consulter la vigilance en cours, veuillez vous rendre sur le site https://vigilance.meteofrance.fr/fr

Météo-France - 73 avenue de Paris, 94165 Saint-Mandé cedex - Contact : contact@meteo.fr

Rédigé par Météo-France avec la contribution des observateurs du réseau nivo-météorologiques. Partenariat : ANMSM (Maires de Stations de Montagne), DSF (Domaines Skiables de France), ADSP (Directeurs de Pistes et de la Sécurité des Stations de Sports d'Hiver) et autres acteurs de la montagne.

Bulletin neige & avalanches par téléphone au

0 892 68 10 20 Service 0,35 € / min + prix appel