Bulletin d'estimation du risque d'avalanche

(valable en dehors des pistes balisées et ouvertes)

MASSIF : Renoso Incudine

Rédigé le dimanche 19 avril 2026 à 16h

Estimation des risques pour le : LUNDI 20 AVRIL

MANTEAU NEIGEUX PRINTANIER

1

1

N O E S

Indice de risque faible.

Départs spontanés : Coulées de neige humide en journée dans les pentes raides

Déclenchements provoqués : Peu probables

Indices de risque : 5 très fort - 4 fort - 3 marqué - 2 limité - 1 faible -- En noir : les pentes les plus dangereuses

Stabilité du manteau neigeux

Situation avalancheuse typique : pas de situation prédominante

Départs spontanés : Le manteau neigeux est bien humidifié et bien tassé. En journée, sous l'effet de la douceur et de l'ensoleillement, des coulées ou petites avalanches de neige humide sont attendues dans les pentes raides et ensoleillées. À noter également qu'une avalanche de fond n'est pas exclue sur les dalles rocheuses (apparition de fissures de reptation).

Déclenchements provoqués : Peu probables. Un randonneur peut provoquer un départ superficiel sous les skis, en coupant une pente raide très humidifiée.

Autres : Présence de nombreuses corniches, susceptibles de rompre à cause des conditions printanières.

Qualité de la neige

Qualification de l'enneigement : L'enneigement est encore très bon pour la saison. À Ghisoni, on relève près de 2 m de neige vers 1800 à 1900 m d'altitude, parfois encore près de 4m dans certaines combes.

Limite d'enneigement skiable : vers 1600 à 1700 m en Nord, 1800 à 1900 m en Sud.

État de la neige : Regel nocturne correct en altitude, inexistant en dessous de 1800 à 2000 m. Rapide humidification en matinée. En moyenne montagne, la neige est très humide, généralement colorée par le sable. Elle devient dense et portante à partir de 1800 m, légèrement revenue en versants Sud dans la journée. Dans les pentes Nord et près des crêtes, on trouve des surfaces plus dures.

Aperçu météo pour le lundi 20 avril

	nuit	matin	après-midi	soir
Beau temps dans l'ensemble				
Pluie-Neige				
Iso 0 °C	3 200 m	3 100 m	3 200 m	3 200 m
Vent 1500 m	→ 25 km/h	→ 35 km/h	→ 40 km/h	↗ 25 km/h
Vent 2000 m	→ 35 km/h	→ 25 km/h	→ 25 km/h	→ 35 km/h

Épaisseur de neige hors-piste

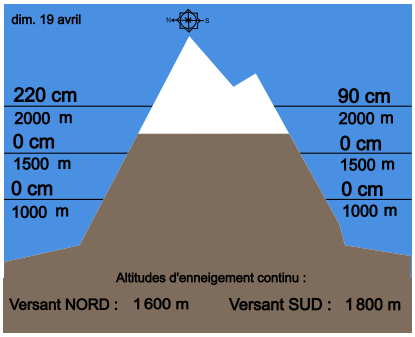

Précipitations à 1800 m

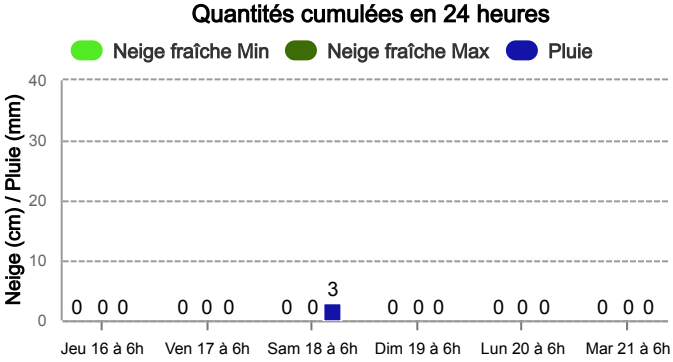

Tendance du mardi 21 avril

1

Indice de risque faible

Pas d'évolution notable en termes de risque.

Pour consulter la vigilance en cours, veuillez vous rendre sur le site https://vigilance.meteofrance.fr/fr

Météo-France - 73 avenue de Paris, 94165 Saint-Mandé cedex - Contact : contact@meteo.fr

Rédigé par Météo-France avec la contribution des observateurs du réseau nivo-météorologiques. Partenariat : ANMSM (Maires de Stations de Montagne), DSF (Domaines Skiables de France), ADSP (Directeurs de Pistes et de la Sécurité des Stations de Sports d'Hiver) et autres acteurs de la montagne.

Bulletin neige & avalanches par téléphone au 0 892 68 10 20 Service 0,35 € / min + prix appel

RÉPUBLIQUE FRANÇAISE
Liberté Égalité Fraternité

METEO FRANCE
À VOS CÔTÉS, DANS UN CLIMAT QUI CHANGE

Bulletin d'estimation du risque d'avalanche

(valable en dehors des pistes balisées et ouvertes)

MASSIF : Renoso Incudine

Rédigé le dimanche 19 avril 2026 à 16h

Conditions nivo-météo des 7 derniers jours

	lun. 13/04				mar. 14/04				mer. 15/04				jeu. 16/04				ven. 17/04				sam. 18/04				dim. 19/04			
	03h	09h	15h	21h	03h	09h	15h	21h	03h	09h	15h	21h	03h	09h	15h	21h	03h	09h	15h	21h	03h	09h	15h	21h	03h	09h	15h	21h
Météo																												
Vent (km/h)	70	40	25	10	10	10	20	25	30	30	35	30	20	20	15	30	20	15	15	20	15	20	15	15	10	15	30	25
à 2000m																												
Vent (km/h)	55	40	25	10	15	15	20	25	30	30	30	25	20	15	10	25	20	15	10	15	10	15	10	5	10	20	35	25
à 1500m																												

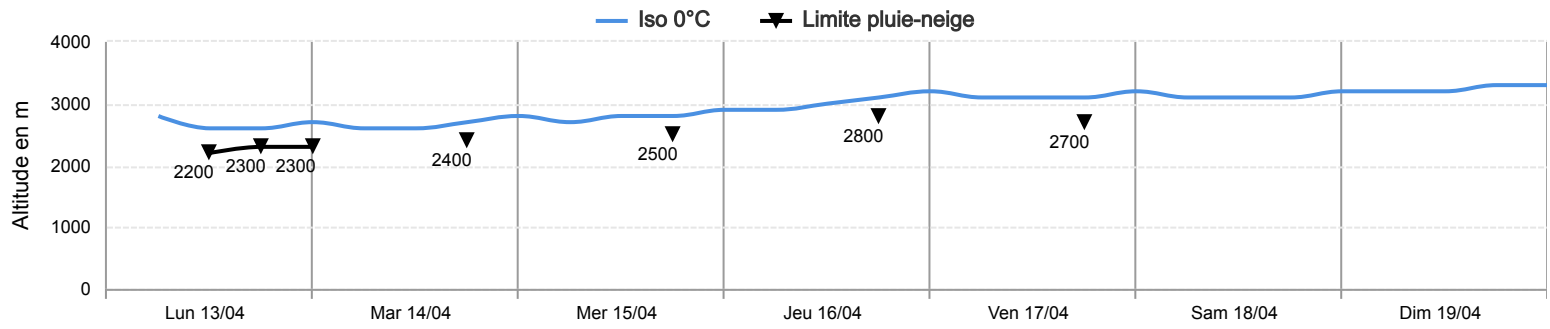

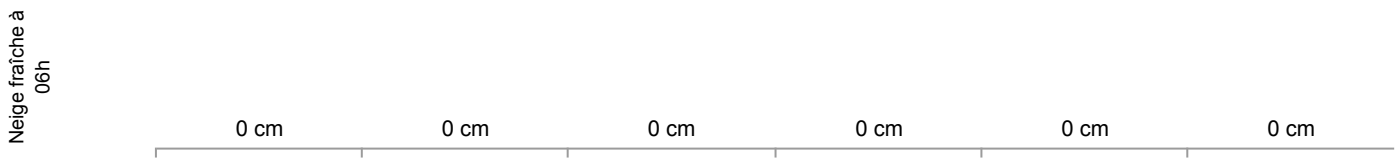

Risque d'avalanche	lun. 13/04	mar. 14/04	mer. 15/04	jeu. 16/04	ven. 17/04	sam. 18/04	dim. 19/04
	2	3	3	2	2	1	1

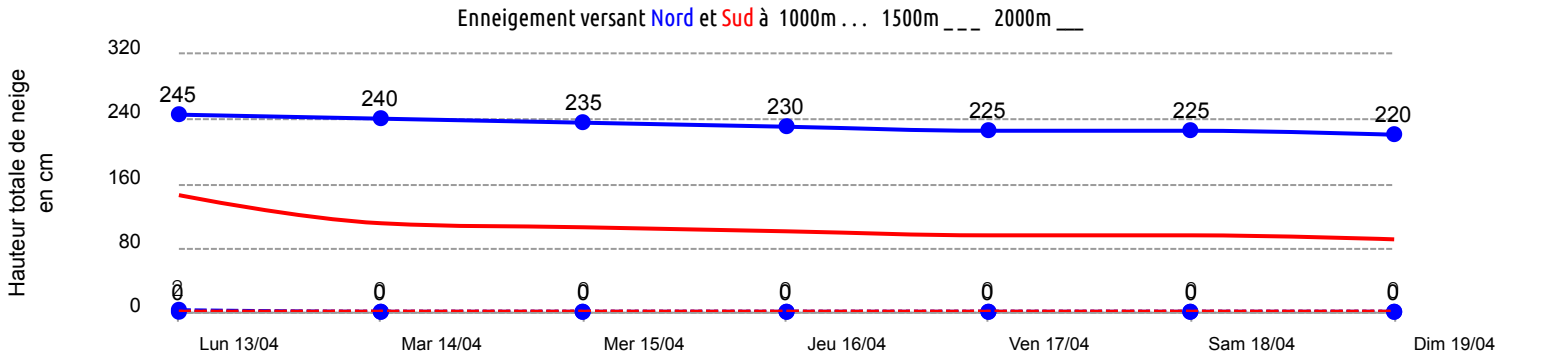

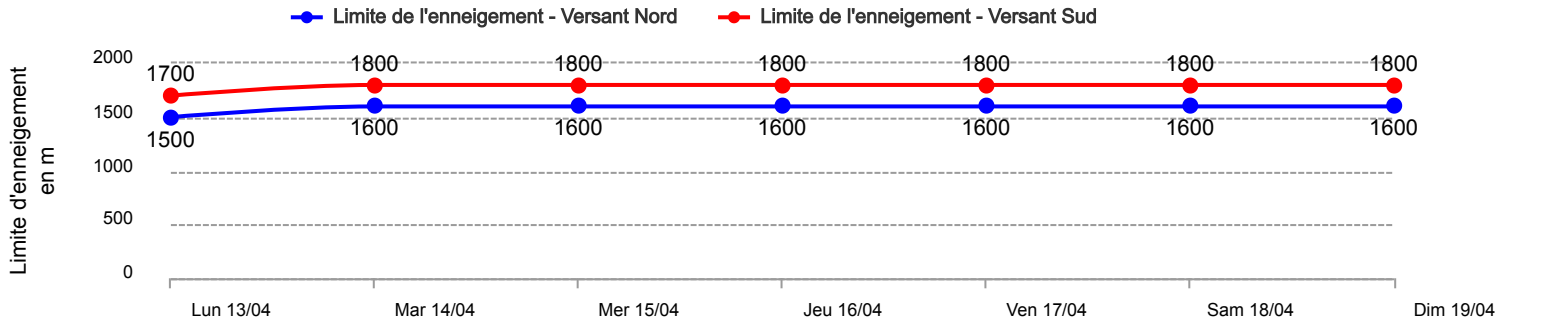

Pour consulter la vigilance en cours, veuillez vous rendre sur le site https://vigilance.meteofrance.fr/fr

Météo-France - 73 avenue de Paris, 94165 Saint-Mandé cedex - Contact : contact@meteo.fr

Rédigé par Météo-France avec la contribution des observateurs du réseau nivo-météorologiques. Partenariat : ANMSM (Maires de Stations de Montagne), DSF (Domaines Skiables de France), ADSP (Directeurs de Pistes et de la Sécurité des Stations de Sports d'Hiver) et autres acteurs de la montagne.

Bulletin neige & avalanches par téléphone au

0 892 68 10 20 Service 0,35 € / min + prix appel