GOBIERNO DE ESPAÑA
VICEPRESIDENCIA TERCERA DEL GOBIERNO
MINISTERIO PARA LA TRANSICIÓN ECOLÓGICA Y EL RETO DEMOGRÁFICO

Boletín de información nivológica y de peligro de aludes

Pirineo Navarro y Aragonés

aemet Agencia Estatal de Meteorología

lunes, 20 de abril de 2026

Pronóstico hasta las 24 horas del martes, día 21 de abril

(Válido fuera de pistas de esquí balizadas y abiertas)

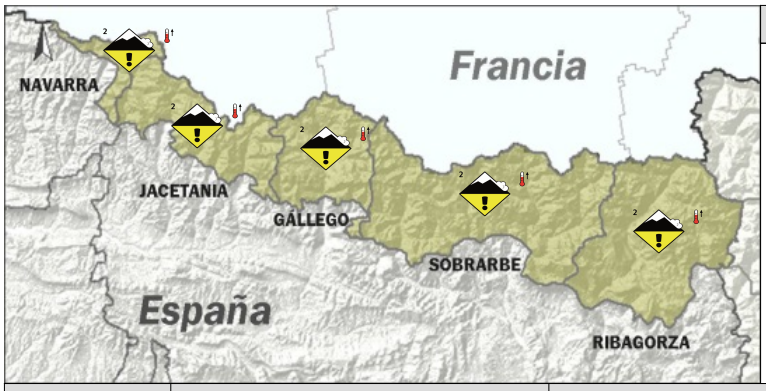

Problemas de aludes

Nieve húmeda

Deslizamientos basales

Macizo	Peligro	Problemas de aludes, cota, orientación, tamaño	Innivación observada (m)
Navarra	2 — 2 — Limitado	Nieve húmeda: 2 — N, O, E, S — 2 Deslizamientos basales: 2 — N, O, E, S — 2	2026-04-20 N / S Cota más baja caras N
Jacetania	2 — 2 — Limitado	Nieve húmeda: 2 — N, O, E, S — 2 Deslizamientos basales: 2 — N, O, E, S — 2	2026-04-20 N / S Cota más baja caras N
Gállego	2 — 2 — Limitado	Nieve húmeda: 2 — N, O, E, S — 2 Deslizamientos basales: 2 — N, O, E, S — 2	2026-04-20 N / S Cota más baja caras N

AEMET. Se autoriza la reproducción de su contenido citando la fuente.

Boletín de información nivológica y de peligro de aludes

Pirineo Navarro y Aragonés

Sobrarbe	2 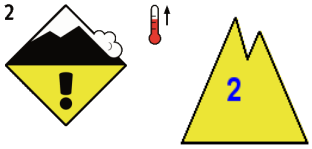 **Limitado**	**Nieve húmeda** 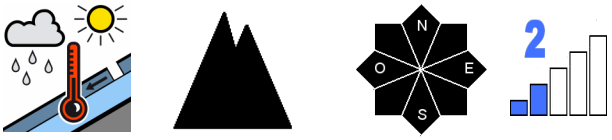 **Deslizamientos basales** 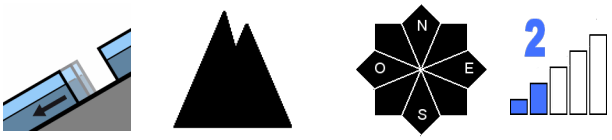	2026-04-20 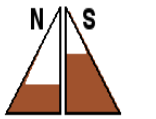 Cota más baja caras N
Ribagorza	2 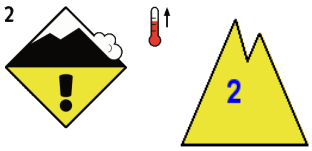 **Limitado**	**Nieve húmeda** **Deslizamientos basales** 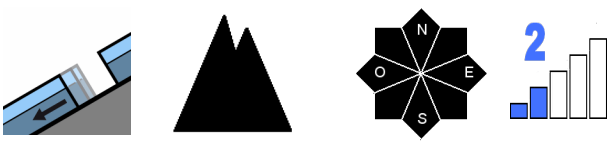	2026-04-20 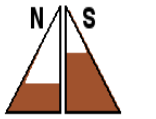 Cota más baja caras N

Estado del manto y observaciones recientes

Ayer por la tarde se registraron precipitaciones en forma de chubascos, superando localmente los 10l/m2 en 24 horas. Continúa el proceso de fusión y humidificación del manto como consecuencia de las cada vez más altas temperaturas y la fuerte insolación, registrándose pérdidas diarias en la cubierta nivosa. Esta mañana las pérdidas han sido mayores que en días anteriores debido al aporte de humedad de los chubascos, alcanzado localmente los 20 cm en la red de observación.
Con todo esto, el manto ha ido retrocediendo a altitudes cada vez más elevadas, más intensamente en las solanas. A pesar de ello, aún podemos encontrar cantidades que superan holgadamente los 100 cm por encima de 2100 metros en numerosas zonas, aún más en ventisqueros y otras áreas propensas a a la acumulación.
El manto es típicamente primaveral, con nieve muy humedecida y predominio de grano redondo. El rehielo nocturno es débil, poco efectivo y está restringido a la alta montaña.

Evolución del manto y peligro de aludes para el martes, día 21

Problemas de nieve húmeda y deslizamientos basales.

Mañana volverán a ascender las temperaturas y la fuerte insolación de días anteriores continuará, con un rehielo nocturno que quedará restringido a las cumbres de mayor altitud. Además se esperan nuevos chubascos, sobre todo durante las horas vespertinas, que allá donde caigan contribuirán a humidificar aún más un manto compuesto por nieve vieja y muy evolucionada.
Con todo esto, los problemas de nieve húmeda se presentarán ya desde el comienzo del día, afectando pronto a todas las orientaciones e incrementándose durante las horas centrales. En laderas suficientemente inclinadas, serán probables las purgas de tamaño pequeño (peligro de caída) o mediano (capaz de enterrar a una persona), más probables y frecuentes en solanas a partir del mediodía y durante los chubascos, preferentemente en lugares próximos a

AEMET. Se autoriza la reproducción de su contenido citando la fuente.

afloramientos rocosos.
Además, en zonas de manto delgado sobre laderas herbosas o de roca lisa, también podrán suceder deslizamientos basales de tamaño generalmente mediano, sin descartar alguno localmente grande (capaz de enterrar a un grupo de personas).

Predicción meteorológica para el martes, día 21

Poco nuboso con nubes altas aumentando a intervalos nubosos, con nubes medias, altas y, sobre todo por la tarde, nubosidad de evolución diurna. Se esperan chubascos ocasionales, más probables durante la segunda mitad del día, cuando no se descarta que en algún caso puedan ser localmente fuertes y con granizo. Cota de nieve en torno a 2700-2900 metros. Se esperan tormentas acompañando a los chubascos. Temperaturas generalmente en ligero ascenso, localmente moderado. Alguna helada débil y dispersa en la alta montaña. Soplarán vientos flojos o moderados de componentes oeste y sur, pudiendo ser fuertes, racheados y de dirección variable durante los chubascos o tormentas.

Datos en la atmósfera libre:

Altitud de la isoterma de 0 ºC: 3300 m
Altitud de la isoterma de -10 ºC: 4600 m

Viento a 1500 m: SW 10 km/h
Viento a 3000 m: SW 20 km/h

Evolución para el miércoles día 22

Nivel de peligro sin cambios.

(Información elaborada a partir de los datos recibidos de los refugios de Linza, Lizara, Respomuso, Panticosa, Bachimaña, Góriz, Pineta, Estós, Angel Orús, La Renclusa, Cap de Llauset y Belagua, de la estación de esquí de Panticosa (lagos) y de Ordesa Pradera)

Escala europea de peligro de aludes

Débil | Limitado | Notable | Fuerte | Muy Fuerte

Problemas de aludes

Nieve reciente | Placas de viento | Capas débiles persistentes | Nieve húmeda | Deslizamientos basales | Sin problema evidente

Nota1: Se recuerda que, siempre que haya nieve, la ausencia total de peligro no existe. Hay que tener presente que en circunstancias desfavorables, con aludes de tamaño 1 (alud pequeño o colada) y tamaño 2 (alud mediano), se pueden sufrir severos daños personales.
Nota2: Los BPA se elaboran en base a información meteorológica así como al estado del manto nivoso a través de sondeos puntuales. Se advierte a los usuarios de la variabilidad de esta información al extrapolarla a zonas extensas de montaña. Por ello, AEMET no se hace responsable de su uso para la toma de decisiones que conciernen a la seguridad personal, ni de los riesgos físicos o materiales de ellas derivadas.

AEMET. Se autoriza la reproducción de su contenido citando la fuente.