Dienstag 21.04.2026

Veröffentlicht am 20.04.2026 um 17:00

Vormittag

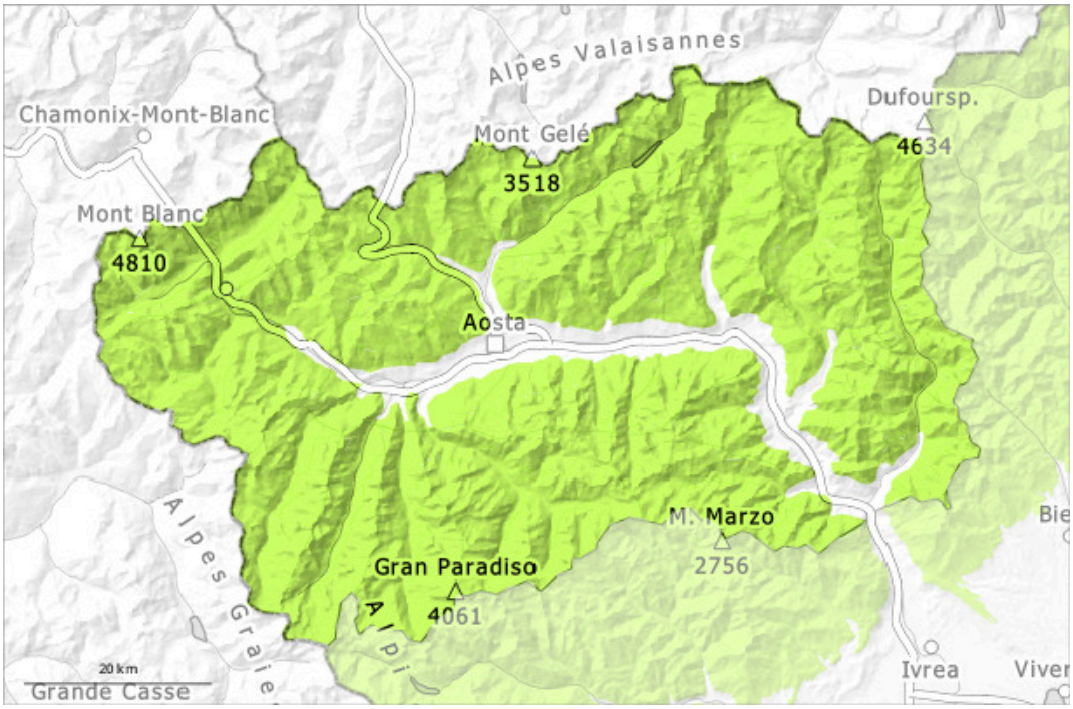

Nachmittag

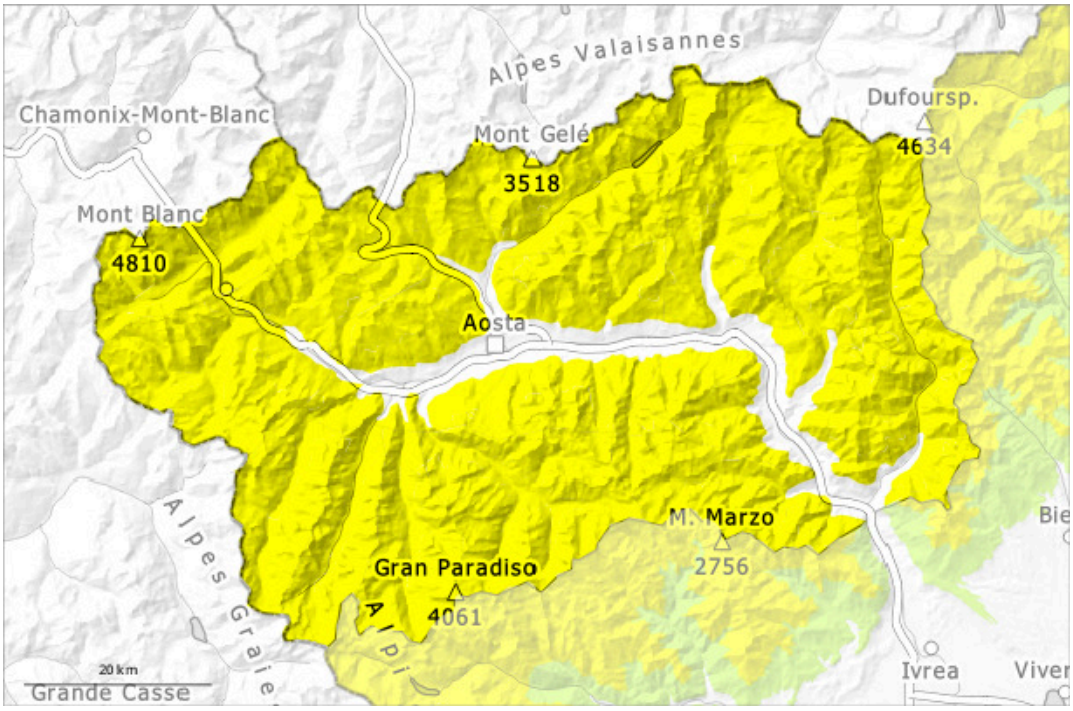

1	2	3	4	5
gering	mäßig	erheblich	groß	sehr groß

Gefahrenstufe 2 - Mäßig

AM:

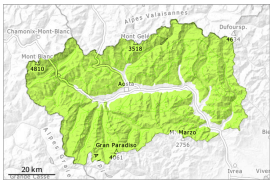

1

Tendenz: Lawinengefahr nimmt ab
am Mittwoch, den 22.04.2026

PM:

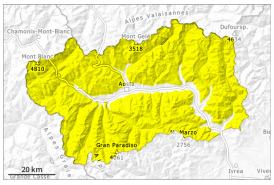

2

Tendenz: Lawinengefahr nimmt ab
am Mittwoch, den 22.04.2026

Nassschnee

N
S

2800m
2200m

Die Gefahr von feuchten und nassen Lawinen steigt im Tagesverlauf etwas an.

Morgen: Die Schneeoberfläche gefriert tragfähig und weicht später auf als am Vortag. Auf der harten Schneeoberfläche besteht im Steilgelände Absturzgefahr.

Die spontane Aktivität von Lawinen nimmt im Tagesverlauf allmählich zu.
Vor allem aus noch nicht entladenen Einzugsgebieten und an sehr steilen Schattenhängen sind weiterhin kleine und mittlere spontane nasse Lawinen möglich.
Für Skitouren sind die Verhältnisse mehrheitlich günstig. Touren und Hüttenaufstiege sollten rechtzeitig beendet werden.
Die oberflächennahen Schneeschichten können vor allem im extremen Steilgelände vereinzelt von Wintersportlern ausgelöst werden.

Schneedecke

Gefahrenmuster gm.10: frühjahrssituation

In den letzten zwei Tagen blies der Wind besonders entlang der Grenze zu Frankreich zeitweise mäßig.
Die Wetterbedingungen führten zu einer raschen Setzung der Schneedecke.
Diese Situation führte unterhalb von rund 2500 m zu einer Anfeuchtung der Schneedecke.
Es liegen kleinräumig stark unterschiedliche Schneehöhen.
Vor allem unterhalb der Waldgrenze liegt an Südost- und Südwesthängen kaum Schnee.
Besonders in hohen Lagen und im Hochgebirge liegt noch viel Schnee.
In der Schneedecke sind v.a. an steilen Schattenhängen Schwachschichten vorhanden.

Tendenz

Mit der Abkühlung sind nur noch vereinzelt feuchte und nasse Lawinen möglich.