aineva.it

# Dienstag 21.04.2026

Veröffentlicht am 20.04.2026 um 17:00

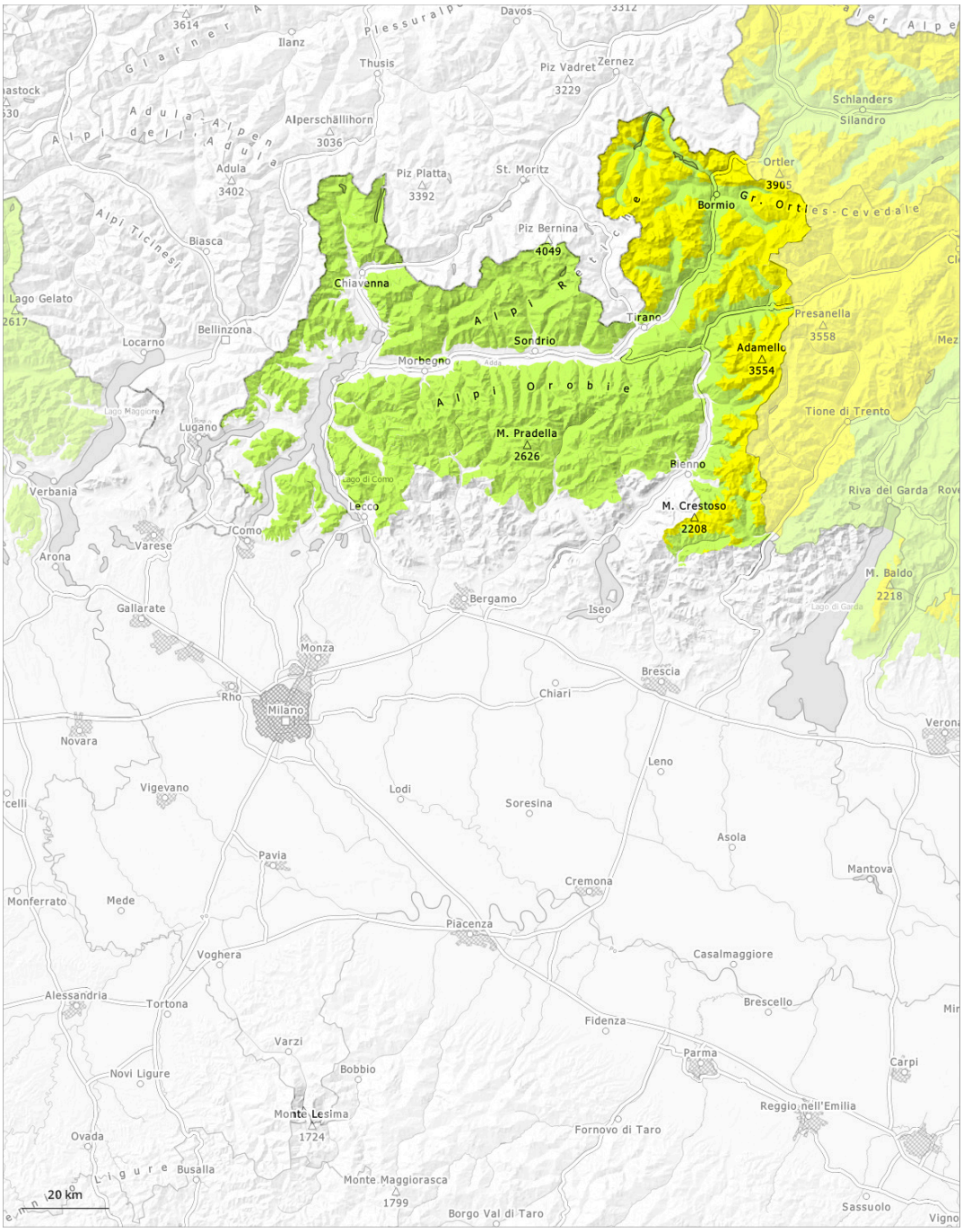


| 1 | 2 | 3 | 4 | 5 |
|---|---|---|---|---|
| gering | mäßig | erheblich | groß | sehr groß |

## Gefahrenstufe 2 - Mäßig

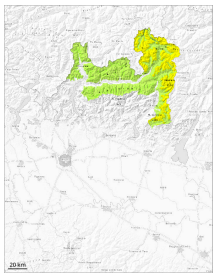

**2800m**

**Tendenz: Lawinengefahr bleibt gleich**
am Mittwoch, den 22.04.2026

Altschnee

**2800m**

Nassschnee

**2800m**

Die Schneeoberfläche ist nur in hohen Lagen tragfähig gefroren und weicht im Tagesverlauf auf. Im unteren Teil der Schneedecke sind an steilen Schattenhängen kantig aufgebaute Schwachschichten vorhanden.

Die Gefahrenstellen für trockene Lawinen liegen an steilen Schattenhängen oberhalb von rund 2800 m.
Mit der tageszeitlichen Erwärmung und der Sonneneinstrahlung steigt die Auslösebereitschaft von nassen Lawinen v.a. an steilen Schattenhängen unterhalb von rund 2800 m an.
Mittlere Lawinen sind möglich.

### Schneedecke

**Gefahrenmuster** gm.1: bodennahe schwachschicht | gm.10: frühjahrssituation

Die Schneeoberfläche weicht im Tagesverlauf auf.
Steile Schattenhänge oberhalb von rund 2800 m: Im unteren Teil der Altschneedecke sind kantig aufgebaute Schwachschichten vorhanden.
Unterhalb von rund 2100 m liegt für Schneesport meist zu wenig Schnee.

## Gefahrenstufe 1 - Gering

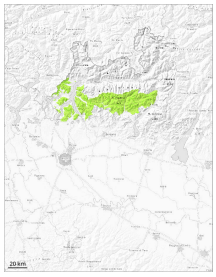

1

**Tendenz: Lawinengefahr bleibt gleich**
am Mittwoch, den 22.04.2026

Nassschnee

2000m

### Die Schneeoberfläche ist nur in hohen Lagen tragfähig gefroren und weicht schon am Vormittag auf.

Die Schneeoberfläche gefriert nur knapp und weicht im Tagesverlauf auf.
Die Lawinen sind vereinzelt klein.

### Schneedecke

**Gefahrenmuster** gm.10: frühjahrssituation

Mit milden Temperaturen verfestigte sich die Schneedecke. Mit der tageszeitlichen Erwärmung steigt die Gefahr von feuchten und nassen Lawinen an.