Dienstag 21.04.2026

Veröffentlicht am 20.04.2026 um 17:00

Vormittag

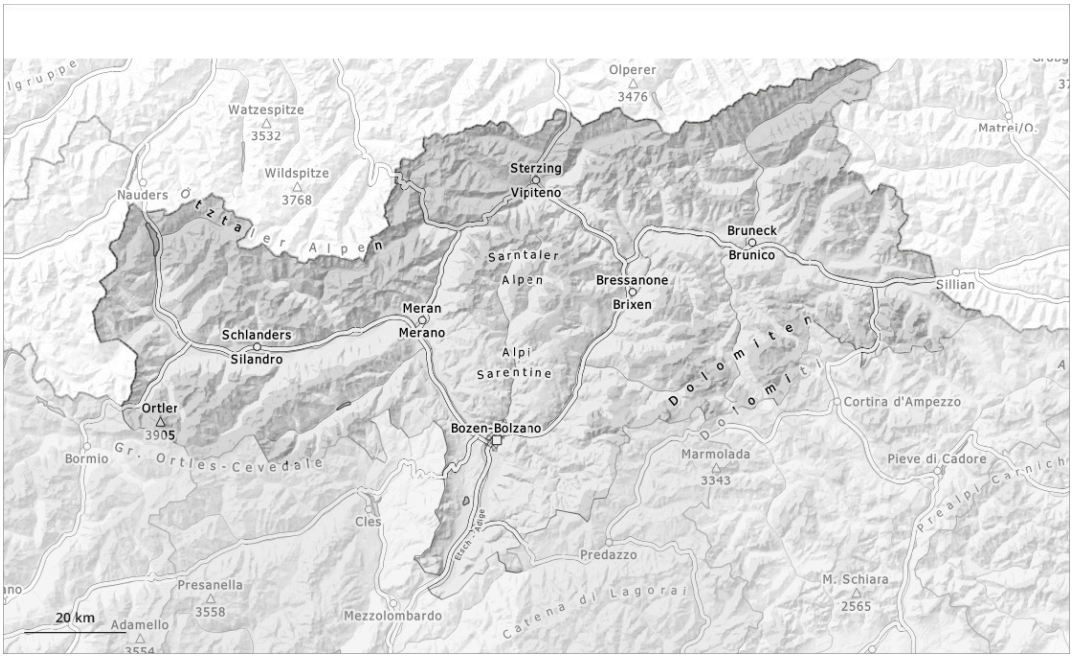

Nachmittag

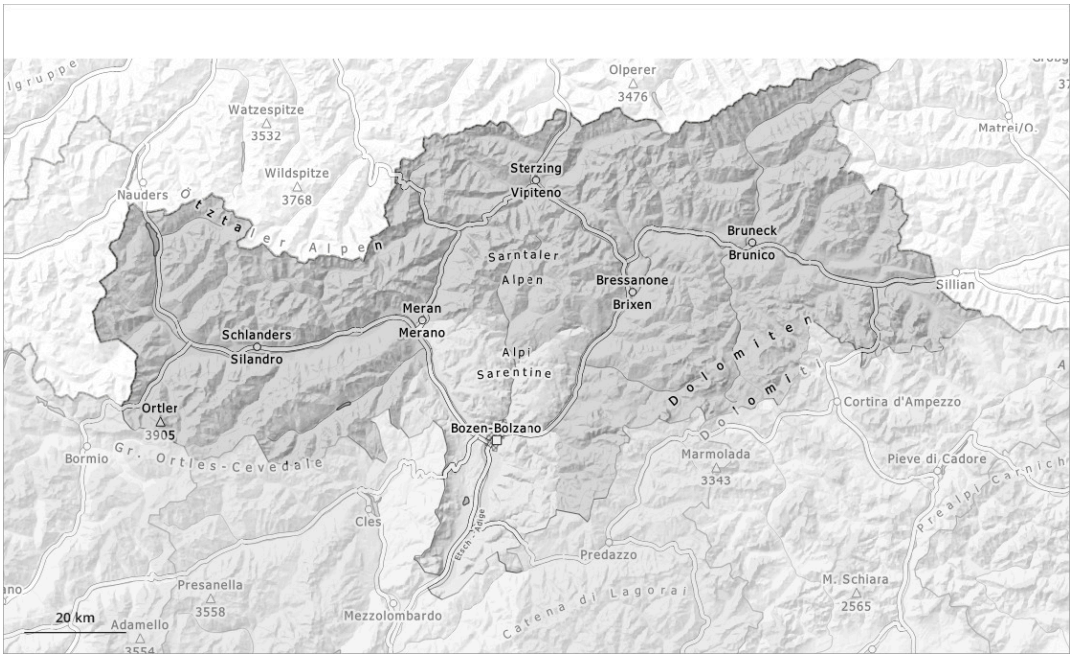

1	2	3	4	5
gering	mäßig	erheblich	groß	sehr groß

Gefahrenstufe 2 - Mäßig

Tendenz: Lawinengefahr bleibt gleich
am Mittwoch, den 22.04.2026

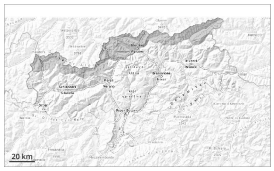

Nassschnee

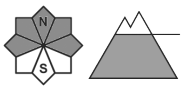

Altschnee

Vorsicht vor schwachem Altschnee und Nassschnee.

Leichter Anstieg der Gefahr von nassen Lawinen mit der tageszeitlichen Erwärmung.
Nasse Lawinen können vereinzelt von einzelnen Wintersportlern ausgelöst werden. Diese können sehr vereinzelt den schwachen Altschnee mitreißen und groß werden. Dies an sehr steilen Schattenhängen unterhalb von rund 2500 m.

Zudem können trockene Lawinen vereinzelt schon mit geringer Belastung ausgelöst werden, besonders an sehr steilen Nordwest-, Nord- und Nordosthängen oberhalb von rund 2500 m. Ungünstig sind besonders Übergänge von wenig zu viel Schnee. Die Gefahrenstellen sind schwer zu erkennen.

Schneedecke

Gefahrenmuster gm.10: frühjahrssituation | gm.1: bodennahe schwachschicht

In den letzten Tagen fielen gebietsweise bis zu 10 cm Schnee, lokal auch mehr.

Die nächtliche Abstrahlung ist teilweise reduziert. Die Schneeoberfläche gefriert kaum.
Die Schneedecke ist feucht, v.a. an Sonnenhängen in allen Höhenlagen sowie an West-, Nord- und Osthängen unterhalb von rund 2500 m. Steile West-, Nord- und Osthänge: Im unteren Teil der Altschneedecke sind in der Höhe kantig aufgebaute Schwachschichten vorhanden.

Tendenz

Die nächtliche Abstrahlung ist recht gut. Die Gefahr von nassen Lawinen steigt im Tagesverlauf etwas an.

Gefahrenstufe 2 - Mäßig

AM:

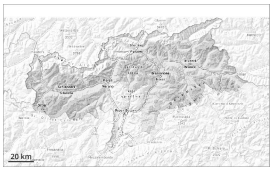

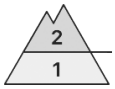

2500m

Tendenz: Lawinengefahr bleibt gleich
am Mittwoch, den 22.04.2026

Altschnee

2500m

PM:

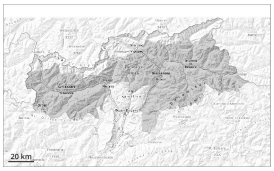

Tendenz: Lawinengefahr bleibt gleich
am Mittwoch, den 22.04.2026

Nassschnee

2500m

Altschnee

2500m

Leichter Anstieg der Gefahr von nassen Lawinen im Tagesverlauf.

Mit der tageszeitlichen Erwärmung und der Sonneneinstrahlung steigt die Gefahr von nassen Lawinen im Tagesverlauf etwas an. Nasse Lawinen können vereinzelt von einzelnen Wintersportlern ausgelöst werden. Dies an sehr steilen Schattenhängen unterhalb von rund 2500 m sowie an sehr steilen Sonnenhängen in der Höhe.

Einzelne Gefahrenstellen für trockene Lawinen liegen an sehr steilen Schattenhängen oberhalb von rund 2500 m. Ungünstig sind besonders Übergänge von wenig zu viel Schnee. Die Gefahrenstellen sind schwer zu erkennen.

Schneedecke

Gefahrenmuster gm.10: frühjahrssituation | gm.1: bodennahe schwachschicht

Die nächtliche Abstrahlung ist zeitweise reduziert. Die Schneeoberfläche gefriert tragfähig und weicht im Tagesverlauf auf. Sonne und Wärme führen in mittleren und hohen Lagen zu einer raschen Aufweichung der Schneedecke.
Schattenhänge oberhalb von rund 2500 m: Im unteren Teil der Altschneedecke sind in der Höhe kantig aufgebaute Schwachschichten vorhanden.
An steilen Sonnenhängen sowie unterhalb von rund 1800 m liegt kaum Schnee.

Nachmittag: Es fällt etwas Schnee, vor allem in hohen Lagen und im Hochgebirge.

Tendenz

Die Gefahr von nassen Lawinen bleibt bestehen.

Gefahrenstufe 1 - Gering

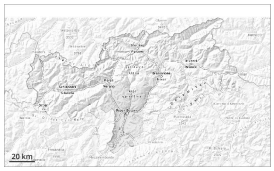

1

Tendenz: Lawinengefahr bleibt gleich
am Mittwoch, den 22.04.2026

Nassschnee

N
S

2000m

Nassschnee beachten.

Es sind nur noch vereinzelt nasse Lawinen möglich. Vorsicht an extrem steilen Schattenhängen. Lawinen sind meist eher klein.

Schneedecke

Gefahrenmuster gm.10: frühjahrssituation gm.1: bodennahe schwachschicht

Die Schneeoberfläche gefriert tragfähig und weicht im Tagesverlauf auf.

Tendenz

Geringe Lawinengefahr. Nassschnee beachten.