Dienstag 21.04.2026

Veröffentlicht am 20.04.2026 um 17:00

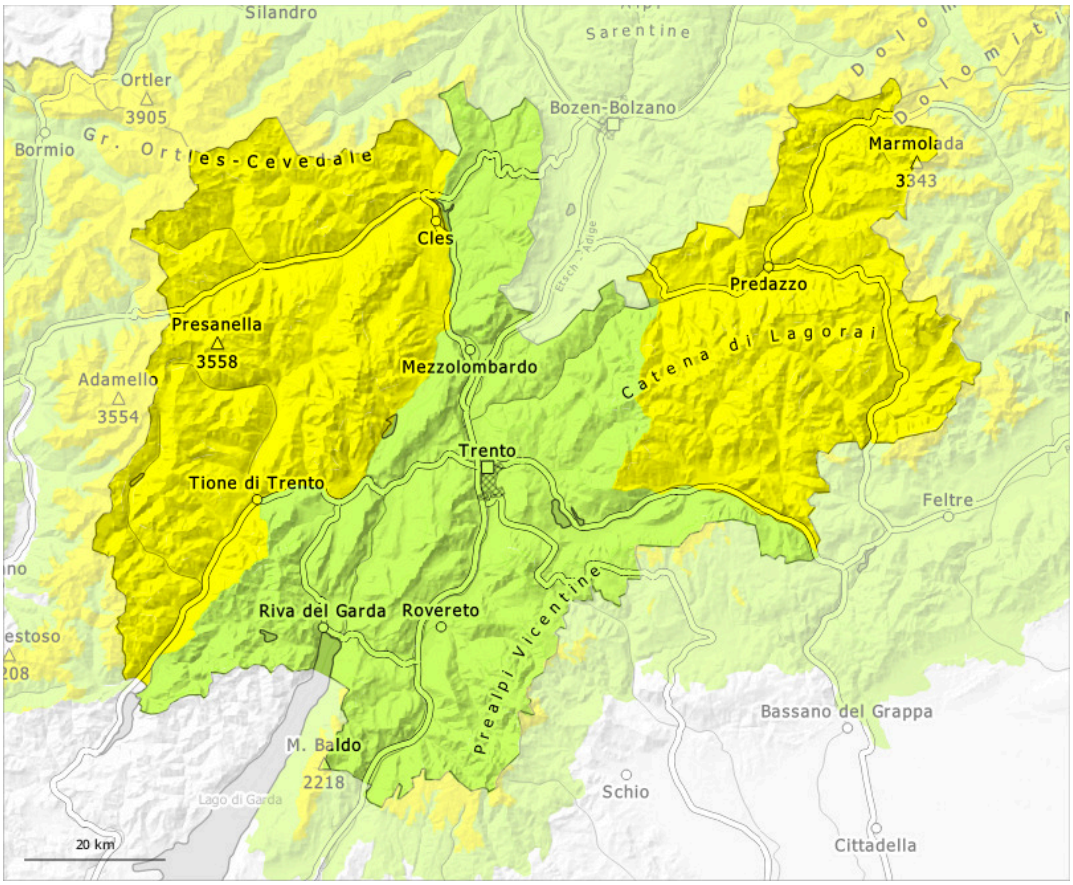

1	2	3	4	5
gering	mäßig	erheblich	groß	sehr groß

Gefahrenstufe 2 - Mäßig

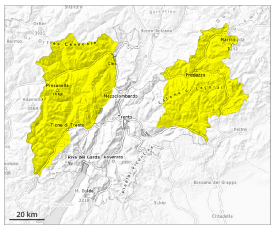

Tendenz: Lawinengefahr bleibt gleich
am Mittwoch, den 22.04.2026

Nassschnee

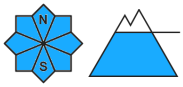

2700m

Altschnee

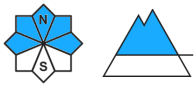

2400m

Anstieg der Gefahr von nassen Lawinen im Tagesverlauf.

Mit der tageszeitlichen Erwärmung und der Sonneneinstrahlung steigt die Gefahr von nassen Lawinen an. Aus noch nicht entladenen Einzugsgebieten sind spontane Lawinen möglich, vor allem solche mittlerer Größe. Dies an Schattenhängen unterhalb von rund 2900 m sowie an Sonnenhängen in der Höhe. Lawinen können an steilen Schattenhängen im schwachen Altschnee anreißen und vereinzelt groß werden.

Einzelne Gefahrenstellen für trockene Lawinen liegen an sehr steilen Schattenhängen oberhalb von rund 2400 m. Solche Gefahrenstellen sind schwer zu erkennen.

Touren und Variantenabfahrten sollten früh gestartet und beendet werden.

Schneedecke

Gefahrenmuster gm.10: frühjahrssituation | gm.1: bodennahe schwachschicht

Es fällt gebietsweise etwas Schnee. Die Schneeoberfläche weicht im Tagesverlauf auf. Sonne und Wärme führen unterhalb von rund 2700 m zu einer zunehmenden Durchnässung der Schneedecke.
Steile West-, Nord- und Osthänge oberhalb von rund 2400 m: Im unteren Teil der Altschneedecke sind kantig aufgebaute Schwachschichten vorhanden.
Unterhalb von rund 1800 m liegt für Schneesport meist zu wenig Schnee.

Tendenz

Mittwoch: Die Lawinengefahr bleibt bestehen.

Gefahrenstufe 1 - Gering

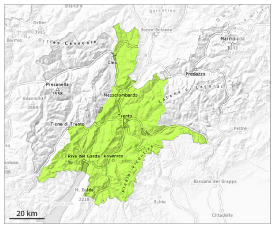

1

Tendenz: Lawinengefahr bleibt gleich
am Mittwoch, den 22.04.2026

Nassschnee beachten.

Es sind nur noch vereinzelt nasse Lawinen möglich. Vorsicht an extrem steilen Schattenhängen. Lawinen sind meist eher klein.

Unterhalb von rund 2000 m liegt für Schneesport meist zu wenig Schnee.

Schneedecke

Gefahrenmuster gm.10: frühjahrssituation

Die Schneeoberfläche weicht im Tagesverlauf auf.

Tendenz

Mittwoch: Die Lawinengefahr bleibt bestehen.