ICGC Institut Cartogràfic i Geològic de Catalunya

Servei Meteorològic de Catalunya meteo.cat

Boletín de peligro de aludes para el Pirineo de Catalunya
Del 20/04/2026 al 21/04/2026

(Válido fuera pistas de esquí y zonas no controladas)

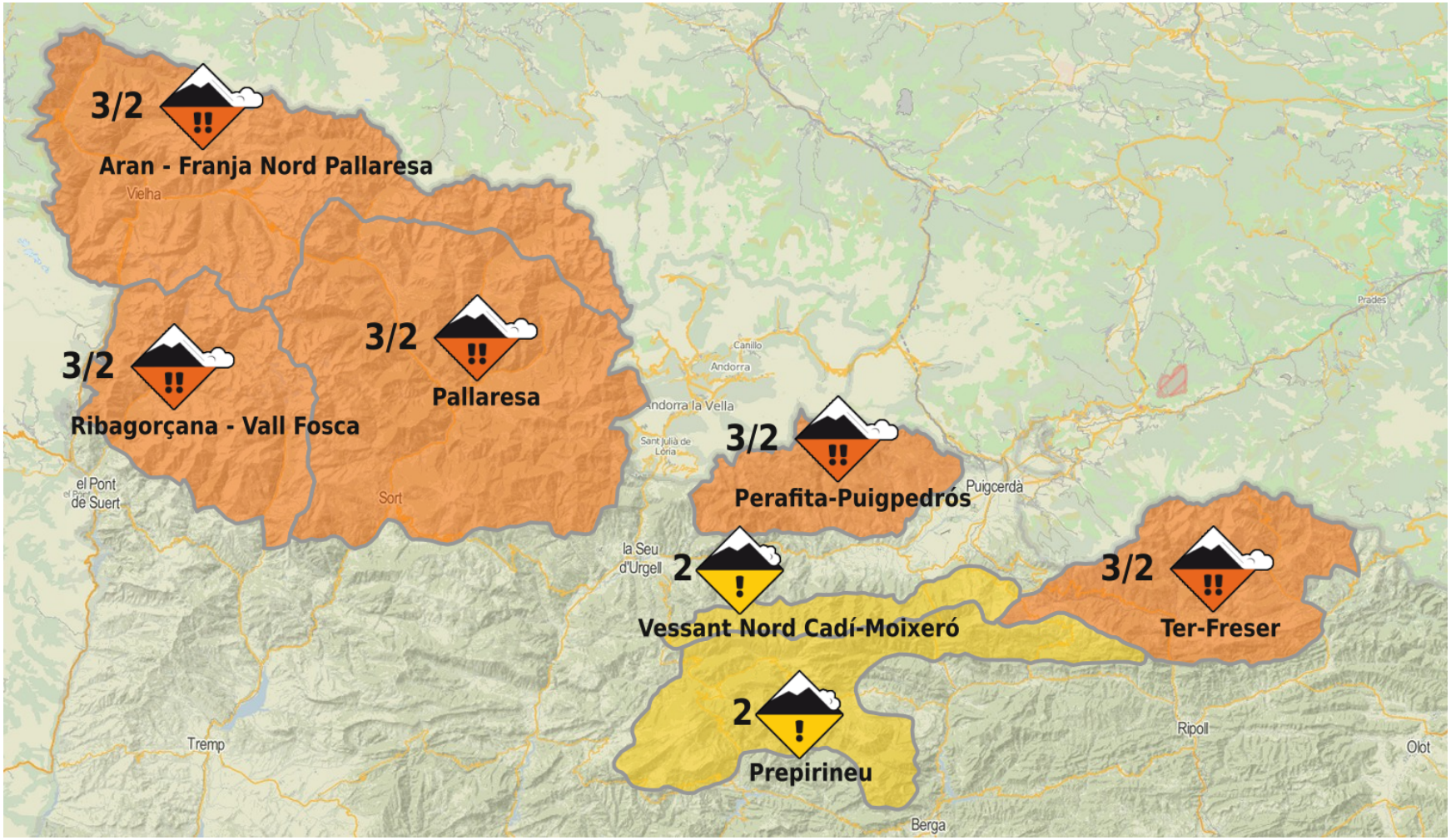

5 MUY FUERTE	4 FUERTE	3 NOTABLE	2 LIMITADO	1 DÉBIL

ICGC Institut Cartogràfic i Geològic de Catalunya

Servei Meteorològic de Catalunya

Boletín de peligro de aludes Aran - Franja Nord Pallaresa Del 20/04/2026 al 21/04/2026

(Válido fuera pistas de esquí y zonas no controladas)

Notable (3) en la Franja Norte de la Pallaresa Limitado (2) en el Aran

Situación primaria

Deslizamientos basales **Distribución** **Tamaño** **Origen** **Tendencia**

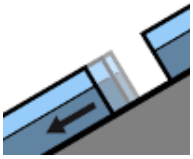

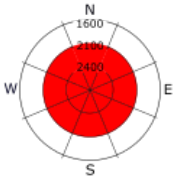

Situación secundaria

Nieve húmeda **Distribución** **Tamaño** **Origen** **Tendencia**

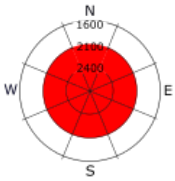

Estado del manto nivoso

El manto nivoso se encuentra húmedo durante el día y con cierto rehielo de noche y madrugada. Durante el fin de semana ha habido deslizamientos basales y aludes de fusión. S esperan chubascos primaverales el lunes y el martes. En estas condiciones se espera que continúen los deslizamientos basales de hasta tamaño 3 (capacidad de cibrir a un grupo) en la Franja norte de la Pallaresa; en el Aran no se descarta alcanzar el tamaño 3 puntualmente. Además son muy probables las caídas naturales de aludes de fusión, que serán de tamaño 2 (mediano, con capacidad de cubrir una persona). Las caídas de aludes y deslizamientos, afectan a cualquier orientación. Por encima de los 2200 m es donde las medidas de los aludes pueden ser de mayor alcance dado que el grosor movilizable de nieve es mayor. Hay que prestar atención a la aparición de grietas para evitar los deslizamientos y evitar sobre todo los momentos de lluvia. De noche y madrugada el rehielo favorecerá levemente la estabilidad

Distribución del manto nivoso

Hay nieve en el suelo con continuidad por encima de 1.800-1.900 m en umbrías y de 2.000 m en solanas. Los espesores a unos 2.200 m rondan los 130-210 cm. Los valores están por encima de los normales por la época.

Tendencia para las próximas 48-72h

Se mantendrá la situación de fusión. Evolución del peligro: EN LEVE DESCENSO

El próximo boletín será emitido el día 2026-04-21

5 MUY FUERTE	4 FUERTE	3 NOTABLE	2 LIMITADO	1 DÉBIL

EAWS EUROPEAN AVALANCHE WARNING SERVICES

ICGC Institut Cartogràfic i Geològic de Catalunya

meteo.cat Servei Meteorològic de Catalunya

Boletín de peligro de aludes Ribagorçana - Vall Fosca Del 20/04/2026 al 21/04/2026

(Válido fuera pistas de esquí y zonas no controladas)

Notable (3) en el extremo norte
Limitado (2) en el resto.

Situación primaria

Deslizamientos basales | **Distribución** | **Tamaño** | **Origen** | **Tendencia**

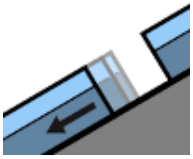

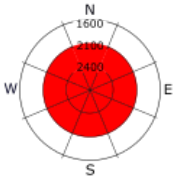

Situación secundaria

Nieve húmeda | **Distribución** | **Tamaño** | **Origen** | **Tendencia**

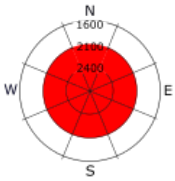

Estado del manto nivoso

El manto se mantiene húmedo de día y se encostra de noche y madrugada. Con los chubascos primaverales previstos para el lunes y el martes en forma de agua hasta cotas altas, se prevé el humedecimiento del manto y que continúe la caída de deslizamientos basales y aludes de fusión. Los deslizamientos basales pueden tener tamaño para enterrarnos (tamaño 2, mediano) e incluso pueden alcanzar tamaño suficiente para tapar un grupo (tamaño 3, grande) en el extremo norte del sector. Las vertientes más proclives son las vertientes de suelo herboso. Los aludes de fusión pueden tener tamaño suficiente para enterrarnos. Las orientaciones afectadas por deslizamientos y por aludes de fusión son todos y los tamaños de los aludes de mayor alcance serán en el extremo norte de este sector y por encima de los 2200 m, donde el grosor movilizable de nieve es mayor. De noche y madrugada el rehielo favorezca levemente la estabilidad.

Distribución del manto nivoso

Hay nieve por encima de 1.800-2.000 m pero esquiable en N por encima de 2.100 m-2.300 m en S. Se alcanzan los 70-90 cm a unos 2.200 m, con frecuentes deflaciones y acumulaciones por encima del nivel del bosque. Estos valores están ligeramente por debajo de los normales para la época.

Tendencia para las próximas 48-72h

Se mantendrá la situación de fusión. Evolución del peligro: EN LEVE DESCENSO

El próximo boletín será emitido el día 2026-04-21

5 MUY FUERTE	4 FUERTE	3 NOTABLE	2 LIMITADO	1 DÉBIL

EAWS EUROPEAN AVALANCHE WARNING SERVICES

ICGC Institut Cartogràfic i Geològic de Catalunya

Servei Meteorològic de Catalunya

Boletín de peligro de aludes Pallaresa
Del 20/04/2026 al 21/04/2026

(Válido fuera pistas de esquí y zonas no controladas)

Notable (3) en el extremo norte, Limitado (2) en el resto.

Situación primaria

Deslizamientos basales | **Distribución** | **Tamaño** | **Origen** | **Tendencia**

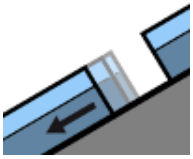

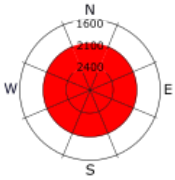

Situación secundaria

Nieve húmeda | **Distribución** | **Tamaño** | **Origen** | **Tendencia**

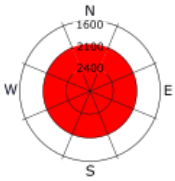

Estado del manto nivoso

El manto se mantiene húmedo de día y se encostra de noche y madrugada. Con los chubascos primaverales previstos para el lunes y el martes en forma de agua hasta cotas altas, se prevé el humedecimiento del manto y que continúe la caída de deslizamientos basales y aludes de fusión. Los deslizamientos basales pueden tener tamaño para enterrarnos (tamaño 2, mediano) e incluso pueden alcanzar tamaño suficiente para tapar un grupo (tamaño 3, grande) en el extremo norte del sector. Las vertientes más proclives son las vertientes de suelo herboso. Los aludes de fusión pueden tener tamaño suficiente para enterrarnos. Las orientaciones afectadas por deslizamientos y por aludes de fusión son todos y los tamaños de los aludes de mayor alcance serán en el extremo norte de este sector y por encima de los 2200 m, donde el grosor movilizable de nieve es mayor. De noche y madrugada el rehielo favorezca levemente la estabilidad.

Distribución del manto nivoso

Hay nieve por encima de 1.800-2.000 m en N por encima de 2.100-2.300 m en S. Se alcanzan los 70-90 cm a unos 2.200 m, con frecuentes deflaciones y acumulaciones por encima del nivel del bosque.

Tendencia para las próximas 48-72h

Se mantendrá la situación de fusión. Evolución del peligro: EN LEVE DESCENSO

El próximo boletín será emitido el día 2026-04-21

5 MUY FUERTE	4 FUERTE	3 NOTABLE	2 LIMITADO	1 DÉBIL

EAWS EUROPEAN AVALANCHE WARNING SERVICES

ICGC Institut Cartogràfic i Geològic de Catalunya

meteo.cat Servei Meteorològic de Catalunya

Boletín de peligro de aludes Perafita-Puigpedrós Del 20/04/2026 al 21/04/2026

(Válido fuera pistas de esquí y zonas no controladas)

Notable (3) por encima de los 2400 m Limitado (2) en el resto.

Situación primaria

Deslizamientos basales | **Distribución** | **Tamaño** | **Origen** | **Tendencia**

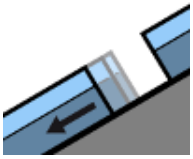

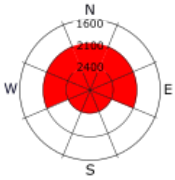

Situación secundaria

Nieve húmeda | **Distribución** | **Tamaño** | **Origen** | **Tendencia**

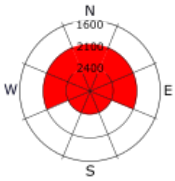

Estado del manto nivoso

El manto se presenta húmedo desde primeras horas de la mañana y hasta la noche, cuando se inicia el rehielo. El fin de semana ha continuado humedeciendo por las lluvias. El lunes y el martes se prevé que continúen las lluvias hasta cotas altas. Son muy probables caídas de deslizamientos basales y aludes de fusión de forma natural. Los deslizamientos basales pueden tener tamaño para enterrarnos (tamaño 2, mediano) e incluso pueden alcanzar tamaño suficiente para tapar un grupo (tamaño 3, grande). Las vertientes más proclives son las vertientes de suelo herboso. Los aludes de fusión pueden tener tamaño suficiente para enterrarnos. Las orientaciones afectadas por deslizamientos y por fusión son todas. Los aludes de mayor alcance estarían por encima de los 2400 m. De noche y madrugada puede haber un cierto rehielo pero las costras que se formen, transforman rápidamente a fusión.

Distribución del manto nivoso

Hay nieve por encima de 1.900-2.000 m en orientaciones N y de 2.200 m en S. Se alcanzan los 30-70 cm de espesor a unos 2.400 m, con frecuentes deflaciones y acumulaciones por encima del nivel del bosque. Estos valores están algo por debajo de los normales por la época.

Tendencia para las próximas 48-72h

Se mantendrá la situación de fusión. Evolución del peligro: EN LEVE DESCENSO

El próximo boletín será emitido el día 2026-04-21

5 MUY FUERTE	4 FUERTE	3 NOTABLE	2 LIMITADO	1 DÉBIL

EAWS EUROPEAN AVALANCHE WARNING SERVICES

ICGC Institut Cartogràfic i Geològic de Catalunya

Servei Meteorològic de Catalunya

Boletín de peligro de aludes
Vessant Nord Cadí-Moixeró
Del 20/04/2026 al 21/04/2026

(Válido fuera pistas de esquí y zonas no controladas)

Limitado (2)

Situación primaria

Nieve húmeda

Distribución

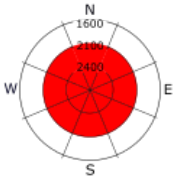

Tamaño

Origen

Tendencia

Estado del manto nivoso

El pasado domingo hubo lluvias cuantiosas en el sector, hasta cotas altas (más de 35 mm). En estas condiciones las costras que había la semana pasada se habrán ablandado y humedecido fuertemente. Con las lluvias y chubascos previstos para hoy lunes y mañana martes se esperan caídas naturales de aludes de fusión, sobre todo en momentos de chubascos en cualquier orientación y alcanzarán mayor envergadura por encima de los 2200 m, donde hay mayor grosor de manto movilizable; pueden alcanzar tamaño suficiente para enterrarnos (tamaño 2). Los sectores más peligrosos son las canales donde los grosores acumulados en caso de alud pueden ser mayores. Habrá que evitar los momentos de chubascos y las horas de mayor humedecimiento. Con el descenso térmico nocturno se prevé un leve encostramiento que puede favorecer momentáneamente la estabilización del manto de noche y madrugada.

Distribución del manto nivoso

Hay nieve por encima de 1.900 m en N y de 2.100 m en S. Se alcanzan los 115-130 cm a unos 2.200 m, con frecuentes deflaciones y acumulaciones por encima del nivel del bosque. Estos valores están por encima de los normales para la época.

Tendencia para las próximas 48-72h

Se mantendrá la situación de fusión. Evolución del peligro: EN LEVE DESCENSO

El próximo boletín será emitido el día 2026-04-21

5 MUY FUERTE	4 FUERTE	3 NOTABLE	2 LIMITADO	1 DÉBIL

EAWS EUROPEAN AVALANCHE WARNING SERVICES

ICGC Institut Cartogràfic i Geològic de Catalunya

Servei Meteorològic de Catalunya

Boletín de peligro de aludes Prepirineu
Del 20/04/2026 al 21/04/2026

(Válido fuera pistas de esquí y zonas no controladas)

Limitado (2)

Situación primaria

Nieve húmeda

Distribución

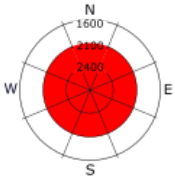

Tamaño

Origen

Tendencia

Estado del manto nivoso

El pasado domingo hubo lluvias cuantiosas en el sector, hasta cotas altas (más de 35 mm). En estas condiciones las costras que había la semana pasada se habrán ablandado y humedeciendo fuertemente. Con las lluvias y chubascos previstos para hoy lunes y mañana martes se esperan caídas naturales de aludes de fusión, sobre todo en momentos de chubascos en cualquier orientación y alcanzarán mayor envergadura por encima de los 2200 m, donde hay mayor grosor de manto movilizable; pueden alcanzar tamaño suficiente para enterrarnos (tamaño 2). Los sectores más peligrosos son las zonas trampa, como las depresiones, donde los grosores acumulados en caso de alud pueden ser mayores. Habrá que evitar los momentos de chubascos y las horas de mayor humedecimiento. Con el descenso térmico nocturno se prevé un leve encostramiento que puede favorecer momentáneamente la estabilización del manto de noche y madrugada.

Distribución del manto nivoso

Hay nieve por encima de 1.900 m en N y de 2.100-2.200 m en S. Se alcanzan los 50-70 cm a unos 2.200 m, con frecuentes deflaciones y acumulaciones por encima del nivel del bosque.

Tendencia para las próximas 48-72h

Se mantendrá la situación de fusión. Evolución del peligro: EN LEVE DESCENSO

El próximo boletín será emitido el día 2026-04-21

5 MUY FUERTE	4 FUERTE	3 NOTABLE	2 LIMITADO	1 DÉBIL

EAWS EUROPEAN AVALANCHE WARNING SERVICES

ICGC Institut Cartogràfic i Geològic de Catalunya

Servei Meteorològic de Catalunya

Boletín de peligro de aludes Ter-Freser
Del 20/04/2026 al 21/04/2026

(Válido fuera pistas de esquí y zonas no controladas)

Notable (3) por encima de los 2200 m
Limitado (2) en el resto.

Situación primaria

Deslizamientos basales | **Distribución** | **Tamaño** | **Origen** | **Tendencia**

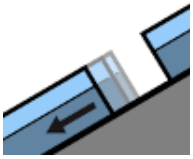

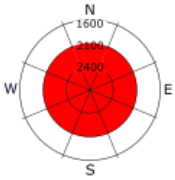

Situación secundaria

Nieve húmeda | **Distribución** | **Tamaño** | **Origen** | **Tendencia**

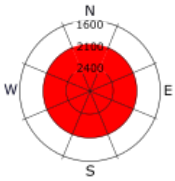

Estado del manto nivoso
El manto se presenta húmedo desde primeras horas de la mañana y hasta la noche, cuando se inicia el rehielo. El fin de semana ha continuado humedeciendose por las lluvias. El lunes y el martes se prevé que continúen las lluvias hasta cotas altas. Son muy probables caídas de deslizamientos basales y aludes de fusión de forma natural. Los deslizamientos basales pueden tener tamaño para enterrarnos (tamaño 2, mediano) e incluso pueden alcanzar tamaño suficiente para tapar un grupo (tamaño 3, grande). Las vertientes más proclives son las vertientes de suelo herboso. Los aludes de fusión pueden tener tamaño suficiente para enterrarnos. Las orientaciones afectadas por deslizamientos y por fusión son todas y los tamaños de los aludes serán de mayor alcance por encima de los 2200 m donde el grosor movilizable de nieve es mayor. De noche y madrugada puede haber un cierto rehielo pero las costras que se formen, transforman rápidamente a fusión.

Distribución del manto nivoso
Hay nieve por encima de 1.900 m en N y de 2.100-2.200 m en S. Los espesores rondan los 40-70 cm a unos 2.200 m, y más de 130-190 cm por encima de 2.400 m, con frecuentes deflaciones y acumulaciones por encima. Estos valores están por encima de la media.

Tendencia para las próximas 48-72h
Se mantendrá la situación de fusión. Evolución del peligro: EN LEVE DESCENSO

El próximo boletín será emitido el día 2026-04-21

5 MUY FUERTE	4 FUERTE	3 NOTABLE	2 LIMITADO	1 DÉBIL

EAWS EUROPEAN AVALANCHE WARNING SERVICES