BUTLLETÍ DEL PERILL D'ALLAUS DEL PRINCIPAT D'ANDORRA

Servei meteorològic nacional
Principat d'Andorra

Elaborat el 20/04/2026 16:00
Propera actualització 21/04/2026 a les 16h

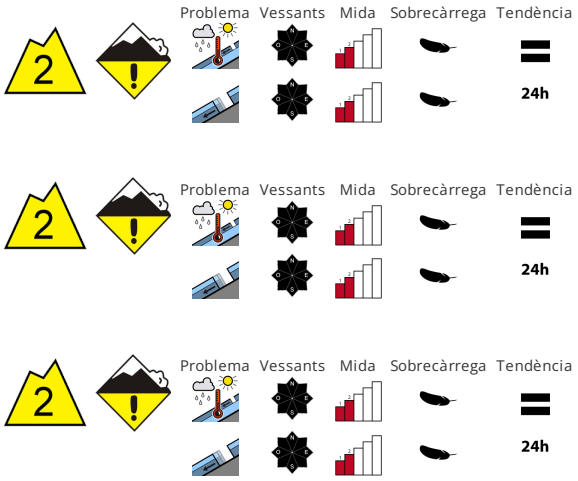

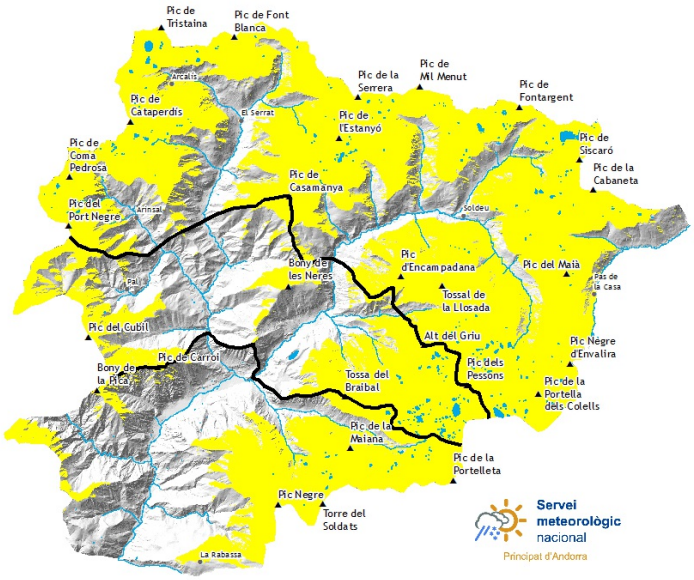

ESTABILITAT DEL MANTELL NIVAL

Al matí el temps serà força assolellat. A partir del migdia caurà pluja fins a cotes altes. Amb la pluja, són possibles allaus de neu humida i molt humida de mida mitjana i, localment, gran. A més, són d'esperar allaus de lliscament basal.

QUALITAT DE LA NEU

El refredament nocturn serà en molts sectors reduït. Al matí les condicions de temps causaran una progressiva humidificació del mantell de neu. A partir de migdia la pluja causarà en alguns casos una pèrdua de la resistència a l'interior del mantell de neu. Evitar les zones amb esquerdes de lliscament basal. Les excursions de muntanya han de començar i acabar d'hora.

GRUIXOS DEL MANTELL NIVAL FORA DE PISTA

Zona nord		Gruix neu		
Mantell Nival		1500m	2000m	2500m
N	1800 m	0 cm	150 cm	250 cm
S	2200 m	0 cm	0 cm	180 cm

Zona centre		Gruix neu		
Mantell Nival		1500m	2000m	2500m
N	1800 m	0 cm	120 cm	160 cm
S	2200 m	0 cm	0 cm	120 cm

Zona sud		Gruix neu		
Mantell Nival		1500m	2000m	2500m
N	1800 m	0 cm	120 cm	160 cm
S	2200 m	0 cm	0 cm	120 cm

Govern d'Andorra

EAWS EUROPEAN AVALANCHE WARNING SERVICES

Aquest butlletí ha estat elaborat seguint les normes i recomanacions de l'**European Avalanche Warning Services**, del qual el **Servei meteorològic Nacional** n'és membre

Informació detallada per espais naturals protegits

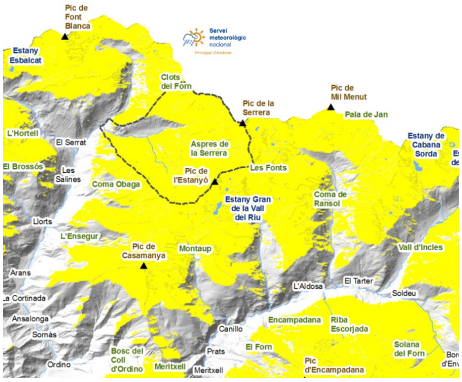

SORTENY

El feble regel de les darreres nits i les pluges de les tardes han deixat un mantell nival més precari que dies anteriors. El regel no és tant bo ni efectiu, per tant la circulació per la neu que no ha estat compactada al llarg de la temporada és més difícil.

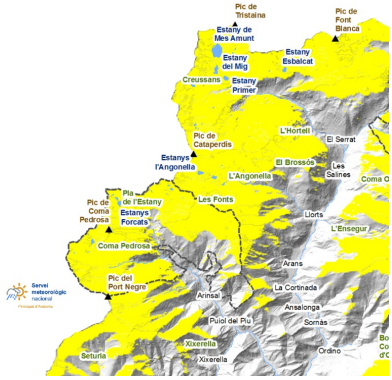

COMAPEDROSA

La neu és més humida que en dies anteriors. Atenció als ponts de gel a sobre dels torrents, ja que es veuran debilitats per l´augment de temperatures i l´augment del cabal dels rius.

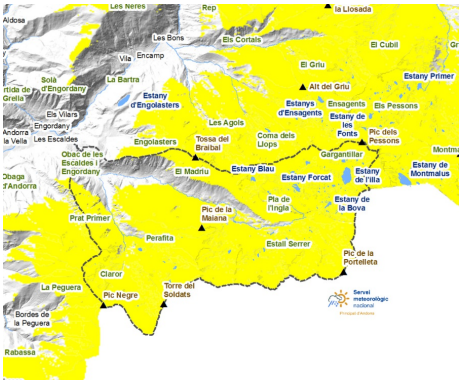

MADRIU-PERAFITA-CLAROR

La penetració de la humitat afavorirà un cicle d´allaus naturals de neu humida i lliscaments basals. A partir de l´Estall Serrer en avall, ja no queda neu contínua.

BUTLLETÍ DEL PERILL D'ALLAUS DEL PRINCIPAT D'ANDORRA

Servei meteorològic nacional
Principat d'Andorra

Gruixos de neu nova dels darrers dies (de les últimes 24h mesurat a les 06:00h UTC)

	16/04/2026	17/04/2026	18/04/2026	19/04/2026
FEDA (Central)	0 cm	0 cm	0 cm	0 cm
Engolasters - FEDA	0 cm	0 cm	0 cm	0 cm
Bony de les Neres	0 cm	0 cm	0 cm	0 cm
Sorteny	0 cm	0 cm	0 cm	0 cm
Les Fonts d'Arinsal	0 cm	0 cm	0 cm	0 cm
Aixàs	0 cm	0 cm	0 cm	0 cm
Perafita	0 cm	0 cm	0 cm	0 cm
Tossa Espiolets	0 cm	0 cm	0 cm	0 cm
Grau Roig - FEDA	0 cm	0 cm	0 cm	0 cm
Fontverd	0 cm	0 cm	0 cm	0 cm
Coll Ordino	0 cm	0 cm	0 cm	0 cm
Ransol - FEDA	0 cm	0 cm	0 cm	0 cm
Setúria	0 cm	0 cm	0 cm	0 cm
Caborreu	0 cm	0 cm	0 cm	0 cm
La Solana	0 cm	0 cm	0 cm	0 cm
Coll Pa	0 cm	0 cm	0 cm	0 cm
Envalira Antenes	0 cm	0 cm	0 cm	0 cm
Vall del Riu FEDA	0 cm	0 cm	0 cm	0 cm