BUTLLETÍ DEL PERILL D'ALLAUS DEL PRINCIPAT D'ANDORRA

Elaborado el 20/04/2026 16:00
Proxima actualización 21/04/2026 a las 16h

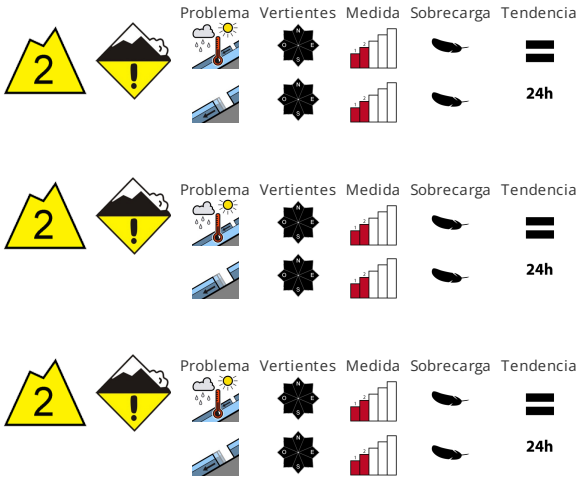

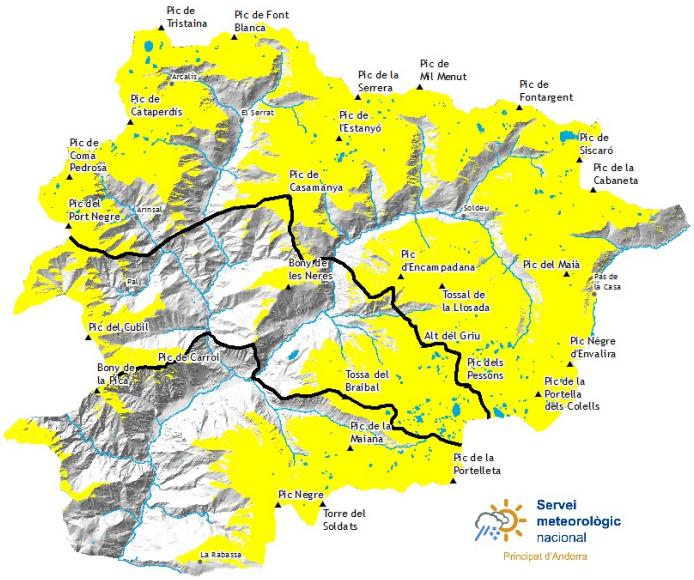

CALIDAD DE LA NIEVE

Por la mañana el tiempo será bastante soleado. A partir del mediodía caerá lluvia hasta en cotas altas. Con la lluvia, son posibles avalanchas de nieve húmeda o muy húmeda de tamaño mediano y, locamente, grande. Además son de esperar aludes de deslizamiento basal.

ESTABILIDAD DEL MANTO NIVOSO

El enfriamiento nocturno será en muchos sectores reducido. Por la mañana las condiciones meteorológicas causarán una progresiva humidificación del manto de nieve. A partir de mediodía la lluvia causará en algunos casos una pérdida de la resistencia en el interior del manto de nieve. Evitar las zonas con grietas de deslizamiento basal. Las excursiones de montaña deben comenzar y acabar temprano.

ESPESORES DEL MANTO NIVOSO FUERA DE PISTA

Zona norte		Espesor nieve		
Manto Nival		1500m	2000m	2500m
N	1800 m	0 cm	150 cm	250 cm
S	2200 m	0 cm	0 cm	180 cm

zona centro		Espesor nieve		
Manto Nival		1500m	2000m	2500m
N	1800 m	0 cm	120 cm	160 cm
S	2200 m	0 cm	0 cm	120 cm

Zona sur		Espesor nieve		
Manto Nival		1500m	2000m	2500m
N	1800 m	0 cm	120 cm	160 cm
S	2200 m	0 cm	0 cm	120 cm

Govern d'Andorra

Aquest butlletí ha estat elaborat seguint les normes i recomanacions de l'**European Avalanche Warning Services**, del qual el **Servei meteorològic Nacional** n'és membre

BUTLLETÍ DEL PERILL D'ALLAUS DEL PRINCIPAT D'ANDORRA

Servei meteorològic nacional
Principat d'Andorra

Información detallada por espacios naturales protegidos

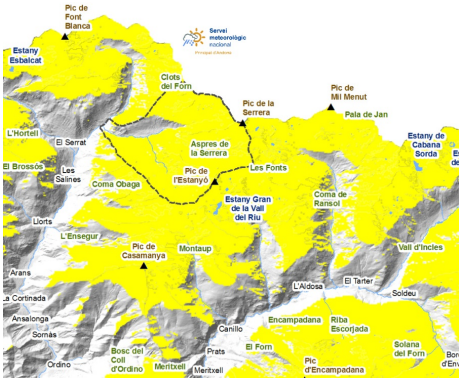

SORTENY

El débil rehielo de las últimas noches y las lluvias de las tardes han dejado un manto nivoso más precario que días anteriores. El rehielo no es tan bueno ni efectivo, por tanto la circulación por la nieve que no ha sido compactada a lo largo de la temporada es más difícil.

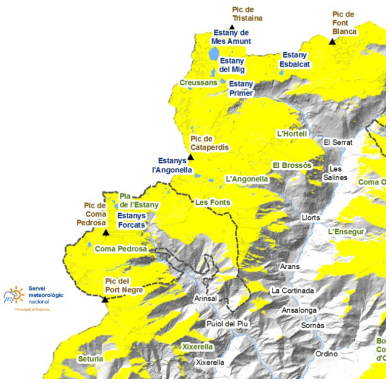

COMAPEDROSA

La nieve está más húmeda que en días anteriores. Atención a los puentes de hielo sobre los torrentes, puesto que se verán debilitados por el aumento de temperaturas y el aumento del caudal de los ríos.

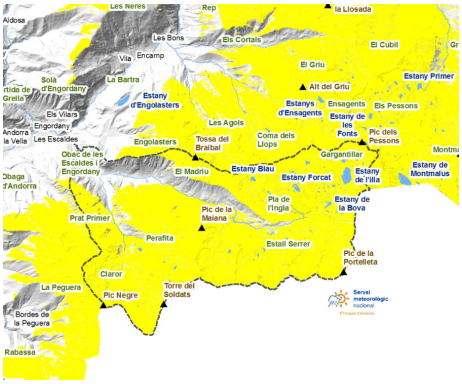

MADRIU-PERAFITA-CLAROR

La penetración de la humedad favorecerá un ciclo de aludes naturales de nieve húmeda y deslizamientos basales. A partir del Estall Serrer en abajo, ya no queda nieve continua.

Govern d'Andorra

EAWS
EUROPEAN AVALANCHE WARNING SERVICES

Aquest butlletí ha estat elaborat seguint les normes i recomanacions de l'**European Avalanche Warning Services**, del qual el **Servei meteorològic Nacional** n'és membre

BUTLLETÍ DEL PERILL D'ALLAUS DEL PRINCIPAT D'ANDORRA

Servei meteorològic nacional
Principat d'Andorra

Espesores de nieve nueva de los últimos días (de las ultimas 24h mesurado a las 06:00h UTC)

	16/04/2026	17/04/2026	18/04/2026	19/04/2026
FEDA (Central)	0 cm	0 cm	0 cm	0 cm
Engolasters - FEDA	0 cm	0 cm	0 cm	0 cm
Bony de les Neres	0 cm	0 cm	0 cm	0 cm
Sorteny	0 cm	0 cm	0 cm	0 cm
Les Fonts d'Arinsal	0 cm	0 cm	0 cm	0 cm
Aixàs	0 cm	0 cm	0 cm	0 cm
Perafita	0 cm	0 cm	0 cm	0 cm
Tossa Espiolets	0 cm	0 cm	0 cm	0 cm
Grau Roig - FEDA	0 cm	0 cm	0 cm	0 cm
Fontverd	0 cm	0 cm	0 cm	0 cm
Coll Ordino	0 cm	0 cm	0 cm	0 cm
Ransol - FEDA	0 cm	0 cm	0 cm	0 cm
Setúria	0 cm	0 cm	0 cm	0 cm
Caborreu	0 cm	0 cm	0 cm	0 cm
La Solana	0 cm	0 cm	0 cm	0 cm
Coll Pa	0 cm	0 cm	0 cm	0 cm
Envalira Antenes	0 cm	0 cm	0 cm	0 cm
Vall del Riu FEDA	0 cm	0 cm	0 cm	0 cm