Bulletin d'estimation du risque d'avalanche

(valable en dehors des pistes balisées et ouvertes)

MASSIF : Capcir Puymorens

Rédigé le lundi 20 avril 2026 à 15h

Estimation des risques pour le : MARDI 21 AVRIL

POURSUITE DE L'HUMIDIFICATION

2

2

N O E S

Indice de risque limité.

Départs spontanés : Avalanches de surface et avalanches de fond en neige humide

Déclenchements provoqués : Départs ponctuels en neige humide favorisés par le passage d'un randonneur.

Indices de risque : 5 très fort - 4 fort - 3 marqué - 2 limité - 1 faible -- En noir : les pentes les plus dangereuses

Stabilité du manteau neigeux

Situation avalancheuse typique : neige humide — avalanches de fond

Départs spontanés :
- Départs ponctuels d'**avalanches en neige humide** de taille petite en haute montagne mobilisant les quelques centimètres de neige récente tombés éventuellement la veille. Avec la douceur et sous les nuages de l'après-midi, des départs un peu plus volumineux demeurent possibles en pentes raides.
- En altitude, avec l'humidification qui gagne en profondeur, des **avalanches de glissement** emportant l'ensemble du manteau neigeux sont possibles en toutes orientations (fissures/reptations et avalanches de glissement signalées ces derniers jours). Elles seront de taille moyenne, voire plus rarement grandes dans les zones de plus fortes accumulations (pentes nord à sud-est).

Déclenchements provoqués :
- Un skieur coupant une pente raide déjà bien humidifiée pourra favoriser un départ ponctuel de taille petite à plus rarement moyenne.

Autre : Des corniches encore imposantes sont en place et sont susceptibles de céder spontanément avec l'humidification, tout comme les ponts de neige sur les torrents bien alimentés par la fonte en cours.

Qualité de la neige

Enneigement :
L'enneigement dans nos massifs reste très bon pour la saison, encore largement supérieur à celui des derniers hivers. Avec la douceur ambiante, le manteau perd une petite dizaine de cm par jour et la limite skiable remonte progressivement surtout en sud. Elle est encore au mieux vers 1700 m en nord et 2100 m en sud. On trouve ensuite rapidement une bonne épaisseur de neige qui dépasse souvent les 1m50 dès 2000 m en nord, et les 2m50 dès 2500m.

Qualité de la neige :
Au petit matin, les pentes au-delà de 2300/2400 m devraient connaitre un regel en surface. Ce dernier est plus aléatoire en dessous. L'humidification reprend rapidement en matinée, et se poursuit l'après-midi. Exceptés les plus hauts sommets qui peuvent avoir été reblanchis par les averses, la surface du manteau est majoritairement constituée de neige ocre, chargée en poussières sahariennes. Les cols et crêtes ouest à nord-ouest sont généralement moins garnis en neige voire pelés.

Aperçu météo pour le mardi 21 avril

Assez beau le matin, plus chargé l'après-midi avec quelques ondées.

	nuit	matin	après-midi	soir
Pluie-Neige	2 700 m		3 000 m	
Iso 0 °C	3 100 m	3 400 m	3 400 m	3 500 m
Vent 2000 m	↗ 15 km/h	→ 15 km/h	↗ 25 km/h	↗ 20 km/h
Vent 3000 m	↘ 25 km/h	↗ 20 km/h	↗ 25 km/h	↗ 20 km/h

Épaisseur de neige hors-piste

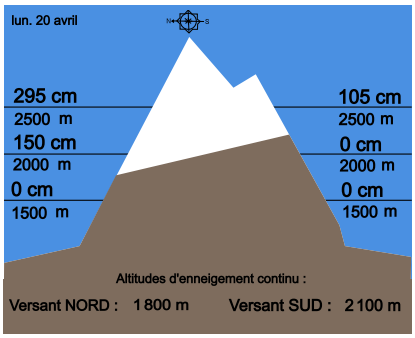

Précipitations à 1800 m

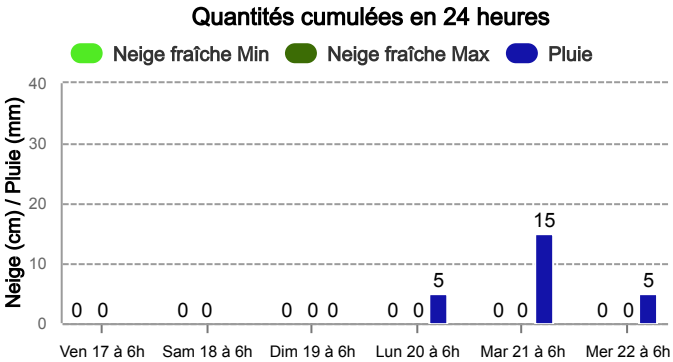

Tendance du mercredi 22 avril

2

Indice de risque limité

Situation équivalente, peu d'évolution du risque.

Pour consulter la vigilance en cours, veuillez vous rendre sur le site https://vigilance.meteofrance.fr/fr

Météo-France - 73 avenue de Paris, 94165 Saint-Mandé cedex - Contact : contact@meteo.fr

Rédigé par Météo-France avec la contribution des observateurs du réseau nivo-météorologiques. Partenariat : ANMSM (Maires de Stations de Montagne), DSF (Domaines Skiables de France), ADSP (Directeurs de Pistes et de la Sécurité des Stations de Sports d'Hiver) et autres acteurs de la montagne.

Bulletin neige & avalanches par téléphone au 0 892 68 10 20 Service 0,35 € / min + prix appel

RÉPUBLIQUE FRANÇAISE
Liberté Égalité Fraternité

METEO FRANCE
À VOS CÔTÉS, DANS UN CLIMAT QUI CHANGE

Bulletin d'estimation du risque d'avalanche

(valable en dehors des pistes balisées et ouvertes)

MASSIF : Capcir Puymorens

Rédigé le lundi 20 avril 2026 à 15h

Conditions nivo-météo des 7 derniers jours

	mar. 14/04				mer. 15/04				jeu. 16/04				ven. 17/04				sam. 18/04				dim. 19/04				lun. 20/04			
	03h	09h	15h	21h	03h	09h	15h	21h	03h	09h	15h	21h	03h	09h	15h	21h	03h	09h	15h	21h	03h	09h	15h	21h	03h	09h	15h	21h
Météo																												
Vent (km/h)	50	50	50	45	35	25	25	20	20	20	25	20	20	20	15	15	15	15	20	15	20	15	30	15	20	25	35	15
à 3000m																												
Vent (km/h)	25	25	25	20	20	15	15	10	10	10	15	10	10	10	10	10	10	10	15	10	15	15	25	15	20	15	30	15
à 2000m																												

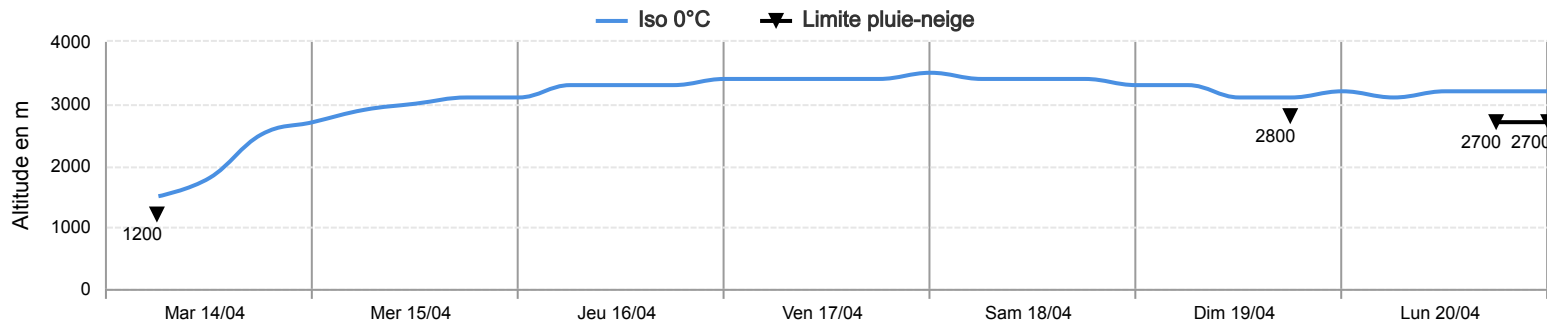

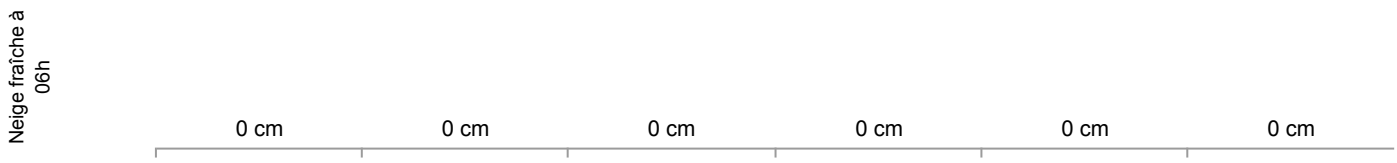

Risque d'avalanche	mar. 14/04	mer. 15/04	jeu. 16/04	ven. 17/04	sam. 18/04	dim. 19/04	lun. 20/04
	2	2	2	2	2	2	2

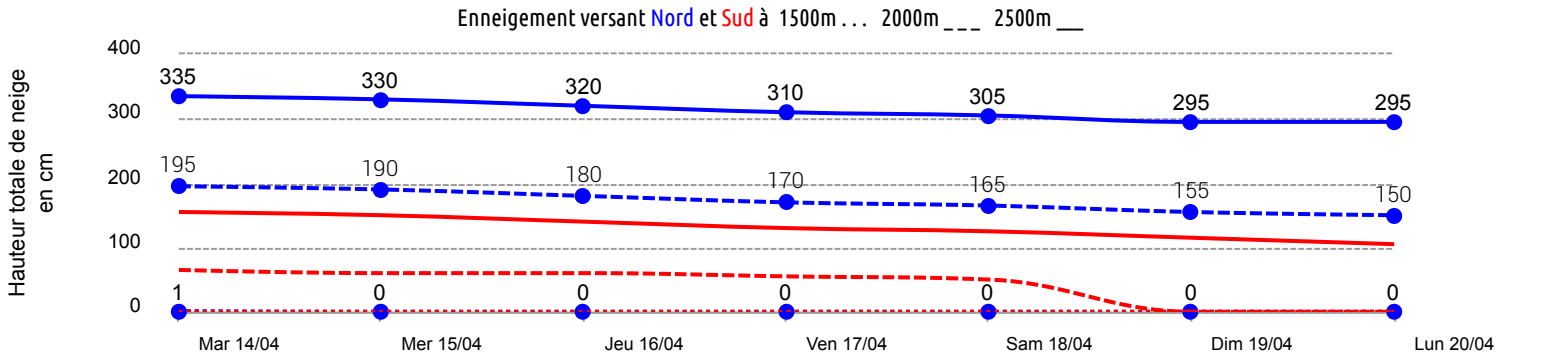

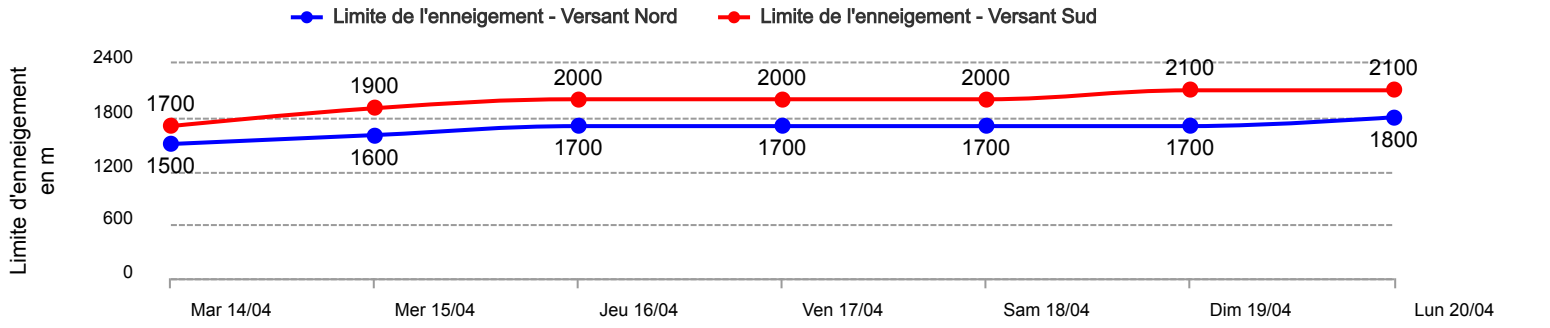

Pour consulter la vigilance en cours, veuillez vous rendre sur le site https://vigilance.meteofrance.fr/fr

Météo-France - 73 avenue de Paris, 94165 Saint-Mandé cedex - Contact : contact@meteo.fr

Bulletin neige & avalanches par téléphone au

0 892 68 10 20 Service 0,35 € / min + prix appel

Rédigé par Météo-France avec la contribution des observateurs du réseau nivo-météorologiques. Partenariat : ANMSM (Maires de Stations de Montagne), DSF (Domaines Skiables de France), ADSP (Directeurs de Pistes et de la Sécurité des Stations de Sports d'Hiver) et autres acteurs de la montagne.