Bulletin d'estimation du risque d'avalanche

(valable en dehors des pistes balisées et ouvertes)

MASSIF : Cinto Rotondo

Rédigé le lundi 20 avril 2026 à 15h

Estimation des risques pour le : MARDI 21 AVRIL

MANTEAU NEIGEUX PRINTANIER

2

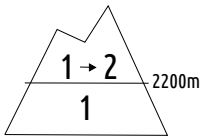

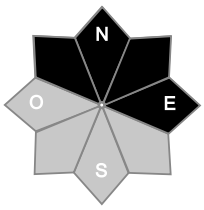

Au-dessus de 2200m indice de risque faible évoluant en limité, plus bas indice faible.

Départs spontanés : Coulées et avalanches de neige humide en journée dans les pentes raides

Déclenchements provoqués : Peu probables

Indices de risque : 5 très fort - 4 fort - 3 marqué - 2 limité - 1 faible -- En noir : les pentes les plus dangereuses

Stabilité du manteau neigeux

Situation avalancheuse typique : neige humide

Départs spontanés : Le manteau neigeux est bien humidifié et bien tassé jusqu'à 2300 m d'altitude. L'après midi, sous l'effet de la douceur et de l'ensoleillement, des coulées ou avalanches de neige humide sont attendues dans les pentes raides. Elles peuvent être de taille moyenne au-dessus de 2300 m, notamment dans les pentes orientées Nord. À noter également qu'une avalanche de fond n'est pas exclue sur les dalles rocheuses (apparition de fissures de reptation).

Déclenchements provoqués : Dans la plupart des secteurs, il est difficile de provoquer une avalanche dans ce manteau neigeux humide et tassé. Un skieur peut éventuellement favoriser un départ ponctuel en coupant une pente raide en neige très humide.

Autres : Prendre garde également aux effondrements de corniches et ponts de neige surchauffés qui peuvent céder.

Qualité de la neige

Qualification de l'enneigement : La fonte est importante depuis début avril. Malgrè tout l'enneigement est encore bon pour la saison. Sur la Maniccia, à 2400 m d'altitude dans le massif du Rotondo, on relève 2m60 de hauteur de neige totale.

Limite d'enneigement skiable : vers 1600 à 1700 m en Nord, 1800 à 1900 m en Sud mais cette limite progresse chaque jour avec la fonte.

État de la neige : Absence de regel mais neige portant le matin au plus haut du massif en expositions nord. Neige dense en sud au lever du jour mais généralement non croûtée, devenant vite printanière, très humide. La surface du manteau est majoritairement constituée de neige colorée, chargée en poussières sahariennes. Les cols et crêtes ouest se dégarnissent en neige ou sont parfois "pelés". Nombreuses fissures en place.

Aperçu météo pour le mardi 21 avril

	nuit	matin	après-midi	soir
Pluie-Neige				
Iso 0 °C	3 100 m	3 100 m	3 200 m	3 300 m
Vent 1500 m	→ 25 km/h	→ 30 km/h	→ 30 km/h	→ 15 km/h
Vent 3000 m	→ 45 km/h	→ 35 km/h	→ 35 km/h	→ 25 km/h

Épaisseur de neige hors-piste

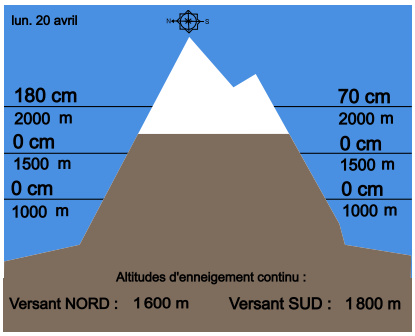

Précipitations à 1800 m

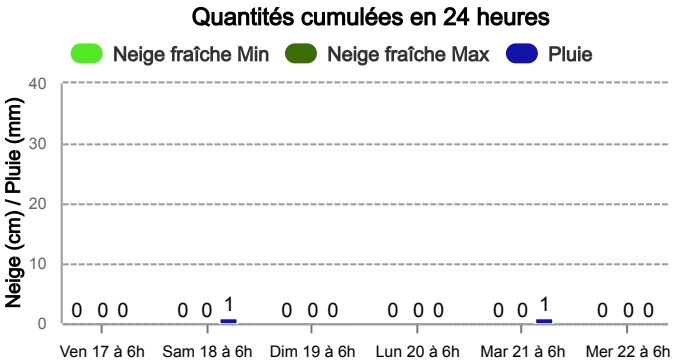

Tendance du mercredi 22 avril

2

Indice de risque limité

Pas d'évolution notable en termes de risque.

Pour consulter la vigilance en cours, veuillez vous rendre sur le site https://vigilance.meteofrance.fr/fr

Météo-France - 73 avenue de Paris, 94165 Saint-Mandé cedex - Contact : contact@meteo.fr

Rédigé par Météo-France avec la contribution des observateurs du réseau nivo-météorologiques. Partenariat : ANMSM (Maires de Stations de Montagne), DSF (Domaines Skiables de France), ADSP (Directeurs de Pistes et de la Sécurité des Stations de Sports d'Hiver) et autres acteurs de la montagne.

Bulletin neige & avalanches par téléphone au

0 892 68 10 20 Service 0,35 € / min + prix appel

Bulletin d'estimation du risque d'avalanche

(valable en dehors des pistes balisées et ouvertes)

MASSIF : Cinto Rotondo

Rédigé le lundi 20 avril 2026 à 15h

Conditions nivo-météo des 7 derniers jours

	mar. 14/04				mer. 15/04				jeu. 16/04				ven. 17/04				sam. 18/04				dim. 19/04				lun. 20/04			
	03h	09h	15h	21h	03h	09h	15h	21h	03h	09h	15h	21h	03h	09h	15h	21h	03h	09h	15h	21h	03h	09h	15h	21h	03h	09h	15h	21h
Météo																												
Vent (km/h)	15	15	20	30	30	30	25	30	30	20	20	20	20	15	15	20	15	15	15	20	10	20	30	30	35	45	60	60
à 3000m																												
Vent (km/h)	15	15	20	25	30	30	25	20	20	15	10	20	15	15	10	15	10	15	10	5	5	20	30	25	25	30	35	35
à 1500m																												

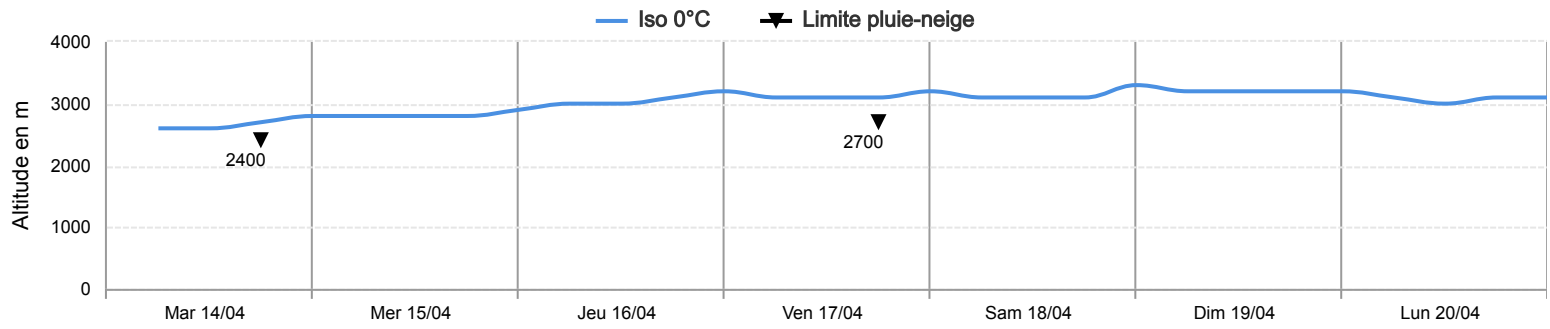

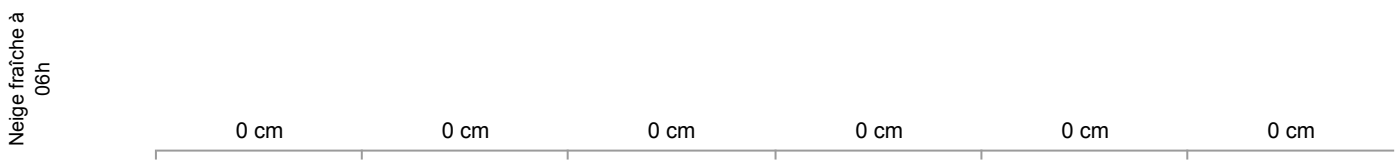

Risque d'avalanche	mar. 14/04	mer. 15/04	jeu. 16/04	ven. 17/04	sam. 18/04	dim. 19/04	lun. 20/04
	3	3	2	2	2	2	2

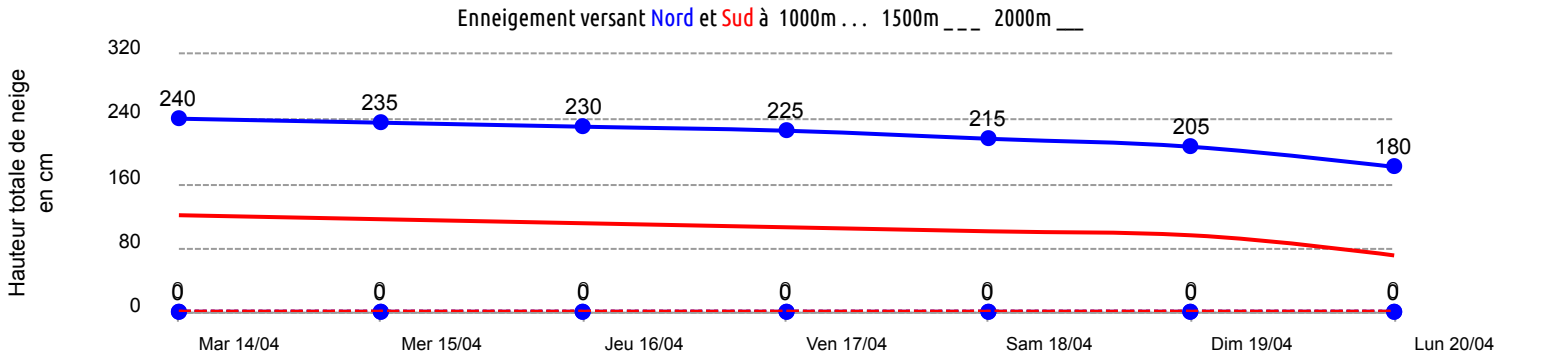

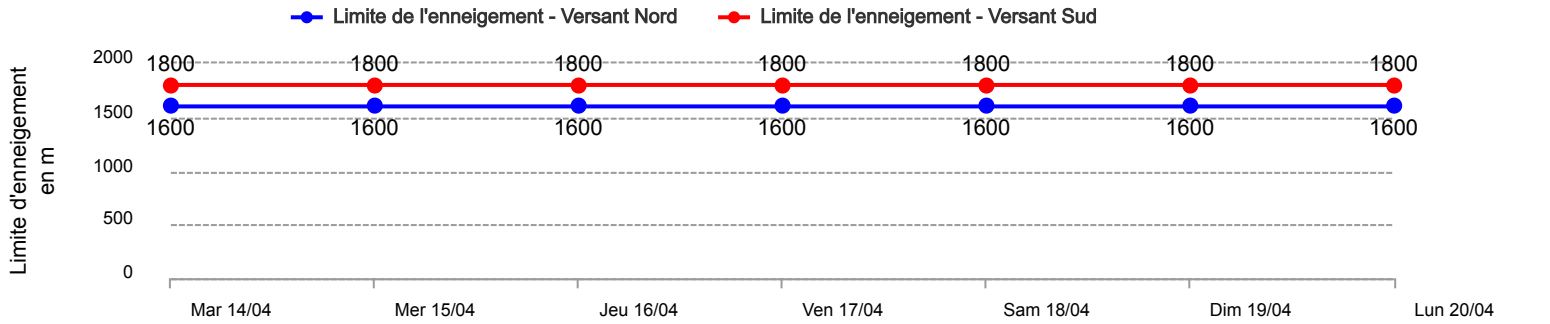

Pour consulter la vigilance en cours, veuillez vous rendre sur le site https://vigilance.meteofrance.fr/fr

Météo-France - 73 avenue de Paris, 94165 Saint-Mandé cedex - Contact : contact@meteo.fr

Bulletin neige & avalanches par téléphone au

0 892 68 10 20 Service 0,35 € / min + prix appel

Rédigé par Météo-France avec la contribution des observateurs du réseau nivo-météorologiques. Partenariat : ANMSM (Maires de Stations de Montagne), DSF (Domaines Skiables de France), ADSP (Directeurs de Pistes et de la Sécurité des Stations de Sports d'Hiver) et autres acteurs de la montagne.