Bulletin d'estimation du risque d'avalanche
(valable en dehors des pistes balisées et ouvertes)

MASSIF : Oisans

Rédigé le lundi 20 avril 2026 à 15h

Estimation des risques pour le : MARDI 21 AVRIL

HUMIDIFICATION PRINTANIERE ; RARES DÉPARTS POSSIBLES, MAIS PARFOIS VOLUMINEUX, AU TERRAIN ?

2

1 → 2

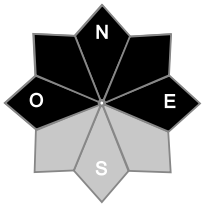

Rares, humidifiées

Indice de risque faible évoluant en limité.

Départs spontanés : Rares coulées ou avalanches humides au fil de la journée. Généralement en pentes "froides" de taille moyennes, rarement grandes - au terrain (glissement non exclu en alpage)... En faces Sud neige presque de névé, plus stable.

Déclenchements provoqués : Peu probables, ou juste une coulée ponctuelle sous les skis en neige très humide ?

Indices de risque : 5 très fort - 4 fort - 3 marqué - 2 limité - 1 faible -- En noir : les pentes les plus dangereuses

Stabilité du manteau neigeux

Situation avalancheuse typique : neige humide — avalanches de fond

Départs spontanés : Neige transformée dense avec un bon regel nocturne à l'aube. Au fil des heures neige devenant très humide. De rares nouvelles coulées sont possibles, près des rochers, voire une avalanche volumineuse en faces "froides" (de taille moyenne à grande). En faces Nord-Est puis Nord-Ouest, un départ ponctuel pourrait créer une plus épaisse et large cassure en contrebas (l'humidité touchant d'anciennes couches fragiles).
Noter que dans certaines pentes herbeuses ou de schistes, une avalanche de glissement - au terrain - n'est pas exclue, plutôt entre l'après-midi et la soirée. Des fissures de reptations sont visibles.
En Sud la neige sera aussi très humide, mais plus dense, de type névé, le risque d'avalanche parait faible. Vigilance plutôt vers les hautes crêtes où les corniches pourraient être fragilisées...

Déclenchements provoqués : Pas de risque de plaque. En terrain raide et bien humidifié, risque limité de coulée ponctuelle sous les skis.

Autres : Neige temporairement durcie par regel ou croutée/cassante... Puis au fil des heures neige parfois trop humide/détrempée "attrapant" les skis.

Qualité de la neige

Qualification de l'enneigement : L'enneigement s'est bien réduit depuis 2 semaines, notamment en Sud. Ceci dit il demeure correct pour la saison en faces moins ensoleillées et en combes d'altitude... NOTA : Enneigement un peu plus déficitaire près des Ecrins, à très haute altitude.
Limites skiables : Vers 1500/1800m en Nord à 1900/2300m suivant l'exposition au soleil, la raideur de la pente...

Qualité de la neige mardi : Vers un bon regel au matin, à l'ombre. Neige temporairement croutée ou durcie puis assez rapide humidification/ fonte parfois. L'après-midi, la neige poursuit son humidification locale. Neige très humide à "soupe" selon le versant/l'altitude. En Sud, neige très densifiée, presque de névé.
Il ne reste de la neige sèche, en poudreuse dense, qu'en plein Nord raide au dessus de 3000m environ.

Aperçu météo pour le mardi 21 avril

	nuit	matin	après-midi	soir

Beau temps souvent clair, regel nocturne correct en altitude. En journée soleil et quelques voiles, discrets cumulus l'après-midi...

Pluie-Neige				
Iso 0 °C	2 800 m	3 000 m	3 000 m	3 000 m
Vent 2500 m	↘ 30 km/h	↘ 35 km/h	→ 30 km/h	→ 20 km/h
Vent 3500 m	↘ 45 km/h	↘ 45 km/h	↘ 40 km/h	↘ 40 km/h

Épaisseur de neige hors-piste

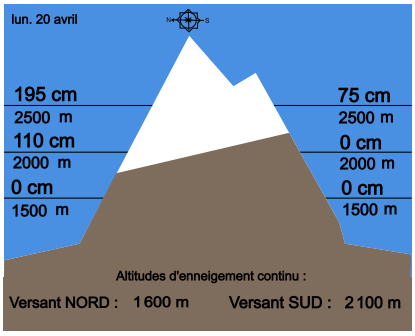

Précipitations à 1800 m

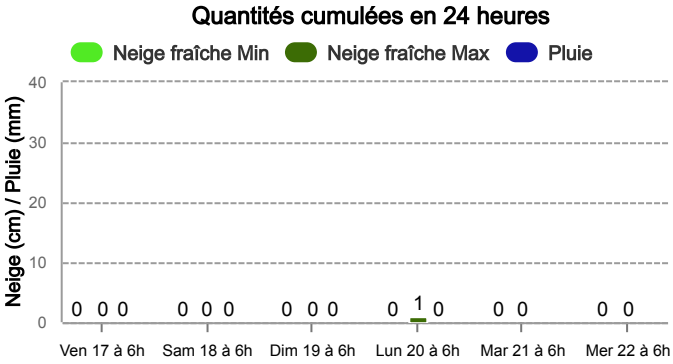

Tendance du mercredi 22 avril

2

Indice de risque limité

Risque stationnaire ou en légère baisse mercredi. Regel nocturne assez bon, puis humidification/fonte en journée...

Pour consulter la vigilance en cours, veuillez vous rendre sur le site https://vigilance.meteofrance.fr/fr

Météo-France - 73 avenue de Paris, 94165 Saint-Mandé cedex - Contact : contact@meteo.fr

Rédigé par Météo-France avec la contribution des observateurs du réseau nivo-météorologiques. Partenariat : ANMSM (Maires de Stations de Montagne), DSF (Domaines Skiables de France), ADSP (Directeurs de Pistes et de la Sécurité des Stations de Sports d'Hiver) et autres acteurs de la montagne.

Bulletin neige & avalanches par téléphone au **0 892 68 10 20** Service 0,35 € / min + prix appel

RÉPUBLIQUE FRANÇAISE
Liberté Égalité Fraternité

METEO FRANCE
À VOS CÔTÉS, DANS UN CLIMAT QUI CHANGE

Bulletin d'estimation du risque d'avalanche
(valable en dehors des pistes balisées et ouvertes)

MASSIF : Oisans

Rédigé le lundi 20 avril 2026 à 15h

Conditions nivo-météo des 7 derniers jours

	mar. 14/04				mer. 15/04				jeu. 16/04				ven. 17/04				sam. 18/04				dim. 19/04				lun. 20/04			
	03h	09h	15h	21h	03h	09h	15h	21h	03h	09h	15h	21h	03h	09h	15h	21h	03h	09h	15h	21h	03h	09h	15h	21h	03h	09h	15h	21h
Météo																												
Vent (km/h)	20	15	15	20	15	10	10	10	20	10	0	5	5	5	5	10	20	20	15	20	20	25	30	35	25	25	30	35
à 3500m																												
Vent (km/h)	10	10	10	10	5	5	5	5	5	5	10	15	10	15	5	0	10	5	0	10	10	15	20	20	10	15	20	20
à 2500m																												

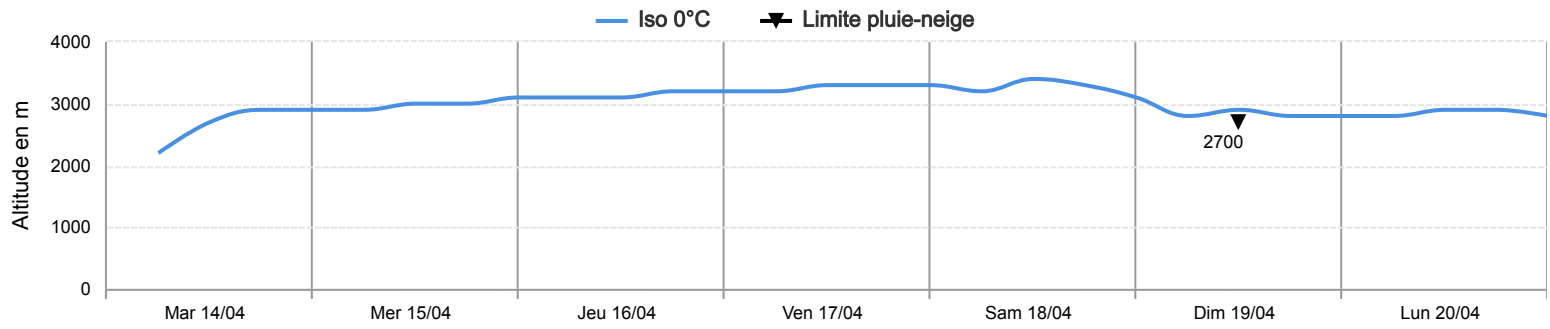

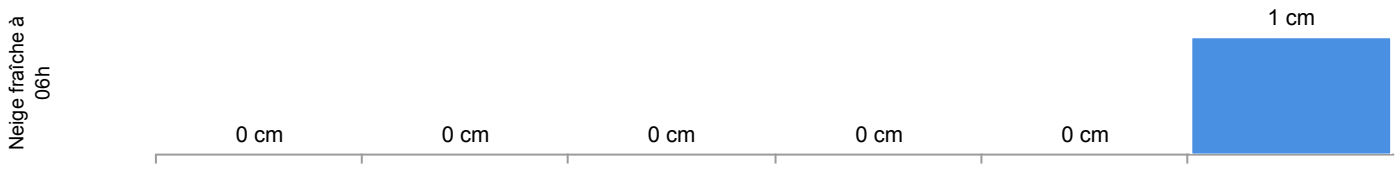

Risque d'avalanche	mar. 14/04	mer. 15/04	jeu. 16/04	ven. 17/04	sam. 18/04	dim. 19/04	lun. 20/04
	2	2	2	2	2	2	2

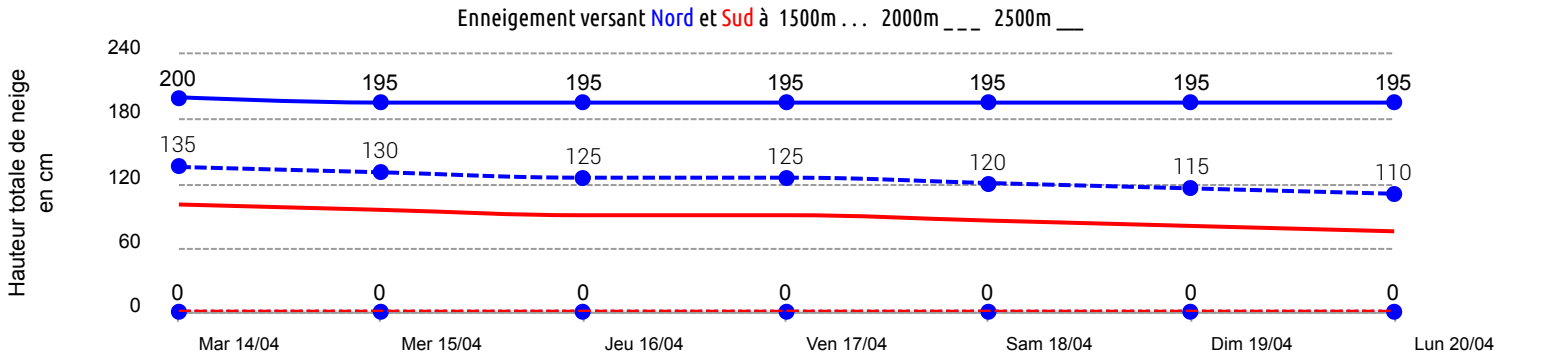

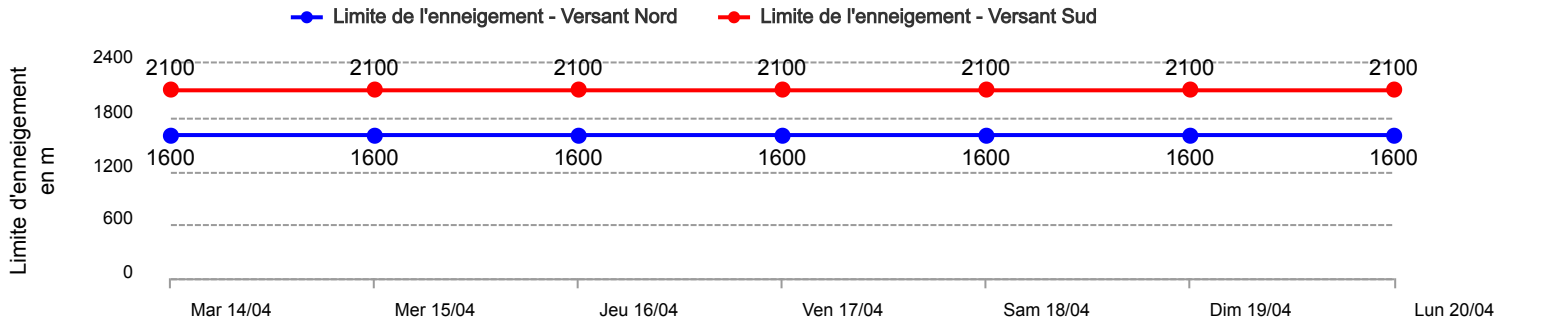

Pour consulter la vigilance en cours, veuillez vous rendre sur le site https://vigilance.meteofrance.fr/fr

Météo-France - 73 avenue de Paris, 94165 Saint-Mandé cedex - Contact : contact@meteo.fr

Rédigé par Météo-France avec la contribution des observateurs du réseau nivo-météorologiques. Partenariat : ANMSM (Maires de Stations de Montagne), DSF (Domaines Skiables de France), ADSP (Directeurs de Pistes et de la Sécurité des Stations de Sports d'Hiver) et autres acteurs de la montagne.

Bulletin neige & avalanches par téléphone au
0 892 68 10 20 Service 0,35 € / min + prix appel