Bulletin d'estimation du risque d'avalanche
(valable en dehors des pistes balisées et ouvertes)

MASSIF : Vercors

Rédigé le lundi 20 avril 2026 à 15h

Estimation des risques pour le : MARDI 21 AVRIL

NEIGE DENSE, TRES HUMIDE EN JOURNE : RARE AVALANCHE POSSIBLE, PARFOIS AU TERRAIN ? (PENTES NORD HERBEUSES)...

2

1 → 2

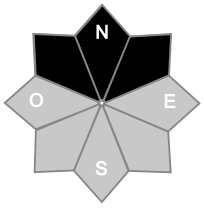

Rares, humidifiées ?

Indice de risque faible évoluant en limité.

Départs spontanés : Rares coulées ou avalanches humides, possibles surtout l'après-midi... En faces Nord avalanche de glissement au terrain non exclue (taille 2 à 3 ?)

Déclenchements provoqués : Peu probables, ou juste une coulée ponctuelle sous les skis en neige très humide ?

Indices de risque : 5 très fort - 4 fort - 3 marqué - 2 limité - 1 faible -- En noir : les pentes les plus dangereuses

Stabilité du manteau neigeux

Situation avalancheuse typique : neige humide — avalanches de fond

Départs spontanés : Neige transformée dense avec un un regel nocturne/matinal. Au fil des heures neige devenant très humide sur de grandes épaisseurs. Une coulée n'est pas exclue, près des rochers, voire une rare avalanche plus volumineuse ?
Noter que dans certaines faces Nord herbeuses, une avalanche de glissement - au terrain - n'est pas exclue, plutôt entre l'après-midi et la soirée. Des fissures de reptations sont présentes...
En Sud il y a peu de neige et de type névé, stable...

Déclenchements provoqués : Pas de risque de plaque. En terrain raide et bien humidifié, risque limité de coulée ponctuelle sous les skis.

Autres : Neige temporairement durcie par regel ou croutée/cassante...

Qualité de la neige

Qualification de l'enneigement : L'enneigement s'est fortement réduit depuis 2 semaines mais reste correct en faces peu ensoleillées d'altitude. Au Sud il ne reste plus que des névés...
Limites skiables : Vers 1500 à 1900m environ suivant l'exposition, la raideur de la pente...

Qualité de la neige mardi : Regel correct mardi matin en altitude. Neige temporairement durcie ou croutée. Rapide dégel au soleil/ fonte. Neige devenant très humide au fil des heures et ce jusqu'en profondeur.... En large Sud, neige presque de névé.
La neige est plus colorée, avec davantage de reliefs désormais.

Aperçu météo pour le mardi 21 avril

	nuit	matin	après-midi	soir

Beau temps souvent clair, regel nocturne correct en altitude. En journée soleil et quelques voiles, discrets cumulus l'après-midi...

Pluie-Neige				
Iso 0 °C	2 800 m	2 900 m	2 900 m	3 000 m
Vent 1500 m	10 km/h	20 km/h	25 km/h	10 km/h
Vent 2000 m	15 km/h	20 km/h	20 km/h	10 km/h

Épaisseur de neige hors-piste

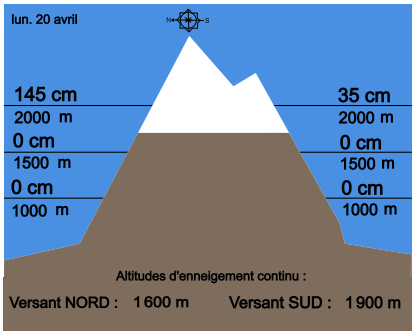

Précipitations à 1800 m

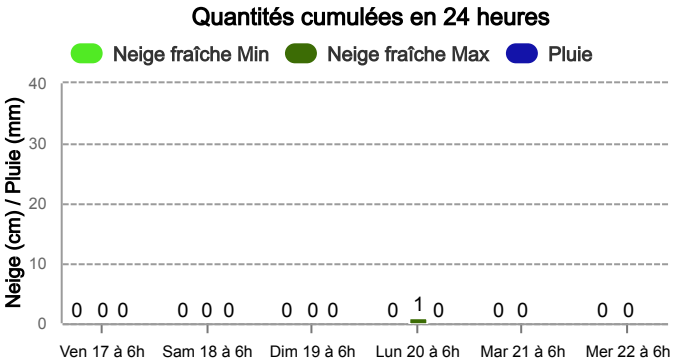

Tendance du mercredi 22 avril

1

Indice de risque faible

Risque en légère baisse mercredi, neige de plus en plus dense, stable, moins de risque d'avalanche humide...

Pour consulter la vigilance en cours, veuillez vous rendre sur le site https://vigilance.meteofrance.fr/fr

Météo-France - 73 avenue de Paris, 94165 Saint-Mandé cedex - Contact : contact@meteo.fr

Rédigé par Météo-France avec la contribution des observateurs du réseau nivo-météorologiques. Partenariat : ANMSM (Maires de Stations de Montagne), DSF (Domaines Skiables de France), ADSP (Directeurs de Pistes et de la Sécurité des Stations de Sports d'Hiver) et autres acteurs de la montagne.

Bulletin neige & avalanches par téléphone au 0 892 68 10 20 Service 0,35 € / min + prix appel

RÉPUBLIQUE FRANÇAISE
Liberté Égalité Fraternité

METEO FRANCE
À VOS CÔTÉS, DANS UN CLIMAT QUI CHANGE

Bulletin d'estimation du risque d'avalanche
(valable en dehors des pistes balisées et ouvertes)

MASSIF : Vercors

Rédigé le lundi 20 avril 2026 à 15h

Conditions nivo-météo des 7 derniers jours

	mar. 14/04				mer. 15/04				jeu. 16/04				ven. 17/04				sam. 18/04				dim. 19/04				lun. 20/04			
	03h	09h	15h	21h	03h	09h	15h	21h	03h	09h	15h	21h	03h	09h	15h	21h	03h	09h	15h	21h	03h	09h	15h	21h	03h	09h	15h	21h
Météo																												
Vent (km/h)	35	40	40	35	35	15	20	15	20	20	15	10	10	5	5	0	10	10	5	5	15	20	25	15	20	20	25	15
à 2000m																												
Vent (km/h)	35	35	35	25	20	10	15	10	15	15	10	0	5	5	5	5	5	5	10	0	15	20	20	10	10	20	25	10
à 1500m																												

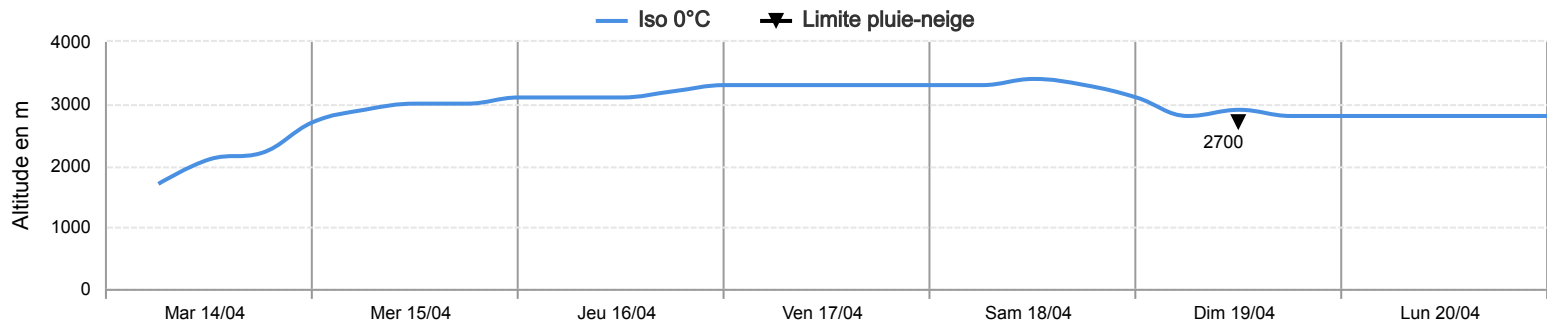

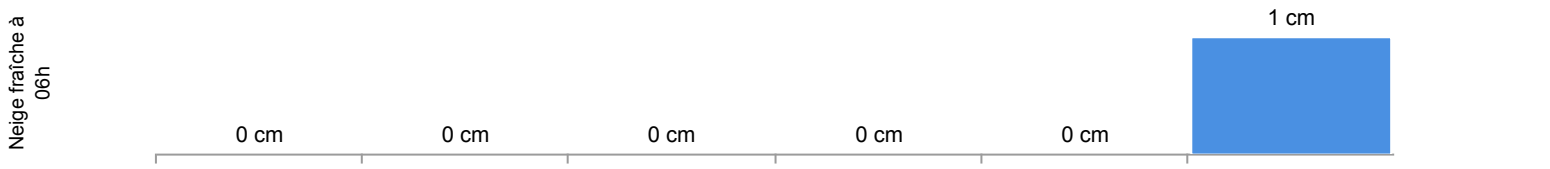

Risque d'avalanche	mar. 14/04	mer. 15/04	jeu. 16/04	ven. 17/04	sam. 18/04	dim. 19/04	lun. 20/04
	2	2	2	2	2	2	2

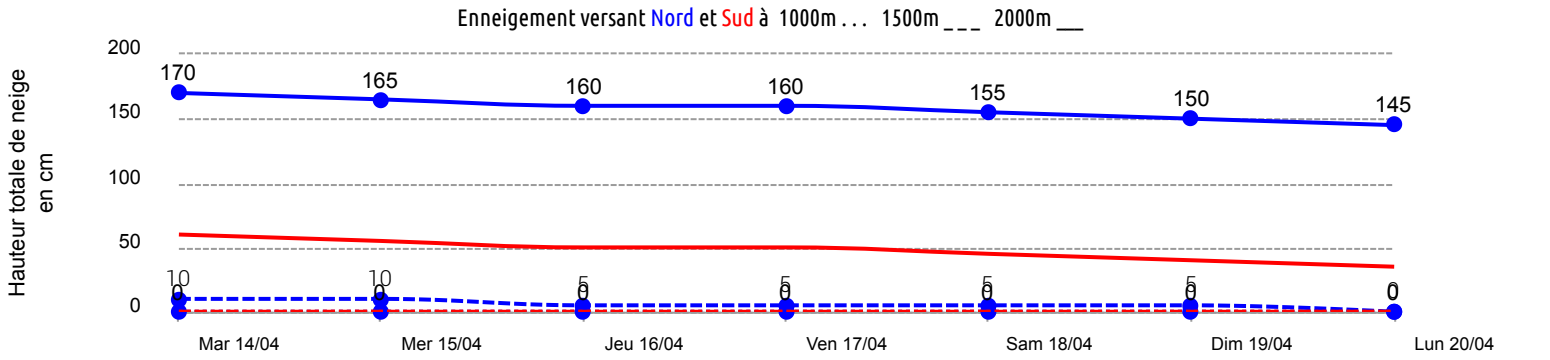

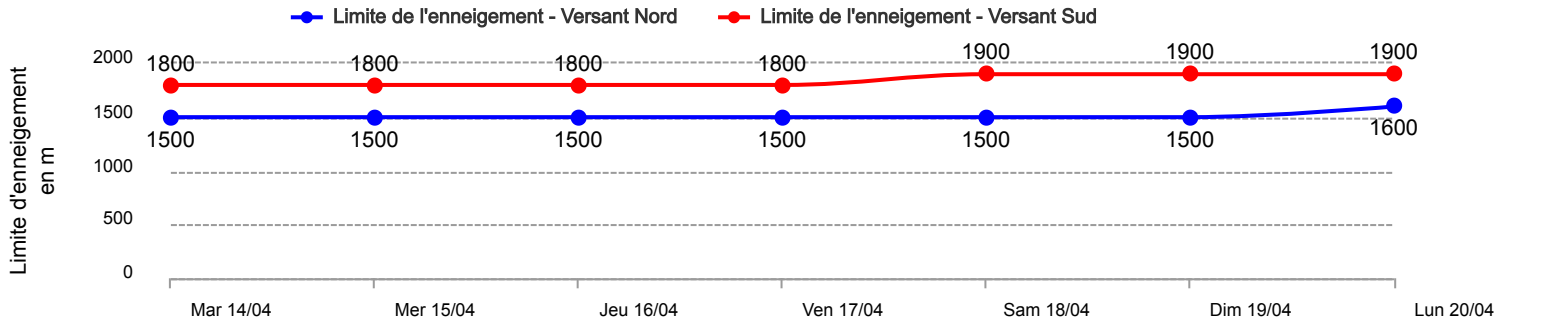

Pour consulter la vigilance en cours, veuillez vous rendre sur le site https://vigilance.meteofrance.fr/fr

Météo-France - 73 avenue de Paris, 94165 Saint-Mandé cedex - Contact : contact@meteo.fr

Rédigé par Météo-France avec la contribution des observateurs du réseau nivo-météorologiques. Partenariat : ANMSM (Maires de Stations de Montagne), DSF (Domaines Skiables de France), ADSP (Directeurs de Pistes et de la Sécurité des Stations de Sports d'Hiver) et autres acteurs de la montagne.

Bulletin neige & avalanches par téléphone au
0 892 68 10 20 Service 0,35 € / min + prix appel