RÉPUBLIQUE FRANÇAISE
Liberté Égalité Fraternité

METEO FRANCE
À VOS CÔTÉS, DANS UN CLIMAT QUI CHANGE

Bulletin d'estimation du risque d'avalanche
(valable en dehors des pistes balisées et ouvertes)

MASSIF : Aspe Ossau

Rédigé le lundi 20 avril 2026 à 16h

Estimation des risques pour le : MARDI 21 AVRIL

HUMIDIFICATION EN PROFONDEUR.

2

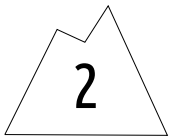

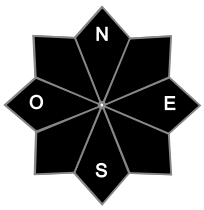

Indice de risque limité.

Départs spontanés : en neige humide et avalanches de fond ou de glissement.

Déclenchements provoqués : en neige humide.

Indices de risque : 5 très fort - 4 fort - 3 marqué - 2 limité - 1 faible -- En noir : les pentes les plus dangereuses

Stabilité du manteau neigeux

Situation avalancheuse typique : neige humide avalanches de fond

Départs spontanés : manteau neigeux **humidifié sur toute son épaisseur, regel nocturne timide et peu épais au-dessus de 2300/2400m**.
Activité **très faible en fin de nuit et début de matinée**, puis, dans la douceur ambiante, sous le soleil du matin et sous les quelques averses de l'après-midi, manteau neigeux très humide à gorgé d'eau, favorable à des **départs ponctuels de plus en plus nombreux** en **pentes raides**, souvent de **petite taille**. **Quelques avalanches de fond ou de glissement** de taille **moyenne** à **localement grande** encore possibles au plus doux et au plus humide de la journée, partant des accumulations encore présentes en altitude.
Aucune orientation ne sera épargnée, **départs à proximité des rochers, des zones déneigées** et des **nombreuses fissures ouvertes**.

Déclenchements provoqués : en **neige humide exclusivement**.
Au passage d'**un skieur ou randonneur**, **déclenchement facile** de **neige humide à très humide** (en nord au-dessus de 2400/2500m) **à gorgée d'eau** (partout ailleurs), plutôt des **coulées ou petites avalanches en versant nord**, **avalanches petites à moyennes en sud** sur le haut du massif.

Autres : corniches et ponts de neige encore en place extrêmement peu résistants.

Qualité de la neige

Enneigement : plutôt bon pour la saison et débutant encore vers 1650m en nord, 2000m en sud.
Les limites de cet enneigement remontent progressivement dans la douceur ambiante, sous les éclaircies matinales et les quelques averses de l'après-midi.
État de la neige : au petit matin, regel nocturne timide et en surface au-dessus de 2300/2400m (manteau neigeux plus ou moins portant), inexistant en dessous.
Manteau neigeux humidifié sur toute son épaisseur, devenant au cours de la journée humide à très humide en nord, humide à gorgé d'eau voire pourri en sud.

Aperçu météo pour le mardi 21 avril

	nuit	matin	après-midi	soir

Dégagé la nuit avec regel peu épais au-dessus de 2300/2400m, beau et sec le matin, quelques averses l'après-midi. Vent plus sensible en soirée.

Pluie-Neige			3 200 m	
Iso 0 °C	3 200 m	3 300 m	3 500 m	3 500 m
Vent 1500 m	↑ 10 km/h	↑ 5 km/h	↑ 10 km/h	↑ 20 km/h
Vent 3000 m	→ 20 km/h	↗ 35 km/h	↑ 40 km/h	↗ 55 km/h

Épaisseur de neige hors-piste

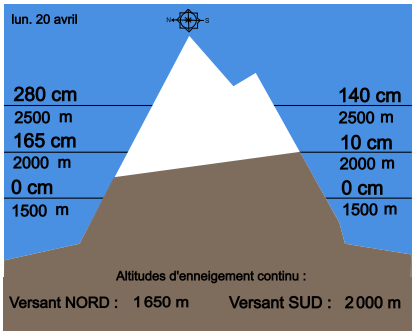

Précipitations à 1800 m

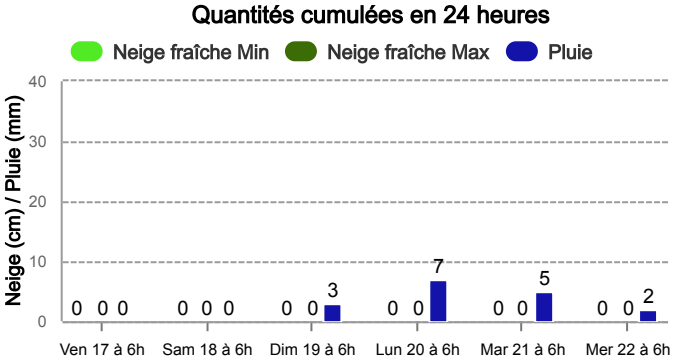

Tendance du mercredi 22 avril

2

Indice de risque limité

Après regel nocturne timide, temps doux, beau et sec le matin, averses l'après-midi : le risque restera limité en neige humide.

Pour consulter la vigilance en cours, veuillez vous rendre sur le site https://vigilance.meteofrance.fr/fr

Météo-France - 73 avenue de Paris, 94165 Saint-Mandé cedex - Contact : contact@meteo.fr

Rédigé par Météo-France avec la contribution des observateurs du réseau nivo-météorologiques. Partenariat : ANMSM (Maires de Stations de Montagne), DSF (Domaines Skiables de France), ADSP (Directeurs de Pistes et de la Sécurité des Stations de Sports d'Hiver) et autres acteurs de la montagne.

Bulletin neige & avalanches par téléphone au
0 892 68 10 20 Service 0,35 € / min + prix appel

RÉPUBLIQUE FRANÇAISE
Liberté Égalité Fraternité

METEO FRANCE
À VOS CÔTÉS, DANS UN CLIMAT QUI CHANGE

Bulletin d'estimation du risque d'avalanche

(valable en dehors des pistes balisées et ouvertes)

MASSIF : Aspe Ossau

Rédigé le lundi 20 avril 2026 à 16h

Conditions nivo-météo des 7 derniers jours

	mar. 14/04				mer. 15/04				jeu. 16/04				ven. 17/04				sam. 18/04				dim. 19/04				lun. 20/04			
	03h	09h	15h	21h	03h	09h	15h	21h	03h	09h	15h	21h	03h	09h	15h	21h	03h	09h	15h	21h	03h	09h	15h	21h	03h	09h	15h	21h
Météo																												
Vent (km/h)	30	35	30	20	20	15	15	15	15	15	10	10	10	10	10	10	10	5	10	15	20	20	25	25	25	20	55	25
à 3000m																												
Vent (km/h)	15	20	25	10	10	10	10	5	5	5	5	5	5	5	5	5	10	5	10	10	10	10	15	10	5	5	15	10
à 1500m																												

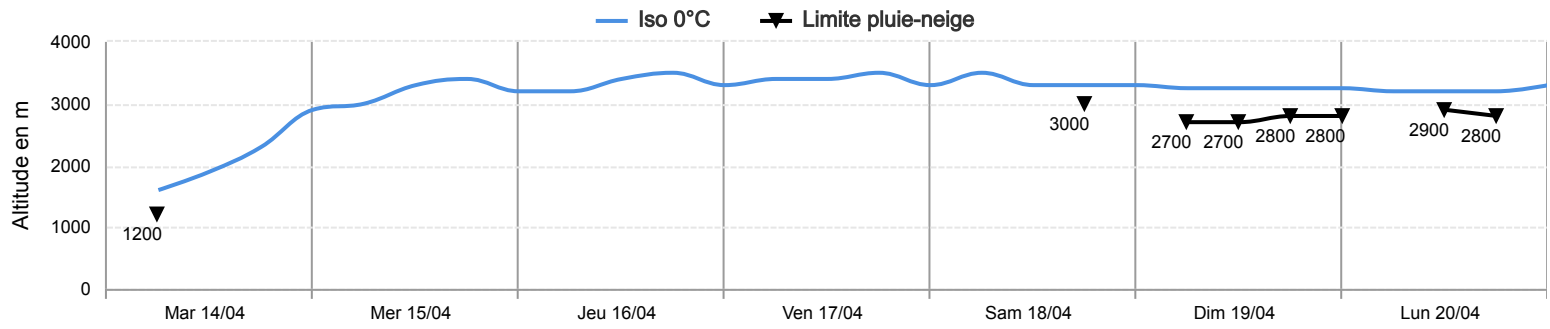

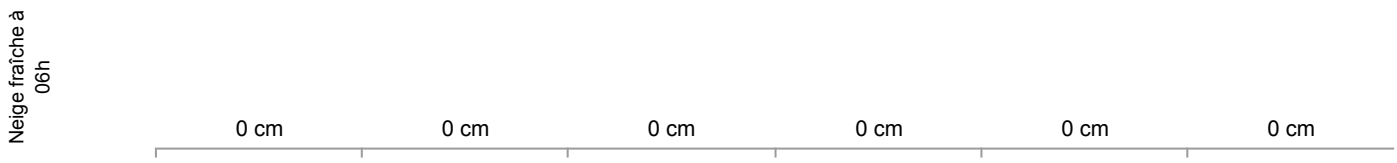

Risque d'avalanche	mar. 14/04	mer. 15/04	jeu. 16/04	ven. 17/04	sam. 18/04	dim. 19/04	lun. 20/04
	2	2	2	2	2	2	2

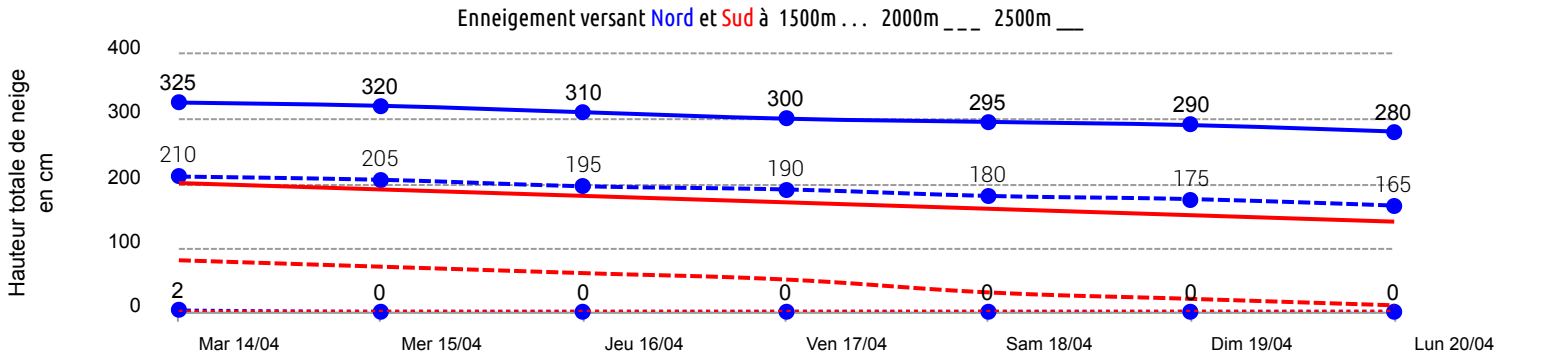

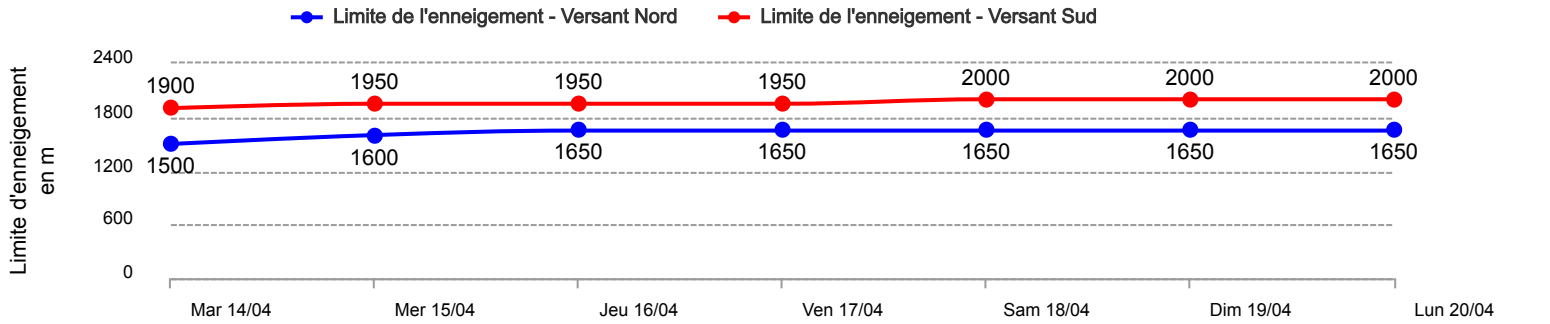

Pour consulter la vigilance en cours, veuillez vous rendre sur le site https://vigilance.meteofrance.fr/fr

Météo-France - 73 avenue de Paris, 94165 Saint-Mandé cedex - Contact : contact@meteo.fr

Rédigé par Météo-France avec la contribution des observateurs du réseau nivo-météorologiques. Partenariat : ANMSM (Maires de Stations de Montagne), DSF (Domaines Skiables de France), ADSP (Directeurs de Pistes et de la Sécurité des Stations de Sports d'Hiver) et autres acteurs de la montagne.

Bulletin neige & avalanches par téléphone au

0 892 68 10 20 Service 0,35 € / min + prix appel