Bulletin d'estimation du risque d'avalanche
(valable en dehors des pistes balisées et ouvertes)

MASSIF : Bauges

Rédigé le lundi 20 avril 2026 à 16h

Estimation des risques pour le : MARDI 21 AVRIL

1

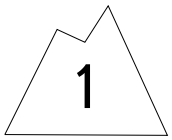

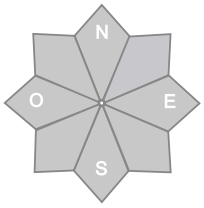

Indice de risque faible.

Départs spontanés : rares avalanches de neige humide

Déclenchements provoqués : rares avalanches de neige humide

Indices de risque : 5 très fort - 4 fort - 3 marqué - 2 limité - 1 faible -- En noir : les pentes les plus dangereuses

Stabilité du manteau neigeux

Situation avalancheuse typique : avalanches de fond neige humide

Départs spontanés :
* fissures de reptation sur entes raides herbeuses très raides et dalles rocheuses. Plaques de fond rares mais possibles, à toute heure. Taille 1 à 2 (petite à moyenne).
* avalanches de neige humide, au fil de l'ensoleillement, et surtout en mi-journée/après-midi. Départs ponctuels en surface, s'élargissant en forme de poire, et pouvant racler toute la neige jusqu'au sol. Taille 1 à 2.

Déclenchements provoqués :
* un skieur peut pousser une avalanche de neige humide, une fois le manteau réchauffé par le soleil. Principalement en pentes raides. Taille 1 à 2.

Observables : enfoncement piéton important.

Qualité de la neige

Enneigement :
il reste encore pas mal de neige dans les ubacs au-dessus de 1600 m. Dans les versants S, on peut encore trouver quelques bancs de neige au-dessus de 1800 m.

Qualité de la neige ce mardi :
* manteau neigeux printanier. Assez bon regel nocturne : neige dure le matin, puis rapidement humide voire très humide en journée.

Aperçu météo pour le mardi 21 avril

	nuit	matin	après-midi	soir

Soleil et douceur. Petits Cumulus l'après-midi. +6 DG à 2000 m l'après-midi.

Pluie-Neige				
Iso 0 °C	2 600 m	2 600 m	2 600 m	2 700 m
Vent 1500 m	↓ 10 km/h	↓ 15 km/h	↓ 20 km/h	↓ 10 km/h
Vent 2000 m	↓ 20 km/h	↘ 20 km/h	↘ 30 km/h	↓ 20 km/h

Épaisseur de neige hors-piste

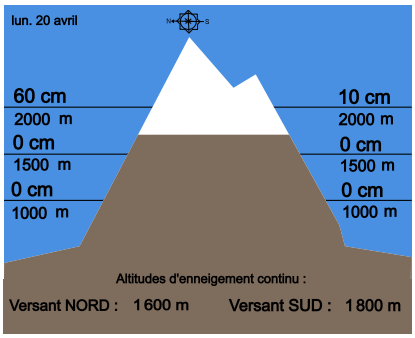

Précipitations à 1800 m

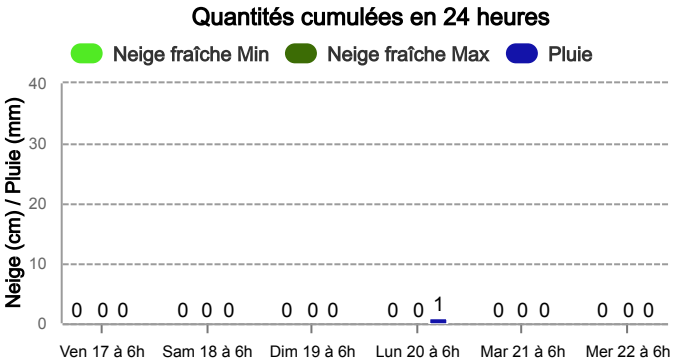

Tendance du mercredi 22 avril

1

Indice de risque faible

encore de rares avalanches de neige humide, surtout l'après-midi.

Pour consulter la vigilance en cours, veuillez vous rendre sur le site https://vigilance.meteofrance.fr/fr

Météo-France - 73 avenue de Paris, 94165 Saint-Mandé cedex - Contact : contact@meteo.fr

Rédigé par Météo-France avec la contribution des observateurs du réseau nivo-météorologiques. Partenariat : ANMSM (Maires de Stations de Montagne), DSF (Domaines Skiables de France), ADSP (Directeurs de Pistes et de la Sécurité des Stations de Sports d'Hiver) et autres acteurs de la montagne.

Bulletin neige & avalanches par téléphone au 0 892 68 10 20 Service 0,35 € / min + prix appel

RÉPUBLIQUE FRANÇAISE
Liberté Égalité Fraternité

METEO FRANCE
À VOS CÔTÉS, DANS UN CLIMAT QUI CHANGE

Bulletin d'estimation du risque d'avalanche

(valable en dehors des pistes balisées et ouvertes)

MASSIF : Bauges

Rédigé le lundi 20 avril 2026 à 16h

Conditions nivo-météo des 7 derniers jours

	mar. 14/04				mer. 15/04				jeu. 16/04				ven. 17/04				sam. 18/04				dim. 19/04				lun. 20/04			
	03h	09h	15h	21h	03h	09h	15h	21h	03h	09h	15h	21h	03h	09h	15h	21h	03h	09h	15h	21h	03h	09h	15h	21h	03h	09h	15h	21h
Météo																												
Vent (km/h)	20	25	20	15	10	10	10	10	20	15	20	10	20	20	10	10	10	10	10	10	15	25	25	15	20	25	30	20
à 2000m																												
Vent (km/h)	15	20	20	10	5	5	10	5	15	10	15	5	10	10	5	5	5	5	5	5	10	15	20	10	10	15	20	10
à 1500m																												

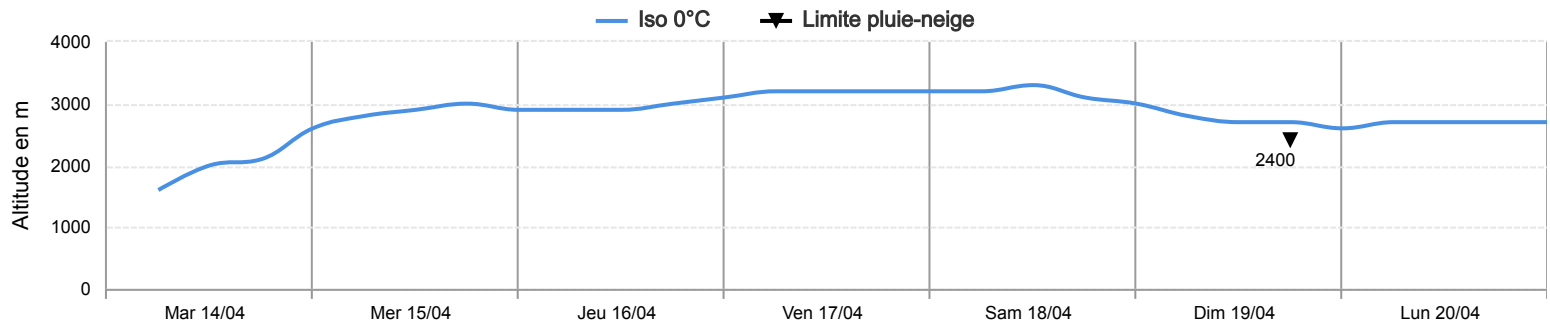

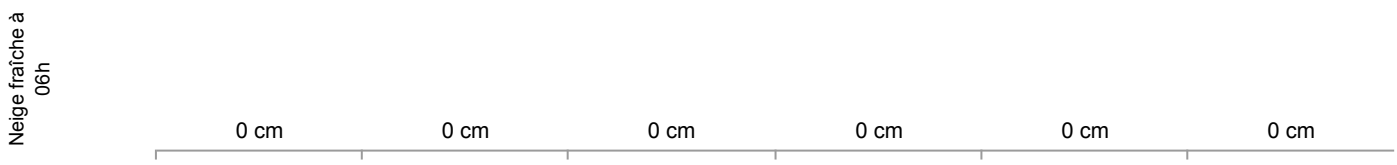

Risque d'avalanche							
	2	2	2	2	1	1	1
	mar. 14/04	mer. 15/04	jeu. 16/04	ven. 17/04	sam. 18/04	dim. 19/04	lun. 20/04

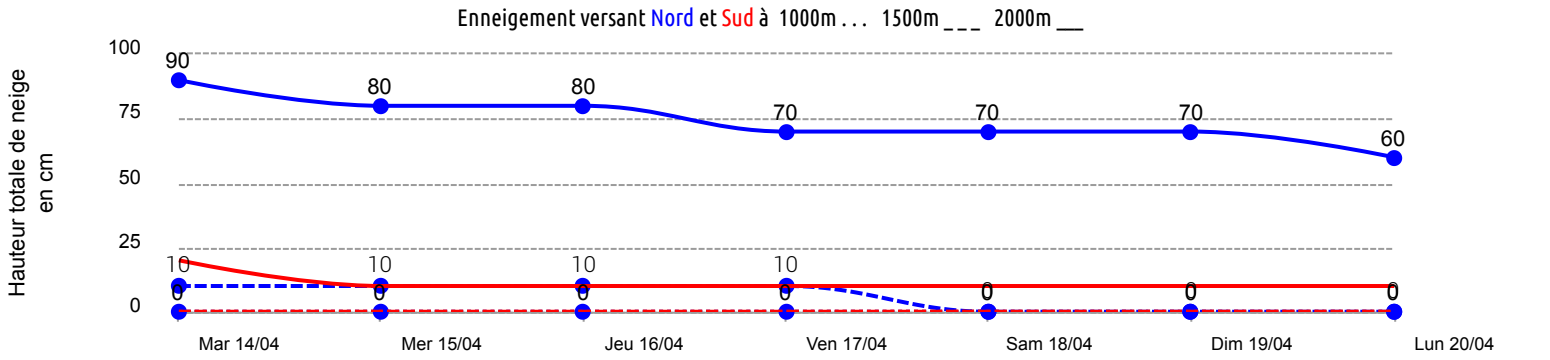

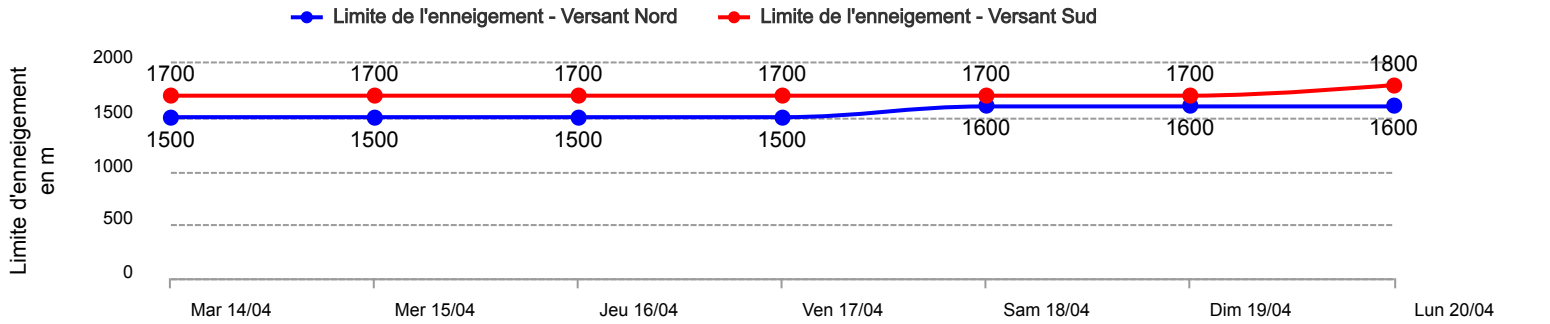

Pour consulter la vigilance en cours, veuillez vous rendre sur le site https://vigilance.meteofrance.fr/fr

Météo-France - 73 avenue de Paris, 94165 Saint-Mandé cedex - Contact : contact@meteo.fr

Bulletin neige & avalanches par téléphone au

0 892 68 10 20 Service 0,35 € / min + prix appel

Rédigé par Météo-France avec la contribution des observateurs du réseau nivo-météorologiques. Partenariat : ANMSM (Maires de Stations de Montagne), DSF (Domaines Skiables de France), ADSP (Directeurs de Pistes et de la Sécurité des Stations de Sports d'Hiver) et autres acteurs de la montagne.