Bulletin d'estimation du risque d'avalanche
(valable en dehors des pistes balisées et ouvertes)

MASSIF : Mercantour

Rédigé le lundi 20 avril 2026 à 16h

Estimation des risques pour le : MARDI 21 AVRIL

MANTEAU NEIGEUX PRINTANIER - UN PEU D'ACTIVITÉ NATURELLE EN JOURNÉE

2

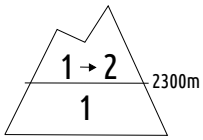

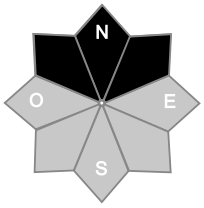

Au-dessus de 2300m indice de risque faible évoluant en limité, plus bas indice faible.

Départs spontanés : quelques avalanches de neige humide, généralement de taille limitée - une avalanche volumineuse possible en ubacs d'altitude.

Déclenchements provoqués : en neige humide sous les skis.

Indices de risque : 5 très fort - 4 fort - 3 marqué - 2 limité - 1 faible -- En noir : les pentes les plus dangereuses

Stabilité du manteau neigeux

Situation avalancheuse typique : neige humide

Départs spontanés : l'activité en neige humide est à nouveau en hausse en cours de journée. Avalanches superficielles de petite taille en général (taille 1), mais quelques départs linéaires plus volumineux sont possibles dans les pentes nord-ouest à nord-est au-dessus de 2300/2400 m environ, emportant la totalité du manteau neigeux en place. Avalanches moyennes (taille 2), voire très ponctuellement grandes (taille 3), si l'humidification atteint pour la première fois des couches fragiles persistantes enfouies dans le manteau neigeux.

Déclenchements provoqués : un skieur coupant une pente raide trop tardivement peut initier un départ de neige humide sous ses skis. À noter également que dans les ubacs d'altitude supérieure à 2300/2400 m, une première avalanche superficielle de neige humide déclenchée par un skieur peut dans de très rares cas provoquer un second départ linéaire plus volumineux.

Qualité de la neige

Enneigement nettement déficitaire pour la période, avec une fonte qui se poursuit à un rythme élevé. Absence de précipitations significatives depuis plus d'1 mois et grande douceur en place depuis début avril.
Hauteurs de neige observées : 86 cm à la Nivose de Millefonts à 2430 m, 23 cm à Isola 2000 à 1900 m.

Enneigement skiable généralement à partir de 1900/2000 m en ubacs sur terrain favorable (routes forestières, terrains herbeux) et 2300/2400 m en adrets peu pentus.

État de la neige en surface : manteau neigeux printanier, croûté le matin, puis s'humidifiant rapidement au soleil en cours de journée dans toutes les expositions.

Aperçu météo pour le mardi 21 avril

	nuit	matin	après-midi	soir

Temps printanier, soleil dominant, quelques cumulus l'après-midi avec une averse possible en Vésubie/Roya. Températures maximales à 2000 m : 12 à 14 °C. Vent d'ouest sensible sur les crêtes.

Pluie-Neige	2 600 m			
Iso 0 °C	2 900 m	3 000 m	3 000 m	3 000 m
Vent 2000 m	↘ 15 km/h	→ 15 km/h	→ 20 km/h	↘ 10 km/h
Vent 3000 m	→ 35 km/h	→ 40 km/h	→ 40 km/h	→ 30 km/h

Épaisseur de neige hors-piste

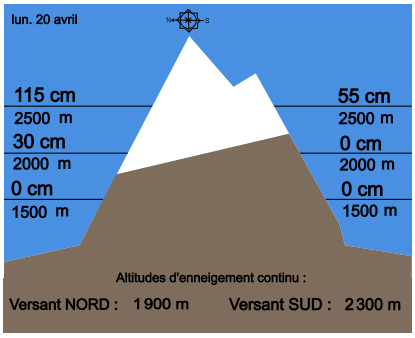

Précipitations à 1800 m

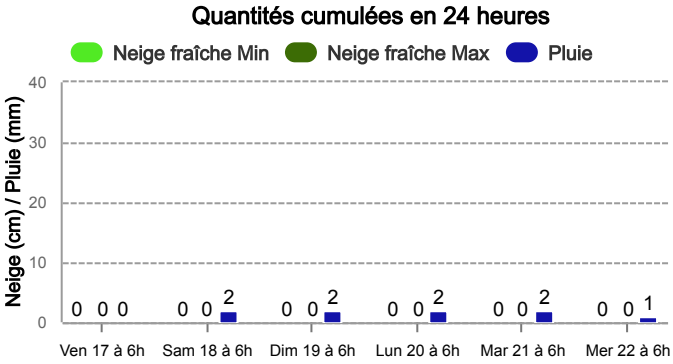

Tendance du mercredi 22 avril

2

Indice de risque limité

La situation nivologique reste similaire et pilotée par l'activité en neige humide au cours de la journée. Rares départs linéaires volumineux dans les ubacs d'altitude.

Pour consulter la vigilance en cours, veuillez vous rendre sur le site https://vigilance.meteofrance.fr/fr

Météo-France - 73 avenue de Paris, 94165 Saint-Mandé cedex - Contact : contact@meteo.fr

Rédigé par Météo-France avec la contribution des observateurs du réseau nivo-météorologiques. Partenariat : ANMSM (Maires de Stations de Montagne), DSF (Domaines Skiables de France), ADSP (Directeurs de Pistes et de la Sécurité des Stations de Sports d'Hiver) et autres acteurs de la montagne.

Bulletin neige & avalanches par téléphone au 0 892 68 10 20 Service 0,35 € / min + prix appel

RÉPUBLIQUE FRANÇAISE
Liberté Égalité Fraternité

METEO FRANCE
À VOS CÔTÉS, DANS UN CLIMAT QUI CHANGE

Bulletin d'estimation du risque d'avalanche

(valable en dehors des pistes balisées et ouvertes)

MASSIF : Mercantour

Rédigé le lundi 20 avril 2026 à 16h

Conditions nivo-météo des 7 derniers jours

	mar. 14/04				mer. 15/04				jeu. 16/04				ven. 17/04				sam. 18/04				dim. 19/04				lun. 20/04			
	03h	09h	15h	21h	03h	09h	15h	21h	03h	09h	15h	21h	03h	09h	15h	21h	03h	09h	15h	21h	03h	09h	15h	21h	03h	09h	15h	21h
Météo																												
Vent (km/h)	40	40	40	40	35	25	20	10	15	10	20	5	10	15	20	10	15	10	25	20	20	30	40	30	30	35	35	30
à 3000m																												
Vent (km/h)	40	40	45	40	45	35	25	15	20	15	20	10	10	10	15	10	10	15	20	10	10	15	25	15	15	20	25	15
à 2000m																												

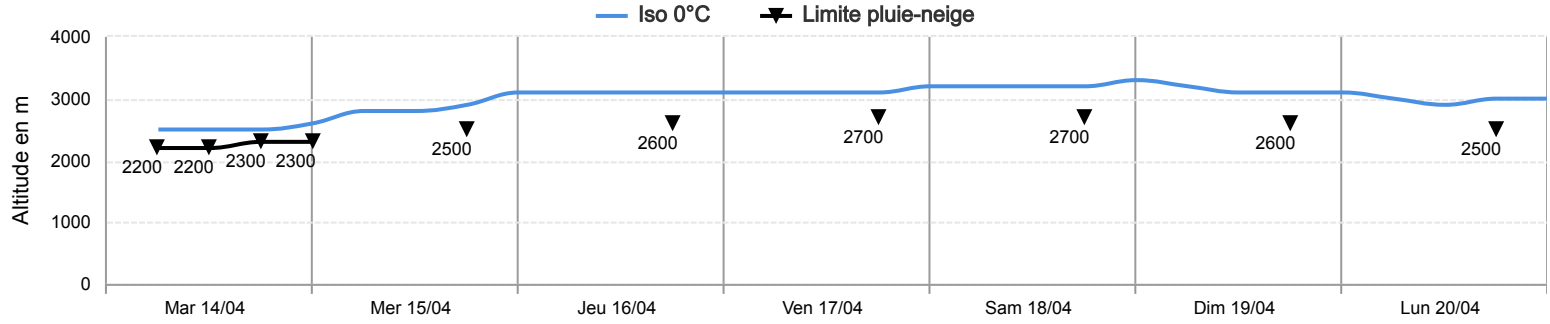

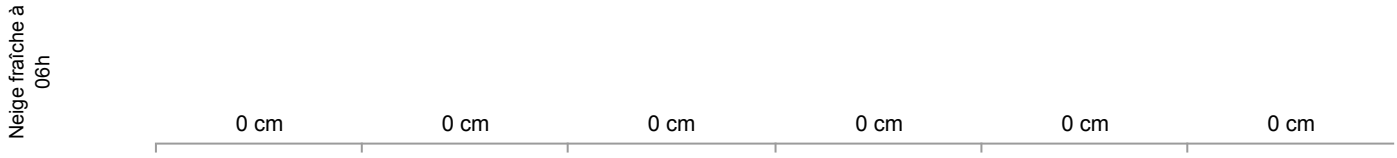

Risque d'avalanche	mar. 14/04	mer. 15/04	jeu. 16/04	ven. 17/04	sam. 18/04	dim. 19/04	lun. 20/04
	2	2	2	2	2	2	2

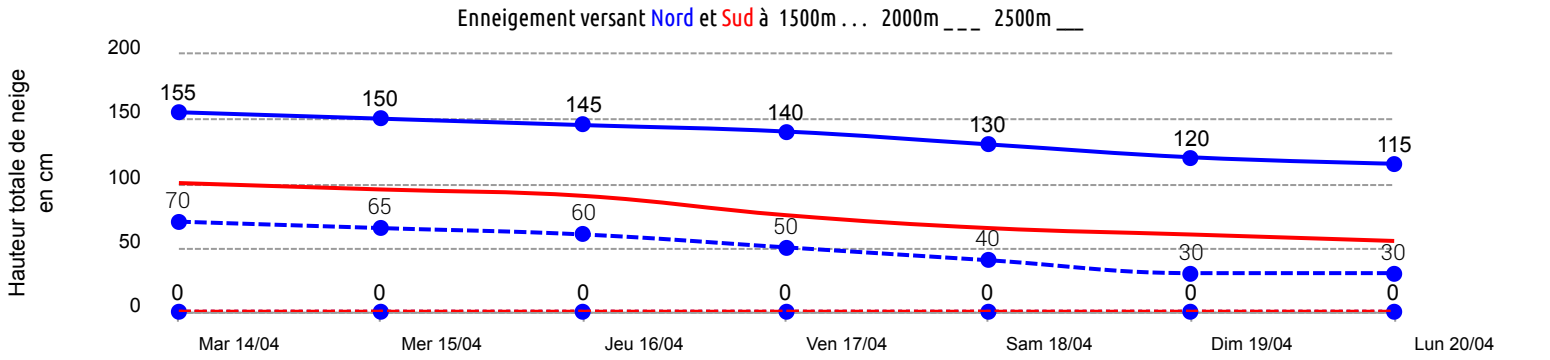

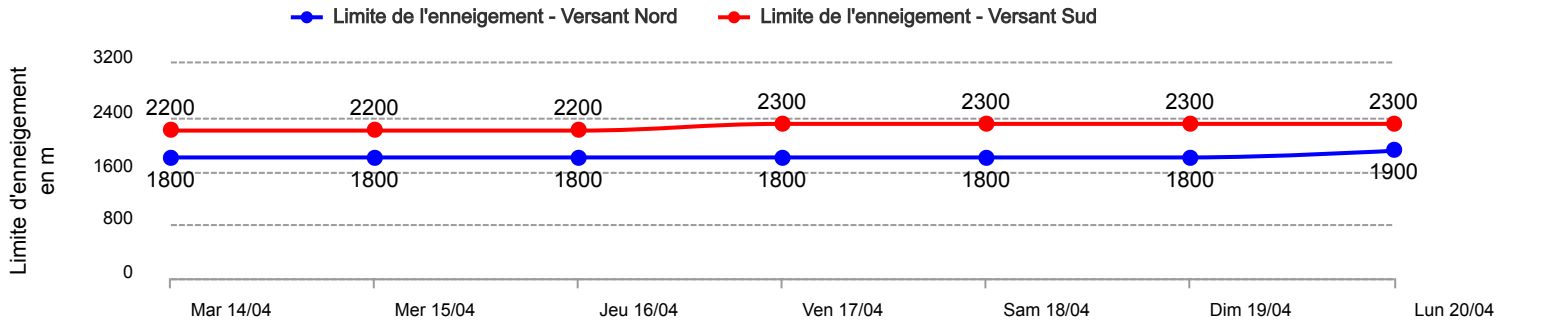

Pour consulter la vigilance en cours, veuillez vous rendre sur le site https://vigilance.meteofrance.fr/fr

Météo-France - 73 avenue de Paris, 94165 Saint-Mandé cedex - Contact : contact@meteo.fr

Rédigé par Météo-France avec la contribution des observateurs du réseau nivo-météorologiques. Partenariat : ANMSM (Maires de Stations de Montagne), DSF (Domaines Skiables de France), ADSP (Directeurs de Pistes et de la Sécurité des Stations de Sports d'Hiver) et autres acteurs de la montagne.

Bulletin neige & avalanches par téléphone au
0 892 68 10 20 Service 0,35 € / min + prix appel