Bulletin d'estimation du risque d'avalanche
(valable en dehors des pistes balisées et ouvertes)

MASSIF : Pays-Basque

Rédigé le lundi 20 avril 2026 à 16h

Estimation des risques pour le : MARDI 21 AVRIL

HUMIDIFICATION EN PROFONDEUR.

2

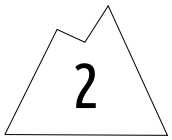

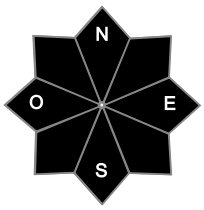

Indice de risque limité.

Départs spontanés : en neige humide, quelques avalanches de fond.

Déclenchements provoqués : en neige humide.

Indices de risque : 5 très fort - 4 fort - 3 marqué - 2 limité - 1 faible -- En noir : les pentes les plus dangereuses

Stabilité du manteau neigeux

Situation avalancheuse typique : neige humide avalanches de fond

Départs spontanés : manteau neigeux **humidifié sur toute son épaisseur, sans regel nocturne**.
Activité **très faible en fin de nuit et début de matinée**, puis, dans la douceur ambiante, sous le soleil du matin et sous les quelques averses de l'après-midi, manteau neigeux très humide à gorgé d'eau, favorable à des **départs ponctuels de plus en plus nombreux** en **pentes raides** encore enneigées, souvent de **petite taille**. **Quelques avalanches de fond ou de glissement** de taille **moyenne** encore possibles au plus doux et au plus humide de la journée, partant des quelques accumulations encore en place au plus haut du massif vers le secteur du Pic d'Anie.
Aucune orientation ne sera épargnée, **départs à proximité des rochers, des zones déneigées** et des **nombreuses fissures ouvertes**.

Déclenchements provoqués : en **neige humide exclusivement**.
Au passage d'**un skieur ou randonneur**, **déclenchement aisé** de **neige très humide à gorgée d'eau**, plutôt des **coulées en versant nord**, **petites avalanches à très rarement moyennes en sud** sur le haut du massif, dans le **secteur du Pic d'Anie** essentiellement.

Autres : corniches et ponts de neige encore en place extrêmement peu résistants.

Qualité de la neige

Enneigement : plutôt bon pour la saison vers La Pierre-Saint-Martin, débutant vers 1650m en nord et 2000m en sud.
Les limites de cet enneigement remontent progressivement dans la douceur ambiante, sous les éclaircies matinales et les quelques averses de l'après-midi. Enneigement discontinu et faible en allant vers l'ouest (pic d'Orhy).
État de la neige : pas de regel nocturne, manteau neigeux humidifié sur toute son épaisseur, humide mais encore assez portant au petit matin, devenant très humide (en nord) à gorgé d'eau (en sud) et pourri au cours de la journée.

Aperçu météo pour le mardi 21 avril

	nuit	matin	après-midi	soir

Dégagé la nuit mais sans regel, beau et sec le matin, quelques averses l'après-midi. Vent plus sensible en soirée.

Pluie-Neige			3 300 m	
Iso 0 °C	3 200 m	3 300 m	3 500 m	3 500 m
Vent 1000 m	↑ 10 km/h	↑ 10 km/h	↑ 10 km/h	↑ 15 km/h
Vent 2000 m	↗ 25 km/h	↑ 30 km/h	↑ 35 km/h	↑ 55 km/h

Épaisseur de neige hors-piste

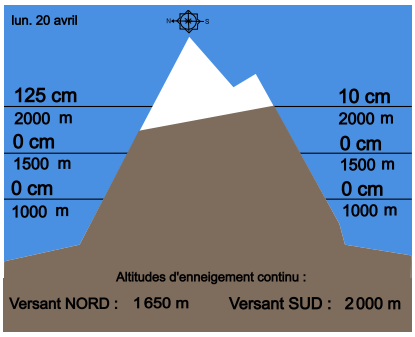

Précipitations à 1800 m

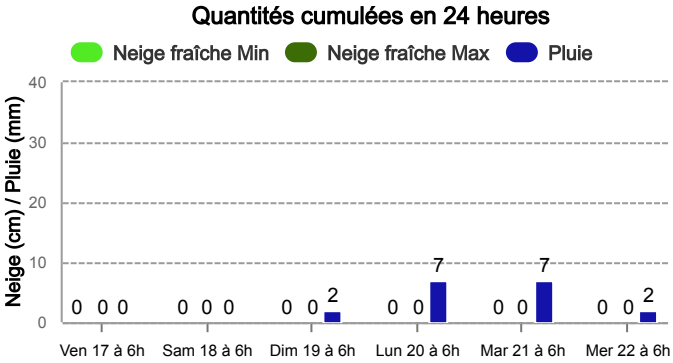

Tendance du mercredi 22 avril

2

Indice de risque limité

Pas de regel nocturne, temps doux, beau et sec le matin, rares averses l'après-midi : le risque restera limité en neige humide.

Pour consulter la vigilance en cours, veuillez vous rendre sur le site https://vigilance.meteofrance.fr/fr

Météo-France - 73 avenue de Paris, 94165 Saint-Mandé cedex - Contact : contact@meteo.fr

Rédigé par Météo-France avec la contribution des observateurs du réseau nivo-météorologiques. Partenariat : ANMSM (Maires de Stations de Montagne), DSF (Domaines Skiables de France), ADSP (Directeurs de Pistes et de la Sécurité des Stations de Sports d'Hiver) et autres acteurs de la montagne.

Bulletin neige & avalanches par téléphone au
0 892 68 10 20 Service 0,35 € / min + prix appel

RÉPUBLIQUE FRANÇAISE
Liberté Égalité Fraternité

METEO FRANCE
À VOS CÔTÉS, DANS UN CLIMAT QUI CHANGE

Bulletin d'estimation du risque d'avalanche
(valable en dehors des pistes balisées et ouvertes)
MASSIF : Pays-Basque

Rédigé le lundi 20 avril 2026 à 16h

Conditions nivo-météo des 7 derniers jours

	mar. 14/04				mer. 15/04				jeu. 16/04				ven. 17/04				sam. 18/04				dim. 19/04				lun. 20/04			
	03h	09h	15h	21h	03h	09h	15h	21h	03h	09h	15h	21h	03h	09h	15h	21h	03h	09h	15h	21h	03h	09h	15h	21h	03h	09h	15h	21h
Météo																												
Vent (km/h)	45	40	35	30	35	35	35	25	15	15	15	10	10	10	10	10	20	15	15	20	25	25	25	30	30	25	35	30
à 2000m	↓	↓	↓	↙	↙	↙	↓	←	←	↗	↗	→	→	↗	→	↘	↑	↘	↙	↑	↑	↗	↘	↑	↑	↗	↘	↑
Vent (km/h)	15	20	30	15	10	15	15	10	5	5	5	5	5	5	5	5	5	10	10	10	10	15	15	15	5	5	15	10
à 1000m	↓	↓	↓	↙	↓	↙	↓	↙	↙	↙	↙	↙	↙	↙	↙	↙	↙	↙	↙	←	↑	↑	↓	↗	↑	↓	↓	↑

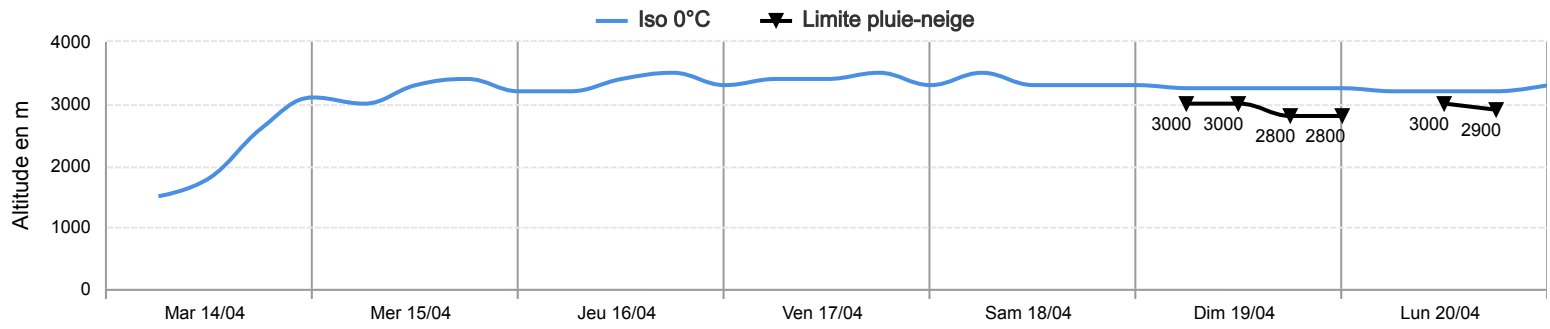

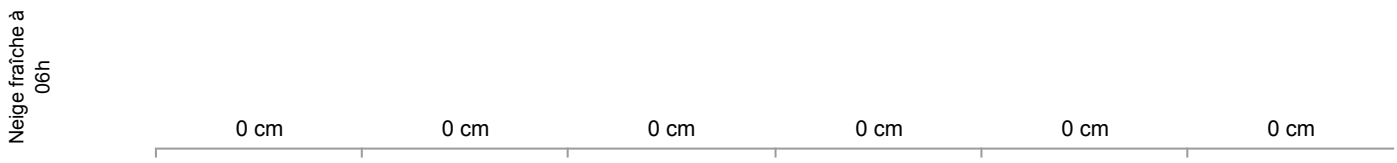

Risque d'avalanche	mar. 14/04	mer. 15/04	jeu. 16/04	ven. 17/04	sam. 18/04	dim. 19/04	lun. 20/04
	2	2	2	2	2	2	2

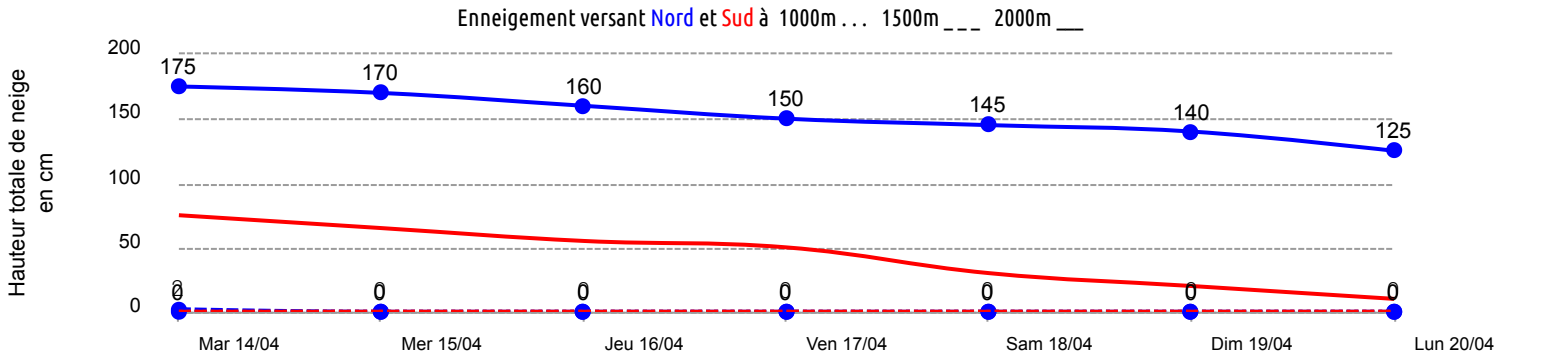

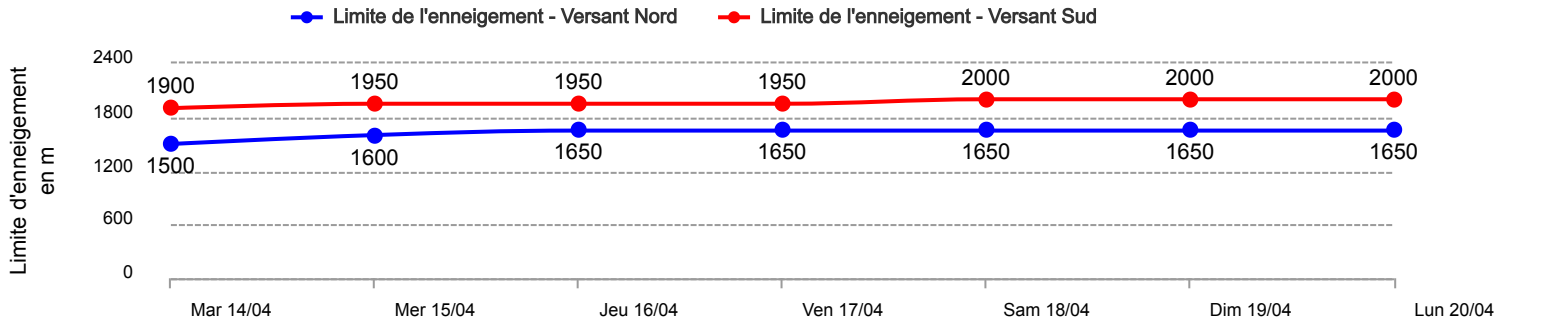

Pour consulter la vigilance en cours, veuillez vous rendre sur le site https://vigilance.meteofrance.fr/fr

Météo-France - 73 avenue de Paris, 94165 Saint-Mandé cedex - Contact : contact@meteo.fr

Rédigé par Météo-France avec la contribution des observateurs du réseau nivo-météorologiques. Partenariat : ANMSM (Maires de Stations de Montagne), DSF (Domaines Skiables de France), ADSP (Directeurs de Pistes et de la Sécurité des Stations de Sports d'Hiver) et autres acteurs de la montagne.

Bulletin neige & avalanches par téléphone au
0 892 68 10 20 Service 0,35 € / min + prix appel