# Bulletin d'estimation du risque d'avalanche
(valable en dehors des pistes balisées et ouvertes)

# MASSIF : Queyras

Rédigé le lundi 20 avril 2026 à 16h

## Estimation des risques pour le : MARDI 21 AVRIL

**MANTEAU NEIGEUX PRINTANIER ET BIEN STABLE EN GÉNÉRAL**

2

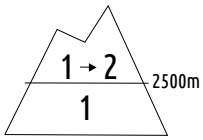


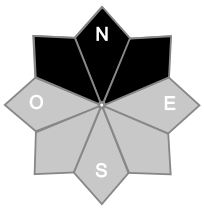


Au-dessus de 2500m indice de risque faible évoluant en limité, plus bas indice faible.

**Départs spontanés :** rares en neige humide en altitude.

**Déclenchements provoqués :** rares en neige humide en altitude.

Indices de risque : 5 très fort - 4 fort - 3 marqué - 2 limité - 1 faible -- En noir : les pentes les plus dangereuses

## Stabilité du manteau neigeux

**Situation avalancheuse typique :** neige humide

**Déclenchements provoqués** : le manteau neigeux est ancien, très dense et bien stable en général. Les instabilités en neige humide sont localisées uniquement en versants nord d'altitude comprise entre 2500 et 3000 m environ. Avalanches pouvant être déclenchées par un skieur, généralement ponctuelles et de petite taille (taille 1), plus rarement moyenne (taille 2). Exceptionnellement, une avalanche de grande taille (taille 3) n'est pas exclue. L'humidification qui se poursuit et qui est très en avance pour la saison peut encore atteindre dans ces orientations des couches fragiles enfouies vers la base du manteau neigeux. Dans les autres orientations où la neige est déjà humidifiée sur toute l'épaisseur, le risque est faible, le fait de faire glisser la neige mouillée en surface ne constitue pas un risque d'avalanche

**Départs spontanés** : peu probables en tout début de journée après un regel nocturne plutôt bon, puis de rares départs de taille 1 à 2 (exceptionnellement taille 3) en ubacs d'altitude humidifiés au soleil, parfois jusqu'au sol après un premier départ de surface.

## Qualité de la neige

**Enneigement** très déficitaire pour une mi-avril, notamment en adrets, souvent secs jusqu'à plus de 2500 m.
Hauteurs de neige observées : 91 cm en versant nord du col Izoard à 2300 m, 49 cm à la Nivôse du Col Agnel à 2630 m.

**Limite d'enneigement skiable** : au plus bas à 1900 m en ubacs bien protégés ou sur pistes forestières vers le Briançonnais, plus souvent 2000/2100 m.

**État de la neige de surface** : neige de type névé en toute orientation sous 2300/2400 m environ et en adrets d'altitude, regel très limité et superficiel, inexistant en forêts. Manteau neigeux pas encore totalement transformé au-dessus en ubacs et en de plus larges orientations au-dessus de 2800/3000 m, avec un bon regel nocturne. Poursuite de l'humidification en journée.

## Aperçu météo pour le mardi 21 avril

| | nuit | matin | après-midi | soir |
|---|---|---|---|---|
| | | | | |
| Toujours chaud, ensoleillé et sec | | | | |
| **Pluie-Neige** | | | | |
| **Iso 0 °C** | 2 900 m | 2 800 m | 3 000 m | 3 000 m |
| **Vent 2000 m** | → 10 km/h | → 15 km/h | ↗ 30 km/h | → 10 km/h |
| **Vent 3000 m** | → 30 km/h | → 30 km/h | → 40 km/h | → 25 km/h |

## Épaisseur de neige hors-piste

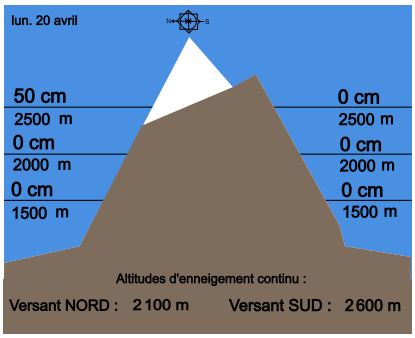


## Précipitations à 1800 m

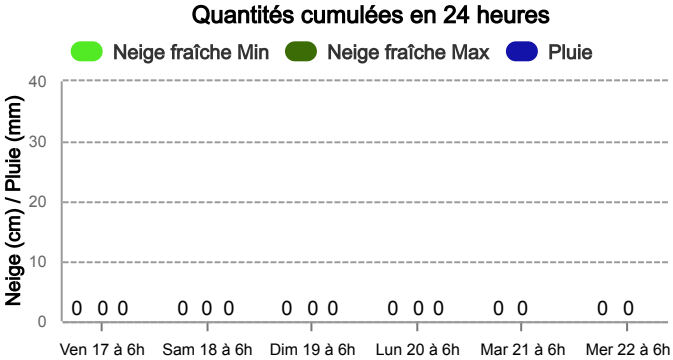


## Tendance du mercredi 22 avril

1

**Indice de risque faible**

Temps moins chaud, humidification moins prononcée. Risque faible.

Pour consulter la vigilance en cours, veuillez vous rendre sur le site https://vigilance.meteofrance.fr/fr

Météo-France - 73 avenue de Paris, 94165 Saint-Mandé cedex - Contact : contact@meteo.fr

Rédigé par Météo-France avec la contribution des observateurs du réseau nivo-météorologiques. Partenariat : ANMSM (Maires de Stations de Montagne), DSF (Domaines Skiables de France), ADSP (Directeurs de Pistes et de la Sécurité des Stations de Sports d'Hiver) et autres acteurs de la montagne.

Bulletin neige & avalanches par téléphone au 0 892 68 10 20 Service 0,35 € / min + prix appel

RÉPUBLIQUE FRANÇAISE
*Liberté Égalité Fraternité*

METEO FRANCE
À VOS CÔTÉS, DANS UN CLIMAT QUI CHANGE

# Bulletin d'estimation du risque d'avalanche

## (valable en dehors des pistes balisées et ouvertes)

# MASSIF : Queyras

Rédigé le lundi 20 avril 2026 à 16h

## Conditions nivo-météo des 7 derniers jours

| | mar. 14/04 | | | | mer. 15/04 | | | | jeu. 16/04 | | | | ven. 17/04 | | | | sam. 18/04 | | | | dim. 19/04 | | | | lun. 20/04 | | | |
|---|---|---|---|---|---|---|---|---|---|---|---|---|---|---|---|---|---|---|---|---|---|---|---|---|---|---|---|---|
| | 03h | 09h | 15h | 21h | 03h | 09h | 15h | 21h | 03h | 09h | 15h | 21h | 03h | 09h | 15h | 21h | 03h | 09h | 15h | 21h | 03h | 09h | 15h | 21h | 03h | 09h | 15h | 21h |
| Météo | | | | | | | | | | | | | | | | | | | | | | | | | | | | |
| Vent (km/h) | 35 | 30 | 30 | 30 | 25 | 20 | 10 | 5 | 10 | 10 | 15 | 5 | 5 | 5 | 5 | 5 | 10 | 15 | 10 | 5 | 20 | 30 | 25 | 30 | 25 | 30 | 35 | 30 |
| à 3000m | | | | | | | | | | | | | | | | | | | | | | | | | | | | |
| Vent (km/h) | 15 | 20 | 25 | 20 | 15 | 15 | 15 | 5 | 10 | 10 | 15 | 5 | 5 | 5 | 5 | 5 | 5 | 10 | 15 | 10 | 10 | 20 | 30 | 15 | 10 | 20 | 30 | 15 |
| à 2000m | | | | | | | | | | | | | | | | | | | | | | | | | | | | |

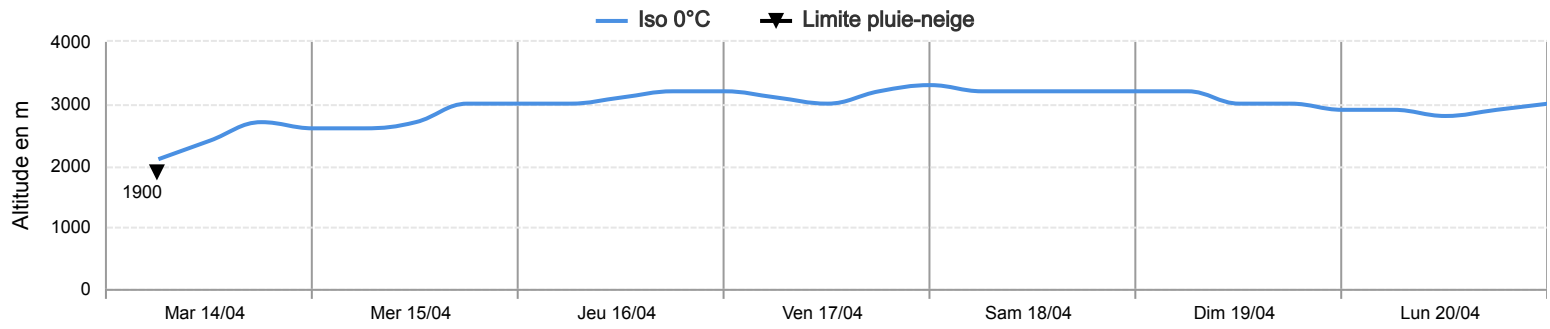


Neige fraîche à 06h

0 cm | 0 cm | 0 cm | 0 cm | 0 cm | 0 cm

| Risque d'avalanche | mar. 14/04 | mer. 15/04 | jeu. 16/04 | ven. 17/04 | sam. 18/04 | dim. 19/04 | lun. 20/04 |
|---|---|---|---|---|---|---|---|
| | 3 | 2 | 2 | 2 | 2 | 2 | 2 |

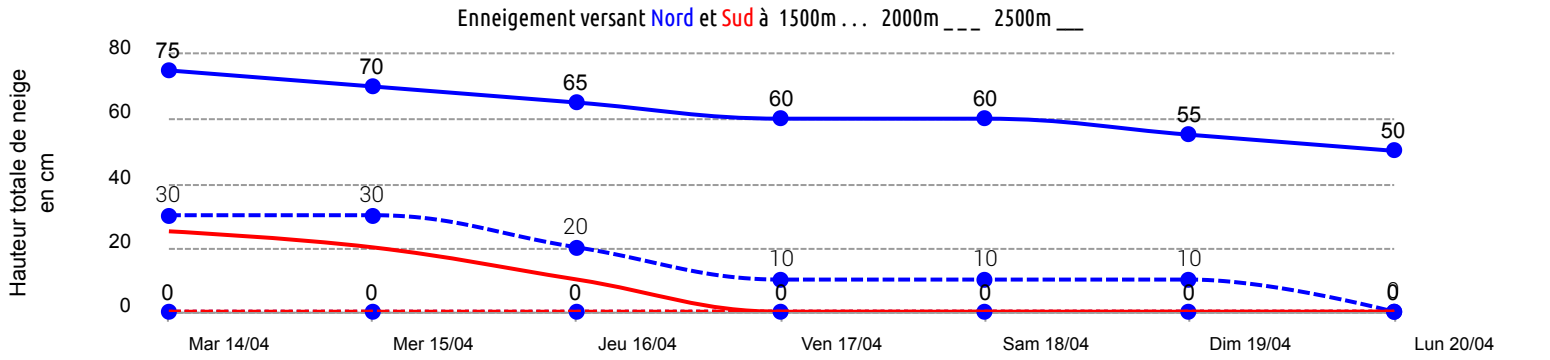


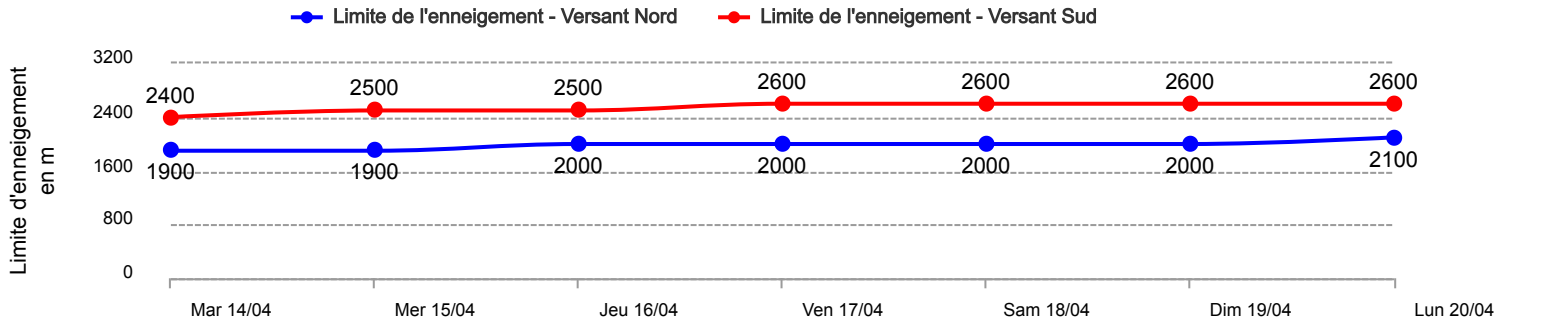


Pour consulter la vigilance en cours, veuillez vous rendre sur le site https://vigilance.meteofrance.fr/fr


Météo-France - 73 avenue de Paris, 94165 Saint-Mandé cedex - Contact : contact@meteo.fr


Rédigé par Météo-France avec la contribution des observateurs du réseau nivo-météorologiques. Partenariat : ANMSM (Maires de Stations de Montagne), DSF (Domaines Skiables de France), ADSP (Directeurs de Pistes et de la Sécurité des Stations de Sports d'Hiver) et autres acteurs de la montagne.

Bulletin neige & avalanches par téléphone au

**0 892 68 10 20** Service 0,35 € / min + prix appel