Bulletin d'estimation du risque d'avalanche
(valable en dehors des pistes balisées et ouvertes)

MASSIF : Thabor

Rédigé le lundi 20 avril 2026 à 16h

Estimation des risques pour le : MARDI 21 AVRIL

MANTEAU NEIGEUX PRINTANIER ET BIEN STABLE EN GÉNÉRAL

2

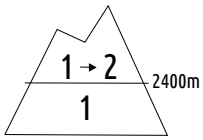

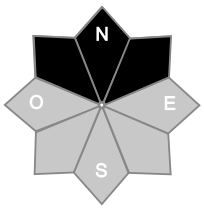

Au-dessus de 2400m indice de risque faible évoluant en limité, plus bas indice faible.

Départs spontanés : rares en neige humide en altitude.

Déclenchements provoqués : rares en neige humide en altitude.

Indices de risque : 5 très fort - 4 fort - 3 marqué - 2 limité - 1 faible -- En noir : les pentes les plus dangereuses

Stabilité du manteau neigeux

Situation avalancheuse typique : neige humide

Déclenchements provoqués : le manteau neigeux est ancien, très dense et bien stable en général. Les instabilités en neige humide sont localisées uniquement en versants nord d'altitude supérieure au-dessus de 2400 m environ. Avalanches pouvant être déclenchées par un skieur, généralement ponctuelles et de petite taille (taille 1), plus rarement moyenne (taille 2). Exceptionnellement, une avalanche de grande taille (taille 3) n'est pas exclue. L'humidification qui se poursuit et qui est très en avance pour la saison peut encore atteindre dans ces orientations des couches fragiles enfouies vers la base du manteau neigeux. Dans les autres orientations où la neige est déjà humidifiée sur toute l'épaisseur, le risque est faible, le fait de faire glisser la neige mouillée en surface ne constitue pas un risque d'avalanche

Départs spontanés : peu probables en tout début de journée après un regel nocturne plutôt bon, puis de rares départs de taille 1 à 2 (exceptionnellement taille 3) en ubacs d'altitude humidifiés au soleil, parfois jusqu'au sol après un premier départ de surface.

Qualité de la neige

Enneigement déficitaire sur le massif, particulièrement en adrets.
Hauteurs de neige observées : 116 cm dans le vallon du Chardonnet, 81 cm aux Rochilles

Limite d'enneigement skiable : très localement vers 1800 m en terrain favorable, 2300/2400 m en adrets.

État de la neige de surface : neige de type névé en toute orientation sous 2300/2400 m environ et en adrets d'altitude, regel très limité et superficiel, inexistant en forêts. Manteau neigeux pas encore totalement transformé au-dessus en ubacs avec un bon regel nocturne. Poursuite de l'humidification en journée.

Aperçu météo pour le mardi 21 avril

	nuit	matin	après-midi	soir
	Toujours chaud, ensoleillé et sec			
Pluie-Neige				
Iso 0 °C	2 800 m	3 000 m	3 000 m	2 900 m
Vent 2000 m	↘ 15 km/h	↘ 20 km/h	↘ 25 km/h	↘ 15 km/h
Vent 3000 m	↘ 25 km/h	↘ 25 km/h	↘ 30 km/h	↘ 25 km/h

Épaisseur de neige hors-piste

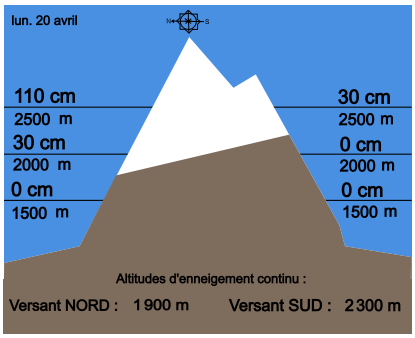

Précipitations à 1800 m

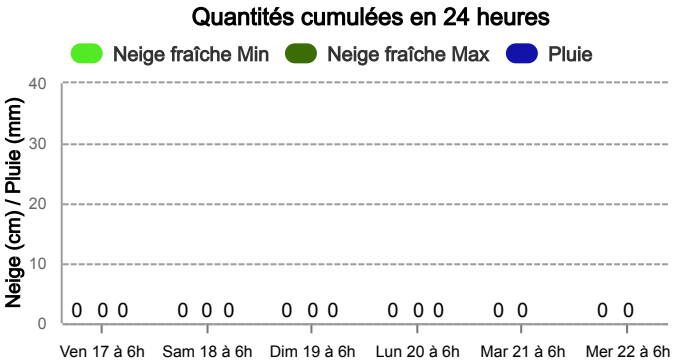

Tendance du mercredi 22 avril

Indice de risque faible

Temps moins chaud, humidification moins prononcée. Risque faible.

Pour consulter la vigilance en cours, veuillez vous rendre sur le site https://vigilance.meteofrance.fr/fr

Météo-France - 73 avenue de Paris, 94165 Saint-Mandé cedex - Contact : contact@meteo.fr

Rédigé par Météo-France avec la contribution des observateurs du réseau nivo-météorologiques. Partenariat : ANMSM (Maires de Stations de Montagne), DSF (Domaines Skiables de France), ADSP (Directeurs de Pistes et de la Sécurité des Stations de Sports d'Hiver) et autres acteurs de la montagne.

Bulletin neige & avalanches par téléphone au **0 892 68 10 20** Service 0,35 € / min + prix appel

RÉPUBLIQUE FRANÇAISE
Liberté Égalité Fraternité

METEO FRANCE
À VOS CÔTÉS, DANS UN CLIMAT QUI CHANGE

Bulletin d'estimation du risque d'avalanche

(valable en dehors des pistes balisées et ouvertes)

MASSIF : Thabor

Rédigé le lundi 20 avril 2026 à 16h

Conditions nivo-météo des 7 derniers jours

	mar. 14/04				mer. 15/04				jeu. 16/04				ven. 17/04				sam. 18/04				dim. 19/04				lun. 20/04			
	03h	09h	15h	21h	03h	09h	15h	21h	03h	09h	15h	21h	03h	09h	15h	21h	03h	09h	15h	21h	03h	09h	15h	21h	03h	09h	15h	21h
Météo																												
Vent (km/h)	15	15	15	15	15	15	15	15	15	15	10	5	5	5	5	10	15	15	15	15	20	25	30	20	25	25	30	25
à 3000m	↙	↙	↙	↙	↖	↙	↘	↓	↓	↓	↘	↖	↑	→	↘	↓	↓	↘	↘	↘	↘	↘	↘	→	→	↘	↘	↘
Vent (km/h)	15	15	15	10	10	15	15	10	10	10	10	5	5	5	10	5	5	5	10	10	15	25	30	15	15	20	30	15
à 2000m	↓	↙	↘	↖	↙	↙	↓	↘	↘	↘	↘	↑	→	↑	↗	↘	↘	↘	↘	↘	↘	↘	↘	↘	→	↘	↘	↘

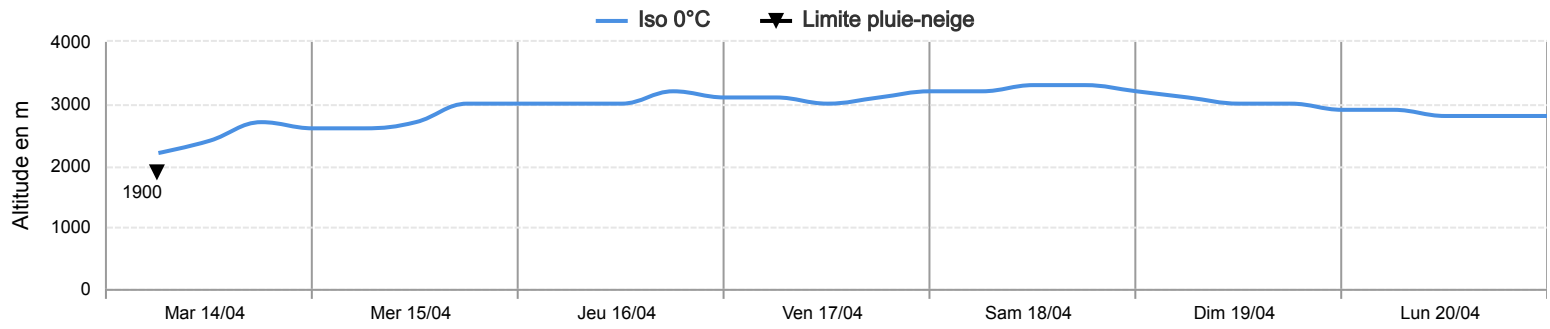

Neige fraîche à 06h

mar. 14/04	mer. 15/04	jeu. 16/04	ven. 17/04	sam. 18/04	dim. 19/04	lun. 20/04
0 cm	0 cm	0 cm	0 cm	0 cm	0 cm	

Risque d'avalanche	mar. 14/04	mer. 15/04	jeu. 16/04	ven. 17/04	sam. 18/04	dim. 19/04	lun. 20/04
	2	2	2	2	2	2	2

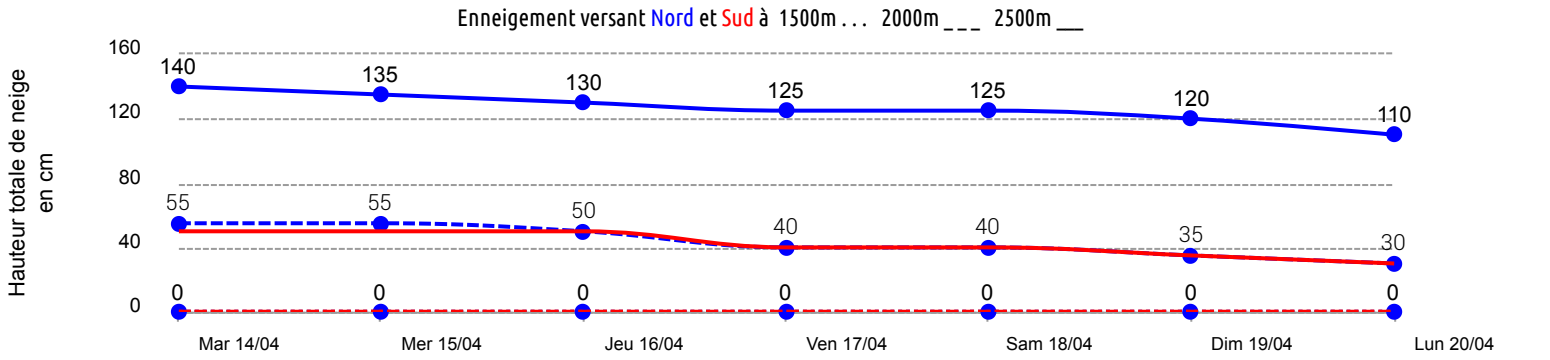

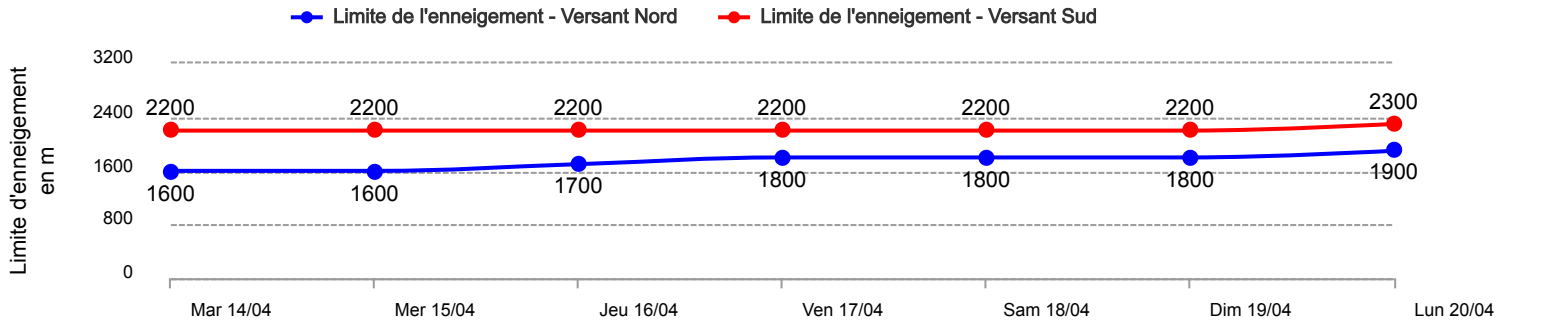

Pour consulter la vigilance en cours, veuillez vous rendre sur le site https://vigilance.meteofrance.fr/fr

Météo-France - 73 avenue de Paris, 94165 Saint-Mandé cedex - Contact : contact@meteo.fr

Rédigé par Météo-France avec la contribution des observateurs du réseau nivo-météorologiques. Partenariat : ANMSM (Maires de Stations de Montagne), DSF (Domaines Skiables de France), ADSP (Directeurs de Pistes et de la Sécurité des Stations de Sports d'Hiver) et autres acteurs de la montagne.

Bulletin neige & avalanches par téléphone au

0 892 68 10 20 Service 0,35 € / min + prix appel