GOBIERNO DE ESPAÑA
VICEPRESIDENCIA TERCERA DEL GOBIERNO
MINISTERIO PARA LA TRANSICIÓN ECOLÓGICA Y EL RETO DEMOGRÁFICO

Boletín de información nivológica y de peligro de aludes

Pirineo Navarro y Aragonés

aemet Agencia Estatal de Meteorología

martes, 21 de abril de 2026

Pronóstico hasta las 24 horas del miércoles, día 22 de abril

(Válido fuera de pistas de esquí balizadas y abiertas)

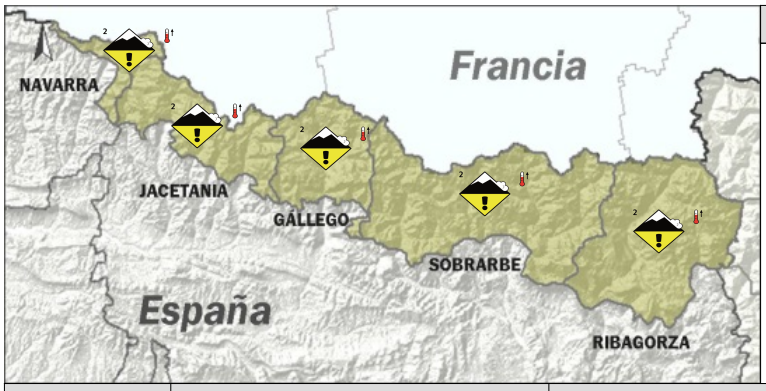

Problemas de aludes

Nieve húmeda

Deslizamientos basales

Macizo	Peligro	Problemas de aludes, cota, orientación, tamaño	Innivación observada (m)
Navarra	2 — 2 — Limitado	Nieve húmeda: 2 — N, E, S, O — 2 Deslizamientos basales: 2 — N, E, S, O — 2	2026-04-21 N / S Cota más baja caras N
Jacetania	2 — 2 — Limitado	Nieve húmeda: 2 — N, E, S, O — 2 Deslizamientos basales: 2 — N, E, S, O — 2	2026-04-21 N / S Cota más baja caras N
Gállego	2 — 2 — Limitado	Nieve húmeda: 2 — N, E, S, O — 2 Deslizamientos basales: 2 — N, E, S, O — 2	2026-04-21 N / S Cota más baja caras N

AEMET. Se autoriza la reproducción de su contenido citando la fuente.

Boletín de información nivológica y de peligro de aludes

Pirineo Navarro y Aragonés

Sobrarbe	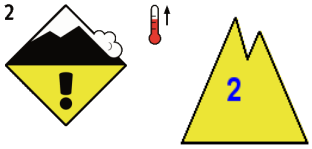 **Limitado**	**Nieve húmeda**  **Deslizamientos basales** 	2026-04-21 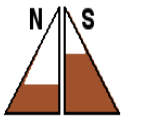 Cota más baja caras N
Ribagorza	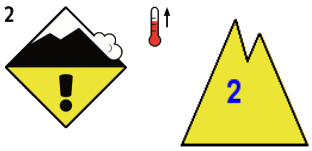 **Limitado**	**Nieve húmeda** **Deslizamientos basales** 	2026-04-21 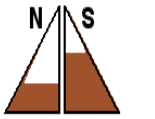 Cota más baja caras N

Estado del manto y observaciones recientes

Ayer por la tarde se registraron precipitaciones en forma de chubascos, a veces acompañados de tormenta, que dejaron acumulados de unos 0.1-5 l/m2 en 24 horas, localmente superiores (19.5 l/m2 en Góriz a 2195 m), y que por lo general fueron menos intensos cuanto más al oeste.
Continúa el proceso de fusión y humidificación del manto como consecuencia de las cada vez más altas temperaturas, la fuerte insolación y los chubascos, registrándose pérdidas diarias de hasta 10-20 cm en la cubierta nivosa.
El manto ha ido retrocediendo a altitudes cada vez más elevadas, más intensamente en las solanas. A pesar de ello, aún podemos encontrar cantidades que superan los 100 cm por encima de 2100 metros en numerosas zonas, aún más en ventisqueros y otras áreas propensas a a la acumulación.
Es típicamente primaveral, con nieve muy humedecida y predominio de grano redondo. El rehielo nocturno es débil, poco efectivo y está restringido a la alta montaña.

Evolución del manto y peligro de aludes para el miércoles, día 22

Problemas de nieve húmeda y deslizamientos basales.

Mañana se espera que continúe el ambiente cálido de días anteriores y con ello el proceso de fusión del manto, así como algunos chubascos que allá donde caigan le aportarán todavía más humedad. Además, el rehielo nocturno estará muy restringido a las cumbres de mayor altitud.
Con todo esto, los problemas de nieve húmeda se presentarán ya desde el comienzo del día, afectando pronto a todas las orientaciones e incrementándose con el transcurso de este. En laderas suficientemente inclinadas, se esperan aludes de tamaño pequeño (peligro de caída) o mediano (capaz de enterrar a una persona), más probables y frecuentes en solanas a partir del mediodía y durante los chubascos, preferentemente en lugares próximos a afloramientos

AEMET. Se autoriza la reproducción de su contenido citando la fuente.

rocosos.
Además, en zonas de manto delgado sobre laderas herbosas o de roca lisa, también podrán suceder deslizamientos basales de tamaño generalmente mediano, sin descartar alguno localmente grande (capaz de enterrar a un grupo de personas).

Predicción meteorológica para el miércoles, día 22

Pirineo navarro:
Intervalos nubosos de nubes altas, medias y algunas de evolución diurna. Por la tarde aumentará la nubosidad baja, que podrá reducir localmente la visibilidad. Se esperan chubascos ocasionales, preferentemente durante la segunda mitad del día. Temperaturas mínimas sin apenas cambios, y máximas en ligero descenso. Viento flojo o moderado del sudoeste, ocasionalmente fuerte en cotas altas y zonas expuestas, y tendiendo a dirección variable en medianías y cotas bajas. Durante los chubascos podrá soplar más intenso y racheado.

Pirineo aragonés:
Intervalos nubosos de nubes altas, medias y algunas de evolución diurna. Por la tarde aumentará la nubosidad baja, que podrá reducir localmente la visibilidad. Se esperan chubascos, preferentemente a partir de las horas centrales y en zonas de la divisoria con Francia. Cota de nieve en torno a 2700-2800 metros. Probables tormentas acompañando a los chubascos. Temperaturas sin cambios o en ligero ascenso, localmente moderado. Alguna helada débil y dispersa en las cumbres de mayor altitud. En cotas altas, viento moderado o fuerte del oeste y sudoeste. En el resto, flojo o moderado de dirección variable, predominando la componente sur al inicio. Durante los chubascos y tormentas podrá soplar más intenso y racheado.

Datos en la atmósfera libre:

Altitud de la isoterma de 0 ºC: 3300 m
Altitud de la isoterma de -10 ºC: 4800 m

Viento a 1500 m: SW 20 km/h
Viento a 3000 m: SW 35 km/h

Evolución para el jueves día 23

Con pocos cambios.

(Información elaborada a partir de los datos recibidos de los refugios de Linza, Lizara, Respomuso, Panticosa, Bachimaña, Góriz, Pineta, Estós, Angel Orús, La Renclusa, Cap de Llauset y Belagua, de la estación de esquí de Panticosa (lagos) y de Ordesa Pradera)

Escala europea de peligro de aludes

Débil | Limitado | Notable | Fuerte | Muy Fuerte

Problemas de aludes

Nieve reciente | Placas de viento | Capas débiles persistentes | Nieve húmeda | Deslizamientos basales | Sin problema evidente

Nota1: Se recuerda que, siempre que haya nieve, la ausencia total de peligro no existe. Hay que tener presente que en circunstancias desfavorables, con aludes de tamaño 1 (alud pequeño o colada) y tamaño 2 (alud mediano), se pueden sufrir severos daños personales.

Nota2: Los BPA se elaboran en base a información meteorológica así como al estado del manto nivoso a través de sondeos puntuales. Se advierte a los usuarios de la variabilidad de esta información al extrapolarla a zonas extensas de montaña. Por ello, AEMET no se hace responsable de su uso para la toma de decisiones que conciernen a la seguridad personal, ni de los riesgos físicos o materiales de ellas derivadas.

AEMET. Se autoriza la reproducción de su contenido citando la fuente.