ICGC Institut Cartogràfic i Geològic de Catalunya

Servei Meteorològic de Catalunya meteo.cat

Boletín de peligro de aludes para el Pirineo de Catalunya
Del 21/04/2026 al 22/04/2026

(Válido fuera pistas de esquí y zonas no controladas)

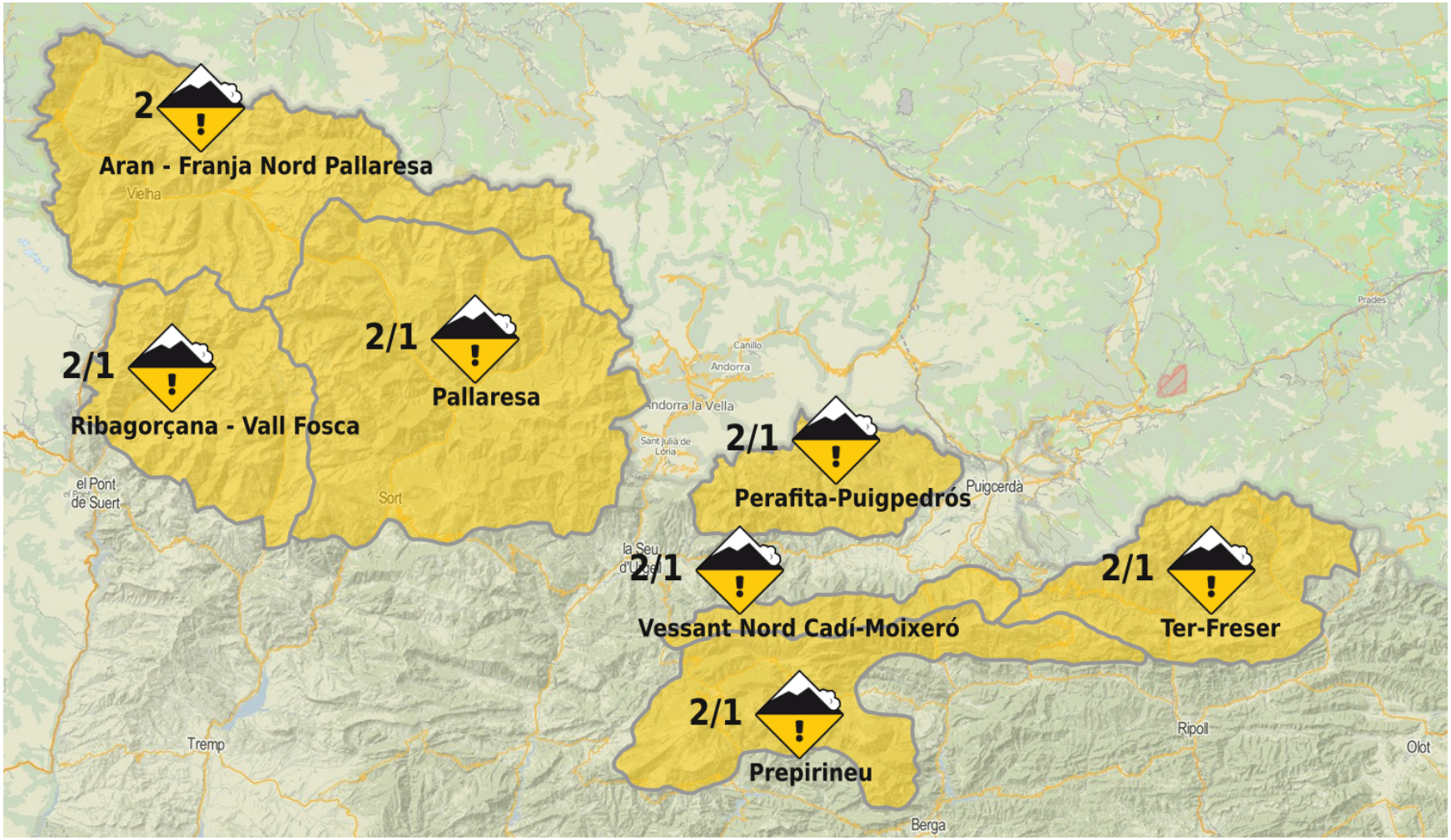

5 MUY FUERTE	4 FUERTE	3 NOTABLE	2 LIMITADO	1 DÉBIL

ICGC Institut Cartogràfic i Geològic de Catalunya

Servei Meteorològic de Catalunya

Boletín de peligro de aludes Aran - Franja Nord Pallaresa Del 21/04/2026 al 22/04/2026

(Válido fuera pistas de esquí y zonas no controladas)

LIMITADO (2).

Situación primaria

Deslizamientos basales **Distribución** **Tamaño** **Origen** **Tendencia**

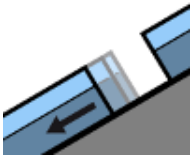

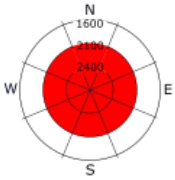

Situación secundaria

Nieve húmeda **Distribución** **Tamaño** **Origen** **Tendencia**

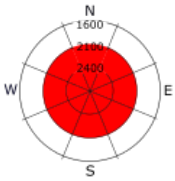

Estado del manto nivoso

Debido a los chubascos de tarde el manto nivoso se encuentra húmedo en su totalidad, con un cierto rehielo de noche y madrugada. Durante estos días se ha observado la caída natural de deslizamientos basales y aludes de fusión. Para este miércoles, y en estas condiciones, se espera que continúe la actividad de deslizamientos basales de hasta tamaño 2 (mediano), suficiente para enterrar a una persona y, localmente, no se descarta que puedan alcanzar también el tamaño 3 (grande), con capacidad de enterrar a un grupo de montañeros. Además, son muy probables las caídas naturales de aludes de fusión, que serán, por lo general, de tamaño 2 (median), con capacidad de cubrir a una persona. Hay que prestar atención a la aparición de grietas para evitar los deslizamientos y evitar sobre todo los momentos de lluvia.

Distribución del manto nivoso

Hay nieve en el suelo con continuidad por encima de 1.800-1.900 m en umbrías y de 2.000 m en solanas. Los espesores a unos 2.300 m rondan los 100-150 cm en el Aran y rondan los 150-180 cm en la Franja Nord de la Pallaresa. Los valores están algo por encima de los normales para la época.

Tendencia para las próximas 48-72h

Se mantendrá la situación de fusión-rehielo con aludes húmedos a partir de mediodía y en momentos de chubascos. Evolución del peligro: ESTACIONARIO.

El próximo boletín será emitido el día 2026-04-22

5 MUY FUERTE	4 FUERTE	3 NOTABLE	2 LIMITADO	1 DÉBIL

EAWS EUROPEAN AVALANCHE WARNING SERVICES

ICGC Institut Cartogràfic i Geològic de Catalunya

Servei Meteorològic de Catalunya

Boletín de peligro de aludes Ribagorçana - Vall Fosca Del 21/04/2026 al 22/04/2026

(Válido fuera pistas de esquí y zonas no controladas)

LIMITADO (2), a partir de media mañana y con chubascos.
DÉBIL (1), de madrugada y a primera hora.

Situación primaria

Deslizamientos basales | **Distribución** | **Tamaño** | **Origen** | **Tendencia**

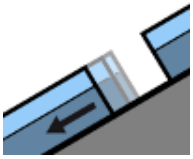

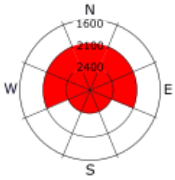

Situación secundaria

Nieve húmeda | **Distribución** | **Tamaño** | **Origen** | **Tendencia**

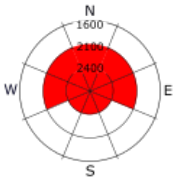

Estado del manto nivoso
El manto va retrocediendo con los chubascos de tarde, la intensa radiación y las temperaturas positivas. Internamente se mantiene húmedo de día y se encostra de noche y madrugada. Los problemas continuarán relacionados con la nieve húmeda, con posibles aludes de nieve húmeda y de deslizamiento basal. Los aludes que puedan caer pueden llegar hasta tamaño 2 (mediano), con capacidad de enterrar a un montañero. Las vertientes más proclives son los terrenos herbosos de fuerte inclinación. Las orientaciones afectadas por deslizamientos y aludes de fusión son todas por encima de 2.100 m en umbrías y por encima de 2.400 m en las solanas. Los tamaños de los aludes de mayor alcance serán en el extremo norte de este sector y por encima de los 2.200 m, donde el grosor movilizable de nieve es mayor. De noche y madrugada el rehielo favorece la estabilidad y el peligro será más débil.

Distribución del manto nivoso
Hay nieve por encima de 1.900 m pero esquiable en N por encima de 2.100 my de los 2.300 m en S, de forma discontinua. Se alcanzan los 70-90 cm a unos 2.200 m, con frecuentes deflaciones y acumulaciones por encima del nivel del bosque. Estos valores están ligeramente por debajo de los normales para la época.

Tendencia para las próximas 48-72h
Se mantendrá la situación de fusión-rehielo con aludes húmedos a partir de mediodía y en momentos de chubascos. Evolución del peligro: ESTACIONARIO.

El próximo boletín será emitido el día 2026-04-22

5 MUY FUERTE	4 FUERTE	3 NOTABLE	2 LIMITADO	1 DÉBIL

EAWS EUROPEAN AVALANCHE WARNING SERVICES

ICGC Institut Cartogràfic i Geològic de Catalunya

Servei Meteorològic de Catalunya

Boletín de peligro de aludes Pallaresa
Del 21/04/2026 al 22/04/2026

(Válido fuera pistas de esquí y zonas no controladas)

LIMITADO (2), a partir de media mañana y con chubascos.
DÉBIL (1), de madrugada y a primera hora.

Situación primaria

Deslizamientos basales | **Distribución** | **Tamaño** | **Origen** | **Tendencia**

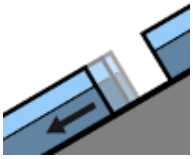

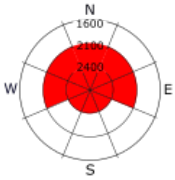

Situación secundaria

Nieve húmeda | **Distribución** | **Tamaño** | **Origen** | **Tendencia**

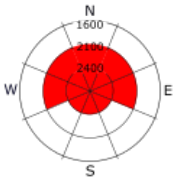

Estado del manto nivoso
El manto va retrocediendo con los chubascos de tarde, la intensa radiación y las temperaturas positivas. Internamente se mantiene húmedo de día y se encostra de noche y madrugada. Los problemas continuarán relacionados con la nieve húmeda, con posibles aludes de nieve húmeda y de deslizamiento basal. Los aludes que puedan caer pueden llegar hasta tamaño 2 (mediano), con capacidad de enterrar a un montañero. Las vertientes más proclives son los terrenos herbosos de fuerte inclinación. Las orientaciones afectadas por deslizamientos y aludes de fusión son todas por encima de 2.100 m en umbrías y por encima de 2.400 m en las solanas. Los tamaños de los aludes de mayor alcance serán en el extremo norte de este sector y por encima de los 2.200 m, donde el grosor movilizable de nieve es mayor. De noche y madrugada el rehielo favorece la estabilidad y el peligro será más débil.

Distribución del manto nivoso
Hay nieve por encima de 1.800-2.000 m en N por encima de 2.100-2.300 m en S. Se alcanzan los 70-90 cm a unos 2.200 m, con frecuentes deflaciones y acumulaciones por encima del nivel del bosque.

Tendencia para las próximas 48-72h
Se mantendrá la situación de fusión-rehielo con aludes húmedos a partir de mediodía y en momentos de chubascos. Evolución del peligro: ESTACIONARIO.

El próximo boletín será emitido el día 2026-04-22

5 MUY FUERTE	4 FUERTE	3 NOTABLE	2 LIMITADO	1 DÉBIL

EAWS EUROPEAN AVALANCHE WARNING SERVICES

ICGC Institut Cartogràfic i Geològic de Catalunya

Servei Meteorològic de Catalunya

Boletín de peligro de aludes Perafita-Puigpedrós Del 21/04/2026 al 22/04/2026

(Válido fuera pistas de esquí y zonas no controladas)

LIMITADO (2), a partir de media mañana y con chubascos.
DÉBIL (1), de madrugada y a primera hora.

Situación primaria

Deslizamientos basales | **Distribución** | **Tamaño** | **Origen** | **Tendencia**

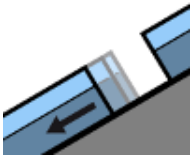

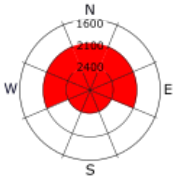

Situación secundaria

Nieve húmeda | **Distribución** | **Tamaño** | **Origen** | **Tendencia**

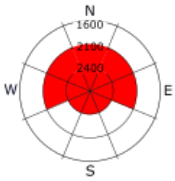

Estado del manto nivoso
Los chubascos de tarde, la intensa radiación y las temperaturas positivas mantendrán un manto húmedo. A primera hora del día aparece un leve encostramiento en umbrías que desaparece rápidamente. Los problemas continuarán relacionados con posibles aludes de nieve húmeda y de deslizamiento basal. Los aludes que puedan caer pueden llegar hasta tamaño 2 (mediano), con capacidad de enterrar a un montañero. Las vertientes más proclives son los terrenos herbosos de fuerte inclinación. Las orientaciones afectadas por deslizamientos y aludes de fusión son todas por encima de 2.100 m en umbrías y por encima de 2.400 m en las solanas. Los tamaños de los aludes de mayor alcance serán en el extremo norte de este sector y por encima de los 2.200 m, donde el grosor movilizable de nieve es mayor. De noche y madrugada el rehielo favorece la estabilidad y el peligro será más débil.

Distribución del manto nivoso
Hay nieve por encima de 1.900-2.000 m en orientaciones N y de 2.200 m en Sur. El grosor total en el suelo oscila entre los 30 y los 70 cm a unos 2.400 m, con frecuentes deflaciones y acumulaciones por encima del nivel del bosque. Estos valores están algo por debajo de los normales para la época.

Tendencia para las próximas 48-72h
Se mantendrá la situación de fusión-rehielo con aludes húmedos a partir de mediodía y en momentos de chubascos. Evolución del peligro: ESTACIONARIO.

El próximo boletín será emitido el día 2026-04-22

5 MUY FUERTE	4 FUERTE	3 NOTABLE	2 LIMITADO	1 DÉBIL

EAWS EUROPEAN AVALANCHE WARNING SERVICES

ICGC Institut Cartogràfic i Geològic de Catalunya

Servei Meteorològic de Catalunya

Boletín de peligro de aludes
Vessant Nord Cadí-Moixeró
Del 21/04/2026 al 22/04/2026

(Válido fuera pistas de esquí y zonas no controladas)

LIMITADO (2), a partir de media mañana y con chubascos.
DÉBIL (1),de madrugada y a primera hora.

Situación primaria

Nieve húmeda

Distribución

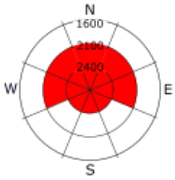

Tamaño

Origen

Tendencia

Estado del manto nivoso
Con los chubascos de estos días el manto se ha humedecido completamente. Las costras internas son todavía algo resistentes y esto hace que el manto se mantenga un poco duro al circular por encima. Para el miércoles se esperan caídas naturales de aludes de fusión, sobre todo en momentos de chubascos en cualquier orientación y alcanzarán mayor alcance por encima de los 2.200 m, donde hay mayor grosor de manto movilizable. En caso de que se desencadenen pueden alcanzar tamaño 2 (mediano), suficiente para enterrar un montañero. Los sectores más peligrosos son los canales donde los grosores acumulados son mayores. Habrá que evitar los momentos de chubascos y las horas de mayor humedecimiento. Con el descenso térmico nocturno se prevé un leve encostramiento que puede favorecer la estabilización del manto de noche, madrugada y a primera hora del día.

Distribución del manto nivoso
Hay nieve por encima de 1.900 m en N y de 2.100 m en S. Se alcanzan los 100-130 cm a unos 2.200 m, con frecuentes deflaciones y acumulaciones por encima del nivel del bosque. Estos valores están por encima de los normales para la época.

Tendencia para las próximas 48-72h
Se mantendrá la situación de fusión-rehielo con aludes húmedos a partir de mediodía y en momentos de chubascos. Evolución del peligro: ESTACIONARIO.

El próximo boletín será emitido el día 2026-04-22

5 MUY FUERTE	4 FUERTE	3 NOTABLE	2 LIMITADO	1 DÉBIL

EAWS EUROPEAN AVALANCHE WARNING SERVICES

ICGC Institut Cartogràfic i Geològic de Catalunya

Servei Meteorològic de Catalunya

Boletín de peligro de aludes Prepirineu
Del 21/04/2026 al 22/04/2026

(Válido fuera pistas de esquí y zonas no controladas)

LIMITADO (2), a partir de media mañana y con chubascos.
DÉBIL (1), de madrugada y a primera hora.

Situación primaria

Nieve húmeda

Distribución

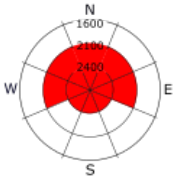

Tamaño

Origen

Tendencia

Estado del manto nivoso
Debido a los chubascos de tarde de estos días las costras presentes en el manto se han ablandado y el humedecimiento ha progresado internamente. Con estas condiciones, para este miércoles se esperan caídas naturales de aludes de fusión, sobre todo en momentos de chubascos en cualquier orientación y alcanzarán mayor alcance por encima de los 2.200 m, donde hay mayor grosor de manto movilizable. Los aludes pueden alcanzar tamaño 2 (mediano), suficiente para enterrar a un montañero. Los sectores más peligrosos es el terreno trampa, como las depresiones, donde los grosores acumulados en caso de alud pueden ser mayores. Habrá que evitar los momentos de chubascos y las horas de mayor humedecimiento. Con el descenso térmico nocturno se prevé un peligro más débil debido al leve encostramiento que puede favorecer la estabilización del manto de noche y madrugada.

Distribución del manto nivoso
Hay nieve por encima de 1.900 m en N y de 2.100-2.200 m en S. Se alcanzan los 50-70 cm a unos 2.200 m, con frecuentes deflaciones y acumulaciones por encima del nivel del bosque.

Tendencia para las próximas 48-72h
Se mantendrá la situación de fusión-rehielo con aludes húmedos a partir de mediodía y en momentos de chubascos. Evolución del peligro: ESTACIONARIO.

El próximo boletín será emitido el día 2026-04-22

5 MUY FUERTE	4 FUERTE	3 NOTABLE	2 LIMITADO	1 DÉBIL

EAWS EUROPEAN AVALANCHE WARNING SERVICES

ICGC Institut Cartogràfic i Geològic de Catalunya

Servei Meteorològic de Catalunya meteo.cat

Boletín de peligro de aludes Ter-Freser
Del 21/04/2026 al 22/04/2026

(Válido fuera pistas de esquí y zonas no controladas)

LIMITADO (2), a partir de media mañana y con chubascos.
DÉBIL (1), de madrugada y a primera hora.

Situación primaria

Deslizamientos basales | **Distribución** | **Tamaño** | **Origen** | **Tendencia**

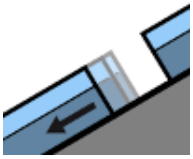

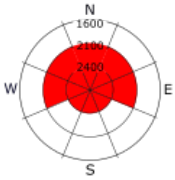

Situación secundaria

Nieve húmeda | **Distribución** | **Tamaño** | **Origen** | **Tendencia**

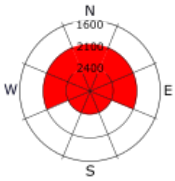

Estado del manto nivoso
Debido a los chubascos de estos días el manto se presenta húmedo en su totalidad y las costras internas están bastante degradadas. El rehielo matinal es muy leve y sólo presente a primeras horas de la mañana y en la madrugada. Para el miércoles, son probables caídas de deslizamientos basales y aludes de fusión de forma natural. Tanto los deslizamientos basales como los aludes de nieve húmeda pueden tener tamaño medio, con capacidad para enterrar a un montañero. Las vertientes más proclives son las vertientes de suelo herboso con fuerte inclinación. Las orientaciones afectadas por deslizamientos y por fusión son todas a partir de 2.100 m y los tamaños de los aludes serán de mayor alcance por encima de los 2.200 m donde el grosor movilizable de nieve es mayor. De noche y madrugada el leve rehielo hará que el peligro sea más débil y aumentará a partir de media mañana y en momentos de chubascos.

Distribución del manto nivoso
Hay nieve por encima de 1.900 m en N y de 2.100 - 2.200 m en S. Los espesores rondan los 40-70 cm a unos 2.200 m, y más de 130-190 cm por encima de 2.400 m, con frecuentes deflaciones y acumulaciones por . Estos valores están por encima de la media.

Tendencia para las próximas 48-72h
Se mantendrá la situación de fusión-rehielo con aludes húmedos a partir de mediodía y en momentos de chubascos. Evolución del peligro: ESTACIONARIO.

El próximo boletín será emitido el día 2026-04-22

5 MUY FUERTE	4 FUERTE	3 NOTABLE	2 LIMITADO	1 DÉBIL

EAWS EUROPEAN AVALANCHE WARNING SERVICES