BUTLLETÍ DEL PERILL D'ALLAUS DEL PRINCIPAT D'ANDORRA

Préparé le 21/04/2026 16:00
Prochaine mise à jour le 22/04/2026 à 16h

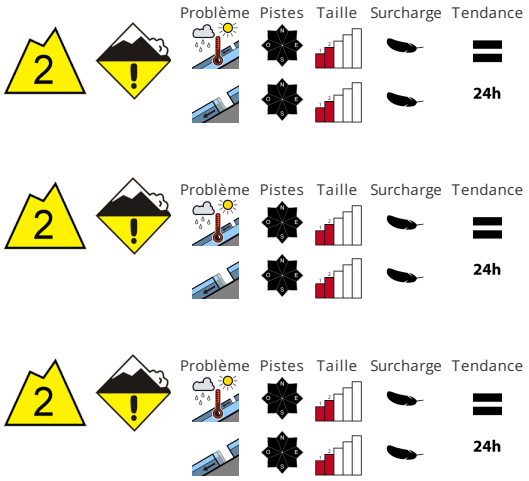

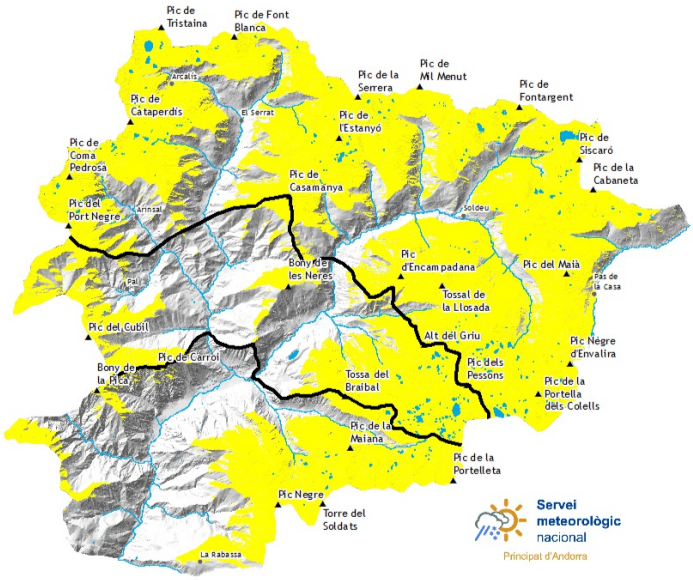

STABILITÉ DU MANTEAU NEIGEUX

Le matin il fait doux. À partir de midi il tombera de la pluie jusqu'à haute altitude. Des avalanches humides et mouillées de moyenne et rarement grande taille sont ils sont possibles avec l'humidification. En outre, des avalanches de glissement sont à attendre.. À toutes les expositions le danger d'avalanches mouillées et de glissement augmente au sein du degré de danger en cours de journée au grade 1 (faible).

QUALITÈ DE LA NEIGE

Le rayonnement nocturne est généralement réduit.. Les conditions météorologiques entraînent le matin une humidification croissante du manteau neigeux. La pluie entraîne à partir de midi partiellement une perte de solidité au sein du manteau neigeux. Les zones présentant des fissures de glissement doivent être évitées.. Les randonnées devraient être commencées et terminées tôt..

EPAISSEUR DE NEIGE HORS PISTE

Zone nord		Epaisseur de neige		
Nival manteau		1500m	2000m	2500m
N	1800 m	0 cm	150 cm	250 cm
S	2200 m	0 cm	0 cm	180 cm

Zone centre		Epaisseur de neige		
Nival manteau		1500m	2000m	2500m
N	1800 m	0 cm	120 cm	160 cm
S	2200 m	0 cm	0 cm	120 cm

Zone sud		Epaisseur de neige		
Nival manteau		1500m	2000m	2500m
N	1800 m	0 cm	120 cm	160 cm
S	2200 m	0 cm	0 cm	120 cm

Govern d'Andorra

Aquest butlletí ha estat elaborat seguint les normes i recomanacions de l'**European Avalanche Warning Services**, del qual el **Servei meteorològic Nacional** n'és membre

BUTLLETÍ DEL PERILL D'ALLAUS DEL PRINCIPAT D'ANDORRA

Servei meteorològic nacional
Principat d'Andorra

Des informations détaillées par espace naturel protégé

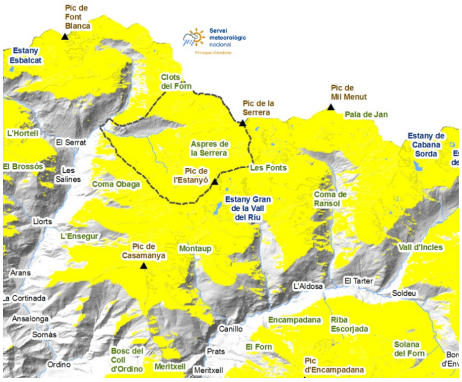

SORTENY

Les faibles gelées des dernières nuits et les pluies des après-midis ont laissé un manteau neigeux plus précaire que les jours précédents. La glace n'est pas aussi bonne ni efficace, il est donc plus difficile de circuler dans la neige qui n'a pas été compactée tout au long de la saison. , , ,

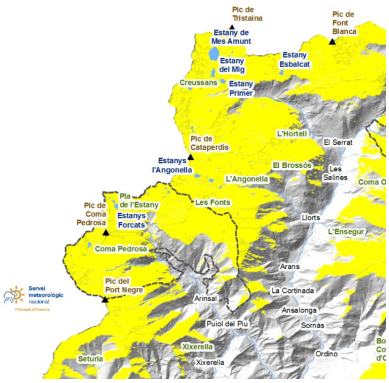

COMAPEDROSA

La neige est plus humide que les jours précédents. Faites attention aux ponts de glace au-dessus des torrents, car ils seront fragilisés par l'augmentation des températures et l'augmentation du débit des rivières. , , ,

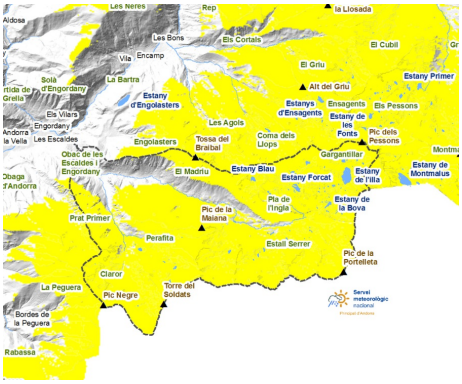

MADRIU-PERAFITA-CLAROR

La pénétration de l'humidité favorisera un cycle d'avalanches naturelles de neige mouillée et de glissements basaux. Depuis l'Estall Serrer en aval, il ne reste plus de neige continue. , , ,

Govern d'Andorra

EAWS
EUROPEAN AVALANCHE WARNING SERVICES

Aquest butlletí ha estat elaborat seguint les normes i recomanacions de l'**European Avalanche Warning Services**, del qual el **Servei meteorològic Nacional** n'és membre

BUTLLETÍ DEL PERILL D'ALLAUS DEL PRINCIPAT D'ANDORRA

Servei meteorològic nacional
Principat d'Andorra

Couche de neige fraiche des derniers jours (De 24 h mesurée à 06:00 h UTC)

	17/04/2026	18/04/2026	19/04/2026	20/04/2026
FEDA (Central)	0 cm	0 cm	0 cm	0 cm
Engolasters - FEDA	0 cm	0 cm	0 cm	0 cm
Bony de les Neres	0 cm	0 cm	0 cm	0 cm
Sorteny	0 cm	0 cm	0 cm	0 cm
Les Fonts d'Arinsal	0 cm	0 cm	0 cm	0 cm
Aixàs	0 cm	0 cm	0 cm	0 cm
Perafita	0 cm	0 cm	0 cm	0 cm
Tossa Espiolets	0 cm	0 cm	0 cm	0 cm
Grau Roig - FEDA	0 cm	0 cm	0 cm	0 cm
Fontverd	0 cm	0 cm	0 cm	0 cm
Coll Ordino	0 cm	0 cm	0 cm	0 cm
Ransol - FEDA	0 cm	0 cm	0 cm	0 cm
Setúria	0 cm	0 cm	0 cm	0 cm
Caborreu	0 cm	0 cm	0 cm	0 cm
La Solana	0 cm	0 cm	0 cm	0 cm
Coll Pa	0 cm	0 cm	0 cm	0 cm
Envalira Antenes	0 cm	0 cm	0 cm	0 cm
Vall del Riu FEDA	0 cm	0 cm	0 cm	0 cm