Bulletin d'estimation du risque d'avalanche
(valable en dehors des pistes balisées et ouvertes)

MASSIF : Beaufortain

Rédigé le mardi 21 avril 2026 à 16h

Estimation des risques pour le : MERCREDI 22 AVRIL

CONDITIONS DE PRINTEMPS AVANCÉES

2

1 → 2

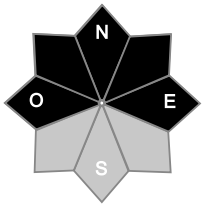

Indice de risque faible évoluant en limité.

Départs spontanés : rares départs en neige humide

Déclenchements provoqués : peu probables sauf neige humide sous les skis.

Indices de risque : 5 très fort - 4 fort - 3 marqué - 2 limité - 1 faible -- En noir : les pentes les plus dangereuses

Stabilité du manteau neigeux

Situation avalancheuse typique : neige humide

Départs spontanés :
- **Rares avalanches de neige humide** dans les **pentes ensoleillées** au fil de la journée. Ce sont généralement des départs ponctuels (poires), donnant de **petites à moyennes avalanches**. Avec l'avancée dans la saison, les pentes Sud deviennent relativement inertes avec une neige transformée sur toute l'épaisseur du manteau (type névé). Par contre, dans les versants Est, Nord et Ouest, l'humidification gagne des couches plus profondes. Ainsi, si une couche fragile est atteinte, **un départ linéaire est possible**. On peut alors s'attendre, très exceptionnellement, à une taille 3 (grande).

Déclenchements provoqués : peu probables sauf avalanche de neige humide (pourrie) sous les skis en coupant une pente trop humidifiée.

Qualité de la neige

Enneigement : à peine correct pour la saison, la montagne subit les assauts répétés de la chaleur excessive et la neige fond à vue d'œil.

Limite skiable : vers 1400 m en Nord, 1700/1800 m en Sud en pente douce, bien plus haut en pente sud raide.

Qualité de la neige : neige de printemps après un très bon regel nocturne. Neige dure aux premières heures du jour puis moquette aux bonnes heures (milieu de matinée à la mi journée suivant orientations et altitude). Comme les jours précédents, les pentes Est chauffent très vite le matin. Neige pourrie à partir de l'après midi.

Aperçu météo pour le mercredi 22 avril

	nuit	matin	après-midi	soir
Ciel clair à voilé. Chaud.				
Pluie-Neige				
Iso 0 °C	2 500 m	2 700 m	2 600 m	2 500 m
Vent 2000 m	10 km/h	15 km/h	10 km/h	15 km/h
Vent 3000 m	25 km/h	25 km/h	15 km/h	10 km/h

Épaisseur de neige hors-piste

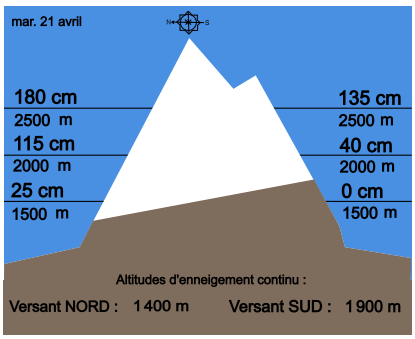

Précipitations à 1800 m

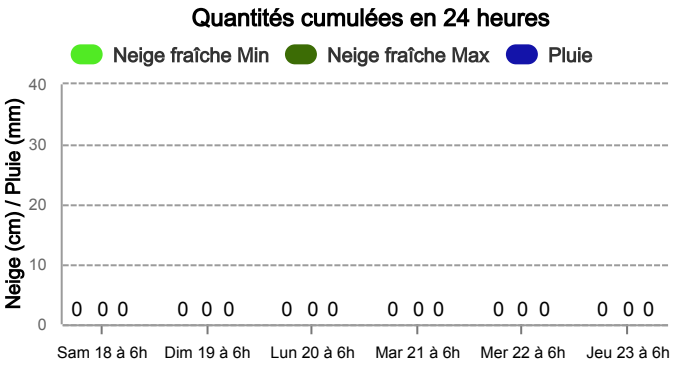

Tendance du jeudi 23 avril

2

Indice de risque limité

Poursuite de conditions printanières : à nouveau, risque faible évoluant en risque limité en journée.

Pour consulter la vigilance en cours, veuillez vous rendre sur le site https://vigilance.meteofrance.fr/fr

Météo-France - 73 avenue de Paris, 94165 Saint-Mandé cedex - Contact : contact@meteo.fr

Rédigé par Météo-France avec la contribution des observateurs du réseau nivo-météorologiques. Partenariat : ANMSM (Maires de Stations de Montagne), DSF (Domaines Skiables de France), ADSP (Directeurs de Pistes et de la Sécurité des Stations de Sports d'Hiver) et autres acteurs de la montagne.

Bulletin neige & avalanches par téléphone au 0 892 68 10 20 Service 0,35 € / min + prix appel

Bulletin d'estimation du risque d'avalanche

(valable en dehors des pistes balisées et ouvertes)

MASSIF : Beaufortain

Rédigé le mardi 21 avril 2026 à 16h

Conditions nivo-météo des 7 derniers jours

	mer. 15/04				jeu. 16/04				ven. 17/04				sam. 18/04				dim. 19/04				lun. 20/04				mar. 21/04			
	03h	09h	15h	21h	03h	09h	15h	21h	03h	09h	15h	21h	03h	09h	15h	21h	03h	09h	15h	21h	03h	09h	15h	21h	03h	09h	15h	21h
Météo																												
Vent (km/h)	10	10	15	10	15	15	15	15	10	10	15	15	20	15	15	15	20	20	20	20	30	25	25	25	25	15	15	20
à 3000m	↓	↘	↘	↘	↓	↓	↘	↗	↗	↗	→	→	↓	↓	↘	→	→	→	→	→	→	→	→	→	→	↘	↘	↘
Vent (km/h)	5	10	15	5	5	10	10	10	5	5	10	10	15	10	10	10	10	15	15	10	10	15	10	10	10	10	10	10
à 2000m	↓	↘	↘	↘	↘	↘	↘	↗	↗	↗	↗	↗	↘	↘	↘	→	↘	→	↘	→	↘	↗	↘	↖	↘	↑	→	↘

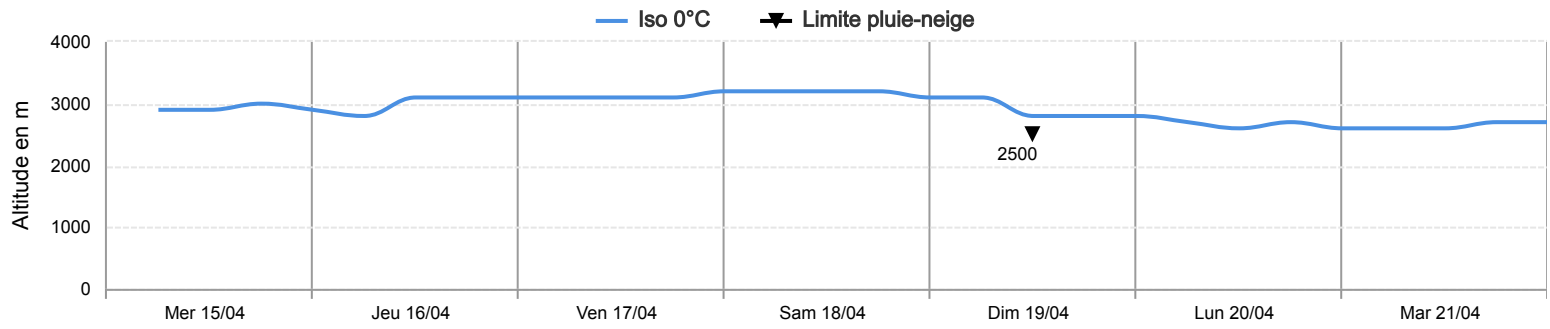

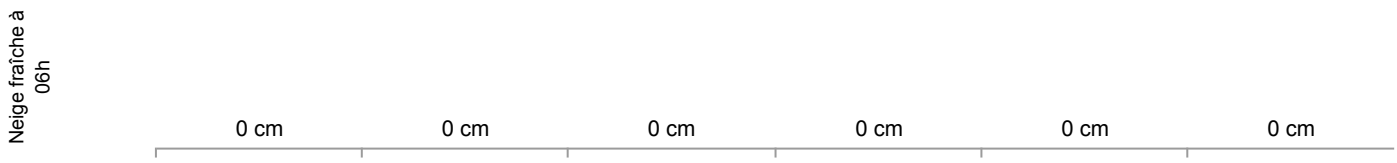

Risque d'avalanche	mer. 15/04	jeu. 16/04	ven. 17/04	sam. 18/04	dim. 19/04	lun. 20/04	mar. 21/04
	2	2	2	2	2	2	2

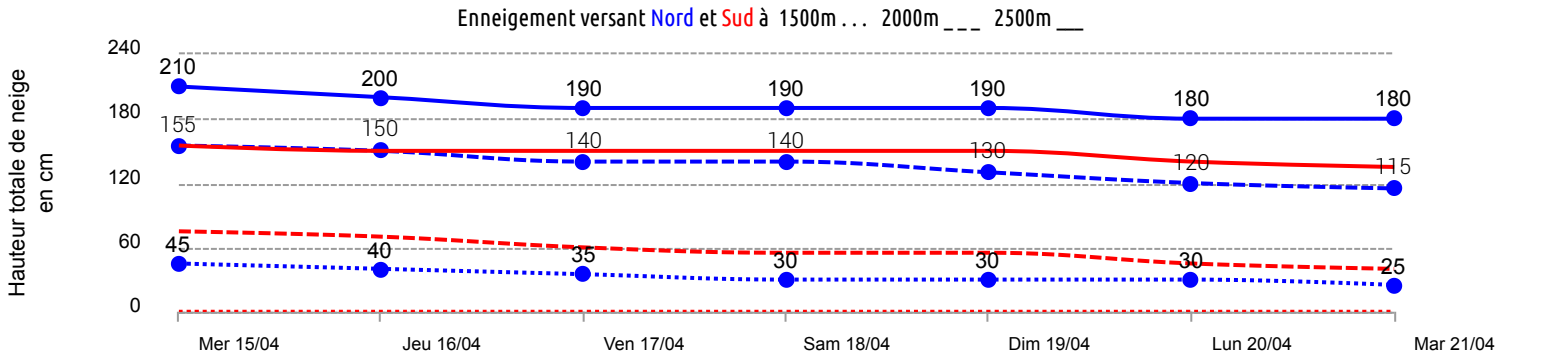

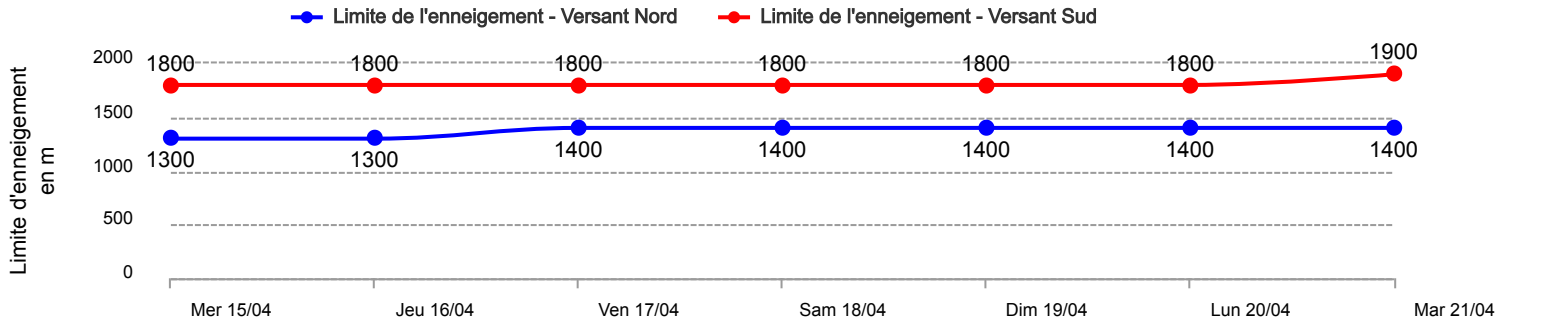

Pour consulter la vigilance en cours, veuillez vous rendre sur le site https://vigilance.meteofrance.fr/fr

Météo-France - 73 avenue de Paris, 94165 Saint-Mandé cedex - Contact : contact@meteo.fr

Rédigé par Météo-France avec la contribution des observateurs du réseau nivo-météorologiques. Partenariat : ANMSM (Maires de Stations de Montagne), DSF (Domaines Skiables de France), ADSP (Directeurs de Pistes et de la Sécurité des Stations de Sports d'Hiver) et autres acteurs de la montagne.

Bulletin neige & avalanches par téléphone au

0 892 68 10 20 Service 0,35 € / min + prix appel