Bulletin d'estimation du risque d'avalanche
(valable en dehors des pistes balisées et ouvertes)

MASSIF : Belledonne

Rédigé le mardi 21 avril 2026 à 16h

Estimation des risques pour le : MERCREDI 22 AVRIL

MANTEAU NEIGEUX PRINTANIER, BON REGEL NOCTURNE, HUMIDIFICATION PARFOIS LENTE SOUS LE VOILE NUAGEUX

2

1 → 2

N O E S

Indice de risque faible évoluant en limité.

Départs spontanés : Rares coulées humides ou départs au terrain. Une cassure linéaire ne peut être totalement exclue en Nord.

Déclenchements provoqués : Peu probables, ou juste une coulée ponctuelle sous les skis en neige très humide ?

Indices de risque : 5 très fort - 4 fort - 3 marqué - 2 limité - 1 faible -- En noir : les pentes les plus dangereuses

Stabilité du manteau neigeux

Situation avalancheuse typique : neige humide — avalanches de fond

Départs spontanés : Rares avalanches humides aux heures chaudes de la journée. En large Nord, l'humidification gagne en profondeur et pourrait atteindre une couche fragile persistante, dans quel cas une avalanche de grande taille serait possible, avec une cassure linéaire. Le risque semble toutefois plus faible que les jours précédents, notamment sur le Sud du massif où le voile nuageux sera le plus dense et limitera fortement l'humidification en journée.
Très localement, une avalanche de fond reste possible en pente herbeuse / dalle rocheuse, parfois précédée par l'ouverture d'une fissure (gueule de baleine).

Déclenchements provoqués : Pas de risque de plaque. Manteau neigeux dense et bien stabilisé. En terrain raide et bien humidifié, risque limité de coulée ponctuelle sous les skis.

Autres : Neige parfois durcie / croûtée par le regel.

Qualité de la neige

Qualification de l'enneigement : L'enneigement s'est bien réduit depuis 3 semaines, et devient progressivement déficitaire en Sud et en moyenne montagne. Il reste de saison dans les versants peu ensoleillés au-dessus de 2000m.

Limites skiables : Vers 1400/1600m en Nord à 1800/2200m suivant l'exposition au soleil, la raideur de la pente...

Qualité de la neige mercredi : Regel nocturne correct à très bon en altitude. Neige croûtée / durcie par le regel. En journée, l'humidification est bien plus lente que les jours précédents avec l'arrivée d'un voile nuageux dense, notamment sur le Sud du massif. En Nord Belledonne, humidification plus marquée en journée sous des nuages moins épais.

Aperçu météo pour le mercredi 22 avril

	nuit	matin	après-midi	soir

Après une nuit claire, le ciel devient voilé en journée, voire couvert sur le Sud du massif. Retour d'un ciel plus dégagé pour la nuit suivante.

Pluie-Neige				
Iso 0 °C	2 800 m	2 800 m	2 700 m	2 700 m
Vent 2000 m	↗ 10 km/h	↗ 15 km/h	↘ 20 km/h	↖ 10 km/h
Vent 3000 m	→ 35 km/h	→ 35 km/h	↘ 25 km/h	↘ 15 km/h

Épaisseur de neige hors-piste

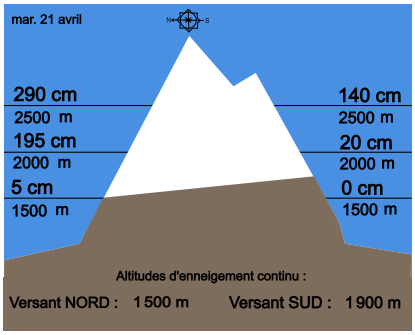

Précipitations à 1800 m

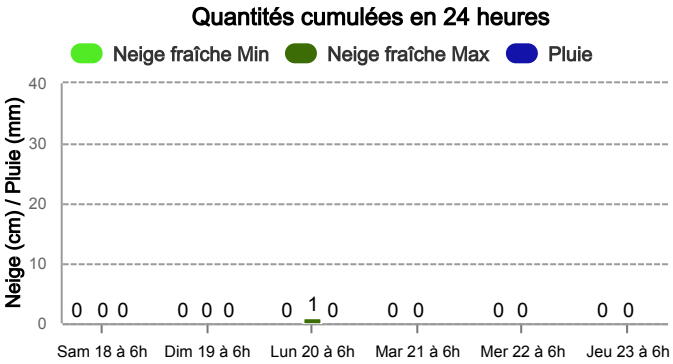

Tendance du jeudi 23 avril

2

Indice de risque limité

Bon regel nocturne dans la nuit de mercredi à jeudi. En journée, humidification rapide au soleil. Quelques cumulus bourgeonnent l'après-midi, accrochant parfois les sommets.

Pour consulter la vigilance en cours, veuillez vous rendre sur le site https://vigilance.meteofrance.fr/fr

Météo-France - 73 avenue de Paris, 94165 Saint-Mandé cedex - Contact : contact@meteo.fr

Rédigé par Météo-France avec la contribution des observateurs du réseau nivo-météorologiques. Partenariat : ANMSM (Maires de Stations de Montagne), DSF (Domaines Skiables de France), ADSP (Directeurs de Pistes et de la Sécurité des Stations de Sports d'Hiver) et autres acteurs de la montagne.

Bulletin neige & avalanches par téléphone au 0 892 68 10 20 Service 0,35 € / min + prix appel

RÉPUBLIQUE FRANÇAISE
Liberté Égalité Fraternité

METEO FRANCE
À VOS CÔTÉS, DANS UN CLIMAT QUI CHANGE

Bulletin d'estimation du risque d'avalanche

(valable en dehors des pistes balisées et ouvertes)

MASSIF : Belledonne

Rédigé le mardi 21 avril 2026 à 16h

Conditions nivo-météo des 7 derniers jours

	mer. 15/04				jeu. 16/04				ven. 17/04				sam. 18/04				dim. 19/04				lun. 20/04				mar. 21/04			
	03h	09h	15h	21h	03h	09h	15h	21h	03h	09h	15h	21h	03h	09h	15h	21h	03h	09h	15h	21h	03h	09h	15h	21h	03h	09h	15h	21h
Météo																												
Vent (km/h)	15	10	10	10	15	10	5	10	5	10	10	5	15	15	10	15	20	20	25	30	25	25	25	30	35	30	30	25
à 3000m																												
Vent (km/h)	10	5	5	15	15	10	5	5	5	5	0	5	10	5	5	5	10	15	20	20	10	15	20	15	10	10	20	10
à 2000m																												

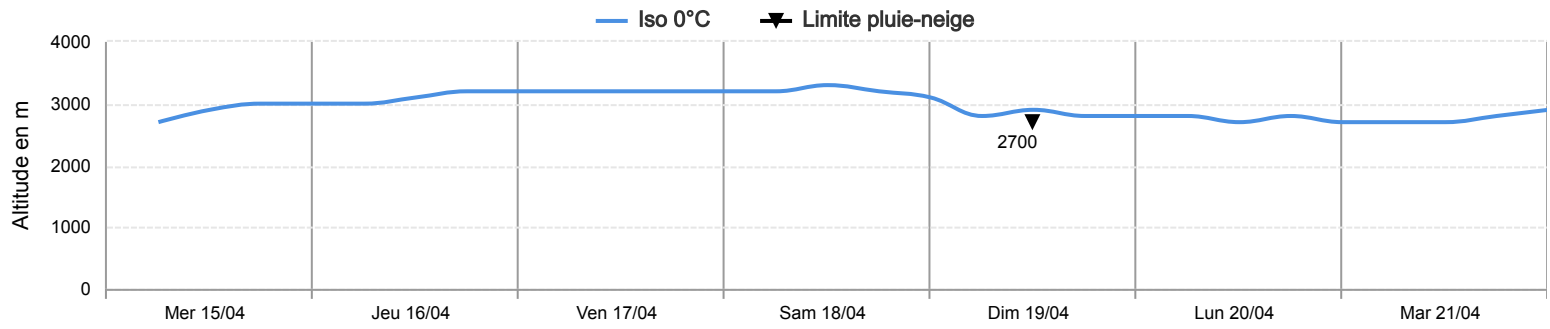

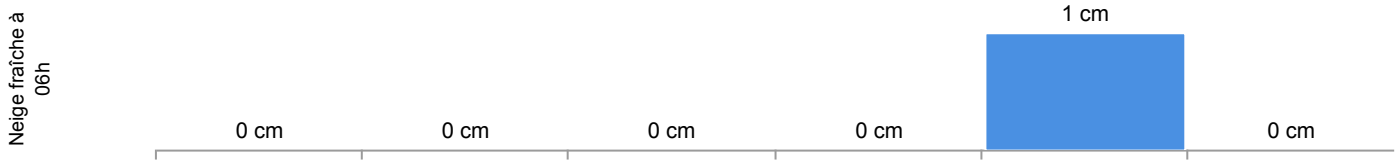

Risque d'avalanche	mer. 15/04	jeu. 16/04	ven. 17/04	sam. 18/04	dim. 19/04	lun. 20/04	mar. 21/04
	2	2	2	2	2	2	2

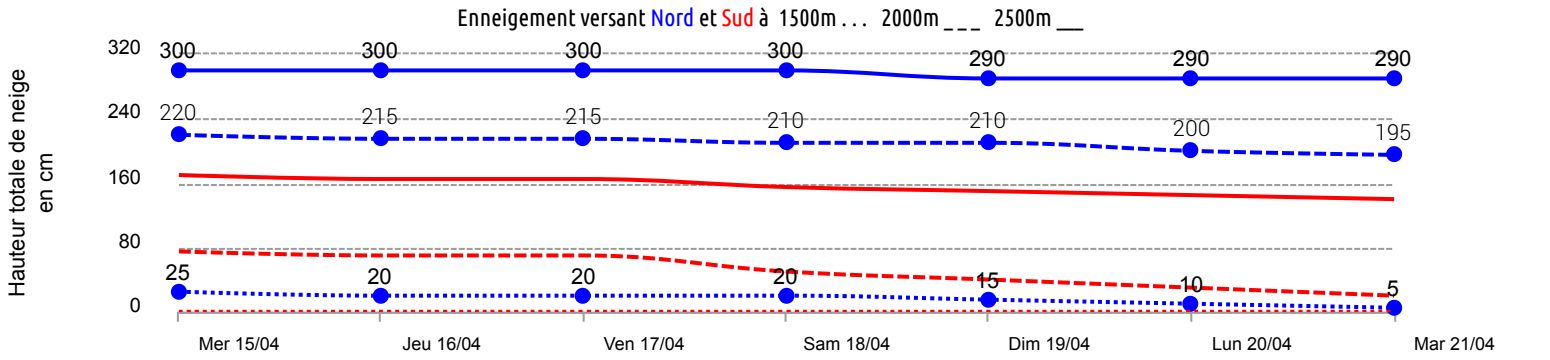

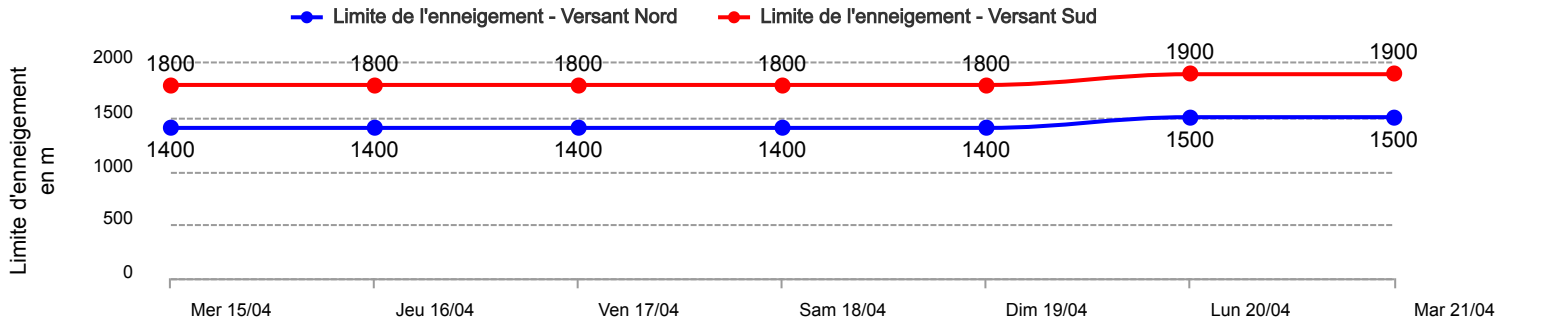

Pour consulter la vigilance en cours, veuillez vous rendre sur le site https://vigilance.meteofrance.fr/fr

Météo-France - 73 avenue de Paris, 94165 Saint-Mandé cedex - Contact : contact@meteo.fr

Rédigé par Météo-France avec la contribution des observateurs du réseau nivo-météorologiques. Partenariat : ANMSM (Maires de Stations de Montagne), DSF (Domaines Skiables de France), ADSP (Directeurs de Pistes et de la Sécurité des Stations de Sports d'Hiver) et autres acteurs de la montagne.

Bulletin neige & avalanches par téléphone au
0 892 68 10 20
Service 0,35 € / min + prix appel