RÉPUBLIQUE FRANÇAISE
Liberté Égalité Fraternité

METEO FRANCE
À VOS CÔTÉS, DANS UN CLIMAT QUI CHANGE

Bulletin d'estimation du risque d'avalanche
(valable en dehors des pistes balisées et ouvertes)
MASSIF : Capcir Puymorens

Rédigé le mardi 21 avril 2026 à 16h

Estimation des risques pour le : MERCREDI 22 AVRIL

POURSUITE DE L'HUMIDIFICATION, AVALANCHES DE FOND EN JOURNÉE.

3

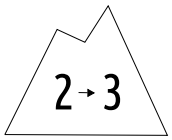

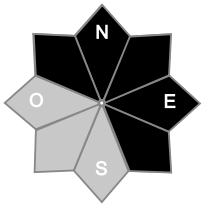

Pentes Est à Nord

Indice de risque limité évoluant en marqué.

Départs spontanés : Avalanches de surface et avalanches de fond en neige humide

Déclenchements provoqués : Départs ponctuels en neige humide favorisés par le passage d'un randonneur

Indices de risque : 5 très fort - 4 fort - 3 marqué - 2 limité - 1 faible -- En noir : les pentes les plus dangereuses

Stabilité du manteau neigeux

Situation avalancheuse typique : avalanches de fond neige humide

Départs spontanés :
- En altitude, avec l'humidification qui gagne en profondeur, des **avalanches de glissement** emportant l'ensemble du manteau neigeux sont possibles en toutes orientations (fissures/reptations et avalanches de glissement signalées ces derniers jours). Elles seront de taille moyenne à grande, voire plus rarement très grandes dans les zones de plus fortes accumulations (pentes nord à sud-est). Les déclenchements sont rares en matinée et deviennent plus nombreux l'après-midi pouvant être initiés par la rupture de corniches sommitales ou après une averse orageuse. avec des cassures pouvant largement dépasser 1 à 2m d'épaisseur, ces avalanches peuvent parcourir de grands dénivelés, finissant leur course parfois beaucoup plus bas que la limite d'enneigement. Il convient donc de se méfier des sentiers traversant des couloirs à avalanche. La présence d'un dépôt plus ou moins ancien n'est pas forcément un gage de sécurité dans le cas ou la pente n'ait pas été totalement purgée.
- Quelques départs départs ponctuels d'**avalanches en neige humide** de taille petite en haute montagne mobilisant les quelques centimètres de neige récente tombés sous les averses. Avec la douceur et sous les nuages de l'après-midi, des départs un peu plus volumineux demeurent possibles en pentes raides pouvant déclencher une avalanche de fond par effet de surcharge.

Déclenchements provoqués :
- Un skieur coupant une pente raide déjà bien humidifiée pourra favoriser un départ ponctuel de taille petite à plus rarement moyenne. Ces coulées peuvent emporter les skis et provoquer la chute. Les pentes orientées Est le matin puis Ouest en fin de journée (en passant par le Sud) sont les plus exposées à ce risque.

Autre : Des corniches encore imposantes sont en place et sont susceptibles de céder spontanément avec l'humidification, tout comme les ponts de neige sur les torrents bien alimentés par la fonte en cours.

Qualité de la neige

Enneigement :
L'enneigement dans nos massifs reste bon pour la saison, encore largement supérieur à celui des derniers hivers. Avec la douceur ambiante, le manteau perd une petite dizaine de cm par jour en deçà de 2000/2100 m, et la limite skiable remonte progressivement surtout en sud. Elle est encore au mieux vers 1700 m en nord et 2000 à 2100 m en sud. On trouve ensuite rapidement une bonne épaisseur de neige qui dépasse souvent les 1m 50 dès 2000 m en nord, et les 2m50 dès 2500m.

Qualité de la neige :
Au petit matin, les pentes au-delà de 2300/2400 m devraient connaitre un regel en surface à la faveur des éclaircies de seconde partie de nuit. Ce dernier est plus aléatoire en dessous. L'humidification reprend rapidement en matinée, et se poursuit l'après-midi avec les nouvelles averses prévues. La surface du manteau est souvent constituée de neige ocre, chargée en poussières sahariennes. L'après-midi, elle est lourde, souvent non portante pour les piétons. Les cols et crêtes ouest à nord-ouest sont généralement moins garnis en neige voire pelés.

Aperçu météo pour le mercredi 22 avril

	nuit	matin	après-midi	soir

Beau le matin, instable l'après-midi toujours dans la douceur.

Pluie-Neige	2 700 m	2 700 m	2 900 m	2 900 m
Iso 0 °C	3 500 m	3 400 m	3 300 m	3 300 m
Vent 2000 m	→ 25 km/h	→ 20 km/h	→ 30 km/h	↓ 10 km/h
Vent 3000 m	→ 30 km/h	→ 25 km/h	↗ 30 km/h	↗ 15 km/h

Pour consulter la vigilance en cours, veuillez vous rendre sur le site https://vigilance.meteofrance.fr/fr

Météo-France - 73 avenue de Paris, 94165 Saint-Mandé cedex - Contact : contact@meteo.fr

Rédigé par Météo-France avec la contribution des observateurs du réseau nivo-météorologiques. Partenariat : ANMSM (Maires de Stations de Montagne), DSF (Domaines Skiables de France), ADSP (Directeurs de Pistes et de la Sécurité des Stations de Sports d'Hiver) et autres acteurs de la montagne.

Bulletin neige & avalanches par téléphone au
0 892 68 10 20 Service 0,35 € / min + prix appel

Bulletin d'estimation du risque d'avalanche

(valable en dehors des pistes balisées et ouvertes)

MASSIF : Capcir Puymorens

Rédigé le mardi 21 avril 2026 à 16h

Épaisseur de neige hors-piste

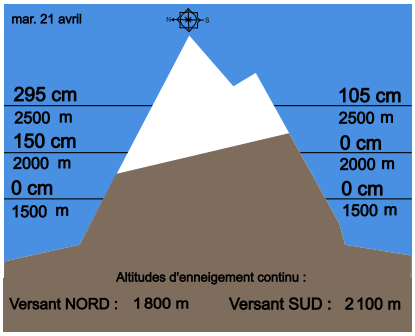

Précipitations à 1800 m

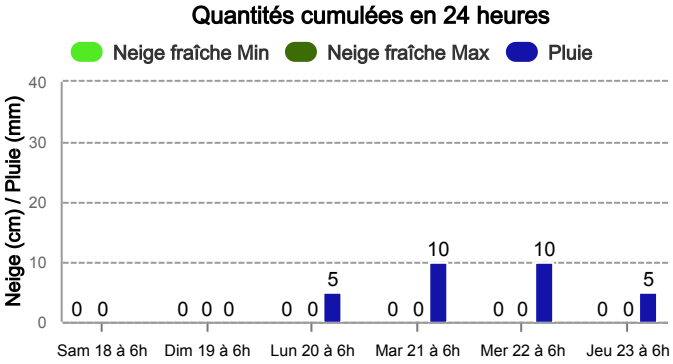

Tendance du jeudi 23 avril

Indice de risque marqué

Maintient d'un risque limité évoluant en risque marqué au fil de la journée.

Pour consulter la vigilance en cours, veuillez vous rendre sur le site https://vigilance.meteofrance.fr/fr

Météo-France - 73 avenue de Paris, 94165 Saint-Mandé cedex - Contact : contact@meteo.fr

Rédigé par Météo-France avec la contribution des observateurs du réseau nivo-météorologiques. Partenariat : ANMSM (Maires de Stations de Montagne), DSF (Domaines Skiables de France), ADSP (Directeurs de Pistes et de la Sécurité des Stations de Sports d'Hiver) et autres acteurs de la montagne.

Bulletin neige & avalanches par téléphone au

0 892 68 10 20 Service 0,35 € / min + prix appel

RÉPUBLIQUE FRANÇAISE
Liberté Égalité Fraternité

METEO FRANCE
À VOS CÔTÉS, DANS UN CLIMAT QUI CHANGE

Bulletin d'estimation du risque d'avalanche

(valable en dehors des pistes balisées et ouvertes)

MASSIF : Capcir Puymorens

Rédigé le mardi 21 avril 2026 à 16h

Conditions nivo-météo des 7 derniers jours

	mer. 15/04				jeu. 16/04				ven. 17/04				sam. 18/04				dim. 19/04				lun. 20/04				mar. 21/04			
	03h	09h	15h	21h	03h	09h	15h	21h	03h	09h	15h	21h	03h	09h	15h	21h	03h	09h	15h	21h	03h	09h	15h	21h	03h	09h	15h	21h
Météo																												
Vent (km/h)	35	25	25	20	20	20	25	20	20	20	15	15	15	15	20	15	20	15	30	15	20	25	35	15	25	20	25	20
à 3000m																												
Vent (km/h)	20	15	15	10	10	10	15	10	10	10	10	10	10	10	15	10	15	15	25	15	20	15	30	15	15	15	25	20
à 2000m																												

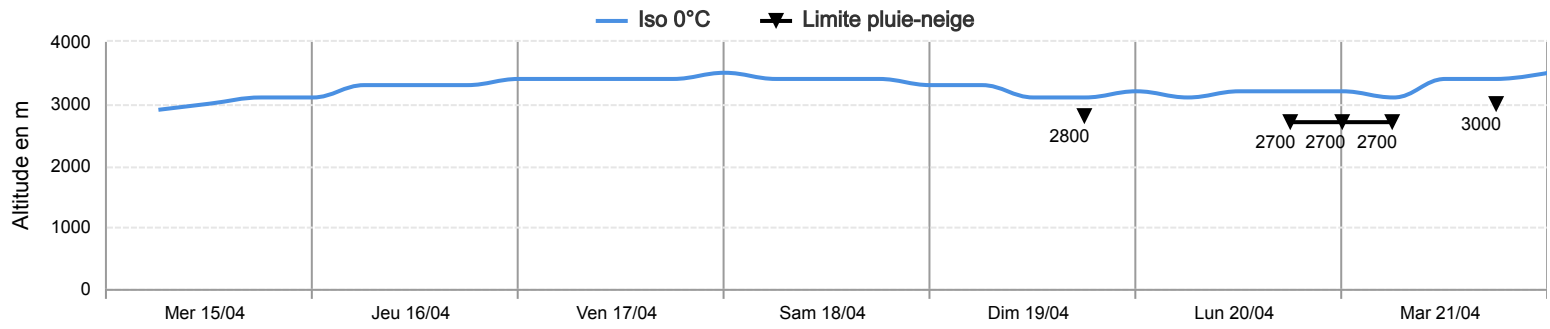

Neige fraîche à 06h

0 cm	0 cm	0 cm	0 cm	0 cm	0 cm

Risque d'avalanche	mer. 15/04	jeu. 16/04	ven. 17/04	sam. 18/04	dim. 19/04	lun. 20/04	mar. 21/04

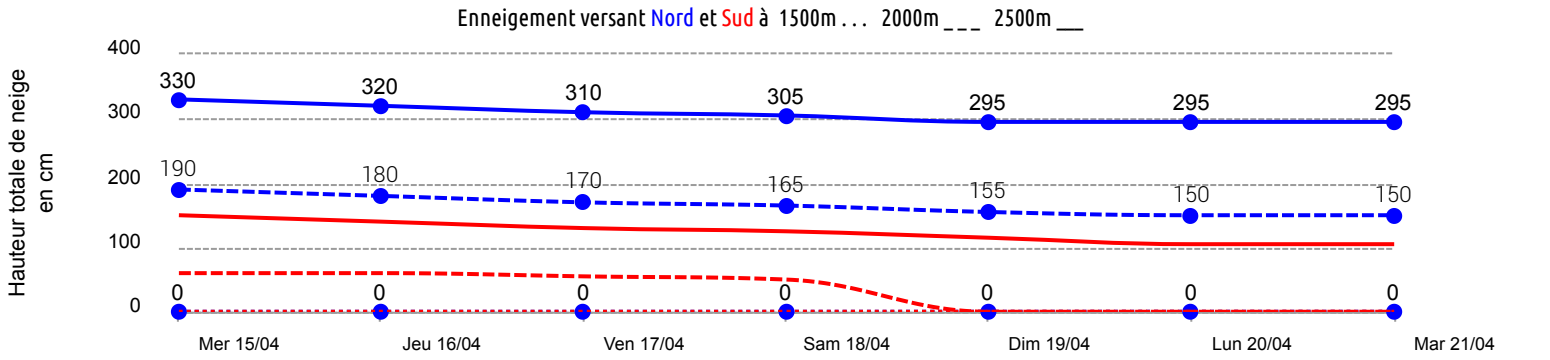

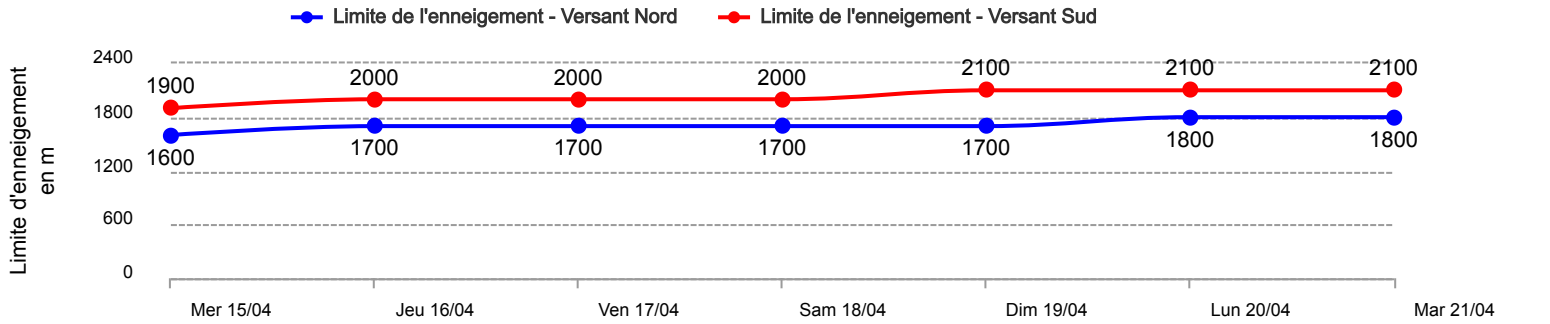

Pour consulter la vigilance en cours, veuillez vous rendre sur le site https://vigilance.meteofrance.fr/fr

Météo-France - 73 avenue de Paris, 94165 Saint-Mandé cedex - Contact : contact@meteo.fr

Bulletin neige & avalanches par téléphone au

0 892 68 10 20 Service 0,35 € / min + prix appel

Rédigé par Météo-France avec la contribution des observateurs du réseau nivo-météorologiques. Partenariat : ANMSM (Maires de Stations de Montagne), DSF (Domaines Skiables de France), ADSP (Directeurs de Pistes et de la Sécurité des Stations de Sports d'Hiver) et autres acteurs de la montagne.