Bulletin d'estimation du risque d'avalanche

(valable en dehors des pistes balisées et ouvertes)

MASSIF : Chartreuse

Rédigé le mardi 21 avril 2026 à 16h

Estimation des risques pour le : MERCREDI 22 AVRIL

NEIGE DENSE, MANTEAU PRINTANIER

1

1

N O E S

Indice de risque faible.

Départs spontanés : Une rare coulée humide ou avalanche de glissement possible.

Déclenchements provoqués : Peu probables, ou juste une coulée ponctuelle sous les skis en neige très humide

Indices de risque : 5 très fort - 4 fort - 3 marqué - 2 limité - 1 faible -- En noir : les pentes les plus dangereuses

Stabilité du manteau neigeux

Situation avalancheuse typique : avalanches de fond — neige humide

Départs spontanés : Peu probables. Neige transformée dense avec un un regel nocturne correct. En journée, le manteau neigeux s'humidifie parfois jusqu'au fond, mais le risque de coulée humide / reptation reste faible, la plupart des pentes ayant déjà purgées. Par ailleurs la présence d'un voile nuageux temporairement bien dense en journée va limiter l'humidification du manteau neigeux par le soleil.

Déclenchements provoqués : Pas de risque de plaque. Manteau neigeux dense et bien stabilisé. En terrain raide et bien humidifié, risque limité de coulée ponctuelle sous les skis.

Qualité de la neige

Qualification de l'enneigement : L'enneigement s'est fortement réduit depuis 2 semaines et devient déficitaire pour la saison. Au Sud il ne reste plus que des névés...

Limites skiables : Vers 1400 à 1900m environ suivant l'exposition, la raideur de la pente...

Qualité de la neige mercredi : Regel correct mercredi matin en altitude. Le dégel sera plus tardif que les jours précédents avec un ciel voilé en journée. Le manteau finit toutefois par s'humidifier en profondeur. En large Sud l'enneigement ressemble de plus en plus à du névé.

Aperçu météo pour le mercredi 22 avril

	nuit	matin	après-midi	soir
Pluie-Neige				
Iso 0 °C	2 800 m	2 800 m	2 700 m	2 700 m
Vent 1500 m	10 km/h	15 km/h	20 km/h	10 km/h
Vent 2000 m	10 km/h	15 km/h	10 km/h	5 km/h

Ciel voilé voire temporairement couvert en milieu de journée.

Épaisseur de neige hors-piste

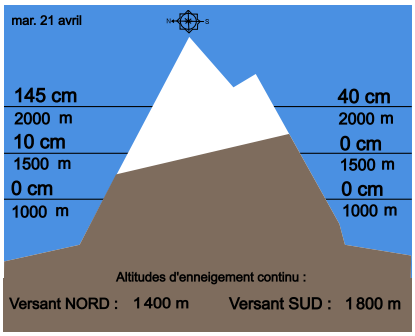

Précipitations à 1800 m

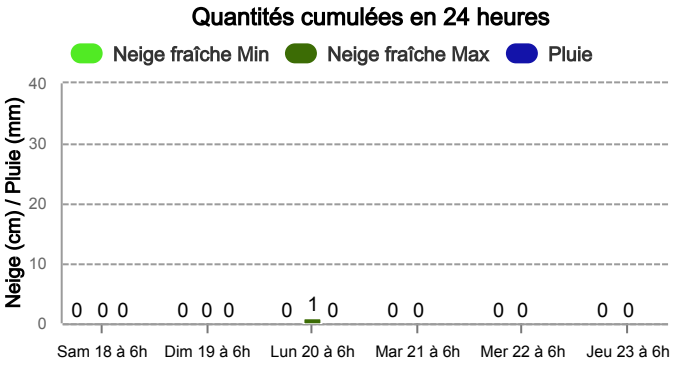

Tendance du jeudi 23 avril

1

Indice de risque faible

Regel nocturne correct, avant une nouvelle journée printanière avec un manteau qui s'humidifie en profondeur en journée. Risque restant faible.

Pour consulter la vigilance en cours, veuillez vous rendre sur le site https://vigilance.meteofrance.fr/fr

Météo-France - 73 avenue de Paris, 94165 Saint-Mandé cedex - Contact : contact@meteo.fr

Rédigé par Météo-France avec la contribution des observateurs du réseau nivo-météorologiques. Partenariat : ANMSM (Maires de Stations de Montagne), DSF (Domaines Skiables de France), ADSP (Directeurs de Pistes et de la Sécurité des Stations de Sports d'Hiver) et autres acteurs de la montagne.

Bulletin neige & avalanches par téléphone au 0 892 68 10 20 Service 0,35 € / min + prix appel

RÉPUBLIQUE FRANÇAISE
Liberté Égalité Fraternité

METEO FRANCE
À VOS CÔTÉS, DANS UN CLIMAT QUI CHANGE

Bulletin d'estimation du risque d'avalanche
(valable en dehors des pistes balisées et ouvertes)
MASSIF : Chartreuse

Rédigé le mardi 21 avril 2026 à 16h

Conditions nivo-météo des 7 derniers jours

	mer. 15/04				jeu. 16/04				ven. 17/04				sam. 18/04				dim. 19/04				lun. 20/04				mar. 21/04			
	03h	09h	15h	21h	03h	09h	15h	21h	03h	09h	15h	21h	03h	09h	15h	21h	03h	09h	15h	21h	03h	09h	15h	21h	03h	09h	15h	21h
Météo																												
Vent (km/h)	25	10	15	10	15	15	10	5	10	10	5	5	5	10	5	5	10	10	25	20	15	10	10	15	10	5	10	10
à 2000m																												
Vent (km/h)	15	5	10	5	5	5	5	15	10	5	5	5	10	10	5	0	10	15	20	10	5	15	20	10	10	15	20	10
à 1500m																												

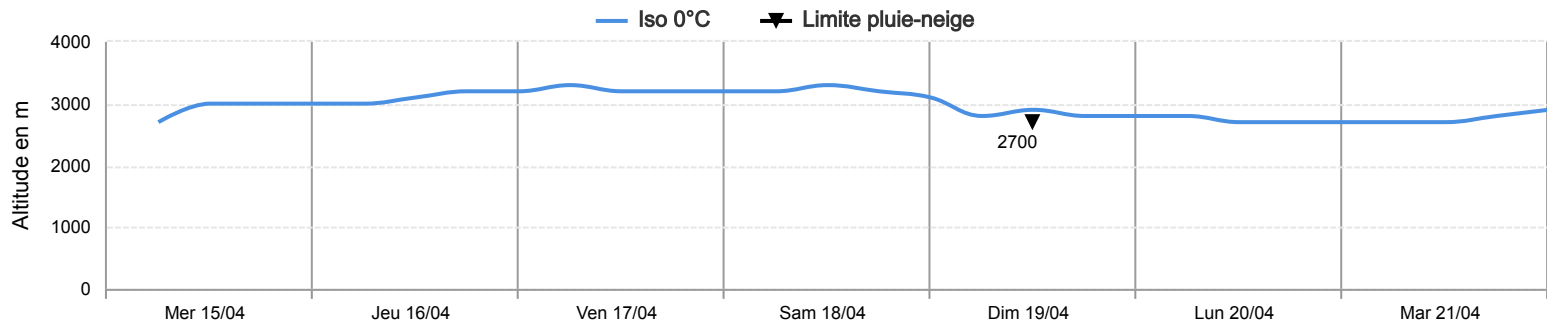

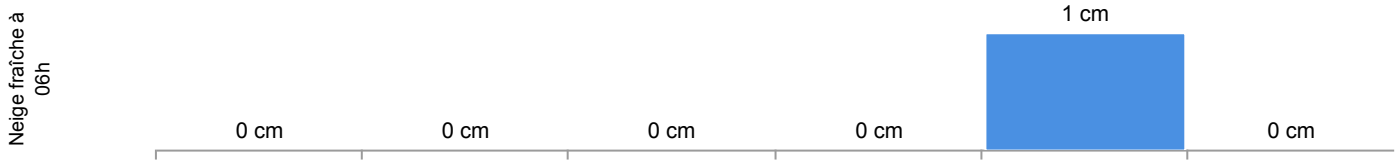

Risque d'avalanche	mer. 15/04	jeu. 16/04	ven. 17/04	sam. 18/04	dim. 19/04	lun. 20/04	mar. 21/04
	2	2	2	2	2	2	2

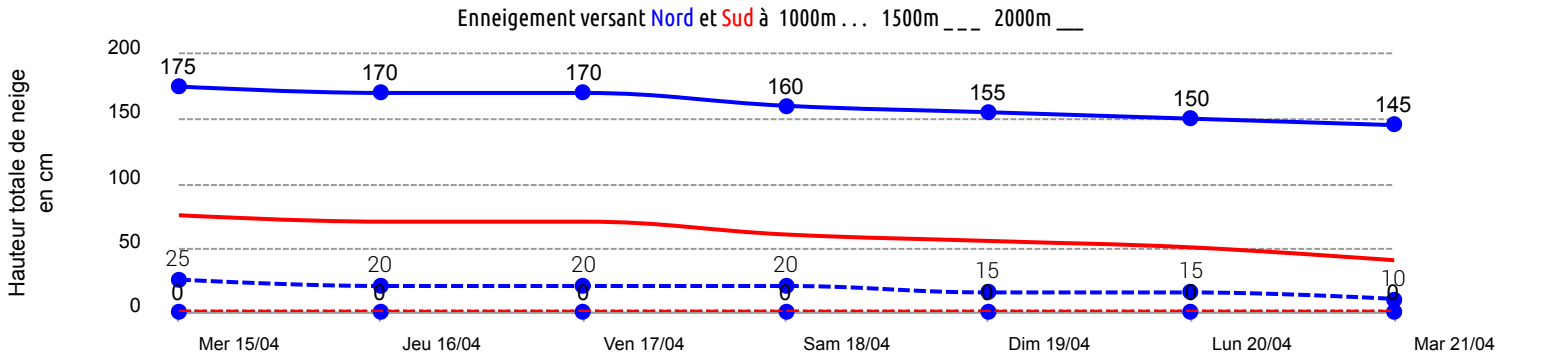

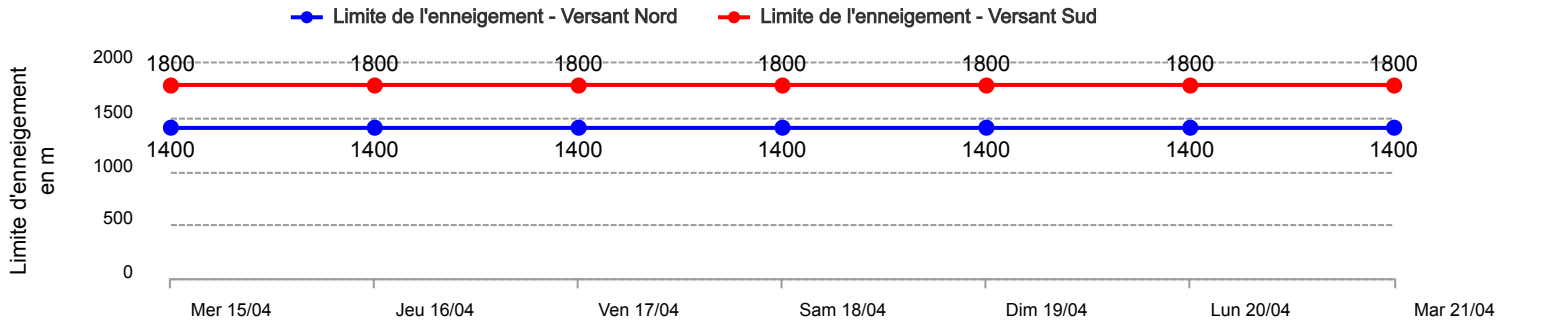

Pour consulter la vigilance en cours, veuillez vous rendre sur le site https://vigilance.meteofrance.fr/fr

Météo-France - 73 avenue de Paris, 94165 Saint-Mandé cedex - Contact : contact@meteo.fr

Rédigé par Météo-France avec la contribution des observateurs du réseau nivo-météorologiques. Partenariat : ANMSM (Maires de Stations de Montagne), DSF (Domaines Skiables de France), ADSP (Directeurs de Pistes et de la Sécurité des Stations de Sports d'Hiver) et autres acteurs de la montagne.

Bulletin neige & avalanches par téléphone au
0 892 68 10 20 Service 0,35 € / min + prix appel